Giovedì 26.02.2026

Pubblicato il 25.02.2026 alle ore 17:00

Mattina

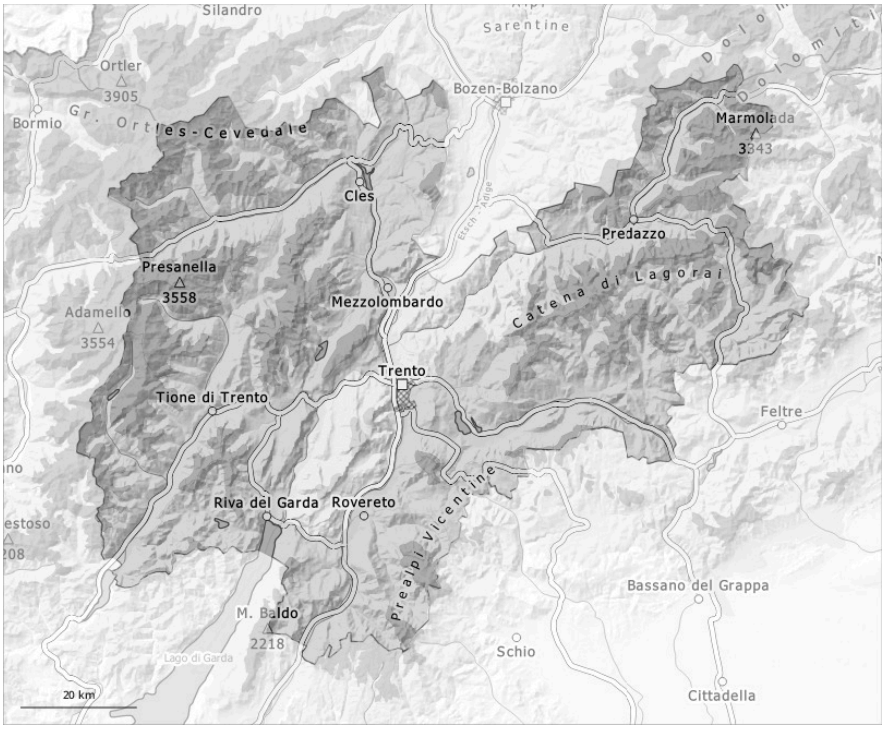

pomeriggio

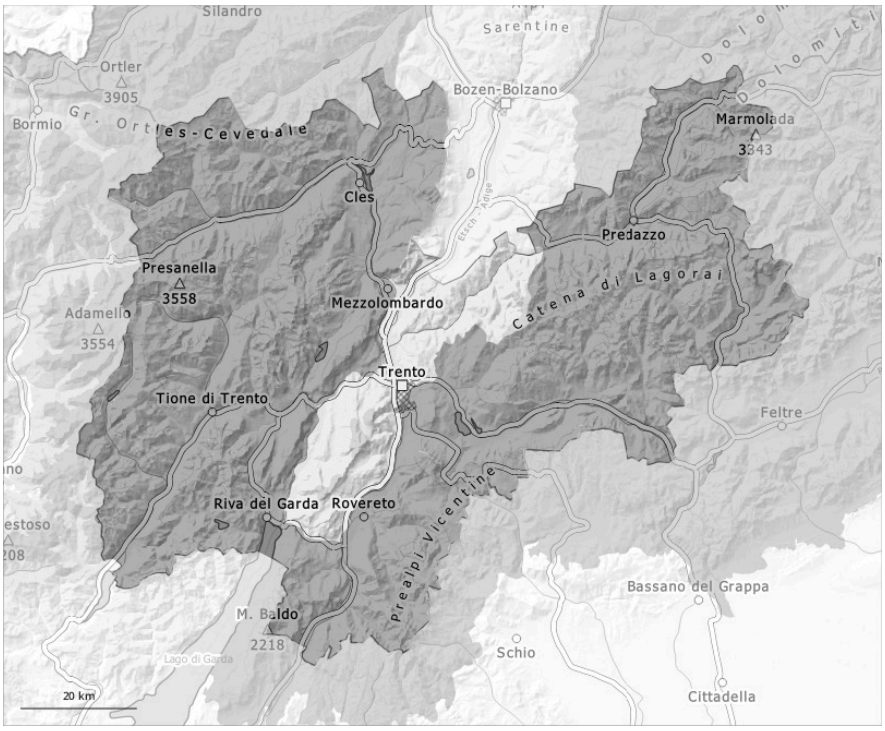

1	2	3	4	5
debole	moderato	marcato	forte	molto forte

Grado di pericolo 3 - Marcato

AM:

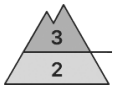

Limite del bosco

Tendenza: pericolo valanghe stabile
per Venerdì il 27.02.2026

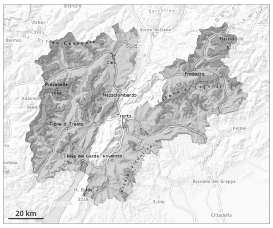

Strati deboli persistenti

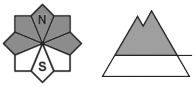

Limite del bosco

Neve bagnata

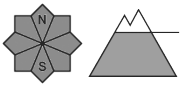

2400m

PM:

Tendenza: pericolo valanghe stabile
per Venerdì il 27.02.2026

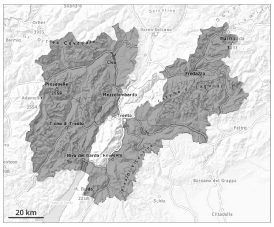

Strati deboli persistenti

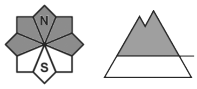

Limite del bosco

Neve bagnata

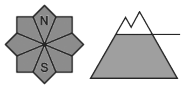

2400m

Attenzione alla neve vecchia con strati deboli persistenti e alle valanghe di slittamento. Soprattutto sui pendii ripidi esposti al sole: Con il rialzo termico, ulteriore aumento del pericolo di valanghe di neve bagnata.

Soprattutto sui pendii molto ripidi si prevedono valanghe spontanee di medie dimensioni. In alcuni punti le valanghe possono trascinare l'intero manto nevoso e raggiungere grandi dimensioni.
Le valanghe di neve asciutta sono per lo più di dimensioni medie e distaccabili da un singolo appassionato di sport invernali. Sono possibili distacchi a distanza. I rumori di "whum" e la formazione di fessure quando si calpesta la coltre di neve sono campanelli di allarme che rimandano a questo pericolo.
I punti pericolosi sono frequenti e difficilmente individuabili anche da parte dell'escursionista esperto. Le escursioni richiedono un'attenta scelta dell'itinerario. Le valanghe possono subire un distacco nella neve vecchia e raggiungere grandi dimensioni a livello isolato. Ciò già da parte di un singolo appassionato di sport invernali. Attenzione soprattutto nelle zone poco frequentate, come pure nelle zone di passaggio da poca a molta neve come p.es. all'ingresso di conche e canaloni. Nella zona di scorrimento le valanghe possono trascinare la neve bagnata. Ciò aumenta la distanza d'arresto delle valanghe.
Gli accumuli di neve ventata meno recenti rimangono ancora instabili soprattutto sui pendii ripidi esposti a ovest, nord ed est al di sopra dei 2400 m circa.

Con il rialzo termico e l'irradiazione solare diurni, sono previste valanghe di neve bagnata. Ciò soprattutto sui pendii soleggiati molto ripidi e alle basi di pareti rocciose.
Fare attenzione alle zone di deposito.

Manto nevoso

Situazione tipo st.1: strato debole persistente basale st.10: situazione primaverile

Nella parte basale del manto di neve vecchia si trovano pronunciati strati fragili. Le condizioni meteorologiche favoriranno un graduale indebolimento del manto nevoso sui pendii soleggiati.
Il manto nevoso rimane instabile in molti punti, soprattutto nelle zone in prossimità delle creste e dei passi a tutte le altitudini, come pure nelle conche, nei canaloni e dietro ai cambi di pendenza in quota.

Tendenza

Il manto nevoso rimane instabile in molti punti. Il pericolo di valanghe rimarrà invariato. L'attività di valanghe di neve bagnata aumenterà progressivamente.

Grado di pericolo 2 - Moderato

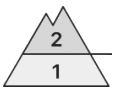

Limite del bosco

Tendenza: pericolo valanghe stabile
per Venerdì il 27.02.2026

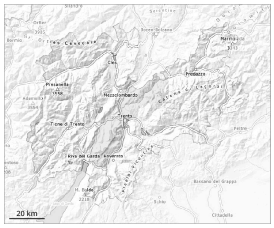

Strati deboli persistenti

Limite del bosco

Neve bagnata

Gli strati deboli presenti nella neve vecchia possono distaccarsi a livello isolato. Il pericolo di valanghe di neve bagnata aumenterà nel corso della giornata.

Le valanghe possono a livello isolato subire un distacco nella neve vecchia e, sui pendii esposti a ovest, nord ed est, raggiungere dimensioni medie. Ciò da parte di un singolo appassionato di sport invernali. Nella zona di scorrimento le valanghe possono trascinare la neve bagnata.

Con il rialzo termico e l'irradiazione solare diurni, sono previste isolate valanghe di neve bagnata di piccole e medie dimensioni.

Manto nevoso

Situazione tipo st.1: strato debole persistente basale | st.10: situazione primaverile

Soprattutto sui pendii esposti a ovest, nord ed est, all'interno del manto di neve vecchia si trovano pronunciati strati fragili.

L'irraggiamento notturno sarà in molte aree buono. Il sole e il calore causeranno nel corso della giornata un rapido impregnamento del manto nevoso.

Tendenza

La neve vecchia con strati deboli persistenti e la neve bagnata richiedono attenzione.