Donnerstag 26.02.2026

Veröffentlicht am 25.02.2026 um 17:00

Vormittag

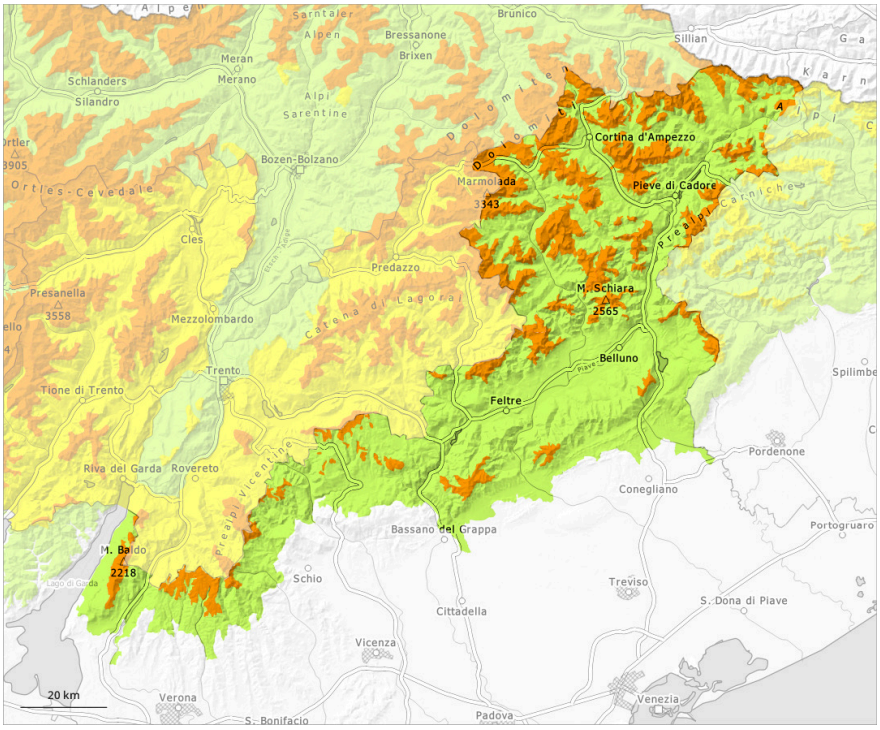

Nachmittag

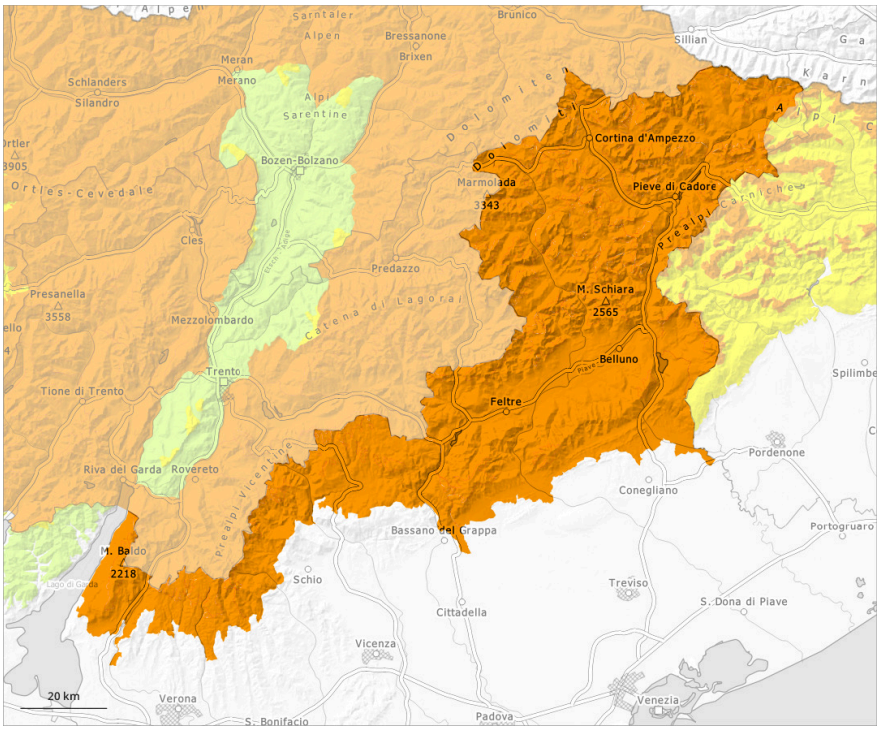

1	2	3	4	5
gering	mäßig	erheblich	groß	sehr groß

Gefahrenstufe 3 - Erheblich

AM:

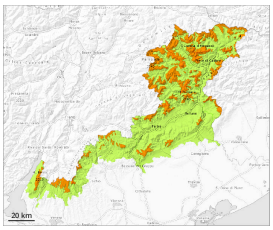

Waldgrenze

Tendenz: Lawinengefahr bleibt gleich
am Freitag, den 27.02.2026

Altschnee

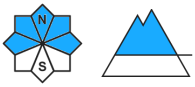

Waldgrenze

Triebschnee

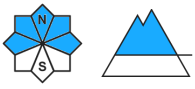

2400m

PM:

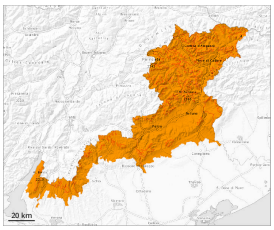

Tendenz: Lawinengefahr bleibt gleich
am Freitag, den 27.02.2026

Nassschnee

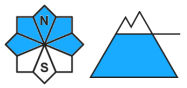

2400m

Altschnee

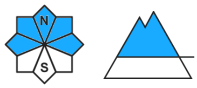

Waldgrenze

Triebschnee

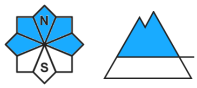

2400m

Vorsicht vor Triebschnee und schwachem Altschnee. Die Gefahr von nassen Lawinen steigt im Tagesverlauf markant an.

Lawinen können im Altschnee ausgelöst werden und vereinzelt groß werden. Dies bereits durch einzelne Wintersportler. Die Gefahrenstellen liegen vor allem an steilen West-, Nord- und Osthängen. Einzelne Gefahrenstellen liegen auch an steilen Sonnenhängen oberhalb von rund 2400 m. Vorsicht vor allem im selten befahrenen Gelände sowie an Übergängen von wenig zu viel Schnee wie z.B. bei der Einfahrt in Rinnen und Mulden. In der Sturzbahn können Lawinen den nassen Schnee mitreißen.
Mit der tageszeitlichen Erwärmung steigt die Gefahr von feuchten und nassen Lawinen im Tagesverlauf rasch an. Dies vor allem an sehr steilen Sonnenhängen und an Felswandfüßen. Die Auslaufbereiche sollten beachtet werden. Touren sollten rechtzeitig beendet werden.
Die nicht mehr ganz frischen Triebschneeansammlungen bleiben vor allem an steilen West-, Nord- und Osthängen oberhalb von rund 2400 m bis auf weiteres störanfällig.

Schneedecke

Gefahrenmuster gm.1: bodennahe schwachschicht gm.10: frühjahrssituation

In der Altschneedecke sind vor allem an steilen Nord-, Ost- und Westhängen Schwachschichten vorhanden. Die nächtliche Abstrahlung ist recht gut. Sonne und Wärme führen im Tagesverlauf vor allem an sehr steilen Sonnenhängen unterhalb von rund 2400 m zu einer raschen Anfeuchtung der Schneedecke.

Tendenz

Steile Schattenhänge hohe Lagen: Vorsicht vor Triebschnee und schwachem Altschnee.
Steile Sonnenhänge mittlere und hohe Lagen: Die Gefahr von nassen Lawinen steigt im Tagesverlauf an.