Donnerstag 26.02.2026

Veröffentlicht am 25.02.2026 um 17:00

Vormittag

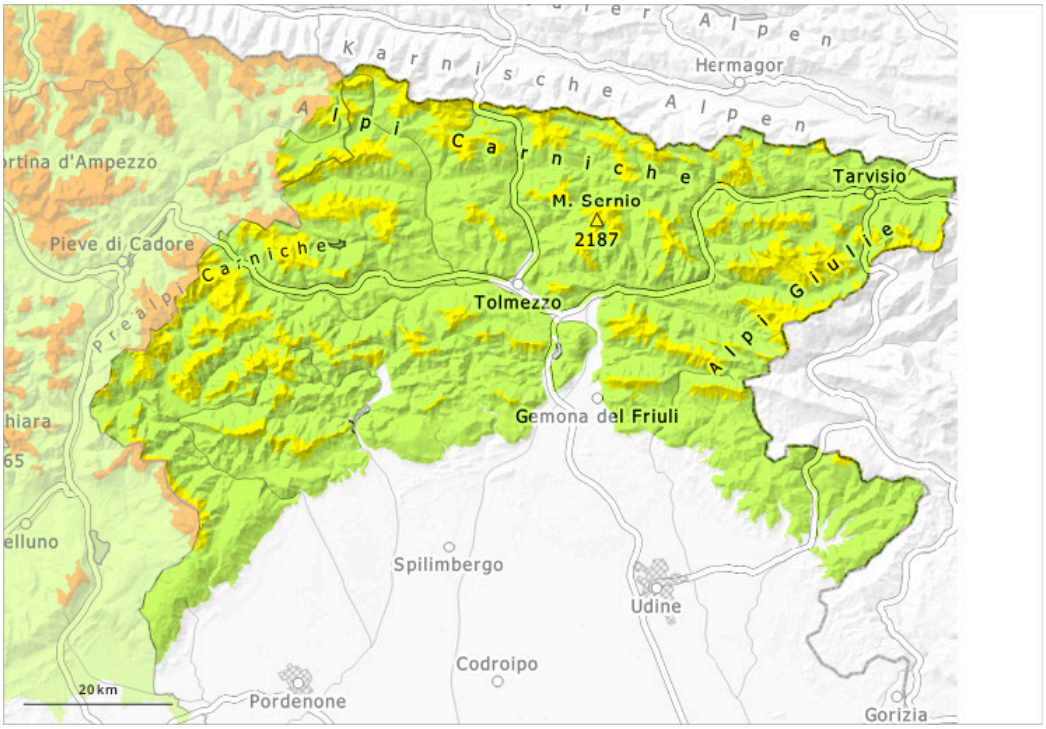

Nachmittag

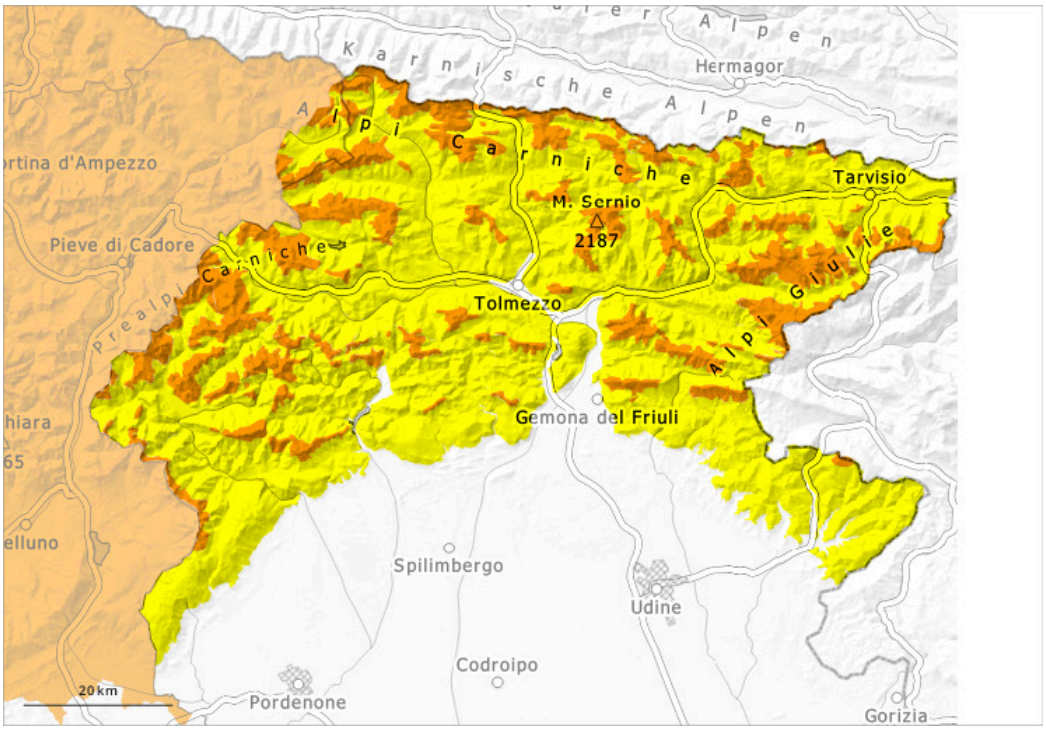

1	2	3	4	5
gering	mäßig	erheblich	groß	sehr groß

Gefahrenstufe 3 - Erheblich

AM:

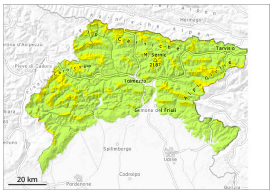

1800m

Tendenz: Lawinengefahr bleibt gleich
am Freitag, den 27.02.2026

Nassschnee

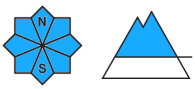

1800m

Altschnee

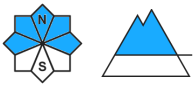

1800m

PM:

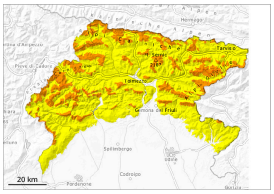

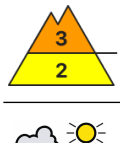

1800m

Tendenz: Lawinengefahr bleibt gleich
am Freitag, den 27.02.2026

Nassschnee

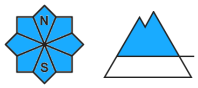

1800m

Nassschnee

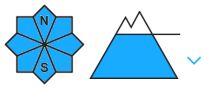

1800m

Mit der tageszeitlichen Erwärmung und der Sonneneinstrahlung nehmen die Gefahrenstellen im Tagesverlauf zu.

The dangerous spots are found on steep slopes, especially grassy ones, as well as in areas near the ridges and at the base of rock walls, also due to the possibility of debris falling from above. Mit der tageszeitlichen Erwärmung und der Sonneneinstrahlung steigt die Auslösebereitschaft von feuchten Lawinen vor allem an Sonnenhängen allmählich an. Zudem sind Gleitschneelawinen zu erwarten. Die Triebschneeansammlungen sind vereinzelt störanfällig. Touren erfordern Erfahrung in der Beurteilung der Lawinengefahr und eine vorsichtige Routenwahl.

Schneedecke

Die Wetterbedingungen führen zu einer raschen Aufweichung der Schneedecke. In der Schneedecke sind vor allem an Schattenhängen Schwachschichten vorhanden.

Tendenz

Es ist meist sonnig. Kontinuierliche Erwärmung.