MINISTERO DELLA DIFESA

meteomont
Servizio Nazionale di previsione neve e valanghe

EAWS EUROPEAN AVALANCHE WARNING SERVICES

CARABINIERI

ALPI OROBICHE

Bollettino Valanghe N. 356/2026 del 25/02/2026 ore 14.00
Validità 48 ore prossima emissione 26/02/2026

A cura del Servizio METEOMONT dell'ARMA dei CARABINIERI
In collaborazione con Servizio Meteorologico dell'Aeronautica militare

SITUAZIONE alle 14:00 del 25/02/2026

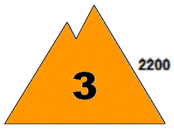

SITUAZIONE TIPO: neve a debole coesione e vento.



SITUAZIONE TIPO: situazione primaverile.

Quota neve (mslm)	Nord	Sud
	1100	1500

Altezza Neve (cm)	Neve al suolo	Neve Fresca	Quota (mslm)
	105	0	1767
	70	0	1635

VALANGHE OSSERVATE: Alcune valanghe di medie dimensioni, Valanghe di slittamento.

PREVISIONI 26/02/2026

GRADO DI PERICOLO: MARCATO 3

SITUAZIONE TIPO: neve a debole coesione e vento.

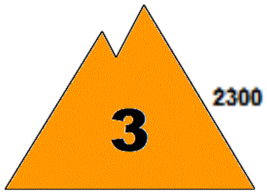



SITUAZIONE TIPO: situazione primaverile.

MANTO NEVOSO: La stabilità del manto nevoso è scarsa su alcuni punti (aree) per versanti da ovest a est al di sopra di 2300 mslm, possibili valanghe di dimensioni grandi.
La stabilità del manto nevoso è scarsa su molti punti (aree) per versanti al sole al di sotto di 2300 mslm, possibili valanghe di dimensioni medie.

AVVERTENZE

Il rialzo termico diurno richiede un'attenta valutazione temporale dell'escursione che eviti l'attraversamento di pendii ripidi nelle ore più calde della giornata.

SCALA EUROPEA DEL GRADO DI PERICOLO VALANGHE

LEGENDA PROBLEMA

Bollettino realizzato su scala sinottica-regionale (standard EAWS). La sua valutazione non può escludere in alcun modo la necessità di una seria e capace valutazione locale del pericolo (singolo pendio) che può essere anche sensibilmente diverso. Le previsioni meteorologiche sono relative all'orario UTC (per l'Italia +1 in inverno e +2 in estate).

MINISTERO DELLA DIFESA

meteomont
Servizio Nazionale di previsione neve e valanghe

EAWS EUROPEAN AVALANCHE WARNING SERVICES

CARABINIERI

ALPI OROBICHE

PREVISIONE METEO

Quota		26/02/2026 h6:00	26/02/2026 h12:00	26/02/2026 h18:00
1000	Venti	00 Calma	01 Nodi da Est	03 Nodi da Nord
	Temperature	+07 °C	+07 °C	+03 °C
	Temp.percepita	7 °C	7 °C	2 °C
2000	Venti	00 Calma	00 Calma	02 Nodi da Nord
	Temperature	+06 °C	+07 °C	+07 °C
	Temp.percepita	6 °C	7 °C	7 °C
3000	Venti	03 nodi da Ovest	02 nodi da N-Ovest	01 Nodi da Nord
	Temperature	+01 °C	+01 °C	+01 °C
	Temp.percepita	-1 °C	1 °C	1 °C
Zero termico		2800-3000 m.	3100-3300 m.	3100-3300 m.
Fenomeno		—	—	—
Stato del cielo				

LEGENDA FENOMENI

— Assenza Fenomeni · Nebbia · Foschia · Pioggia debole · Pioggia moderata · Pioggia forte · Temporali

Nevicata debole · Nevicata moderata · Nevicata forte

STATO DEL CIELO

Sereno · Poco nuvoloso · Nuvoloso · Molto nuvoloso · Coperto

Parametri meteonivometrici registrati presso i campi di rilevamento il 25/02/2026.

Località	Comune	Quota (m.s.l.m.)	Altezza neve (cm)	Neve caduta nelle 24 ore (cm)	Temp. Min (°C)	Temp. Max (°C)	Condizioni del tempo
CIMA VALZELLI	Castione della Presolana (BG)	1622	52	0	N.P.	N.P.	Assenza di precipitazioni
VODALA	Gromo (BG)	1635	70	0	+2	+10	Assenza di precipitazioni
QUARTA BAITA	Foppolo (BG)	1760	64	0	-2	+10	Assenza di precipitazioni
MALGA BARBAROSSA *	Vilminore di Scalve (BG)	1767	105	0	N.P.	N.P.	Assenza di precipitazioni
PIZZO DI PETTO *	Vilminore di Scalve (BG)	1827	130	0	N.P.	N.P.	Assenza di precipitazioni
PASSO DI CARONELLA *	Teglio (SO)	2691	160	0	N.P.	N.P.	Assenza di precipitazioni

(*) Rilievi fuori campo

L'INFORMAZIONE E' PREVENZIONE - LEGGI L'ATTUALE GRADO DI PERICOLO VALANGHE!

IL CAPO DEL CENTRO NAZIONALE METEOMONT
(Ten. Col. RFI Emanuela Gini)
FIRMA AUTOGRAFA OMESSA AI SENSI
DELL'ART.3 DEL D.LGS N.39/1993

Bollettino realizzato su scala sinottica-regionale (standard EAWS). La sua valutazione non può escludere in alcun modo la necessità di una seria e capace valutazione locale del pericolo (singolo pendio) che può essere anche sensibilmente diverso. Le previsioni meteorologiche sono relative all'orario UTC (per l'Italia +1 in inverno e +2 in estate).