# Bulletin d'estimation du risque d'avalanche

(valable en dehors des pistes balisées et ouvertes)

# MASSIF : Aravis

Rédigé le mercredi 25 février 2026 à 15h

## Estimation des risques pour le : JEUDI 26 FÉVRIER

**MANTEAU NEIGEUX RÉACTIF SOUS L'EFFET DE LA DOUCEUR PERSISTANTE**

3

2→3

N O E S

Indice de risque limité évoluant en marqué.

**Départs spontanés :** avalanches de neige humide et plaques de fond

**Déclenchements provoqués :** coulée humides + rares anciennes plaques peu réactives mais épaisses

Indices de risque : 5 très fort - 4 fort - 3 marqué - 2 limité - 1 faible -- En noir : les pentes les plus dangereuses

## Stabilité du manteau neigeux

**Situation avalancheuse typique :** neige humide — avalanches de fond

**Départs spontanés :**

* **avalanches de neige humide**, dès la fin de matinée, toutes orientations surtout adrets, en suivant la course du soleil. La plupart en forme de poire, mais localement pouvant s'élargir et entraîner une plaque en contrebas. Taille 2 (moyenne), voire 3 (grande) en cas de grande pente qui n'aurait pas encore purgé. Ces avalanches partent spontanément au réchauffement, mais aussi au passage d'un skieur. *Observables :* escargots, départs souvent près des rochers/falaises réchauffés, enfoncement piéton pour estimer le volume mobilisable.
* **plaques de fond**. Surtout l'après-midi, mais possibles à n'importe quelle heure. Sur terrains raides et lisses en herbes, vires, dalles rocheuses. Versants S : en dessous de 2300/2400 m. Versants N : en dessous de 2000 m. Taille 2 voire 3.

**Déclenchements provoqués :**

* **plaques dures sur couche fragile persistante enfouie**. Versants W/N/E, au-dessus de 2000/2200 m. Peu probables, car cette ancienne couche fragile est généralement bien enfouie et hors d'atteinte par un skieur. MAIS une première petite plaque de surface pourrait en déclencher une nettement plus épaisse (60cm/1m). Observables : aucun, sauf tests d'instabilité. Se méfier des ubacs raides qui étaient peu enneigés avant les dernières perturbations.

**Autres :**

* **Chutes de corniches**, épaisses et volumineuses, pouvant entraîner une plaque en contrebas.

## Qualité de la neige

Enneigement : bon pour une fin février, à toutes altitudes. On peut chausser les skis vers 1200/1300 m. Épaisseur du manteau neigeux hétérogène : fort tassement sous l'effet de la douceur, accumulations, crêtes érodées par les forts vents pendant et après les perturbations (de SW puis NW). Grosses corniches.

Qualité de la neige jeudi :

* sous 2000/2300 m : neige très dense, croûte cassante le matin, s'humidifiant rapidement. Tendance à l'humidification en profondeur.
* au-dessus de 2200/2400 m : variable, neige dense, encore assez froide voire poudreuse plein N. Humidification superficielle en adrets. Cartonnée dans les secteurs qui ont été exposés aux vents de W/NW/N.

## Aperçu météo pour le jeudi 26 février

| | nuit | matin | après-midi | soir |
|---|---|---|---|---|
| Soleil et grande douceur. +9 DG à 2000 m. | | | | |
| **Pluie-Neige** | | | | |
| **Iso 0 °C** | 3 000 m | 3 000 m | 3 000 m | 3 000 m |
| **Vent 2000 m** | ↑ 5 km/h | ↑ 5 km/h | ↑ 10 km/h | ↑ 10 km/h |
| **Vent 2500 m** | ↑ 10 km/h | ↑ 10 km/h | ↗ 15 km/h | ↗ 15 km/h |

## Épaisseur de neige hors-piste

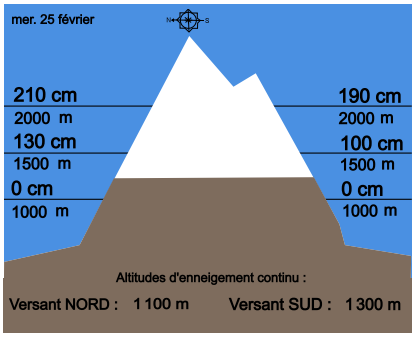


## Précipitations à 1800 m

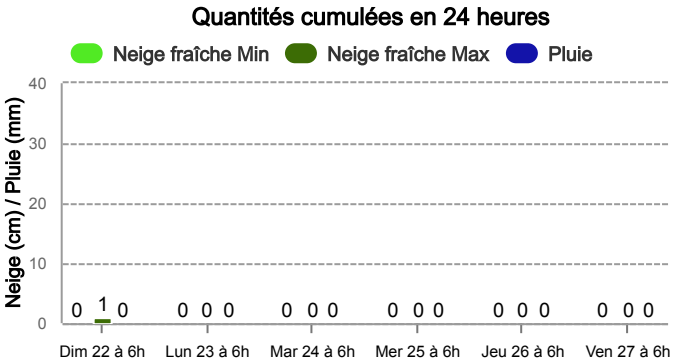


## Tendance du vendredi 27 février

3

**Indice de risque marqué**

Encore de l'activité en neige humide et avalanches de fond. Risque stationnaire.

Pour consulter la vigilance en cours, veuillez vous rendre sur le site https://vigilance.meteofrance.fr/fr


Météo-France - 73 avenue de Paris, 94165 Saint-Mandé cedex - Contact : contact@meteo.fr



Rédigé par Météo-France avec la contribution des observateurs du réseau nivo-météorologiques. Partenariat : ANMSM (Maires de Stations de Montagne), DSF (Domaines Skiables de France), ADSP (Directeurs de Pistes et de la Sécurité des Stations de Sports d'Hiver) et autres acteurs de la montagne.


Bulletin neige & avalanches par téléphone au 0 892 68 10 20 Service 0,35 € / min + prix appel

RÉPUBLIQUE FRANÇAISE
*Liberté Égalité Fraternité*

METEO FRANCE
À VOS CÔTÉS, DANS UN CLIMAT QUI CHANGE

# Bulletin d'estimation du risque d'avalanche

## (valable en dehors des pistes balisées et ouvertes)

# MASSIF : Aravis

Rédigé le mercredi 25 février 2026 à 15h

## Conditions nivo-météo des 7 derniers jours

| | jeu. 19/02 | | | | ven. 20/02 | | | | sam. 21/02 | | | | dim. 22/02 | | | | lun. 23/02 | | | | mar. 24/02 | | | | mer. 25/02 | | | |
|---|---|---|---|---|---|---|---|---|---|---|---|---|---|---|---|---|---|---|---|---|---|---|---|---|---|---|---|---|
| | 03h | 09h | 15h | 21h | 03h | 09h | 15h | 21h | 03h | 09h | 15h | 21h | 03h | 09h | 15h | 21h | 03h | 09h | 15h | 21h | 03h | 09h | 15h | 21h | 03h | 09h | 15h | 21h |
| Météo | | | | | | | | | | | | | | | | | | | | | | | | | | | | |
| Vent (km/h) | 50 | 50 | 40 | 40 | 50 | 35 | 30 | 35 | 35 | 35 | 35 | 45 | 40 | 35 | 40 | 30 | 30 | 20 | 20 | 25 | 25 | 25 | 15 | 15 | 15 | 15 | 20 | 20 |
| à 2500m | | | | | | | | | | | | | | | | | | | | | | | | | | | | |
| Vent (km/h) | 35 | 35 | 25 | 30 | 35 | 25 | 20 | 20 | 20 | 20 | 20 | 20 | 20 | 20 | 25 | 20 | 20 | 10 | 15 | 15 | 15 | 15 | 10 | 10 | 10 | 10 | 10 | 10 |
| à 2000m | | | | | | | | | | | | | | | | | | | | | | | | | | | | |

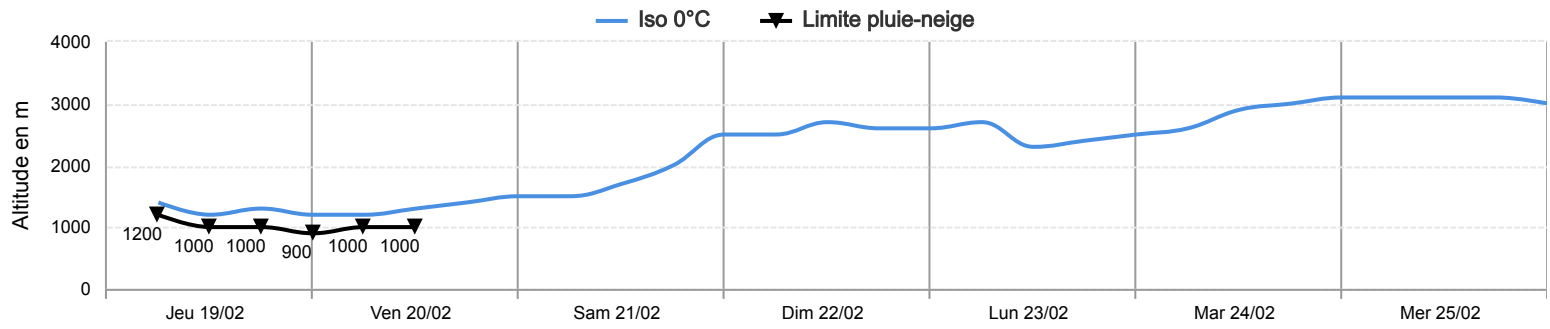


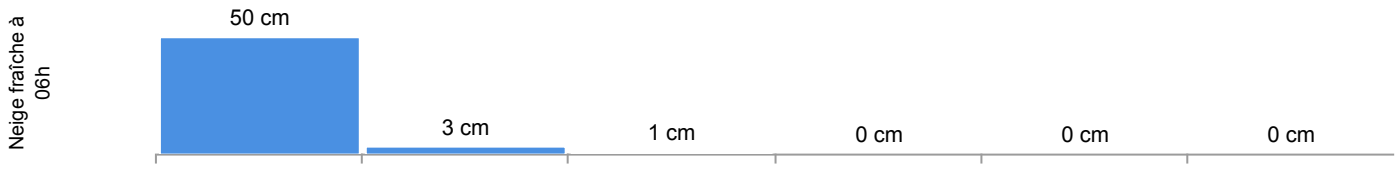


| Risque d'avalanche | jeu. 19/02 | ven. 20/02 | sam. 21/02 | dim. 22/02 | lun. 23/02 | mar. 24/02 | mer. 25/02 |
|---|---|---|---|---|---|---|---|
| | 5 | 4 | 4 | 3 | 2 | 3 | 3 |

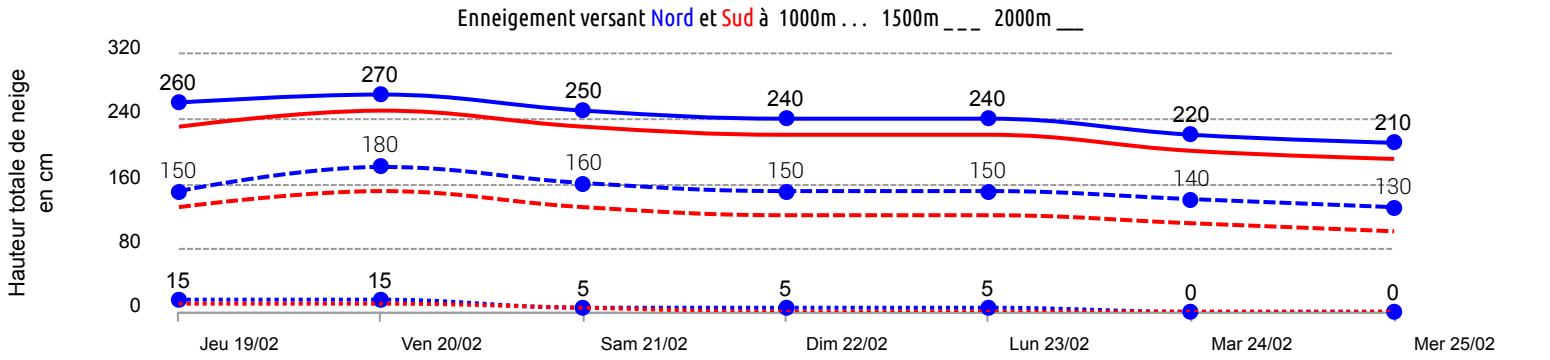


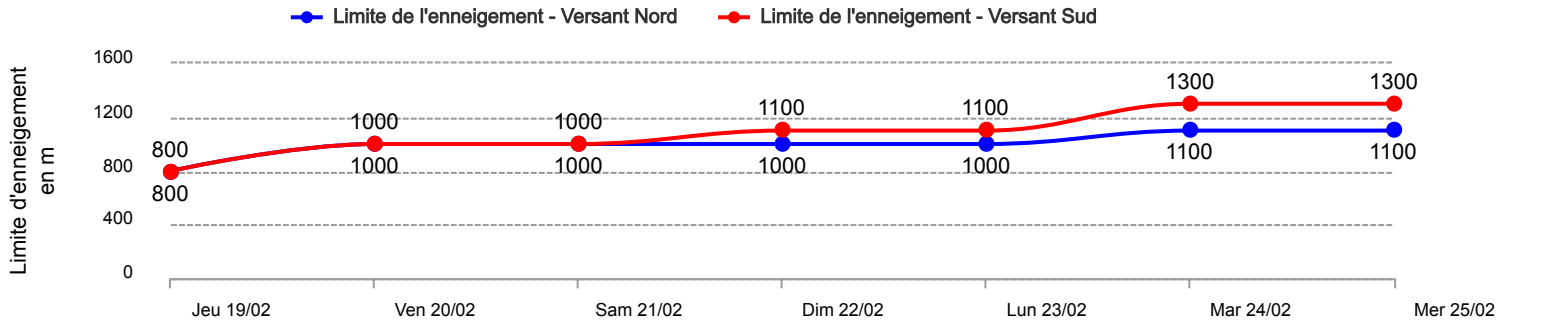


Pour consulter la vigilance en cours, veuillez vous rendre sur le site https://vigilance.meteofrance.fr/fr


Météo-France - 73 avenue de Paris, 94165 Saint-Mandé cedex - Contact : contact@meteo.fr


Bulletin neige & avalanches par téléphone au **0 892 68 10 20** Service 0,35 € / min + prix appel


Rédigé par Météo-France avec la contribution des observateurs du réseau nivo-météorologiques. Partenariat : ANMSM (Maires de Stations de Montagne), DSF (Domaines Skiables de France), ADSP (Directeurs de Pistes et de la Sécurité des Stations de Sports d'Hiver) et autres acteurs de la montagne.