Bulletin d'estimation du risque d'avalanche
(valable en dehors des pistes balisées et ouvertes)

MASSIF : Mont-Blanc

Rédigé le mercredi 25 février 2026 à 15h

Estimation des risques pour le : JEUDI 26 FÉVRIER

MANTEAU NEIGEUX RÉACTIF SOUS L'EFFET DE LA DOUCEUR PERSISTANTE

3

2 → 3

N O E S

Indice de risque limité évoluant en marqué.

Départs spontanés : avalanches de neige humide et plaques de fond

Déclenchements provoqués : coulée humides + anciennes plaques peu réactives mais épaisses

Indices de risque : 5 très fort - 4 fort - 3 marqué - 2 limité - 1 faible -- En noir : les pentes les plus dangereuses

Stabilité du manteau neigeux

Situation avalancheuse typique : neige humide — avalanches de fond

Départs spontanés :
* **avalanches de neige humide**, dès la fin de matinée, en suivant la course du soleil. Versants S raides : toutes altitudes. Versant N : sous 2200 m. La plupart en forme de poire, mais pouvant s'élargir nettement jusqu'à entraîner une plaque en contrebas. Taille 2 (moyenne), voire 3 (grande) en cas de grande pente pas encore purgée. Ces avalanches partent spontanément au réchauffement, mais aussi au passage d'un skieur. *Observables :* escargots, départs souvent près des rochers/falaises réchauffés.
* **plaques de fond**. Surtout l'après-midi, mais possibles à n'importe quelle heure. Sur terrains raides et lisses en herbes ou dalles rocheuses. Versants S : en dessous de 2200/2400 m. Versants N : en dessous de 2000 m. Taille 2 voire 3.
* **chutes de corniches**, épaisses et volumineuses, pouvant entraîner une plaque en contrebas.

Déclenchements provoqués :
* rares **plaques à vent**. Formées lundi-mardi par le fort vent de N/NE, plus haut que 3000 m. Taille 1 à 2.
* **plaques dures sur couche fragile persistante enfouie**. Versants W/N/E, au-dessus de 2000/2200 m. Peu probables, car cette ancienne couche fragile est généralement bien enfouie et hors d'atteinte par un skieur. MAIS une première plaque de surface peut en déclencher une autre plus épaisse (80/150 cm). Taille 2 à 3. Observables : aucun, sauf tests d'instabilité. Se méfier des pentes raides qui étaient peu enneigées et peu fréquentées avant les dernières chutes.

Qualité de la neige

Enneigement : bon pour une fin février, à toutes altitudes. On peut chausser les skis vers 1200 m. Épaisseur du manteau neigeux hétérogène : fort tassement sous l'effet de la douceur, grosses corniches et accumulations, crêtes érodées par les forts vents pendant et après les perturbations (de SW puis NW/N).

Qualité de la neige jeudi :
* sous 2000/2300 m : neige très dense, croûtée le matin, s'humidifiant rapidement. Tendance à l'humidification en profondeur.
* au-dessus de 2200/2400 m : variable, neige dense, encore assez froide voire poudreuse plein N. Humidification superficielle en adrets. Portante à cartonnée dans les secteurs qui ont été exposés aux vents de W/NW/N.

Aperçu météo pour le jeudi 26 février

nuit	matin	après-midi	soir

Soleil et grande douceur. +9 DG à 2000 m, -2 à l'Aiguille du Midi.

Pluie-Neige				
Iso 0 °C	3 100 m	3 100 m	3 100 m	3 100 m
Vent 2000 m	↑ 10 km/h	↑ 10 km/h	↗ 10 km/h	↑ 10 km/h
Vent 4000 m	↗ 20 km/h	↗ 20 km/h	↗ 30 km/h	↗ 30 km/h

Épaisseur de neige hors-piste

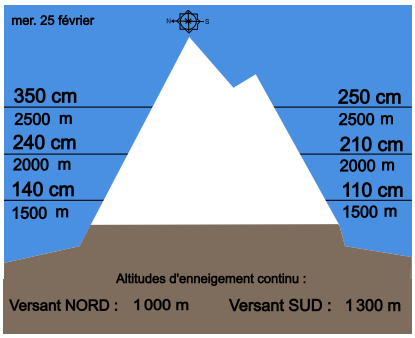

Précipitations à 1800 m

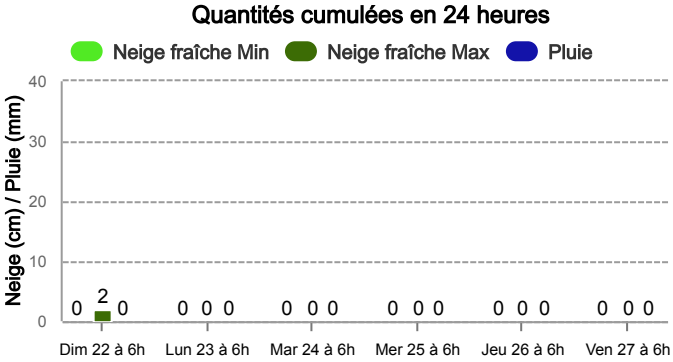

Tendance du vendredi 27 février

3

Indice de risque marqué

Encore de l'activité en neige humide et avalanches de fond. Risque stationnaire.

Pour consulter la vigilance en cours, veuillez vous rendre sur le site https://vigilance.meteofrance.fr/fr

Météo-France - 73 avenue de Paris, 94165 Saint-Mandé cedex - Contact : contact@meteo.fr

Rédigé par Météo-France avec la contribution des observateurs du réseau nivo-météorologiques. Partenariat : ANMSM (Maires de Stations de Montagne), DSF (Domaines Skiables de France), ADSP (Directeurs de Pistes et de la Sécurité des Stations de Sports d'Hiver) et autres acteurs de la montagne.

Bulletin neige & avalanches par téléphone au 0 892 68 10 20 Service 0,35 € / min + prix appel

RÉPUBLIQUE FRANÇAISE
Liberté Égalité Fraternité

METEO FRANCE
À VOS CÔTÉS, DANS UN CLIMAT QUI CHANGE

Bulletin d'estimation du risque d'avalanche

(valable en dehors des pistes balisées et ouvertes)

MASSIF : Mont-Blanc

Rédigé le mercredi 25 février 2026 à 15h

Conditions nivo-météo des 7 derniers jours

	jeu. 19/02				ven. 20/02				sam. 21/02				dim. 22/02				lun. 23/02				mar. 24/02				mer. 25/02			
	03h	09h	15h	21h	03h	09h	15h	21h	03h	09h	15h	21h	03h	09h	15h	21h	03h	09h	15h	21h	03h	09h	15h	21h	03h	09h	15h	21h
Météo																												
Vent (km/h)	60	60	80	80	90	80	80	85	70	80	100	100	75	60	60	65	60	60	60	70	70	60	40	30	20	20	20	20
à 4000m	↗	→	↘	↘	↓	↓	↘	↘	↘	↘	↘	↘	↘	→	↘	↘	↘	↘	↘	↓	↓	↓	↓	↓	↓	↑	↑	↑
Vent (km/h)	25	25	25	30	20	20	20	20	20	25	30	30	20	20	20	20	25	25	25	20	10	10	10	10	10	10	10	10
à 2000m	↗	↗	↗	→	↘	↘	↓	↓	↗	↗	↗	↗	↗	↗	↗	↗	↗	↗	↗	↓	↗	↙	↙	←	↑	↑	↑	↑

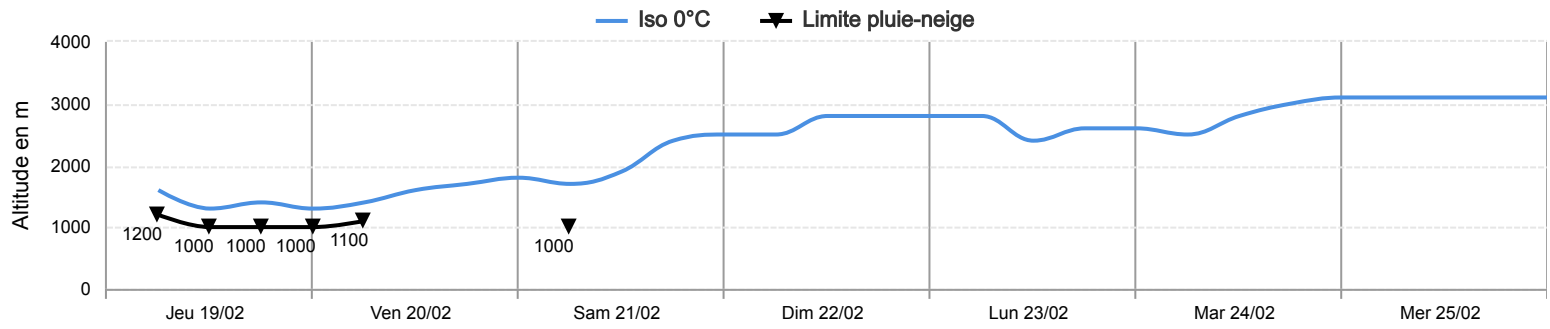

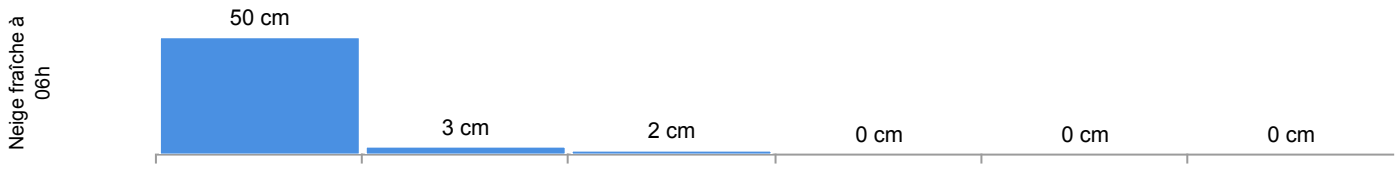

Risque d'avalanche	jeu. 19/02	ven. 20/02	sam. 21/02	dim. 22/02	lun. 23/02	mar. 24/02	mer. 25/02
	5	4	4	3	3	3	3

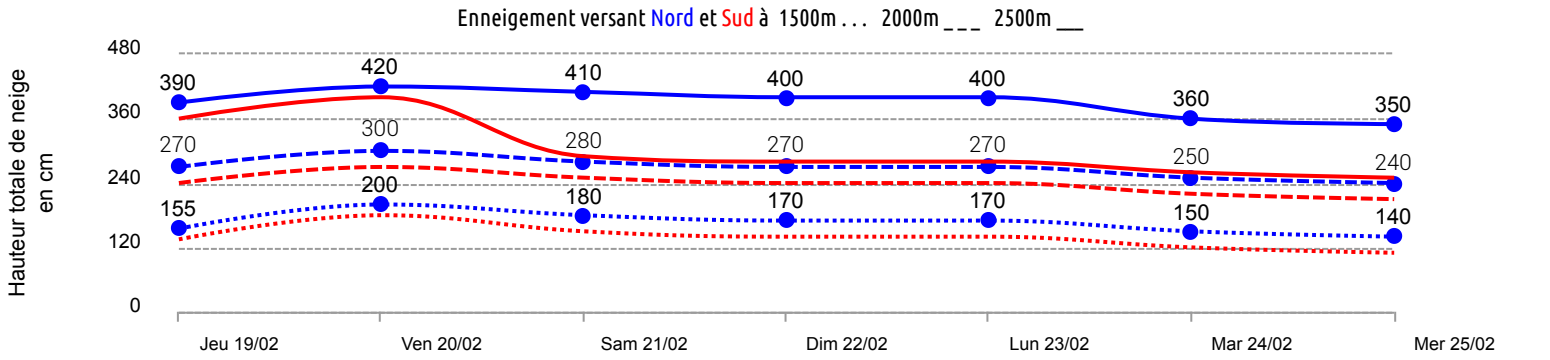

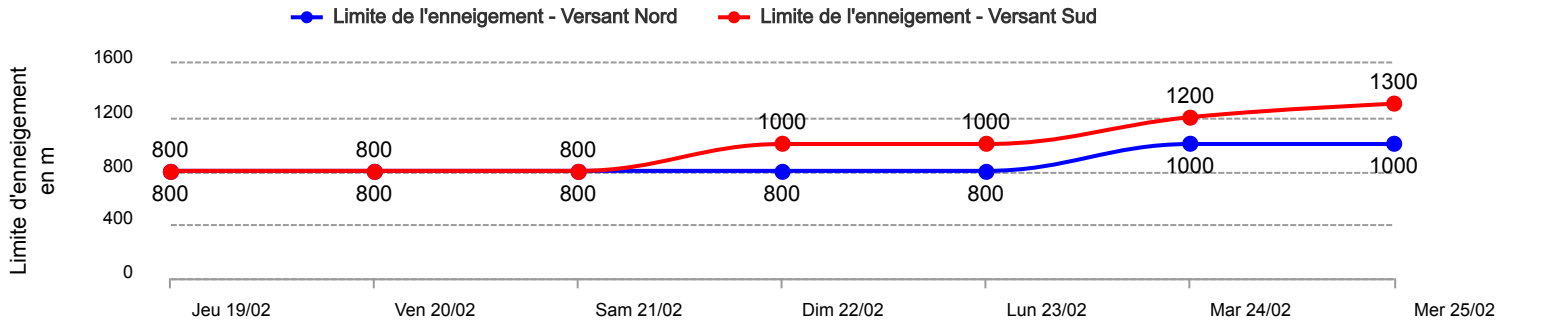

Pour consulter la vigilance en cours, veuillez vous rendre sur le site https://vigilance.meteofrance.fr/fr

Météo-France - 73 avenue de Paris, 94165 Saint-Mandé cedex - Contact : contact@meteo.fr

Rédigé par Météo-France avec la contribution des observateurs du réseau nivo-météorologiques. Partenariat : ANMSM (Maires de Stations de Montagne), DSF (Domaines Skiables de France), ADSP (Directeurs de Pistes et de la Sécurité des Stations de Sports d'Hiver) et autres acteurs de la montagne.

Bulletin neige & avalanches par téléphone au

0 892 68 10 20 Service 0,35 € / min + prix appel