Bulletin d'estimation du risque d'avalanche

(valable en dehors des pistes balisées et ouvertes)

MASSIF : Pays-Basque

Rédigé le mercredi 25 février 2026 à 15h

Estimation des risques pour le : JEUDI 26 FÉVRIER

MANTEAU NEIGEUX PRINTANIER

1

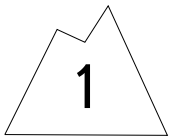

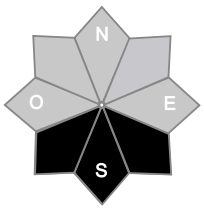

Indice de risque faible.

Départs spontanés : Petite activié en neige humide dans les pentes raides trés ensoleillées.

Déclenchements provoqués : Peu probable.

Indices de risque : 5 très fort - 4 fort - 3 marqué - 2 limité - 1 faible -- En noir : les pentes les plus dangereuses

Stabilité du manteau neigeux

Situation avalancheuse typique : avalanches de fond neige humide

Départs spontanés : en **neige humide dans les pentes raides au soleil**. **Ponctuels** en général, souvent **près des rochers.**
Coulées ou boulettes en matinée dans les pentes Est à Sud, avalanches de taille **très localement moyenne en pentes Sud à Sud-Ouest l'après-midi**.
Une **avalanche de fond** jusqu'au sol reste également possible **dans les pentes Sud-Ouest** en partant d'une accumulation encore en place sur le haut du massif.

Déclenchements provoqués : **peu probables**. Une **rare plaque peu épaisse** peut encore être en place dans les **pentes nord raides au plus haut du massif**, mais désormais **difficile à déclencher**.
Dans les **versants raides au soleil**, **un skieur ou randonneur** peut **aisément déclencher** à son passage une **coulée ou petite avalanche de neige humide et lourde**.
Observables : en pentes nord raides voyant peu le soleil, neige encore sèche très travaillée par le vent au plus haut du massif, fissures sous les skis.

Autres : **très bon regel nocturne** du manteau neigeux humidifié dans la journée de mardi, **propice aux glissades** dans **tous les secteurs en début de journée**, souvent **persistant dans les pentes raides à l'ombre sur le haut du massif**.

Qualité de la neige

Enneigement : très bon pour la saison au regard de ces derniers hivers. Avec le beau temps, fonte très limitée à l'ombre au-delà de 1500m, plus prononcée dans les versants d'un large secteur sud. Le manteau neigeux s'amincit très doucement dans les pentes bien ensoleillées.
Limites skiables : à partir de 1300 à 1500 m au petit matin suivant les versants.
État de la neige : crêtes, cols et sommets pelés et en neige dure en expositions ouest, en neige déjà bien humidifié en profondeur dans un très large secteur Sud à Est (dure le matin, devenant molle, humide et lourde en journée).
Éventuellement un peu de neige sèche résistant dans les combes raides exposées nord et abritées du vent au plus haut du massif (secteur Pic d'Anie essentiellement).

Aperçu météo pour le jeudi 26 février

	nuit	matin	après-midi	soir

Belle journée ensoleillée, un peu de vent sur les sommets.

Pluie-Neige				
Iso 0 °C	3 000 m	3 000 m	3 000 m	3 000 m
Vent 1000 m	↑ 20 km/h	↑ 20 km/h	↑ 25 km/h	↑ 30 km/h
Vent 2000 m	↑ 35 km/h	↑ 35 km/h	↑ 45 km/h	↑ 50 km/h

Épaisseur de neige hors-piste

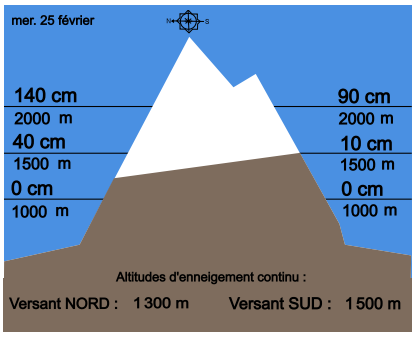

Précipitations à 1800 m

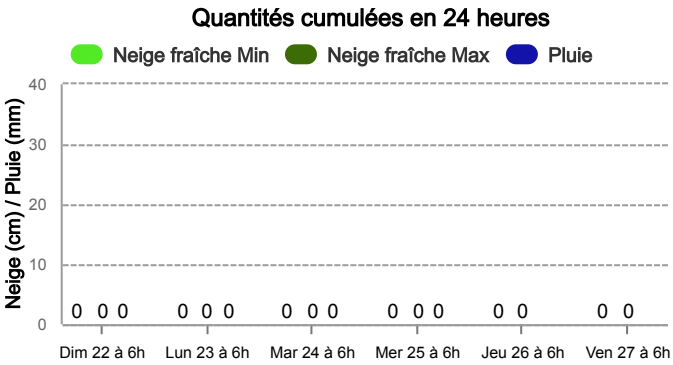

Tendance du vendredi 27 février

1

Indice de risque faible

Stationnaire et de même nature.

Pour consulter la vigilance en cours, veuillez vous rendre sur le site https://vigilance.meteofrance.fr/fr

Météo-France - 73 avenue de Paris, 94165 Saint-Mandé cedex - Contact : contact@meteo.fr

Rédigé par Météo-France avec la contribution des observateurs du réseau nivo-météorologiques. Partenariat : ANMSM (Maires de Stations de Montagne), DSF (Domaines Skiables de France), ADSP (Directeurs de Pistes et de la Sécurité des Stations de Sports d'Hiver) et autres acteurs de la montagne.

Bulletin neige & avalanches par téléphone au

0 892 68 10 20 Service 0,35 € / min + prix appel

RÉPUBLIQUE FRANÇAISE
Liberté Égalité Fraternité

METEO FRANCE
À VOS CÔTÉS, DANS UN CLIMAT QUI CHANGE

Bulletin d'estimation du risque d'avalanche
(valable en dehors des pistes balisées et ouvertes)
MASSIF : Pays-Basque

Rédigé le mercredi 25 Février 2026 à 15h

Conditions nivo-météo des 7 derniers jours

	jeu. 19/02				ven. 20/02				sam. 21/02				dim. 22/02				lun. 23/02				mar. 24/02				mer. 25/02			
	03h	09h	15h	21h	03h	09h	15h	21h	03h	09h	15h	21h	03h	09h	15h	21h	03h	09h	15h	21h	03h	09h	15h	21h	03h	09h	15h	21h
Météo																												
Vent (km/h)	95	80	55	40	30	20	25	20	20	10	15	20	25	25	25	25	15	15	20	45	60	55	40	35	35	35	35	35
à 2000m																												
Vent (km/h)	55	40	25	15	15	10	15	10	5	2	10	10	15	15	10	5	5	5	10	15	20	15	15	15	15	15	15	15
à 1000m																												

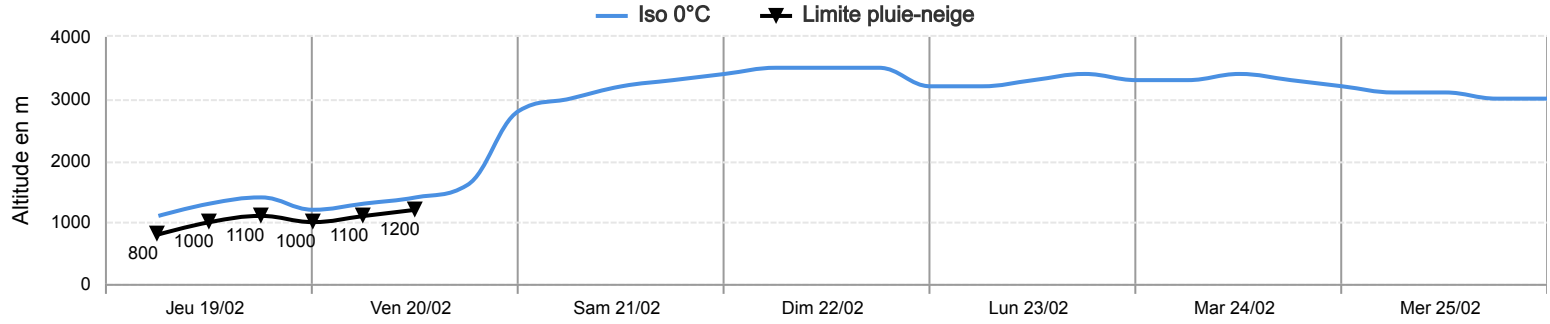

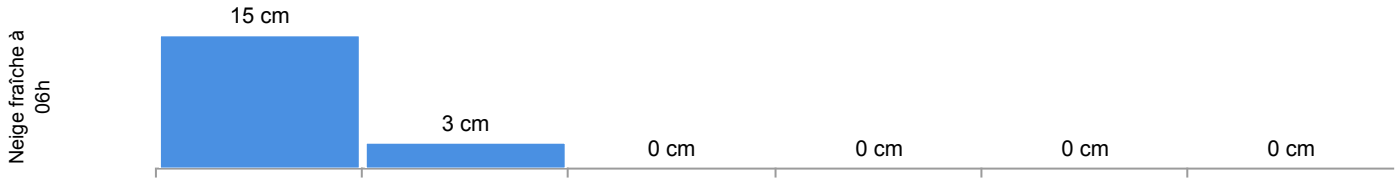

Risque d'avalanche	jeu. 19/02	ven. 20/02	sam. 21/02	dim. 22/02	lun. 23/02	mar. 24/02	mer. 25/02
	3	3	3	2	2	2	1

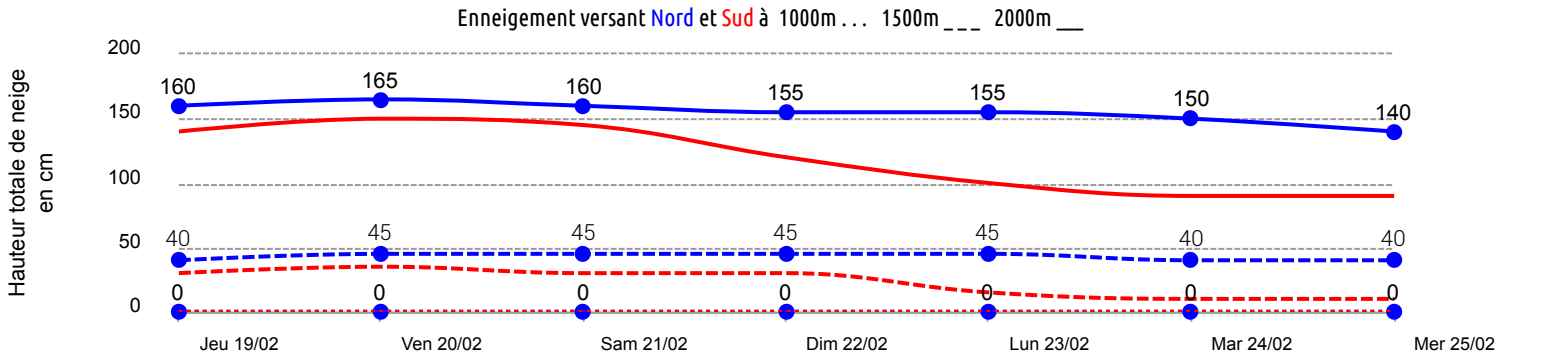

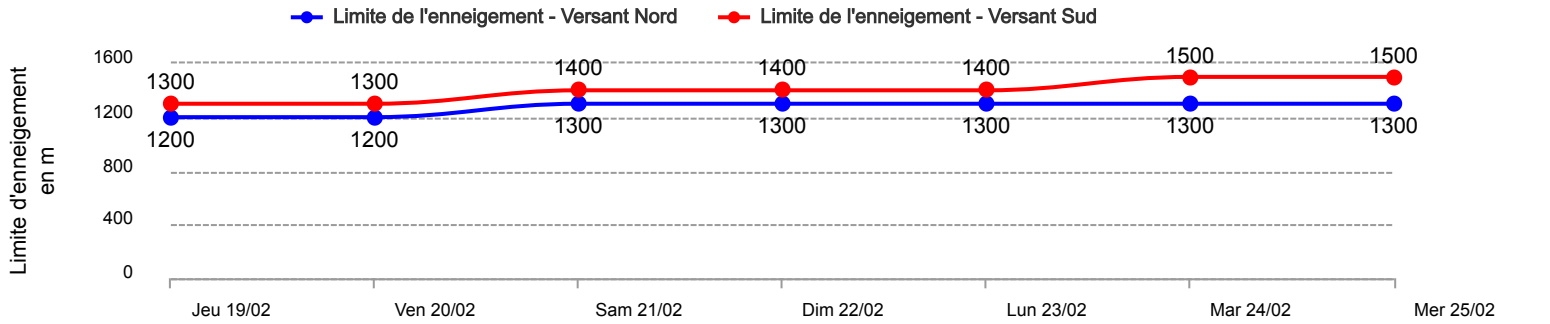

Pour consulter la vigilance en cours, veuillez vous rendre sur le site https://vigilance.meteofrance.fr/fr

Météo-France - 73 avenue de Paris, 94165 Saint-Mandé cedex - Contact : contact@meteo.fr

Rédigé par Météo-France avec la contribution des observateurs du réseau nivo-météorologiques. Partenariat : ANMSM (Maires de Stations de Montagne), DSF (Domaines Skiables de France), ADSP (Directeurs de Pistes et de la Sécurité des Stations de Sports d'Hiver) et autres acteurs de la montagne.

Bulletin neige & avalanches par téléphone au
0 892 68 10 20 Service 0,35 € / min + prix appel