Bulletin d'estimation du risque d'avalanche

(valable en dehors des pistes balisées et ouvertes)

MASSIF : Chartreuse

Rédigé le mercredi 25 février 2026 à 16h

Estimation des risques pour le : JEUDI 26 FÉVRIER

ACTIVITÉ PRINTANIÈRE DANS LA NEIGE RÉCENTE.

2

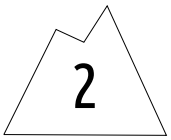

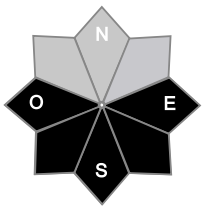

humidification

Indice de risque limité.

Départs spontanés : Quelques avalanches humides, départ possible au terrain. De taille 1 à 2, rare taille 3 non exclue. Risque de rupture de corniche.

Déclenchements provoqués : Sous les skis dans une pente réchauffée.

Indices de risque : 5 très fort - 4 fort - 3 marqué - 2 limité - 1 faible -- En noir : les pentes les plus dangereuses

Stabilité du manteau neigeux

Situation avalancheuse typique : neige humide avalanches de fond

Départs spontanés : Avec la période de grande douceur qui se prolonge, et l'humidification qui gagne en profondeur, quelques avalanches de neige humide restent possibles, plus probables en cours de journée dans les pentes réchauffées par le soleil. Localement en terrain herbeux / secteur de reptation, un départ d'une avalanche de fond reste possible à toute heure du jour ou de la nuit. De taille 1 à 2, même si une rare taille 3 ne peut être totalement exclue au vu des volumes de neige récente en altitude. A signaler également un risque de rupture de corniche près des crêtes sommitales. Plus bas que 1600/1800 m et en plein Sud, le risque semble être encore un peu plus limité, la neige s'y étant davantage transformée.

Déclenchements provoqués : Les (très) rares plaques encore présentes surtout dans les versants Nord d'altitude sont devenues difficiles à déclencher. Le risque principal est plutôt de faire couler de la neige humide sous les skis en évoluant à un horaire inadapté dans une pente réchauffée.

Qualité de la neige

Qualification de l'enneigement : L'enneigement commence à régresser tout en bas, mais il est bon pour la saison dès 1200 m, voire abondant au dessus de 1500 m environ, notamment dans les combes d'altitude. On trouve des crêtes un peu dégarnies par le vent, ou au contraire des corniches assez conséquentes.

Limites skiables : vers 1100/1300 m.

Qualité de la neige jeudi : Neige humide avec un cycle de printemps dans la plupart des versants, parfois croûtée en début de journée (regel pouvant être correct en l'absence de vent et sous ciel dégagé). L'humidification reprend en journée, plus marquée au soleil. Dans les versants ombragés d'altitude, la neige est plus mate, également densifiée, quelques croûtes plus fines y sont possibles.

Aperçu météo pour le jeudi 26 février

	nuit	matin	après-midi	soir
	Poursuite du temps ensoleillé et très doux.			
Pluie-Neige				
Iso 0 °C	3 100 m	3 100 m	3 100 m	3 100 m
Vent 1500 m	↖ 10 km/h	↑ 10 km/h	→ 10 km/h	↖ 10 km/h
Vent 2000 m	↑ 25 km/h	↑ 20 km/h	↑ 20 km/h	↗ 15 km/h

Épaisseur de neige hors-piste

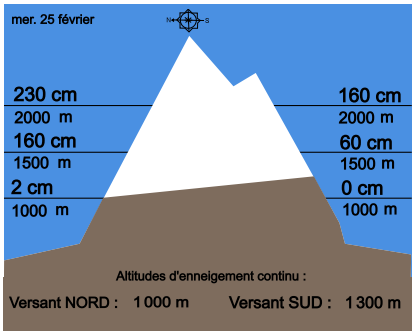

Précipitations à 1800 m

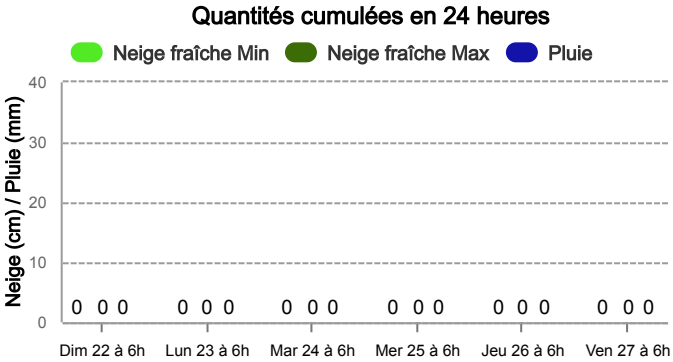

Tendance du vendredi 27 février

2

Indice de risque limité

Vendredi, le risque évolue peu. Maintien d'un temps ensoleillé et doux. Isotherme 0°C vers 3000 m.

Pour consulter la vigilance en cours, veuillez vous rendre sur le site https://vigilance.meteofrance.fr/fr

Météo-France - 73 avenue de Paris, 94165 Saint-Mandé cedex - Contact : contact@meteo.fr

Rédigé par Météo-France avec la contribution des observateurs du réseau nivo-météorologiques. Partenariat : ANMSM (Maires de Stations de Montagne), DSF (Domaines Skiables de France), ADSP (Directeurs de Pistes et de la Sécurité des Stations de Sports d'Hiver) et autres acteurs de la montagne.

Bulletin neige & avalanches par téléphone au 0 892 68 10 20 Service 0,35 € / min + prix appel

RÉPUBLIQUE FRANÇAISE
Liberté Égalité Fraternité

METEO FRANCE
À VOS CÔTÉS, DANS UN CLIMAT QUI CHANGE

Bulletin d'estimation du risque d'avalanche

(valable en dehors des pistes balisées et ouvertes)

MASSIF : Chartreuse

Rédigé le mercredi 25 février 2026 à 16h

Conditions nivo-météo des 7 derniers jours

	jeu. 19/02				ven. 20/02				sam. 21/02				dim. 22/02				lun. 23/02				mar. 24/02				mer. 25/02			
	03h	09h	15h	21h	03h	09h	15h	21h	03h	09h	15h	21h	03h	09h	15h	21h	03h	09h	15h	21h	03h	09h	15h	21h	03h	09h	15h	21h
Météo																												
Vent (km/h)	75	50	55	70	65	60	60	60	50	50	50	50	35	35	30	30	30	20	20	30	35	35	20	15	25	25	25	30
à 2000m	↑	→	↘	↘	↓	↓	↓	↓	↻	↓	↓	↓	↓	↘	→	→	→	↓	↓	↓	↙	↙	↙	↗	↗	↑	↑	↑
Vent (km/h)	45	25	25	25	40	35	35	30	20	20	20	15	10	10	10	15	15	15	15	15	15	15	10	10	10	15	15	20
à 1500m	↑	↗	→	↘	→	↓	↓	↓	↙	↓	↓	↓	↙	↙	↗	↓	↗	↙	↓	↓	↙	←	↓	←	↙	↑	↑	↑

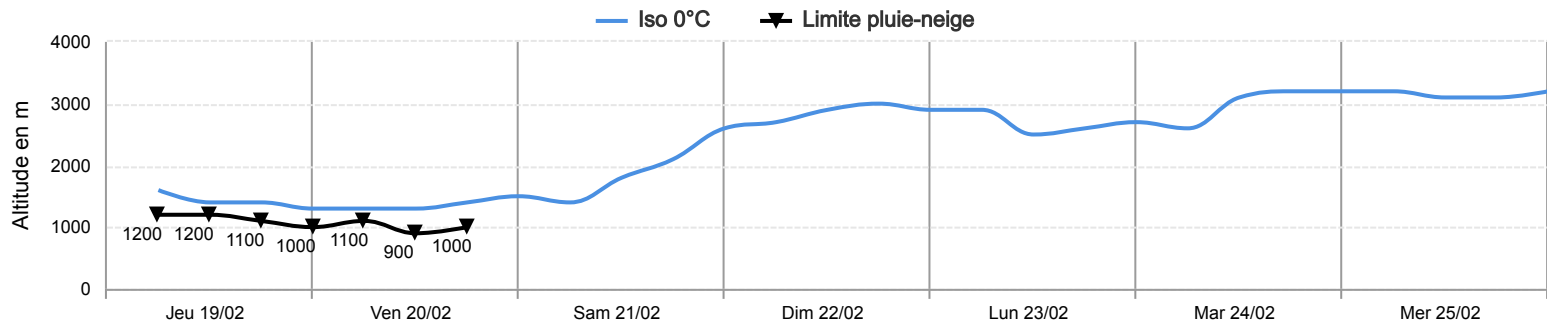

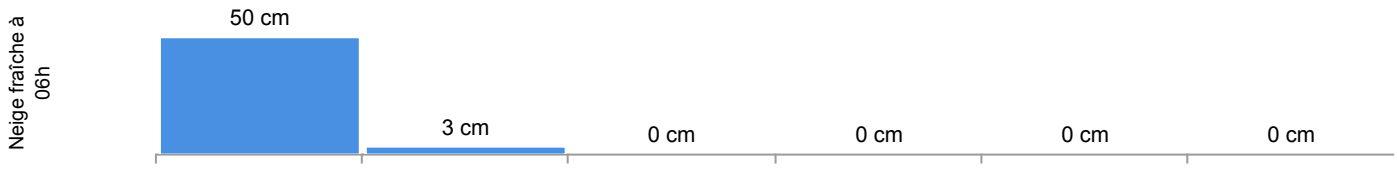

Risque d'avalanche	jeu. 19/02	ven. 20/02	sam. 21/02	dim. 22/02	lun. 23/02	mar. 24/02	mer. 25/02
	4	4	3	2	2	2	2

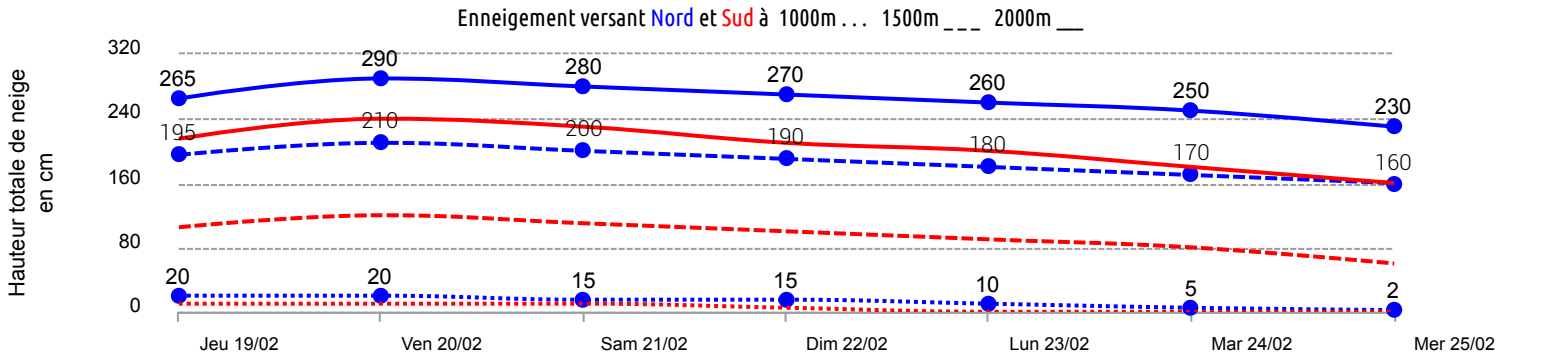

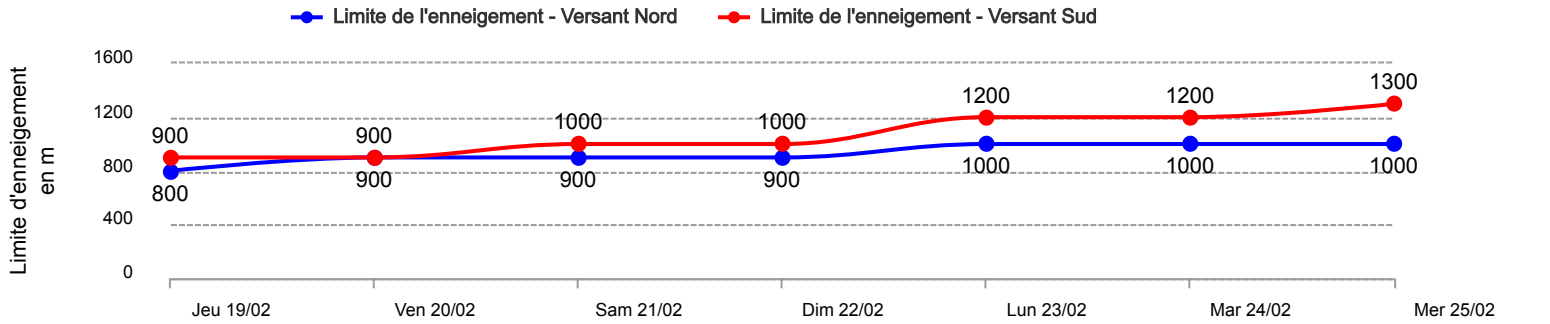

Pour consulter la vigilance en cours, veuillez vous rendre sur le site https://vigilance.meteofrance.fr/fr

Météo-France - 73 avenue de Paris, 94165 Saint-Mandé cedex - Contact : contact@meteo.fr

Rédigé par Météo-France avec la contribution des observateurs du réseau nivo-météorologiques. Partenariat : ANMSM (Maires de Stations de Montagne), DSF (Domaines Skiables de France), ADSP (Directeurs de Pistes et de la Sécurité des Stations de Sports d'Hiver) et autres acteurs de la montagne.

Bulletin neige & avalanches par téléphone au

0 892 68 10 20 Service 0,35 € / min + prix appel