RÉPUBLIQUE FRANÇAISE
Liberté Égalité Fraternité

METEO FRANCE
À VOS CÔTÉS, DANS UN CLIMAT QUI CHANGE

Bulletin d'estimation du risque d'avalanche
(valable en dehors des pistes balisées et ouvertes)
MASSIF : Embrunais Parpaillon

Rédigé le mercredi 25 février 2026 à 16h

Estimation des risques pour le : JEUDI 26 FÉVRIER

AVALANCHES DE NEIGE HUMIDE AU SOLEIL, PARFOIS GRANDES - RARES PLAQUES EN UBACS D'ALTITUDE, MAIS GROS VOLUME EN CAS DE DÉPART

3

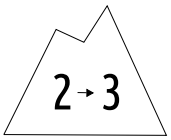

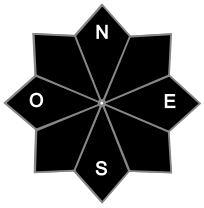

Indice de risque limité évoluant en marqué.

Départs spontanés : avalanches de neige humide au soleil, départs ponctuels ou linéaires mobilisant beaucoup de neige.

Déclenchements provoqués : plaques généralement difficiles à déclencher dans les versants ombragés d'altitude, mais mobilisant tout le manteau neigeux en place en cas de départ.

Indices de risque : 5 très fort - 4 fort - 3 marqué - 2 limité - 1 faible -- En noir : les pentes les plus dangereuses

Stabilité du manteau neigeux

Situation avalancheuse typique : neige humide couche fragile persistante

Départs spontanés : * Activité en neige humide en hausse selon la course du soleil, départs en poire ou linéaires, souvent près des rochers ou des barres. Ces avalanches mobilisent des volumes de neige parfois conséquents, en emportant une grande partie du manteau neigeux en place. Avalanches moyennes à grandes (taille 2 à 3), pouvant descendre à basse altitude dans les couloirs habituels.
* Quelques plaques de fond peuvent céder spontanément à toute heure du jour ou de la nuit en terrain favorable (dalles lisses, sols herbeux). Avalanches moyennes en général (taille 2).
* Une première petite avalanche superficielle de neige humide ou la chute d'une corniche peuvent engendrer un départ de plaque en contrebas.

Déclenchements provoqués : * Dans les ubacs au-dessus de 2200/2300 m environ, **un skieur peut encore déclencher de façon isolée une plaque épaisse et large qui emporte la quasi-totalité du manteau neigeux en place** et provoque une grande avalanche (taille 3). Déclenchements peu probables dans les grandes pentes homogènes, mais parfois possibles au niveau des discontinuités de terrain (croupes, rochers affleurants, transitions entre zones très enneigées et moins enneigées), là où les épaisseurs de neige plus faibles isolent moins la couche fragile enfouie. Depuis ces zones moins enneigées, **un pratiquant peut déclencher à distance les grandes pentes** nettement plus chargées situées à proximité. Une lecture attentive et précise du terrain est ainsi nécessaire pour éviter les zones de danger potentiel.
* Dans une pente raide ayant trop chauffé au soleil, un skieur peut initier une avalanche de neige humide avec départ ponctuel, voire linéaire.

Qualité de la neige

L'enneigement est excédentaire pour un mois de février.
Hauteurs de neige observées : environ 100 cm à la Nivôse du Parpaillon à 2550 m, secteur soufflé par le vent.

Limite d'enneigement skiable vers 1200/1300 m en ubacs, plutôt 1600/1800 m en adrets.

État de la neige de surface : * En adrets, manteau neigeux désormais bien printanier jusqu'à très haute altitude, petite croûte le matin, puis humidification au soleil l'après-midi, sur une grande épaisseur dans les pentes bien exposées.
* En ubacs (nord-ouest à nord-est), croûte de quelques cm le matin sous 2100/2200 m environ sur les zones peu pentues, s'humidifiant en cours de journée. Ailleurs, la neige est soit cartonnée/durcie par les épisodes de vent passés, ou en poudreuse dense dans les combes ou pentes abritées.

Aperçu météo pour le jeudi 26 février

nuit	matin	après-midi	soir

Le temps printanier se poursuit : soleil et températures très élevées pour une fin février, 12/13 °C à 2000 m l'après-midi. Vent faible.

Pluie-Neige				
Iso 0 °C	3 100 m	3 200 m	3 300 m	3 200 m
Vent 2000 m	↖ 5 km/h	↗ 5 km/h	↗ 5 km/h	→ 5 km/h
Vent 3000 m	↗ 10 km/h	→ 5 km/h	→ 10 km/h	↗ 10 km/h

Épaisseur de neige hors-piste

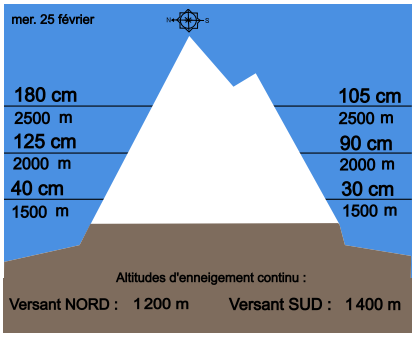

Précipitations à 1800 m

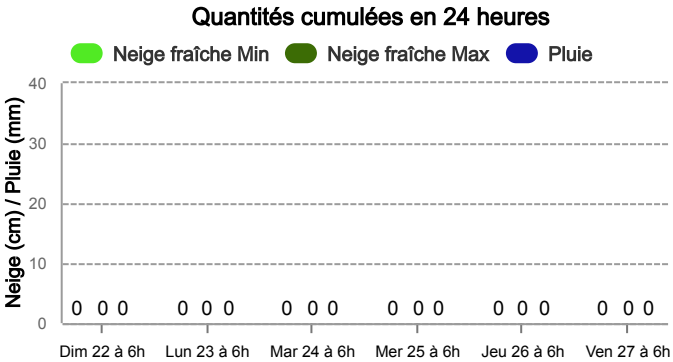

Tendance du vendredi 27 février

3

Indice de risque marqué

Maintien probable d'un risque marqué, avec les mêmes problématiques : neige humide et plaques épaisses difficiles à solliciter en ubacs d'altitude.

Pour consulter la vigilance en cours, veuillez vous rendre sur le site https://vigilance.meteofrance.fr/fr

Météo-France - 73 avenue de Paris, 94165 Saint-Mandé cedex - Contact : contact@meteo.fr

Rédigé par Météo-France avec la contribution des observateurs du réseau nivo-météorologiques. Partenariat : ANMSM (Maires de Stations de Montagne), DSF (Domaines Skiables de France), ADSP (Directeurs de Pistes et de la Sécurité des Stations de Sports d'Hiver) et autres acteurs de la montagne.

Bulletin neige & avalanches par téléphone au
0 892 68 10 20 Service 0,35 € / min + prix appel

RÉPUBLIQUE FRANÇAISE
Liberté Égalité Fraternité

METEO FRANCE
À VOS CÔTÉS, DANS UN CLIMAT QUI CHANGE

Bulletin d'estimation du risque d'avalanche
(valable en dehors des pistes balisées et ouvertes)
MASSIF : Embrunais Parpaillon

Rédigé le mercredi 25 février 2026 à 16h

Conditions nivo-météo des 7 derniers jours

	jeu. 19/02				ven. 20/02				sam. 21/02				dim. 22/02				lun. 23/02				mar. 24/02				mer. 25/02			
	03h	09h	15h	21h	03h	09h	15h	21h	03h	09h	15h	21h	03h	09h	15h	21h	03h	09h	15h	21h	03h	09h	15h	21h	03h	09h	15h	21h
Météo																												
Vent (km/h)	55	50	70	55	70	60	60	60	60	60	70	60	35	30	40	40	40	40	40	35	25	10	5	5	15	10	15	20
à 3000m																												
Vent (km/h)	25	25	35	20	25	50	40	50	40	25	25	45	15	10	10	10	10	10	0	10	15	20	0	10	10	5	5	10
à 2000m																												

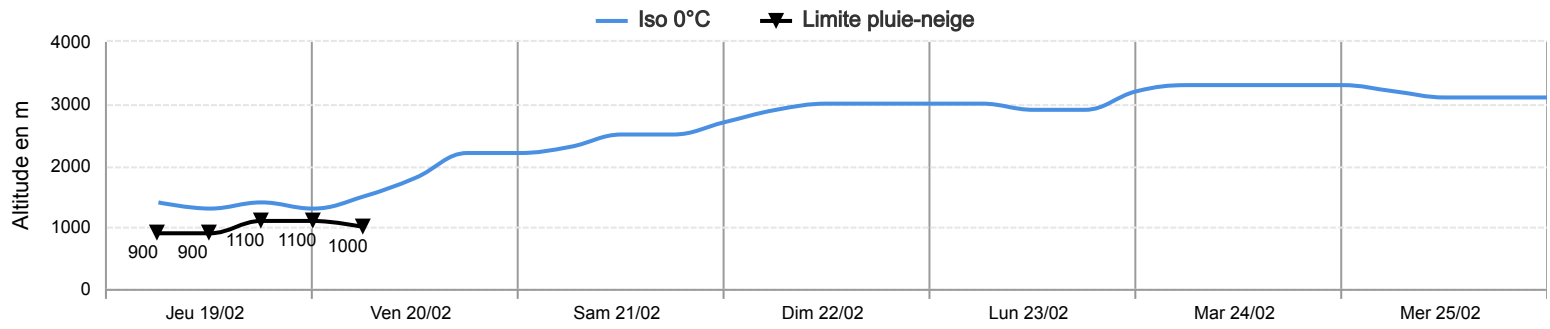

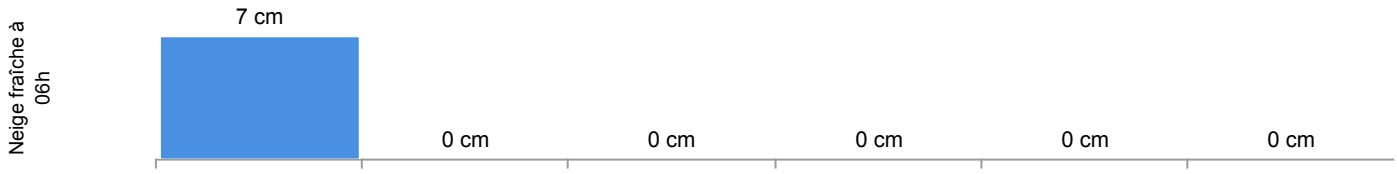

Risque d'avalanche	jeu. 19/02	ven. 20/02	sam. 21/02	dim. 22/02	lun. 23/02	mar. 24/02	mer. 25/02
	4	3	3	3	3	3	3

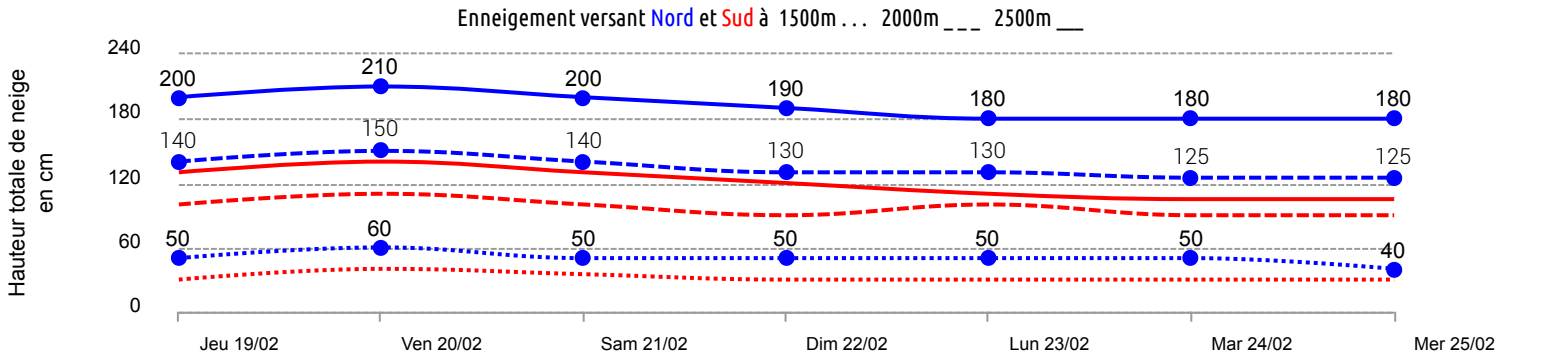

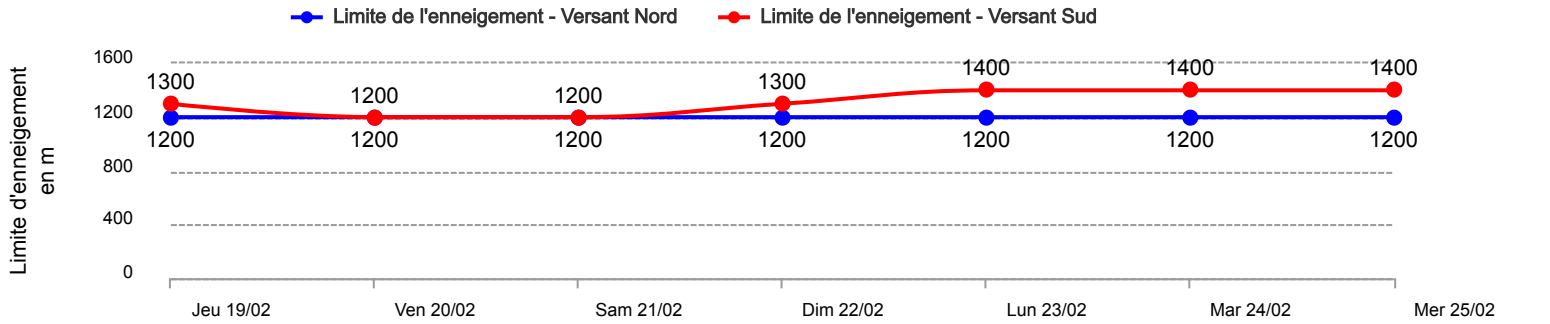

Pour consulter la vigilance en cours, veuillez vous rendre sur le site https://vigilance.meteofrance.fr/fr

Météo-France - 73 avenue de Paris, 94165 Saint-Mandé cedex - Contact : contact@meteo.fr

Rédigé par Météo-France avec la contribution des observateurs du réseau nivo-météorologiques. Partenariat : ANMSM (Maires de Stations de Montagne), DSF (Domaines Skiables de France), ADSP (Directeurs de Pistes et de la Sécurité des Stations de Sports d'Hiver) et autres acteurs de la montagne.

Bulletin neige & avalanches par téléphone au
0 892 68 10 20 Service 0,35 € / min + prix appel