RÉPUBLIQUE FRANÇAISE
Liberté Égalité Fraternité

METEO FRANCE
À VOS CÔTÉS, DANS UN CLIMAT QUI CHANGE

Bulletin d'estimation du risque d'avalanche
(valable en dehors des pistes balisées et ouvertes)
MASSIF : Grandes-Rousses

Rédigé le mercredi 25 février 2026 à 16h

Estimation des risques pour le : JEUDI 26 FÉVRIER

ACTIVITÉ PRINTANIÈRE DANS LA NEIGE RÉCENTE, ET DE RARES PLAQUES EN VERSANTS FROIDS D'ALTITUDE.

3

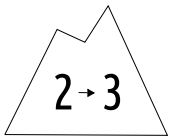

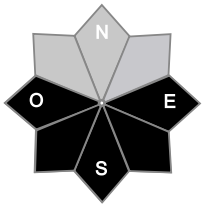

humidification

Indice de risque limité évoluant en marqué.

Départs spontanés : Avalanches humides, départ possible au terrain. De taille 1 à 2, quelques tailles 3 possibles. Risque de rupture de corniche.

Déclenchements provoqués : Rares instabilités dissimulées en altitude, avec des cassures potentiellement très épaisses. Ou sous les skis dans la neige humide.

Indices de risque : 5 très fort - 4 fort - 3 marqué - 2 limité - 1 faible -- En noir : les pentes les plus dangereuses

Stabilité du manteau neigeux

Situation avalancheuse typique : neige humide couche fragile persistante

Départs spontanés : Avec la période de grande douceur qui se prolonge, et l'humidification qui gagne en profondeur, des avalanches de neige humide restent possibles, plus probables en cours de journée dans les pentes réchauffées par le soleil. Localement en terrain herbeux / secteur de reptation de moyenne altitude, un départ d'une avalanche de fond reste possible à toute heure du jour ou de la nuit. De taille 1 à 2, avec quelques tailles 3 possibles au vu des volumes de neige récente. A signaler également un risque de rupture de corniche près des crêtes sommitales, pouvant déclencher une avalanche en contrebas. Plus bas que 1600/1800 m, le risque semble être un peu plus limité, la neige s'y étant davantage transformée avec le redoux.

Déclenchements provoqués : De rares instabilités restent dissimulées sous les importantes quantités de neige récente tombée la semaine dernière, encore possibles dans de nombreuses orientations à l'exception peut-être du plein Sud. Ces plaques, parfois très épaisses dans les zones d'accumulations, reposent sur des couches fragiles persistantes enfouies. Leur stabilisation est assez lente, en particulier dans les versants ombragés d'altitude au-dessus de 2200/2300 m, moins impactées par le redoux. Bien que se faisant moins nombreuses au fil des jours et plus difficiles à déclencher, on ne peut exclure qu'un skieur isolé ou un groupe de skieurs puisse les solliciter localement. Par exemple, dans les secteurs où l'épaisseur du manteau neigeux est un peu moins importante, permettant de les atteindre plus facilement : en bord de zone d'accumulation, à proximité des rochers, ou dans des ruptures de pentes. Les volumes mobilisés peuvent être importants, avec des cassures potentiellement supérieures au mètre. Plus bas que 2200 m en revanche, le risque principal est plutôt de faire couler de la neige humide sous les skis en évoluant à un horaire inadapté dans une pente réchauffée.

Qualité de la neige

Qualification de l'enneigement : l'enneigement commence à régresser tout en bas, mais est bon pour la saison dès 1200 m, voire abondant au dessus de 1500 m environ, notamment dans les combes d'altitude. On trouve des crêtes un peu dégarnies par le vent, ou au contraire des corniches assez conséquentes.

Limites skiables : vers 1100/1300 m.

Qualité de la neige jeudi : Sous 2000/2400 m voire plus haut en Sud, neige humide avec un cycle de printemps, parfois croûtée en début de journée (regel pouvant être correct en l'absence de vent et sous ciel dégagé). L'humidification reprend en journée, plus marquée au soleil et gagnant en profondeur. Dans les versants ombragés au-dessus de 2000/2400 m, neige restée davantage poudreuse, bien que de plus en plus tassée/densifiée au fil des jours. A proximité des crêtes, neige parfois soufflée ou travaillée par le vent.

Aperçu météo pour le jeudi 26 février

	nuit	matin	après-midi	soir
Poursuite du temps ensoleillé et très doux.				
Pluie-Neige				
Iso 0 °C	3 100 m	3 200 m	3 100 m	3 100 m
Vent 2000 m	↑ 5 km/h	↗ 5 km/h	↗ 5 km/h	↗ 5 km/h
Vent 3000 m	↑ 15 km/h	↗ 15 km/h	↗ 15 km/h	↗ 10 km/h

Épaisseur de neige hors-piste

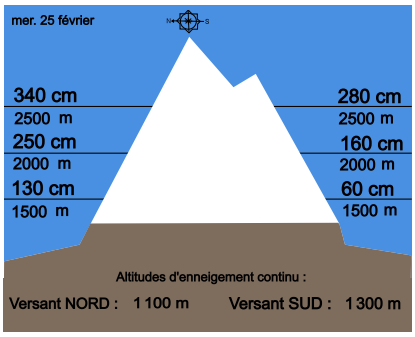

Précipitations à 1800 m

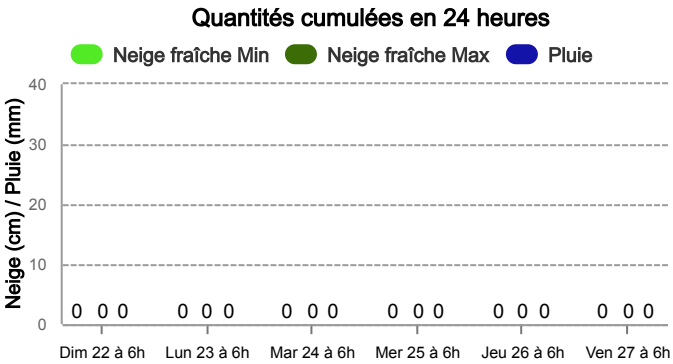

Tendance du vendredi 27 février

2

Indice de risque limité

Vendredi, le risque diminuerait un peu, même si quelques instabilités persistent en haute montagne, et quelques départs restent possibles dans la neige humide au soleil et aux altitudes plus modestes. Maintien d'un temps ensoleillé et doux. Isotherme 0°C vers 3000 m.

Pour consulter la vigilance en cours, veuillez vous rendre sur le site https://vigilance.meteofrance.fr/fr

Météo-France - 73 avenue de Paris, 94165 Saint-Mandé cedex - Contact : contact@meteo.fr

Rédigé par Météo-France avec la contribution des observateurs du réseau nivo-météorologiques. Partenariat : ANMSM (Maires de Stations de Montagne), DSF (Domaines Skiables de France), ADSP (Directeurs de Pistes et de la Sécurité des Stations de Sports d'Hiver) et autres acteurs de la montagne.

Bulletin neige & avalanches par téléphone au
0 892 68 10 20 Service 0,35 € / min + prix appel

RÉPUBLIQUE FRANÇAISE
Liberté Égalité Fraternité

METEO FRANCE
À VOS CÔTÉS, DANS UN CLIMAT QUI CHANGE

Bulletin d'estimation du risque d'avalanche

(valable en dehors des pistes balisées et ouvertes)

MASSIF : Grandes-Rousses

Rédigé le mercredi 25 février 2026 à 16h

Conditions nivo-météo des 7 derniers jours

	jeu. 19/02				ven. 20/02				sam. 21/02				dim. 22/02				lun. 23/02				mar. 24/02				mer. 25/02			
	03h	09h	15h	21h	03h	09h	15h	21h	03h	09h	15h	21h	03h	09h	15h	21h	03h	09h	15h	21h	03h	09h	15h	21h	03h	09h	15h	21h
Météo																												
Vent (km/h)	55	35	60	60	60	60	60	70	60	55	50	40	45	40	40	35	35	30	30	30	30	25	15	10	10	10	15	15
à 3000m																												
Vent (km/h)	35	20	25	25	35	40	35	40	40	25	25	20	15	10	15	15	15	15	15	15	15	10	10	5	5	5	10	10
à 2000m																												

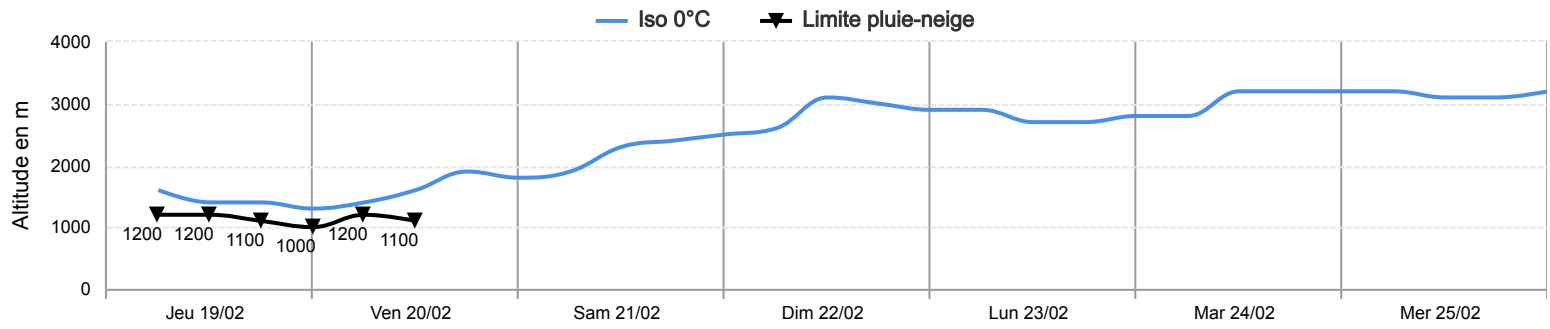

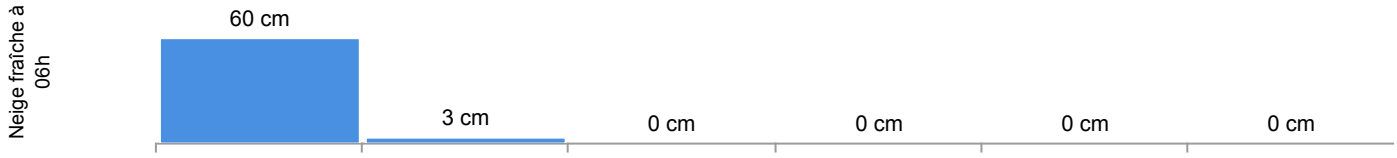

Risque d'avalanche	jeu. 19/02	ven. 20/02	sam. 21/02	dim. 22/02	lun. 23/02	mar. 24/02	mer. 25/02
	5	5	4	3	3	3	3

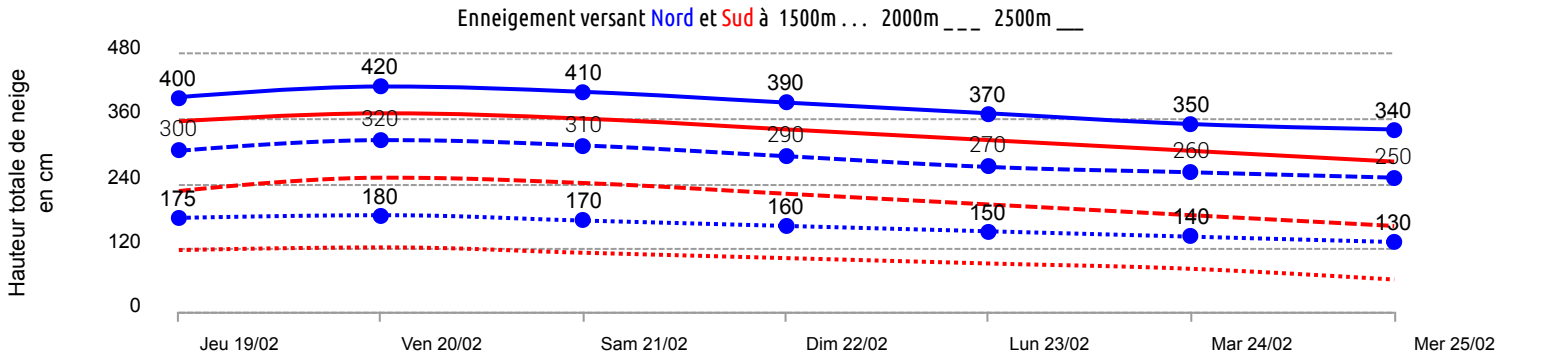

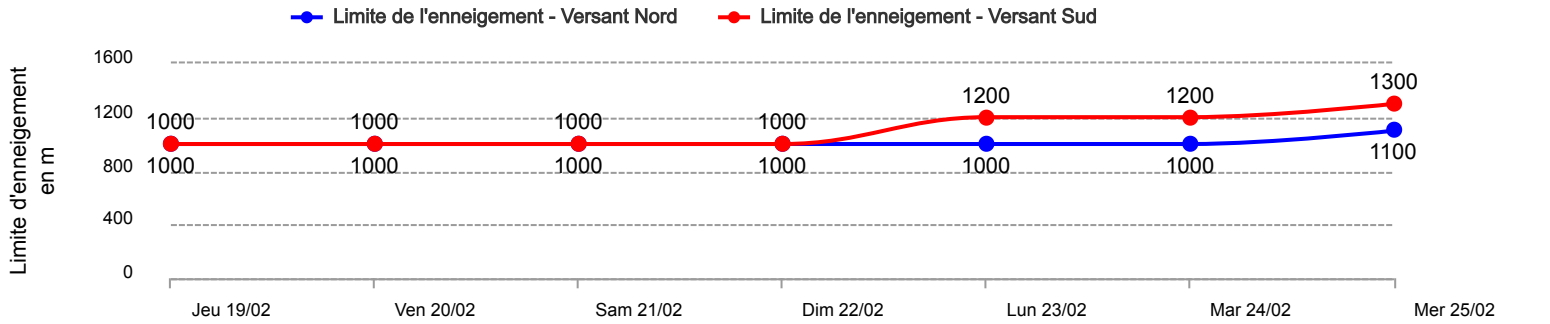

Pour consulter la vigilance en cours, veuillez vous rendre sur le site https://vigilance.meteofrance.fr/fr

Météo-France - 73 avenue de Paris, 94165 Saint-Mandé cedex - Contact : contact@meteo.fr

Bulletin neige & avalanches par téléphone au

0 892 68 10 20 Service 0,35 € / min + prix appel

Rédigé par Météo-France avec la contribution des observateurs du réseau nivo-météorologiques. Partenariat : ANMSM (Maires de Stations de Montagne), DSF (Domaines Skiables de France), ADSP (Directeurs de Pistes et de la Sécurité des Stations de Sports d'Hiver) et autres acteurs de la montagne.