RÉPUBLIQUE FRANÇAISE
Liberté Égalité Fraternité

METEO FRANCE
À VOS CÔTÉS, DANS UN CLIMAT QUI CHANGE

Bulletin d'estimation du risque d'avalanche
(valable en dehors des pistes balisées et ouvertes)
MASSIF : Haute-Ariege

Rédigé le mercredi 25 février 2026 à 16h

Estimation des risques pour le : JEUDI 26 FÉVRIER

HUMIDIFICATION QUI SE POURSUIT EN VERSANT SUD EN GAGNANT EN ALTITUDE ET EN PROFONDEURDITIONS PRINTANIÈRES

2

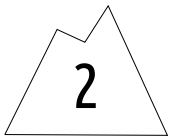

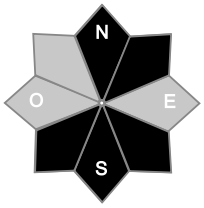

Indice de risque limité.

Départs spontanés : Avalanches de neige humide ou avalanches de fond au soleil, taille 1 ou 2, exceptionnellement 3.

Déclenchements provoqués : Rares structures de plaques en nord/nord est au delà de 2100/2200 m.

Indices de risque : 5 très fort - 4 fort - 3 marqué - 2 limité - 1 faible -- En noir : les pentes les plus dangereuses

Stabilité du manteau neigeux

Situation avalancheuse typique : neige humide avalanches de fond

Départs spontanés :
- Activité avalancheuse qui augmente au fil de la journée dans les pentes raides prenant le soleil, notamment à proximité des rochers. Départs ponctuels d'avalanches petites à moyennes, plus rarement grandes, avec l'humidification qui se généralise au soleil à des altitudes élevées.
- Présence éventuelle de larges fissures dans les pentes au sol lisse, signes avant-coureurs d'une éventuelle avalanche de glissement pouvant en revanche se produire à tout moment.

Déclenchements provoqués :
Au-delà de 2000/2100 m, présence éventuelle de structures de plaques isolées avec une couche fragile persistante en grains anguleux enfouie sous la neige de la fin de semaine dernière. Déclenchables par un skieur dans quelques secteurs ou combes raides orientées principalement nord à nord-est, elles donneront des avalanches de taille petite à moyenne en cas de déclenchement (taille 1 à 2).
Observables : neige travaillée par le vent en surface, bruit d'effondrements sous les skis, couche de neige sans cohésion à 20/40 cm de la surface.

Autre :
- La neige a pris des allures printanières dans de nombreux secteurs avec un risque accru de glissade sur de la neige dure ou glacée en matinée après un bon regel nocturne, parfois encore plus tardivement en versant ouest. Certaines crêtes d'altitude sont aussi localement en glace dure.
- Les corniches sont volumineuses près des crêtes et sont fragilisées par l'humidification en cours.

Qualité de la neige

Enneigement :
Avec les passages neigeux qui se sont succédé depuis janvier, l'enneigement est excédentaire par rapport aux normales pour la période. Les vallons ombragés sont encore bien enneigés avec des quantités de neige importantes dès 1400 m, et une limite d'enneigement skiable évoluant pour le moment assez peu (1200/1300m).
Au soleil, le manteau neigeux perd un peu d'épaisseur depuis quelques jours, mais l'enneigement reste exploitable dès 1400/1500 m.

Qualité de la neige :
Bon regel nocturne des pentes humidifiées la veille, avec une neige dure, (voir une croute plus ou moins portante en versants nord), évoluant en journée vers une neige humide et lourde au fil de l'ensoleillement Les crêtes, cols et sommets sont souvent pelés et en neige dure en expositions ouest.
En altitude, neige encore sèche ou poudreuse dans les combes raides d'un large secteur Nord n'ayant pas trop pris le vent durant le dernier épisode perturbé.

Aperçu météo pour le jeudi 26 février

	nuit	matin	après-midi	soir
Journée printanière				
Pluie-Neige				
Iso 0 °C	3 100 m	3 000 m	3 000 m	3 100 m
Vent 2000 m	↑ 10 km/h	↑ 5 km/h	↗ 10 km/h	↗ 15 km/h
Vent 3000 m	↑ 15 km/h	↖ 10 km/h	↗ 15 km/h	↑ 15 km/h

Pour consulter la vigilance en cours, veuillez vous rendre sur le site https://vigilance.meteofrance.fr/fr

Météo-France - 73 avenue de Paris, 94165 Saint-Mandé cedex - Contact : contact@meteo.fr

Rédigé par Météo-France avec la contribution des observateurs du réseau nivo-météorologiques. Partenariat : ANMSM (Maires de Stations de Montagne), DSF (Domaines Skiables de France), ADSP (Directeurs de Pistes et de la Sécurité des Stations de Sports d'Hiver) et autres acteurs de la montagne.

Bulletin neige & avalanches par téléphone au
0 892 68 10 20 Service 0,35 € / min + prix appel

RÉPUBLIQUE FRANÇAISE
Liberté Égalité Fraternité

METEO FRANCE
À VOS CÔTÉS, DANS UN CLIMAT QUI CHANGE

Bulletin d'estimation du risque d'avalanche

(valable en dehors des pistes balisées et ouvertes)

MASSIF : Haute-Ariege

Rédigé le mercredi 25 février 2026 à 16h

Épaisseur de neige hors-piste

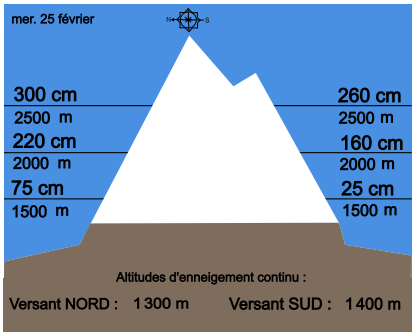

Précipitations à 1800 m

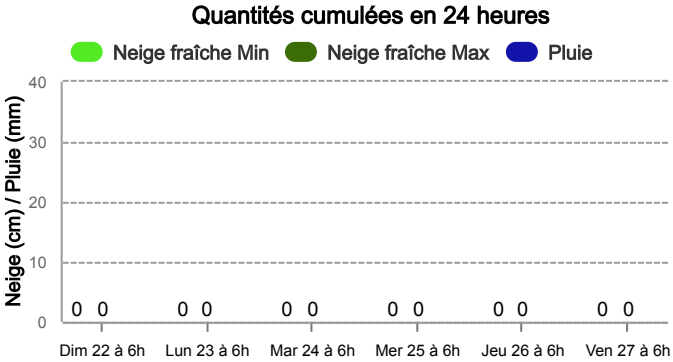

Tendance du vendredi 27 février

Indice de risque limité

risque stationnaire avec la persistance de conditions printanières

Pour consulter la vigilance en cours, veuillez vous rendre sur le site https://vigilance.meteofrance.fr/fr

Météo-France - 73 avenue de Paris, 94165 Saint-Mandé cedex - Contact : contact@meteo.fr

Rédigé par Météo-France avec la contribution des observateurs du réseau nivo-météorologiques. Partenariat : ANMSM (Maires de Stations de Montagne), DSF (Domaines Skiables de France), ADSP (Directeurs de Pistes et de la Sécurité des Stations de Sports d'Hiver) et autres acteurs de la montagne.

Bulletin neige & avalanches par téléphone au

0 892 68 10 20 Service 0,35 € / min + prix appel

RÉPUBLIQUE FRANÇAISE
Liberté Égalité Fraternité

METEO FRANCE
À VOS CÔTÉS, DANS UN CLIMAT QUI CHANGE

Bulletin d'estimation du risque d'avalanche

(valable en dehors des pistes balisées et ouvertes)

MASSIF : Haute-Ariege

Rédigé le mercredi 25 Février 2026 à 16h

Conditions nivo-météo des 7 derniers jours

	jeu. 19/02				ven. 20/02				sam. 21/02				dim. 22/02				lun. 23/02				mar. 24/02				mer. 25/02			
	03h	09h	15h	21h	03h	09h	15h	21h	03h	09h	15h	21h	03h	09h	15h	21h	03h	09h	15h	21h	03h	09h	15h	21h	03h	09h	15h	21h
Météo																												
Vent (km/h)	80	70	70	75	65	65	55	50	45	35	30	25	15	15	15	15	15	20	20	20	20	20	25	25	25	25	25	25
à 3000m																												
Vent (km/h)	50	45	45	40	35	35	30	30	25	20	20	15	10	10	5	10	10	10	10	10	10	10	15	15	15	15	15	15
à 2000m																												

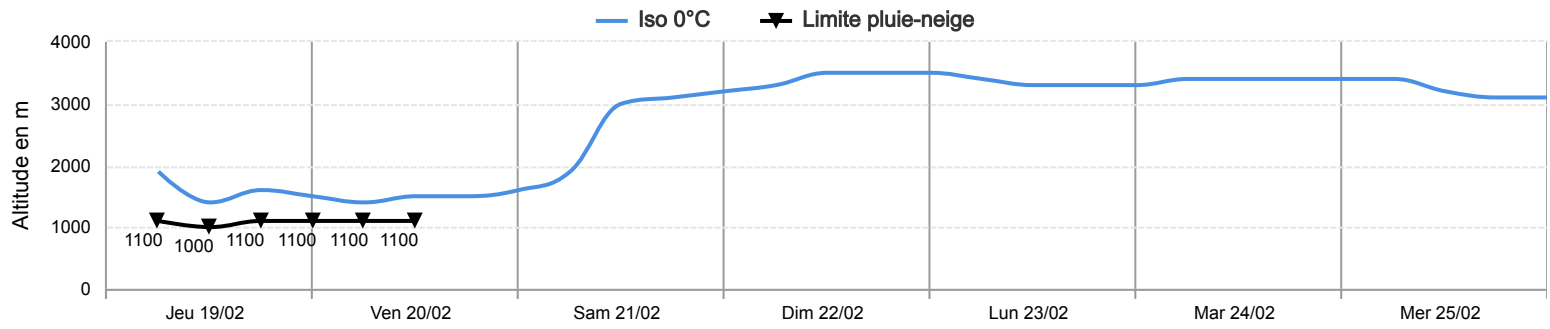

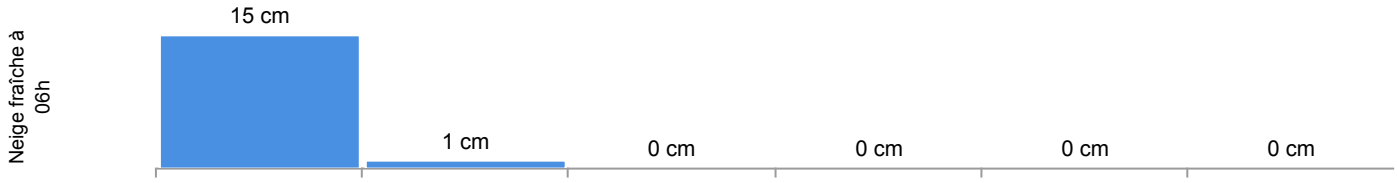

Risque d'avalanche	jeu. 19/02	ven. 20/02	sam. 21/02	dim. 22/02	lun. 23/02	mar. 24/02	mer. 25/02
	3	3	3	3	3	2	2

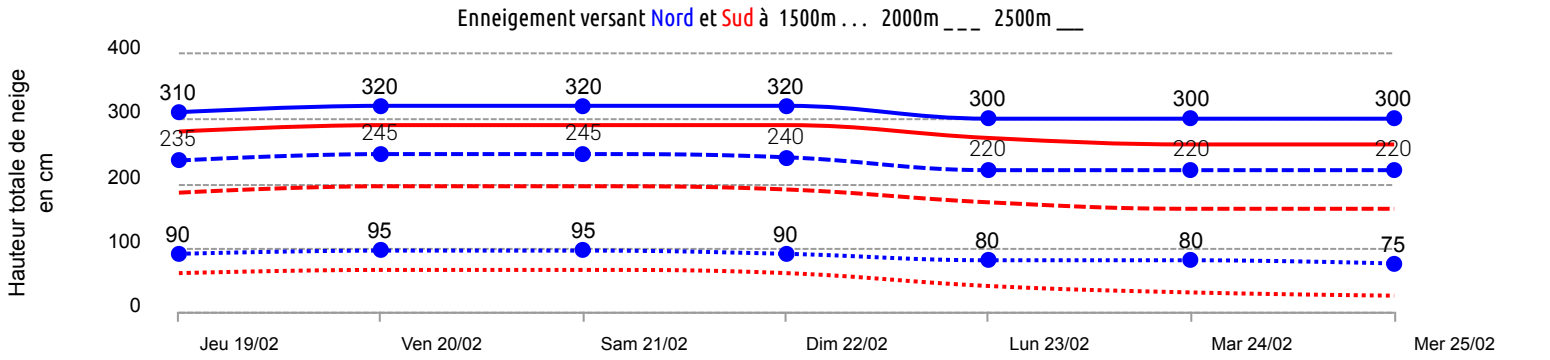

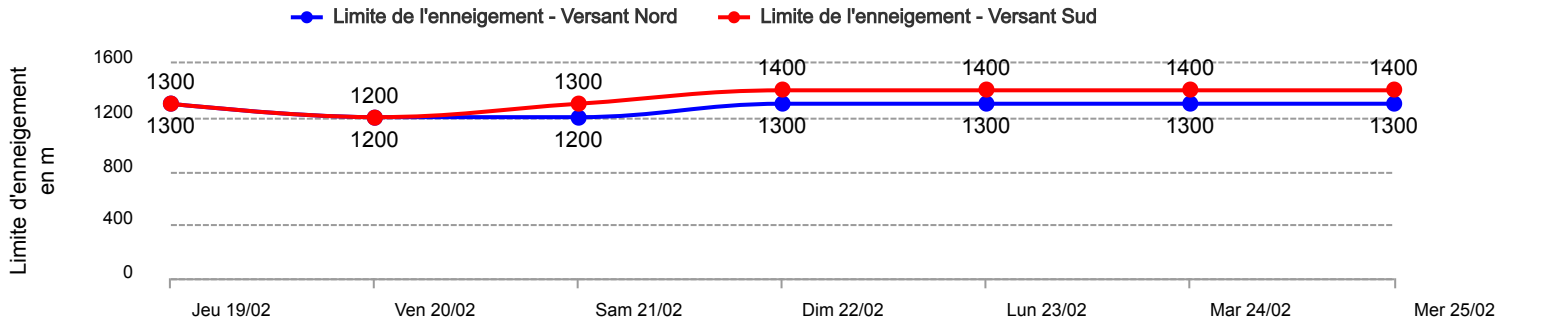

Pour consulter la vigilance en cours, veuillez vous rendre sur le site https://vigilance.meteofrance.fr/fr

Météo-France - 73 avenue de Paris, 94165 Saint-Mandé cedex - Contact : contact@meteo.fr

Rédigé par Météo-France avec la contribution des observateurs du réseau nivo-météorologiques. Partenariat : ANMSM (Maires de Stations de Montagne), DSF (Domaines Skiables de France), ADSP (Directeurs de Pistes et de la Sécurité des Stations de Sports d'Hiver) et autres acteurs de la montagne.

Bulletin neige & avalanches par téléphone au
0 892 68 10 20 Service 0,35 € / min + prix appel