Bulletin d'estimation du risque d'avalanche
(valable en dehors des pistes balisées et ouvertes)

MASSIF : Mercantour

Rédigé le mercredi 25 février 2026 à 16h

Estimation des risques pour le : JEUDI 26 FÉVRIER

MAINTIEN DE L'ACTIVITÉ EN NEIGE HUMIDE EN VERSANTS ENSOLEILLÉS, PARFOIS VOLUMINEUSE - PLAQUES RÉSIDUELLES DANS LA NEIGE VENTÉE EN ALTITUDE

2

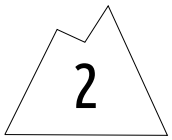

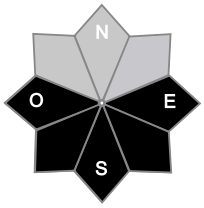

Indice de risque limité.

Départs spontanés : avalanches de neige humide et quelques avalanches de fond

Déclenchements provoqués : quelques plaques résiduelles + départs en neige humide

Indices de risque : 5 très fort - 4 fort - 3 marqué - 2 limité - 1 faible -- En noir : les pentes les plus dangereuses

Stabilité du manteau neigeux

Situation avalancheuse typique : neige humide neige ventée

Départs spontanés :
- **avalanches de neige humide**, pouvant être volumineuses et/ou emporter une grande partie du manteau neigeux en place. Peu probables en début de journée puis risque en hausse suivant la course du soleil, affectant surtout les orientations est / sud / ouest. Taille petite à moyenne, plus rarement grande, pouvant atteindre des altitudes relativement basses et toucher des fonds de vallées ou chemins plus bas. Départs généralement en poire.
- **éventuelles avalanches de fond**. Taille moyenne, plus rarement grande. Possibles à n'importe quel moment. En versant sud, plutôt au-dessous de 2500/2700 m. En versant nord, plutôt au-dessous de 2000 m.
- chute de corniche non exclue.

Déclenchements provoqués :
- **quelques plaques de surface résiduelles** au-dessus de 2000 m plus particulièrement en orientation nord-ouest à est, formées par le vent du week-end dernier et lundi. Plus ou moins faciles à déclencher. Taille petite, plus rarement moyenne.
- **en neige humide**. Un skieur peut également favoriser un départ en neige fortement humidifiée en pente raide ensoleillée aux heures les plus chaudes.

Qualité de la neige

Enneigement très excédentaire pour un mois de février.
Données observées : 145 cm à la nivôse de Millefonts à 2430 m, 116 cm à Isola 2000 à 1912 m.

Enneigement skiable dès 1300/1400 m en ubacs en terrains favorables et 1600/1800 m en adrets

État de la neige en surface : croute plus ou moins portante le matin après un regel nocturne correct, s'humidifiant rapidement en journée au fil de l'ensoleillement. En ubacs au-dessus de 2000/2200 m environ, neige froide souvent travaillée/durcie par le vent de nord. Zones dégarnies proches des crêtes, alternant avec des corniches parfois épaisses.

Aperçu météo pour le jeudi 26 février

	nuit	matin	après-midi	soir

Maintien de la grande douceur, 8 à 10 degrés à 2000 m.

Pluie-Neige				
Iso 0 °C	3 200 m	3 300 m	3 300 m	3 200 m
Vent 2000 m	10 km/h	5 km/h	10 km/h	10 km/h
Vent 3000 m	15 km/h	15 km/h	15 km/h	10 km/h

Épaisseur de neige hors-piste

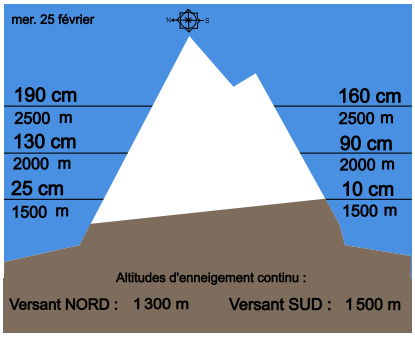

Précipitations à 1800 m

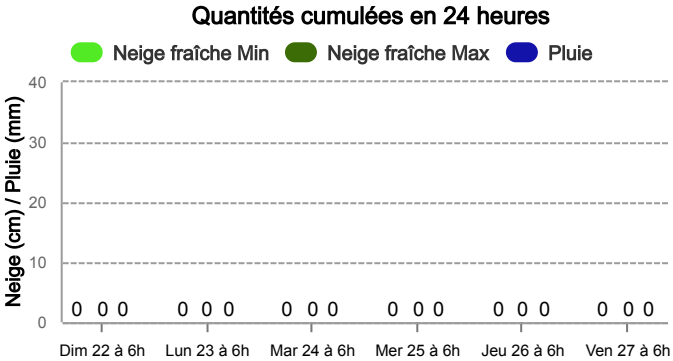

Tendance du vendredi 27 février

2

Indice de risque limité

Peu d'évolution. Maintien de l'activité en neige humide.

Pour consulter la vigilance en cours, veuillez vous rendre sur le site https://vigilance.meteofrance.fr/fr

Météo-France - 73 avenue de Paris, 94165 Saint-Mandé cedex - Contact : contact@meteo.fr

Rédigé par Météo-France avec la contribution des observateurs du réseau nivo-météorologiques. Partenariat : ANMSM (Maires de Stations de Montagne), DSF (Domaines Skiables de France), ADSP (Directeurs de Pistes et de la Sécurité des Stations de Sports d'Hiver) et autres acteurs de la montagne.

Bulletin neige & avalanches par téléphone au 0 892 68 10 20 Service 0,35 € / min + prix appel

RÉPUBLIQUE FRANÇAISE
Liberté Égalité Fraternité

METEO FRANCE
À VOS CÔTÉS, DANS UN CLIMAT QUI CHANGE

Bulletin d'estimation du risque d'avalanche
(valable en dehors des pistes balisées et ouvertes)

MASSIF : Mercantour

Rédigé le mercredi 25 février 2026 à 16h

Conditions nivo-météo des 7 derniers jours

	jeu. 19/02				ven. 20/02				sam. 21/02				dim. 22/02				lun. 23/02				mar. 24/02				mer. 25/02			
	03h	09h	15h	21h	03h	09h	15h	21h	03h	09h	15h	21h	03h	09h	15h	21h	03h	09h	15h	21h	03h	09h	15h	21h	03h	09h	15h	21h
Météo																												
Vent (km/h)	55	55	80	80	75	60	50	30	45	50	40	30	30	35	45	50	50	45	25	20	30	25	10	10	15	15	15	15
à 3000m																												
Vent (km/h)	30	35	35	45	45	40	15	15	15	20	15	20	15	15	20	15	25	20	15	15	15	10	5	10	10	10	10	10
à 2000m																												

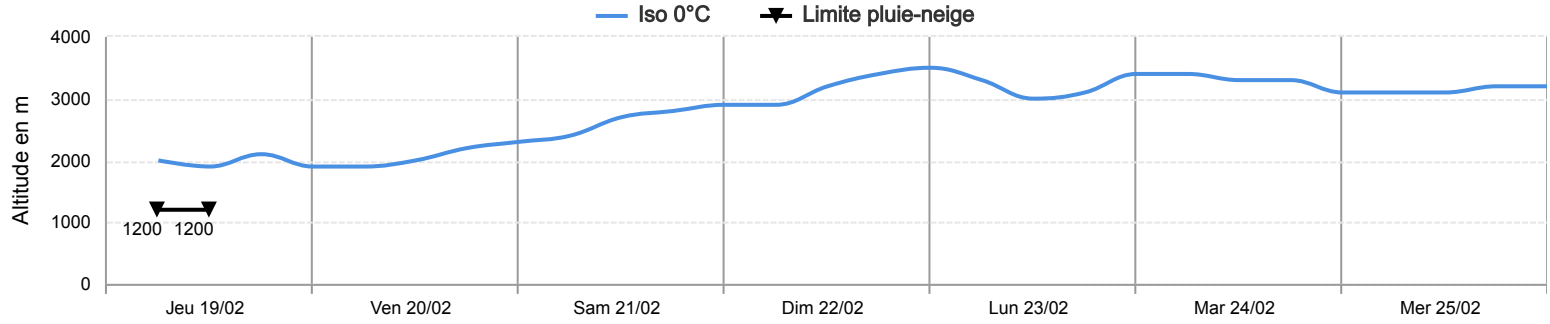

Neige fraîche à 06h

Jeu 19/02	Ven 20/02	Sam 21/02	Dim 22/02	Lun 23/02	Mar 24/02	Mer 25/02
0 cm	0 cm	0 cm	0 cm	0 cm	0 cm	

Risque d'avalanche	jeu. 19/02	ven. 20/02	sam. 21/02	dim. 22/02	lun. 23/02	mar. 24/02	mer. 25/02
	3	3	3	3	3	2	2

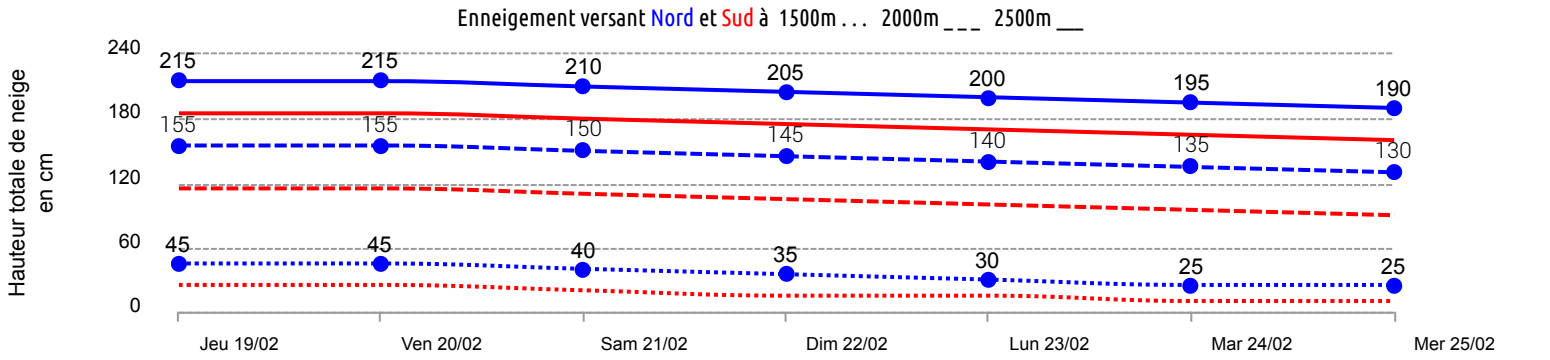

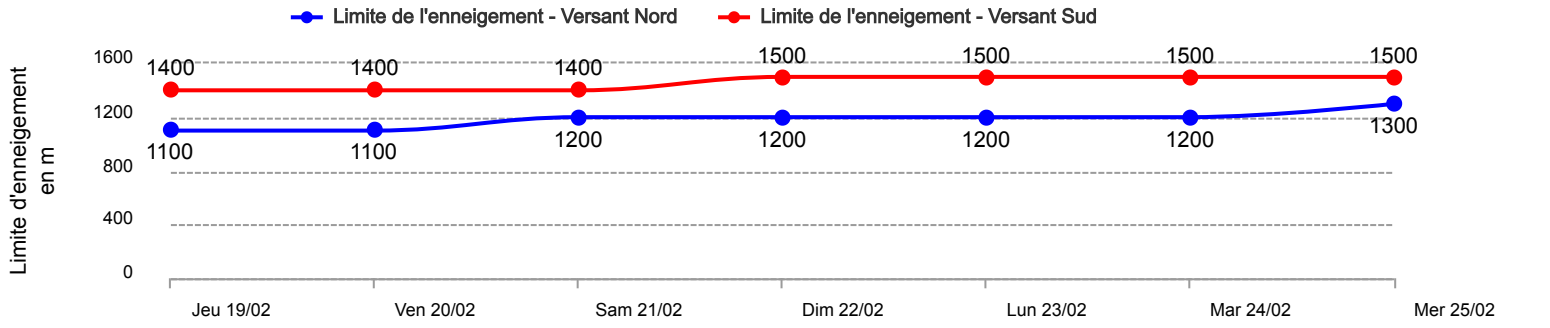

Pour consulter la vigilance en cours, veuillez vous rendre sur le site https://vigilance.meteofrance.fr/fr

Météo-France - 73 avenue de Paris, 94165 Saint-Mandé cedex - Contact : contact@meteo.fr

Rédigé par Météo-France avec la contribution des observateurs du réseau nivo-météorologiques. Partenariat : ANMSM (Maires de Stations de Montagne), DSF (Domaines Skiables de France), ADSP (Directeurs de Pistes et de la Sécurité des Stations de Sports d'Hiver) et autres acteurs de la montagne.

Bulletin neige & avalanches par téléphone au

0 892 68 10 20 Service 0,35 € / min + prix appel