Bulletin d'estimation du risque d'avalanche

(valable en dehors des pistes balisées et ouvertes)

MASSIF : Haute-Tarentaise

Rédigé le mercredi 25 février 2026 à 17h

Estimation des risques pour le : JEUDI 26 FÉVRIER

FORTE ACTIVITE AVALANCHEUSE NATURELLE EN NEIGE HUMIDE (REDOUX). PLAQUES EN ALTITUDE.

3

2 → 3

N O E S

Indice de risque limité évoluant en marqué.

Départs spontanés : forte activité en neige humide et plaque de fond.

Déclenchements provoqués : plaques encore réactives dans les secteurs ventés d'altitude.

Indices de risque : 5 très fort - 4 fort - 3 marqué - 2 limité - 1 faible -- En noir : les pentes les plus dangereuses

Stabilité du manteau neigeux

Situation avalancheuse typique : neige humide — couche fragile persistante

Départs spontanés :
(1) après plusieurs heures au Soleil, **la neige trop humide coule** dans les pentes raides, au départ des barres rocheuses. Dans les versants Est à Ouest en passant par le Sud, l'avalanche peut prendre un **aspect de plaque** (par exemple : déclenchement en cascade) et engendrer une plus grande avalanche, **jusqu'à la taille 3** (grande avalanche). *Situation atypique avec de gros volumes mobilisables et des écoulements qui prennent rapidement de la vitesse.*
(2) des **plaques de fond** dans les pentes raides en herbe ou en dalle rocheuse **à toutes heures et en toutes orientations**, plutôt **sous 2500 m**. Le manteau neigeux actuel étant épais, les volumes mobilisés sont plus conséquents que d'habitude. Moyennes à grandes avalanches possibles (taille 2 à 3).

Déclenchements provoqués : au-dessus de 2000 m, dans les versants Est à Ouest en passant par le Nord, de rares "plaque à vent" subsistent. Elles génèrent des avalanches de taille 1 à 2 (petite à moyenne).
Facteur aggravant : dans ces mêmes versants mais aussi en Sud à haute altitude, des couches fragiles persistantes enfouies sont en place. La probabilité de les solliciter baisse de jour en jour. Toutefois, les pentes les moins enneigées (abords d'une crête ou d'une croupe ventée) semblent les plus propices. Se méfiez aussi des anciennes plaques faiblement recouvertes de neige qui peuvent être facilement redéclenchées (gobelet faiblement enfouie).

Qualité de la neige

Enneigement : grâce aux chutes de neige de mi février, l'enneigement est actuellement excédentaire à toutes altitudes. Les températures anormalement douces engendrent une fonte marquée en Sud de moyenne et basse montagne. La limite d'enneigement dans ces pentes va vite remonter. Ailleurs le manteau se tasse considérablement.

Limite skiable : encore skiable ce mardi dès 1000 m dans les prairies orientées Nord, plutôt 1200 m en Sud pas trop raide.

Qualité de la neige :
En Sud, véritable ski de printemps. Croûte portante au réveil qui ramollie rapidement au soleil.
En Nord, neige croutée souvent non portante jusqu'à 1800/2000 qui chauffe doucement là où elle prend le Soleil. Plus haut, la neige est froide, poudreuse dense à l'abri du vent et très hétérogène entre carton et dure dans les secteurs ventés (à l'approche des crêtes).
En Est et Ouest, la croûte peu portante monte jusqu'en haute montagne. Elle ramollie rapidement au Soleil.

Aperçu météo pour le jeudi 26 février

	nuit	matin	après-midi	soir
Soleil et "canicule hivernale".				
Pluie-Neige				
Iso 0 °C	3 100 m	3 200 m	3 100 m	3 100 m
Vent 2500 m	↓ 5 km/h	↖ 5 km/h	↗ 5 km/h	↖ 5 km/h
Vent 3500 m	↑ 15 km/h	→ 15 km/h	→ 15 km/h	↗ 15 km/h

Épaisseur de neige hors-piste

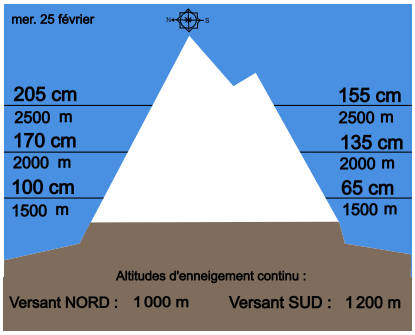

Précipitations à 1800 m

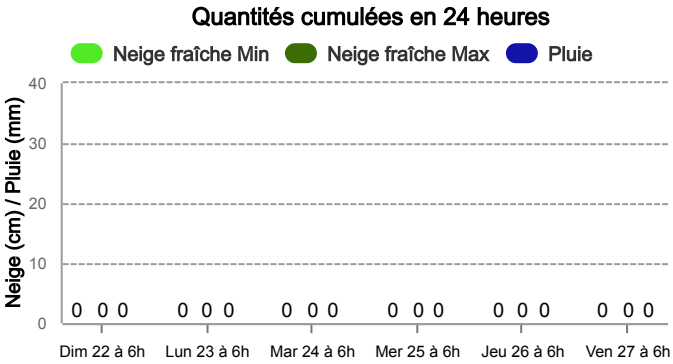

Tendance du vendredi 27 février

3

Indice de risque marqué

Poursuite des conditions excessivement douces et de l'activité avalancheuse naturelle associée. Lente stabilisation des plaques en versants froids.

Pour consulter la vigilance en cours, veuillez vous rendre sur le site https://vigilance.meteofrance.fr/fr

Météo-France - 73 avenue de Paris, 94165 Saint-Mandé cedex - Contact : contact@meteo.fr

Rédigé par Météo-France avec la contribution des observateurs du réseau nivo-météorologiques. Partenariat : ANMSM (Maires de Stations de Montagne), DSF (Domaines Skiables de France), ADSP (Directeurs de Pistes et de la Sécurité des Stations de Sports d'Hiver) et autres acteurs de la montagne.

Bulletin neige & avalanches par téléphone au **0 892 68 10 20** Service 0,35 € / min + prix appel

RÉPUBLIQUE FRANÇAISE
Liberté Égalité Fraternité

METEO FRANCE
À VOS CÔTÉS, DANS UN CLIMAT QUI CHANGE

Bulletin d'estimation du risque d'avalanche

(valable en dehors des pistes balisées et ouvertes)

MASSIF : Haute-Tarentaise

Rédigé le mercredi 25 février 2026 à 17h

Conditions nivo-météo des 7 derniers jours

	jeu. 19/02				ven. 20/02				sam. 21/02				dim. 22/02				lun. 23/02				mar. 24/02				mer. 25/02			
	03h	09h	15h	21h	03h	09h	15h	21h	03h	09h	15h	21h	03h	09h	15h	21h	03h	09h	15h	21h	03h	09h	15h	21h	03h	09h	15h	21h
Météo																												
Vent (km/h)	60	50	60	65	65	55	45	40	50	50	60	60	40	40	50	50	55	45	50	50	50	40	30	25	20	20	20	15
à 3500m																												
Vent (km/h)	50	40	50	55	55	45	35	30	30	35	40	40	20	20	30	30	25	25	25	20	20	15	15	10	5	5	5	5
à 2500m																												

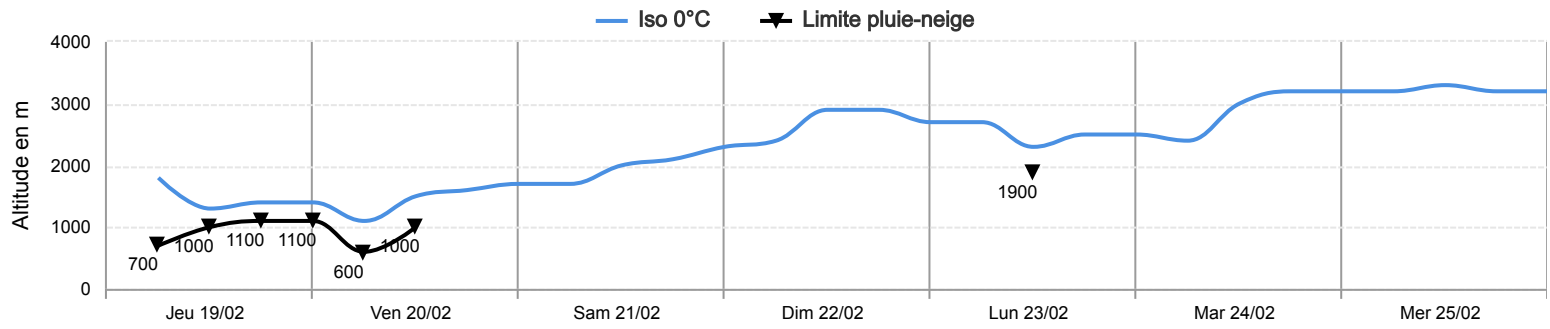

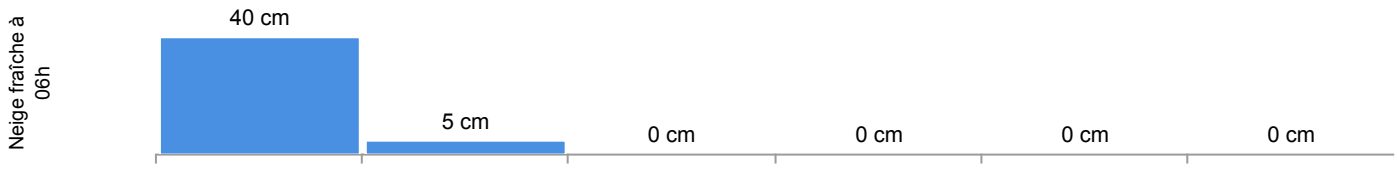

Risque d'avalanche	jeu. 19/02	ven. 20/02	sam. 21/02	dim. 22/02	lun. 23/02	mar. 24/02	mer. 25/02
	5	4	4	3	3	3	3

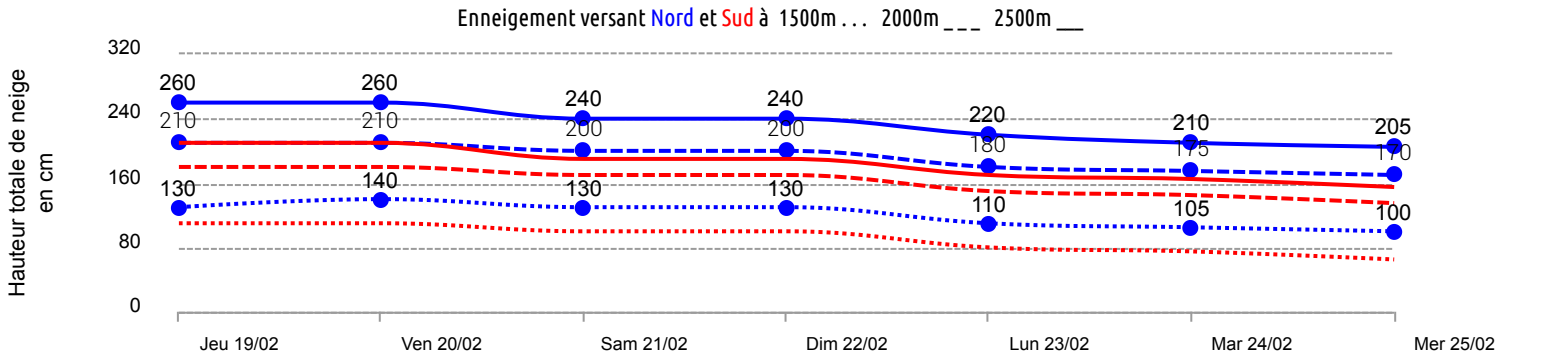

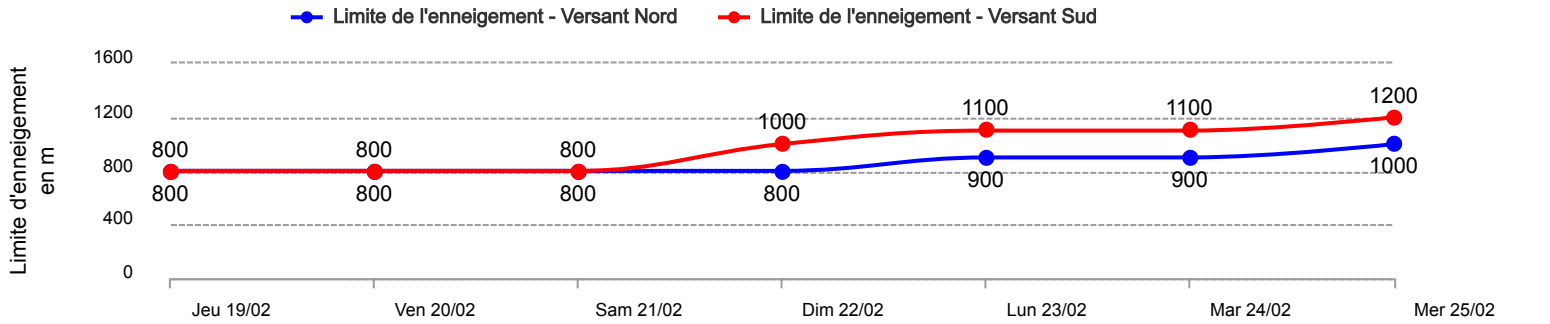

Pour consulter la vigilance en cours, veuillez vous rendre sur le site https://vigilance.meteofrance.fr/fr

Météo-France - 73 avenue de Paris, 94165 Saint-Mandé cedex - Contact : contact@meteo.fr

Rédigé par Météo-France avec la contribution des observateurs du réseau nivo-météorologiques. Partenariat : ANMSM (Maires de Stations de Montagne), DSF (Domaines Skiables de France), ADSP (Directeurs de Pistes et de la Sécurité des Stations de Sports d'Hiver) et autres acteurs de la montagne.

Bulletin neige & avalanches par téléphone au

0 892 68 10 20 Service 0,35 € / min + prix appel