GOBIERNO DE ESPAÑA
VICEPRESIDENCIA TERCERA DEL GOBIERNO
MINISTERIO PARA LA TRANSICIÓN ECOLÓGICA Y EL RETO DEMOGRÁFICO

Boletín de información nivológica y de peligro de aludes

Pirineo Navarro y Aragonés

aemet Agencia Estatal de Meteorología

jueves, 26 de febrero de 2026

Pronóstico hasta las 24 horas del viernes, día 27 de febrero

(Válido fuera de pistas de esquí balizadas y abiertas)

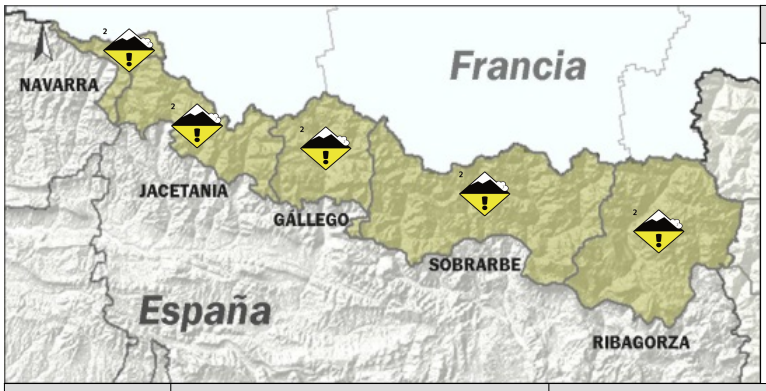

Problemas de aludes

Nieve húmeda

Placas de viento

Macizo	Peligro	Problemas de aludes, cota, orientación, tamaño	Innivación observada (m)
Navarra	2 2 / 1→2 / 2200 Durante el día Limitado	Nieve húmeda Placas de viento	2026-02-26 Cotas bajas
Jacetania	2 2 / 1→2 / 2200 Durante el día Limitado	Nieve húmeda Placas de viento	2026-02-26 Cotas bajas
Gállego	2 2 / 1→2 / 2200 Durante el día Limitado	Nieve húmeda Placas de viento	2026-02-26 Cotas bajas

Boletín de información nivológica y de peligro de aludes

Pirineo Navarro y Aragonés

Sobrarbe	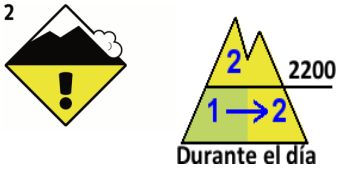 **Limitado**	**Nieve húmeda** 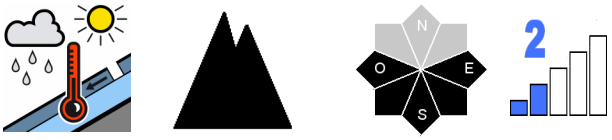 **Placas de viento** 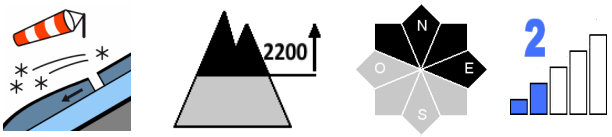	2026-02-26
Ribagorza	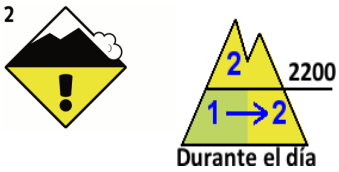 **Limitado**	**Nieve húmeda** **Placas de viento**	2026-02-26

Estado del manto y observaciones recientes

Durante las últimas jornadas, el ambiente templado con temperaturas anormalmente altas y la abundante insolación han propiciado la humidificación y compactación del manto, a razón de algunos centímetros cada día. Con todo, el manto es continuo desde fondos de valle, aunque en las solanas afloran rocas en algunas zonas, y presenta espesores muy por encima de lo que sería habitual a estas alturas de la temporada. En torno a 2100 metros se superan fácilmente los 150-200 cm, aún más en ventisqueros, hoyas y otras zonas propensas a la acumulación.
En cotas medias y bajas el manto se ha humidificado significativamente, y por lo general amanece encostrado, también en solanas a mayor altitud, aunque el calentamiento diurno y la intensa radiación van ablandando las costras durante la mañana. En días pasados hubo mucho trasporte por el viento en cotas altas, por lo que las orientaciones norte y oeste están muy erosionadas. En umbrías manto seco, con costras viejas y placas de viento que no dan actividad estos días, aunque hay algún test de estabilidad que muestra reactividad (no así en el último sondeo realizado hoy en Bachimaña a 2200 m en orientación W). Además, no se descarta que persista alguna capa débil enterrada que pueda seguir latente.
En las últimas 24 horas no se han reportado aludes.

Evolución del manto y peligro de aludes para el viernes, día 27

Problema de nieve húmeda y deslizamientos basales. Problema de capas débiles persistentes y placas de viento en umbrías de cotas altas.

Mañana a primeras horas se podrán formar costras de rehielo que aportarán cierta estabilidad al manto, pero que tenderán a desaparecer en el transcurso de la mañana, debido al calentamiento diurno y a la intensa insolación que se espera. Así, con el avance del día, el manto se hará cada vez más inestable, especialmente en solanas, dando lugar a aludes de nieve húmeda en pendientes suficientemente inclinadas, de dimensión 1 (pequeño, riesgo de

AEMET. Se autoriza la reproducción de su contenido citando la fuente.

caída) ó 2 (mediano, capaz de enterrar a una persona). Cabe destacar que en zonas herbosas o de roca lisa son probables los deslizamientos basales, que podrían movilizar una cantidad de nieve considerable y alcanzar localmente el tamaño 3 (grande, capaz de enterrar un vehículo). Los problemas de nieve húmeda y deslizamientos basales tenderán a remitir al final del día con el descenso térmico y las probables precipitaciones en forma de nieve.
En cotas altas, por encima de 2200 metros, aún podemos encontrar placas de viento, principalmente en umbrías, que aunque tienden a estabilizarse, todavía podrían colapsar ante una sobrecarga fuerte, ocasionando aludes de dimensión 1 ó 2. Además, no se descarta que se pueda fracturar alguna capa débil persistente en profundidad, que en el peor de los casos podría provocar un alud de mayores dimensiones.

Predicción meteorológica para el viernes, día 27

Pirineo navarro:
Poco nuboso o despejado a primeras horas, aumentando posteriormente la nubosidad media y alta desde el oeste, quedando muy nuboso o cubierto por la tarde con nubosidad baja que reducirá localmente la visibilidad.
No se descartan precipitaciones débiles por la tarde, a veces como chubascos, más probables en la divisoria con Francia y al final del día. Cota de nieve bajando de 1900 a 1600 metros. Escasa probabilidad de tormentas.
Temperaturas mínimas sin cambios o en ligero ascenso y máximas sin cambios o en ligero descenso. Heladas débiles en cumbres.
Viento moderado del sur y sudoeste, girando a norte por la tarde y perdiendo intensidad.
Pirineo aragonés:
Poco nuboso o despejado, aumentando a nuboso por la tarde en la Jacetania y divisoria con Francia.
No se descartan precipitaciones débiles por la tarde en la Jacetania y divisoria con Francia, más probables al final del día. Cota de nieve en torno a unos 1800-2000 metros.
Temperaturas sin cambios o con ligero descenso de las máximas. Heladas débiles en la alta montaña y fondos de valle.
Viento flojo de componente sur, tendiendo a dirección variable por la tarde. En cotas altas soplará del oeste girando a sudoeste con intervalos de moderado.

Datos en la atmósfera libre:

Altitud de la isoterma de 0 ºC: 2800 m
Altitud de la isoterma de -10 ºC: 4200 m

Viento a 1500 m: S 10 km/h
Viento a 3000 m: SW 30 km/h

Evolución para el sábado día 28

Nivel de peligro sin cambios o en ligero ascenso.

(Información elaborada a partir de los datos recibidos de los refugios de Linza, Lizara, Panticosa, Bachimaña, Góriz, Pineta, Estós, Angel Orús, Cap de Llauset y Belagua, de las estaciones de esquí de Candanchú, Formigal y Panticosa (lagos) y de la estación de esquí de fondo de Llanos del Hospital)

AEMET. Se autoriza la reproducción de su contenido citando la fuente.

Boletín de información nivológica y de peligro de aludes

Pirineo Navarro y Aragonés

Escala europea de peligro de aludes

Débil | Limitado | Notable | Fuerte | Muy Fuerte

Problemas de aludes

Nieve reciente | Placas de viento | Capas débiles persistentes | Nieve húmeda | Deslizamientos basales | Sin problema evidente

Nota1: Se recuerda que, siempre que haya nieve, la ausencia total de peligro no existe. Hay que tener presente que en circunstancias desfavorables, con aludes de tamaño 1 (alud pequeño o colada) y tamaño 2 (alud mediano), se pueden sufrir severos daños personales.

Nota2: Los BPA se elaboran en base a información meteorológica así como al estado del manto nivoso a través de sondeos puntuales. Se advierte a los usuarios de la variabilidad de esta información al extrapolarla a zonas extensas de montaña. Por ello, AEMET no se hace responsable de su uso para la toma de decisiones que conciernen a la seguridad personal, ni de los riesgos físicos o materiales de ellas derivadas.

AEMET. Se autoriza la reproducción de su contenido citando la fuente.