Freitag 27.02.2026

Veröffentlicht am 26.02.2026 um 17:00

Vormittag

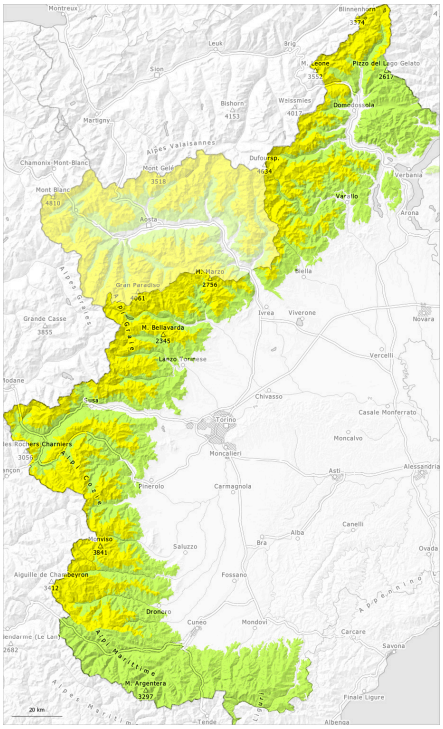

Nachmittag

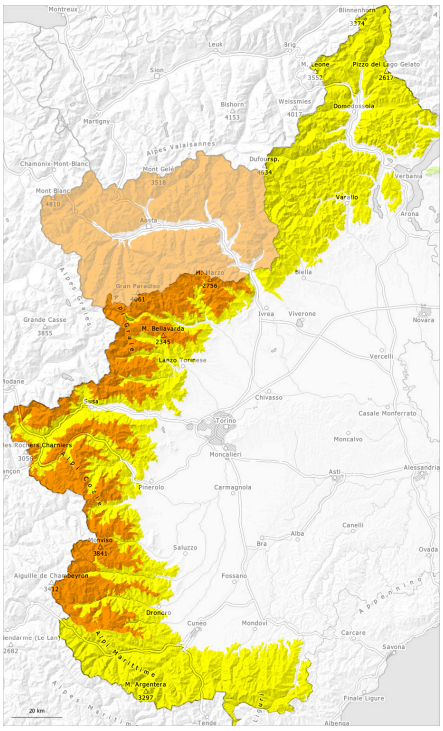

1	2	3	4	5
gering	mäßig	erheblich	groß	sehr groß

Gefahrenstufe 3 - Erheblich

AM:

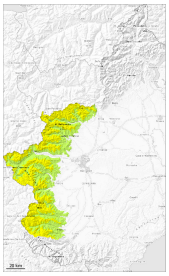

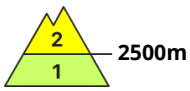

Tendenz: Lawinengefahr bleibt gleich
am Samstag, den 28.02.2026

Altschnee

2500m

PM:

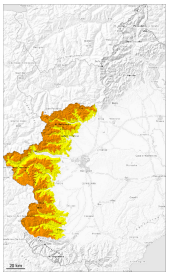

Tendenz: Lawinengefahr bleibt gleich
am Samstag, den 28.02.2026

Nassschnee

2000m

Nassschnee

2000m

Altschnee

2500m

Mit der tageszeitlichen Erwärmung und der Sonneneinstrahlung steigt die Gefahr von feuchten und nassen Lawinen im Tagesverlauf markant an.

An sehr steilen Sonnenhängen und in tiefen und mittleren Lagen sind mit der tageszeitlichen Erwärmung und der Sonneneinstrahlung mittlere und vereinzelt große feuchte und nasse Lawinen möglich, besonders an Felswandfüßen. Feuchte Lawinen können unterhalb von rund 2600 m bis in tiefe Schichten durchreißen und vereinzelt sehr groß werden.
Touren sollten früh gestartet und beendet werden.

Besonders steile Schattenhänge hohe Lagen und Hochgebirge: In der Schneedecke sind einzelne Schwachschichten vorhanden.
Die trockenen Lawinen sind meist mittelgroß und meist mit großer Belastung auslösbar.
Vorsicht vor allem an Übergängen von wenig zu viel Schnee sowie an Felswandfüßen und hinter Geländekanten.

Schneedecke

Gefahrenmuster gm.10: frühjahrssituation

Die Wetterbedingungen erlauben in der Nacht eine deutliche Verfestigung der oberflächennahen

Schneeschichten. Der obere Teil der Schneedecke ist weitgehend stabil, mit einer oft tragfähigen Schmelzharschkruste an der Oberfläche.
Auf der harten Schneeoberfläche besteht im Steilgelände Absturzgefahr.

Sonne und Wärme führen ab dem Morgen vor allem an Sonnenhängen in tiefen und mittleren Lagen zu einer zunehmenden Anfeuchtung der Schneedecke. Die Schneeoberfläche weicht im Tagesverlauf auf.

In windgeschützten Lagen in allen Höhenlagen liegt für die Jahreszeit viel Schnee. In Gipfellagen liegen je nach Windeinfluss sehr unterschiedliche Schneehöhen.
Besonders steile Schattenhänge hohe Lagen und Hochgebirge: Verschiedene Triebschneeschichten liegen stellenweise auf grobkörnigem Altschnee.

Gefahrenstufe 2 - Mäßig

AM:

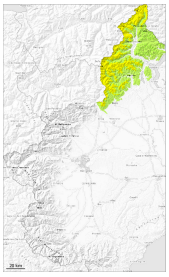

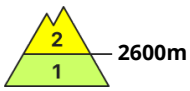

Tendenz: Lawinengefahr bleibt gleich
am Samstag, den 28.02.2026

Altschnee

2600m

PM:

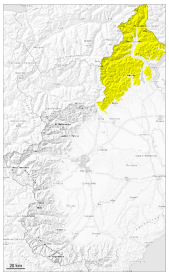

Tendenz: Lawinengefahr bleibt gleich
am Samstag, den 28.02.2026

Nassschnee

Altschnee

2600m

Es ist sonnig. Die Gefahr von feuchten und nassen Lawinen steigt im Tagesverlauf an.

An Sonnenhängen und in tiefen und mittleren Lagen sind mit der tageszeitlichen Erwärmung und der Sonneneinstrahlung mittlere und vereinzelt große feuchte und nasse Lawinen möglich. Feuchte Lawinen können vor allem unterhalb von rund 2500 m bis in tiefe Schichten durchreißen und recht groß werden.

Hohe Lagen und Hochgebirge: Die Wetterbedingungen begünstigten eine deutliche Stabilisierung der Triebschneeansammlungen. Dort sind die Lawinen meist mittelgroß und meist noch mit großer Belastung auslösbar. Vorsicht vor allem an sehr steilen Hängen und in Kammlagen, Rinnen und Mulden.

Touren sollten früh gestartet und beendet werden.

Schneedecke

Gefahrenmuster gm.10: frühjahrssituation gm.2: gleitschnee

In Gipfellagen liegen je nach Windeinfluss sehr unterschiedliche Schneehöhen.

Die Wetterbedingungen erlauben in der Nacht eine deutliche Verfestigung der oberflächennahen Schneeschichten. Der obere Teil der Schneedecke ist weitgehend stabil, mit einer oft tragfähigen Schmelzharschkruste an der Oberfläche. Auf der harten Schneeoberfläche besteht im Steilgelände Absturzgefahr.

Die frühlingshaften Wetterbedingungen führen am Vormittag vor allem an Sonnenhängen unterhalb von rund 2500 m zu einer raschen Anfeuchtung der Schneedecke. Die Schneeoberfläche weicht im Tagesverlauf auf.
Besonders steile Schattenhänge hohe Lagen und Hochgebirge: Verschiedene Triebschneeschichten liegen stellenweise auf grobkörnigem Altschnee.

Gefahrenstufe 2 - Mäßig

AM:

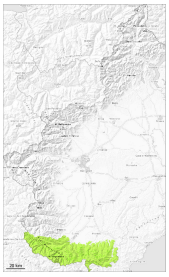

Tendenz: Lawinengefahr bleibt gleich
am Samstag, den 28.02.2026

PM:

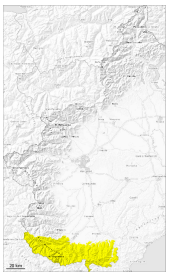

Tendenz: Lawinengefahr bleibt gleich
am Samstag, den 28.02.2026

Nassschnee

Anstieg der Gefahr von feuchten und nassen Lawinen mit der tageszeitlichen Erwärmung.

Vor allem steile Sonnenhänge und Felswandfüße: Mit der tageszeitlichen Erwärmung und der Sonneneinstrahlung sind ab dem Vormittag feuchte und nasse Lawinen möglich, vereinzelt auch große. V.a. an steilen Grashängen sind Gleitschneelawinen und feuchte Rutsche möglich. Zonen mit Gleitschneerissen sollten gemieden werden.

Touren sollten sehr früh gestartet und rechtzeitig beendet werden.

Schneedecke

Gefahrenmuster gm.10: frühjahrssituation | gm.2: gleitschnee

V.a. in Gipfellagen liegen je nach Windeinfluss sehr unterschiedliche Schneehöhen.

Die Schneeoberfläche ist tragfähig gefroren und weicht rasch auf. Auf der eisigen Kruste besteht im Steilgelände Absturzgefahr.
Sonne und Wärme führen am Vormittag vor allem an Sonnenhängen zu einer raschen Anfeuchtung der Schneedecke.