Venerdì 27.02.2026

Pubblicato il 26.02.2026 alle ore 17:00

Mattina

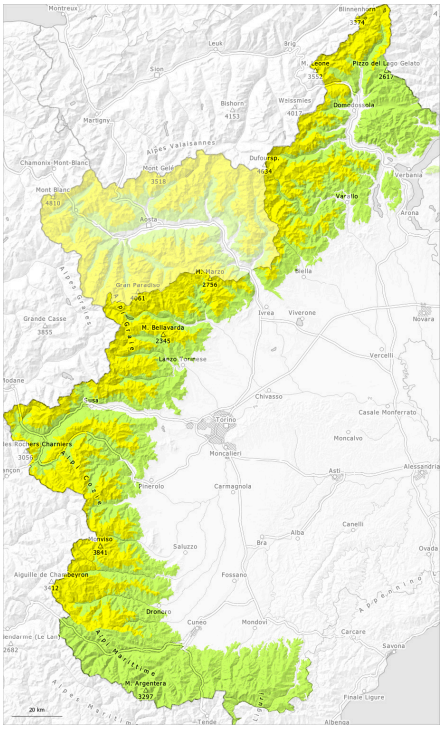

pomeriggio

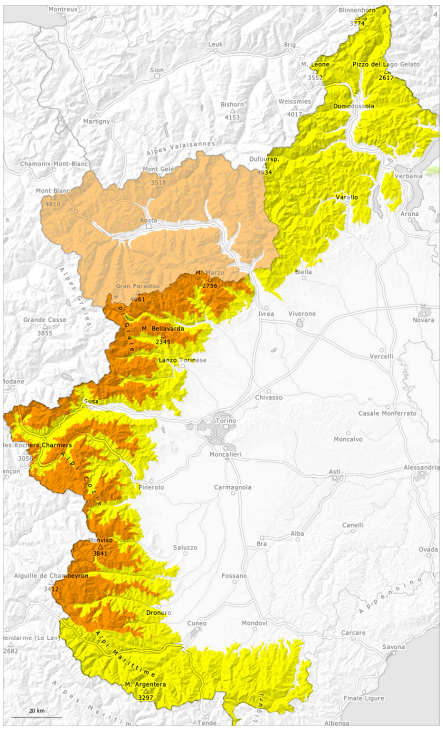

1	2	3	4	5
debole	moderato	marcato	forte	molto forte

Grado di pericolo 3 - Marcato

AM:

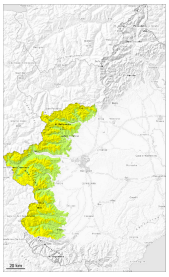

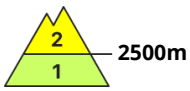

Tendenza: pericolo valanghe stabile
per Sabato il 28.02.2026

Strati deboli persistenti

2500m

PM:

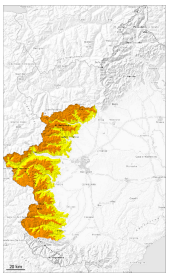

Tendenza: pericolo valanghe stabile
per Sabato il 28.02.2026

Neve bagnata

2000m

Neve bagnata

2000m

Strati deboli persistenti

2500m

Con il rialzo termico e l'irradiazione solare diurni, nel corso della giornata il pericolo di valanghe umide e bagnate aumenterà nettamente.

Con il rialzo termico e l'irradiazione solare diurni, sui pendii soleggiati molto ripidi e alle quote di bassa e media montagna sono possibili valanghe umide e bagnate di medie e, a livello isolato, di grandi dimensioni, soprattutto alle basi di pareti rocciose. Al di sotto dei 2600 m circa le valanghe umide possono coinvolgere gli strati più profondi e, a livello isolato, raggiungere dimensioni molto grandi.
Le escursioni dovrebbero iniziare e terminare presto.

Principalmente sui pendii ripidi ombreggiati ad alta quota e in alta montagna: All'interno del manto nevoso si trovano isolati strati fragili.
Le valanghe asciutte sono per lo più di dimensioni medie e per lo più distaccabili in seguito a un forte sovraccarico.
Attenzione soprattutto nelle zone di passaggio da poca a molta neve, come pure ai piedi di pareti rocciose e dietro ai cambi di pendenza.

Manto nevoso

Situazione tipo st.10: situazione primaverile

Le condizioni meteo consentiranno durante la notte un netto consolidamento degli strati di neve superficiali. La parte superiore del manto nevoso è per lo più stabile, con una crosta da rigelo spesso portante in superficie.
Sulla dura superficie del manto nevoso sussiste un pericolo di caduta nelle zone ripide.

Il sole e il calore causeranno a partire dal mattino soprattutto sui pendii soleggiati alle quote di bassa e media montagna un progressivo inumidimento del manto nevoso. La superficie del manto nevoso si ammorbidirà nel corso della giornata.

Nelle zone riparate dal vento a tutte le altitudini è presente molta più neve rispetto alla media stagionale. In prossimità delle cime l'innevamento è estremamente variabile a seconda dell'azione del vento. Principalmente sui pendii ripidi ombreggiati ad alta quota e in alta montagna: In alcuni punti diversi strati di neve ventata poggiano su un manto di neve vecchia a grani grossi.

Grado di pericolo 2 - Moderato

AM:

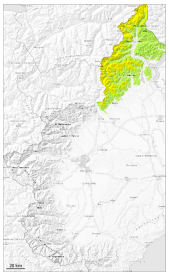

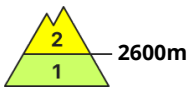

Tendenza: pericolo valanghe stabile
per Sabato il 28.02.2026

Strati deboli persistenti

2600m

PM:

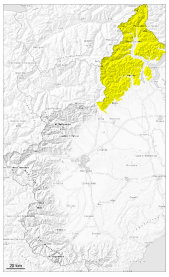

Tendenza: pericolo valanghe stabile
per Sabato il 28.02.2026

Neve bagnata

Strati deboli persistenti

2600m

Il tempo sarà soleggiato. Il pericolo di valanghe umide e bagnate aumenterà nel corso della giornata.

Con il rialzo termico e l'irradiazione solare diurni, sui pendii soleggiati e alle quote di bassa e media montagna sono possibili valanghe umide e bagnate di medie e, a livello isolato, di grandi dimensioni. Soprattutto al di sotto dei 2500 m circa le valanghe umide possono coinvolgere gli strati più profondi e raggiungere dimensioni piuttosto grandi.

Ad alta quota e in alta montagna: Le condizioni meteo hanno favorito una netta stabilizzazione degli accumuli di neve ventata. Qui le valanghe sono per lo più di dimensioni medie e per lo più ancora distaccabili in seguito a un forte sovraccarico. Attenzione soprattutto sui pendii molto ripidi e nelle zone in prossimità delle creste, nelle conche e nei canaloni.

Le escursioni dovrebbero iniziare e terminare presto.

Manto nevoso

Situazione tipo st.10: situazione primaverile | st.2: neve da slittamento

In prossimità delle cime l'innevamento è estremamente variabile a seconda dell'azione del vento.

Le condizioni meteo consentiranno durante la notte un netto consolidamento degli strati di neve

superficiali. La parte superiore del manto nevoso è per lo più stabile, con una crosta da rigelo spesso portante in superficie. Sulla dura superficie del manto nevoso sussiste un pericolo di caduta nelle zone ripide.

Durante la mattinata le condizioni meteo primaverili causeranno soprattutto sui pendii soleggiati al di sotto dei 2500 m circa un rapido inumidimento del manto nevoso. La superficie del manto nevoso si ammorbidirà nel corso della giornata.
Principalmente sui pendii ripidi ombreggiati ad alta quota e in alta montagna: In alcuni punti diversi strati di neve ventata poggiano su un manto di neve vecchia a grani grossi.

Grado di pericolo 2 - Moderato

AM:

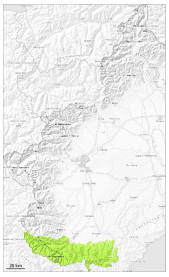

Tendenza: pericolo valanghe stabile
per Sabato il 28.02.2026

PM:

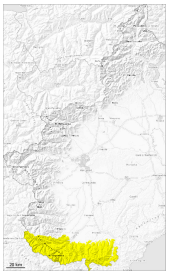

Tendenza: pericolo valanghe stabile
per Sabato il 28.02.2026

Neve bagnata

Con il rialzo termico diurno, aumento del pericolo di valanghe umide e bagnate.

Soprattutto sui pendii ripidi esposti al sole e alle basi di pareti rocciose: Con il rialzo termico e l'irradiazione solare diurni, a partire dalla mattinata sono possibili valanghe umide e bagnate, a livello isolato anche di grandi dimensioni. Specialmente sui pendii erbosi ripidi, sono possibili valanghe per scivolamento di neve e colate umide. Evitare le zone con rotture da scivolamento.

Le escursioni dovrebbero iniziare e terminare in tempo.

Manto nevoso

Situazione tipo st.10: situazione primaverile | st.2: neve da slittamento

Specialmente in prossimità delle cime l'innevamento è estremamente variabile a seconda dell'azione del vento.

La superficie del manto nevoso si è rigelata ed è portante e si ammorbidirà rapidamente. Sulla crosta ghiacciata sussiste un pericolo di caduta nelle zone ripide.
Il sole e il calore causeranno in mattinata soprattutto sui pendii soleggiati un rapido inumidimento del manto nevoso.