Venerdì 27.02.2026

Pubblicato il 26.02.2026 alle ore 17:00

Mattina

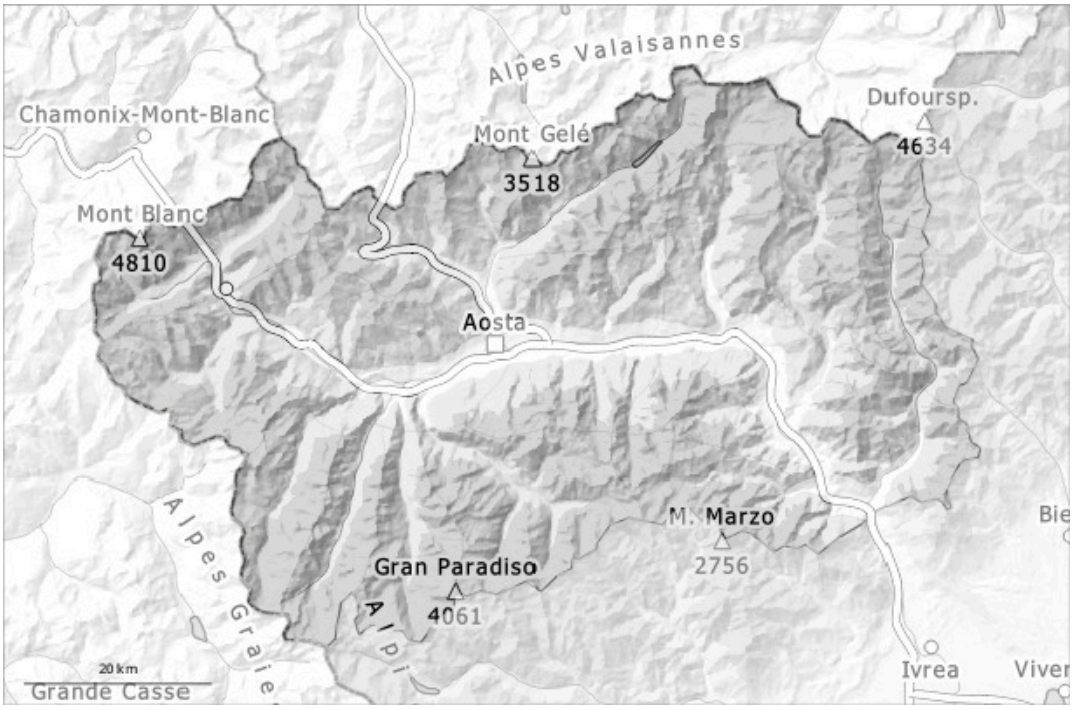

pomeriggio

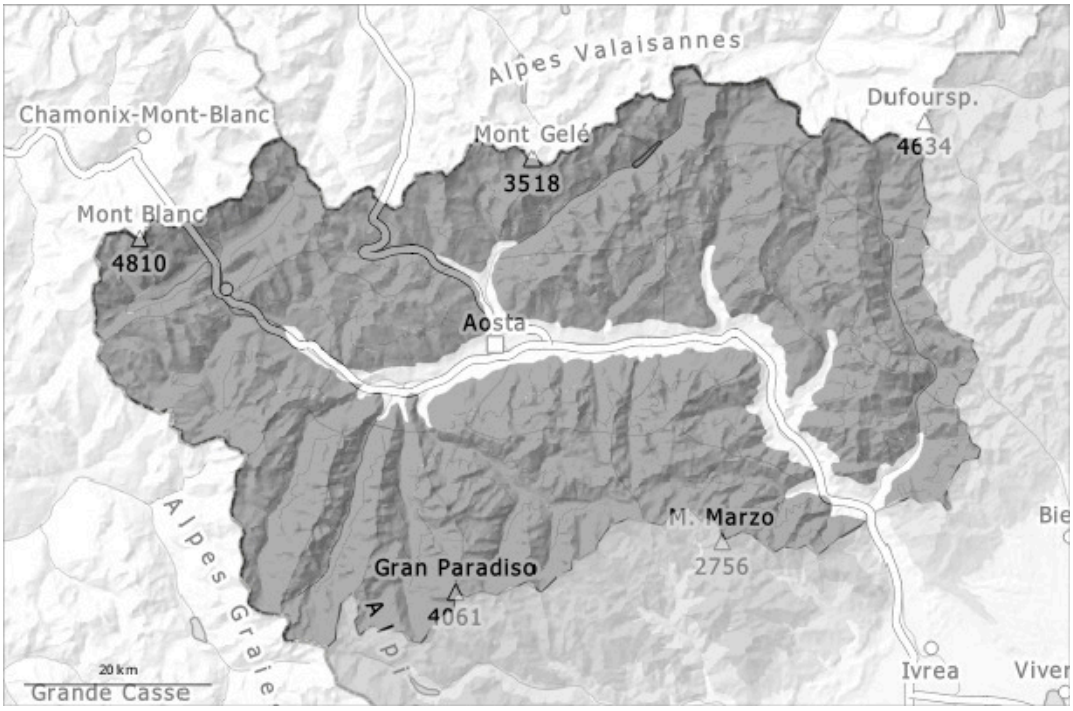

1	2	3	4	5
debole	moderato	marcato	forte	molto forte

Grado di pericolo 3 - Marcato

AM:

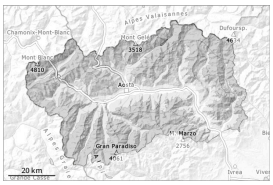

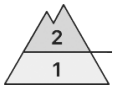

2300m

Tendenza: pericolo valanghe in diminuzione
per Sabato il 28.02.2026

Strati deboli persistenti

2300m

PM:

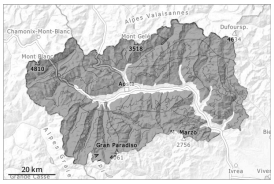

Tendenza: pericolo valanghe in diminuzione
per Sabato il 28.02.2026

Neve bagnata

Strati deboli persistenti

Soprattutto sui pendii molto ripidi esposti al sole alle basi di pareti rocciose: Il pericolo di valanghe umide e bagnate aumenterà già durante la mattinata.

La superficie del manto nevoso riuscirà a rigelarsi e a essere portante e si ammorbidirà nel corso della giornata.
Soprattutto sui pendii molto ripidi esposti al sole e alle basi di pareti rocciose: Con il rialzo termico e l'irradiazione solare diurni, sono ancora previste valanghe bagnate nel corso della giornata di dimensioni medio-grandi.
Al di sotto dei 2600 m circa le valanghe umide possono coinvolgere gli strati più profondi, anche sui pendii erbosi molto ripidi.
Le escursioni dovrebbero iniziare e terminare presto.

Nella parte centrale del manto nevoso si trovano isolati strati fragili. Inoltre gli accumuli di neve ventata delle ultime settimane sono a livello isolato ancora instabili. Essi sono ben individuabili e possono subire un distacco per lo più solo in seguito a un forte sovraccarico, attenzione soprattutto nelle zone di passaggio da poca a molta neve come p.es. all'ingresso di conche e canaloni. Specialmente qui le valanghe possono coinvolgere la neve vecchia e raggiungere dimensioni piuttosto grandi.

Manto nevoso

Situazione tipo st.10: situazione primaverile | st.1: strato debole persistente basale

L'irraggiamento notturno sarà buono. La superficie del manto nevoso riuscirà a rigelarsi e a essere portante e si ammorbidirà nel corso della giornata. A partire dalla mattinata le condizioni meteo primaverili causeranno soprattutto sui pendii soleggiati ripidi al di sotto dei 3000 m circa un progressivo inumidimento del manto nevoso.
Le condizioni meteo hanno favorito una stabilizzazione degli accumuli di neve ventata soprattutto sui pendii soleggiati.
La parte centrale del manto nevoso ha una stratificazione sfavorevole.
Nelle zone in prossimità delle creste e dei passi l'innevamento è estremamente variabile a seconda dell'azione del vento. In cresta sono presenti grosse cornici.
Negli ultimi giorni sono cadute molte valanghe umide di dimensioni medio-grandi.

Tendenza

Il pericolo di valanghe bagnate spontanee diminuirà progressivamente.