Freitag 27.02.2026

Veröffentlicht am 26.02.2026 um 17:00

Vormittag

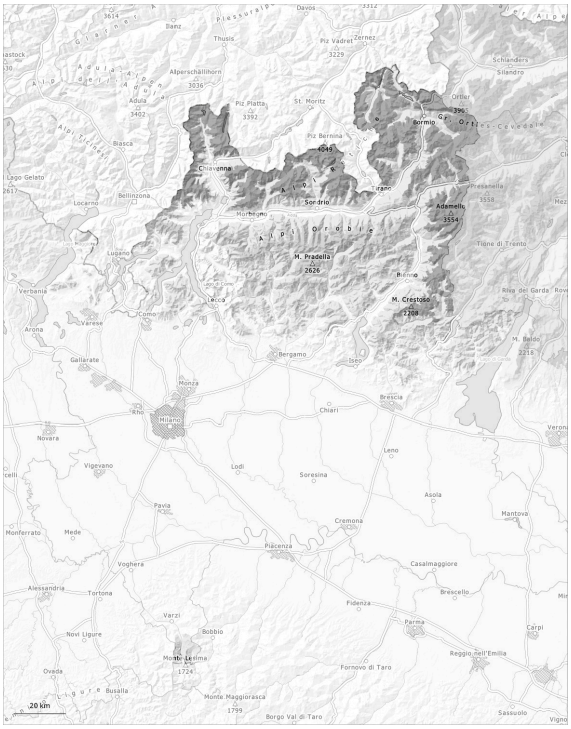
Davos
Piz Vadret
3229
Zernez
Thusis
Alpe
Schlanders
Silandro
Alpe Bella
Alpe Adula
Alpe Adula
Alpe Lepontina
Alpe Lepontina
Alpe Lepontina

Gefahrenstufe 3 - Erheblich

AM:

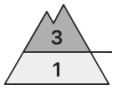

Waldgrenze

Tendenz: Lawinengefahr bleibt gleich
am Samstag, den 28.02.2026

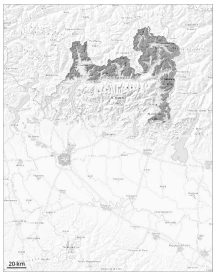

Triebschnee

Waldgrenze

Altschnee

Waldgrenze

Nassschnee

2000m

PM:

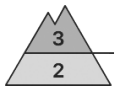

2000m

Tendenz: Lawinengefahr bleibt gleich
am Samstag, den 28.02.2026

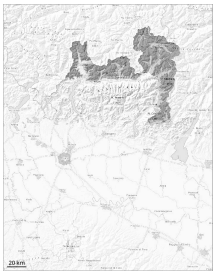

Nassschnee

2000m

Triebschnee

Waldgrenze

Altschnee

Waldgrenze

Die Schneedecke ist oberhalb von rund 1800 m störanfällig. Triebschnee und schwacher Altschnee sind die Hauptgefahr. Schwachschichten im Altschnee erfordern eine defensive Routenwahl.
Mit der tageszeitlichen Erwärmung steigt die Auslösebereitschaft von feuchten Lawinen an Südhängen unterhalb von rund 2500 m an.

Vorsicht vor Triebschnee. Schwachschichten im Altschnee können schon von einzelnen Wintersportlern leicht ausgelöst werden, besonders an steilen West-, Nord- und Osthängen in hohen Lagen und im Hochgebirge. Lawinen können bis auf den Boden durchreißen und groß werden. Die Gefahrenstellen sind häufig für Anfänger kaum zu erkennen.
Wummgeräusche und Risse beim Betreten der Schneedecke sind Alarmzeichen und weisen auf die Gefahr

hin.
Mit der tageszeitlichen Erwärmung steigt die Auslösebereitschaft von feuchten und nassen Lawinen an Südhängen unterhalb von rund 2500 m an.

Schneedecke

Gefahrenmuster gm.4: kalt auf warm / warm auf kalt gm.1: bodennahe schwachschicht

Der untere Teil der Schneedecke ist kantig aufgebaut und schwach. Lawinen können auch in tieferen Schichten ausgelöst werden.
Zudem sind die frischen Triebschneeansammlungen in Kammlagen, Rinnen und Mulden leicht auslösbar.

Tendenz

Mit der tageszeitlichen Erwärmung nimmt die Anzahl der Gefahrenstellen im Tagesverlauf zu.

Gefahrenstufe 2 - Mäßig

AM:

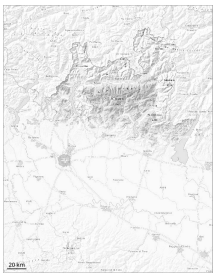

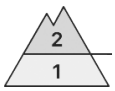

1500m

Tendenz: Lawinengefahr bleibt gleich
am Samstag, den 28.02.2026

Triebschnee

1500m

Nassschnee

1000m

PM:

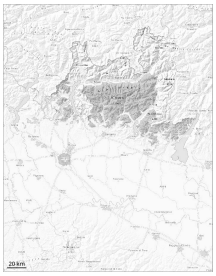

Tendenz: Lawinengefahr bleibt gleich
am Samstag, den 28.02.2026

Triebschnee

1500m

Nassschnee

1000m

Die Triebschneeansammlungen können vor allem an steilen Schattenhängen stellenweise leicht ausgelöst werden. Schwachschichten im Altschnee erfordern Vorsicht und Zurückhaltung.
Mit der Erwärmung sind kleine und mittlere feuchte Lawinen zu erwarten.

Trockene Lawinen können auch in tieferen Schichten ausgelöst werden.
Mit der tageszeitlichen Erwärmung steigt die Auslösebereitschaft von feuchten und nassen Lawinen an Südhängen unterhalb von rund 2500 m an.

Schneedecke

Gefahrenmuster gm.6: lockerer schnee und wind | gm.10: frühjahrssituation

In der Altschneedecke sind vor allem an steilen Nordwest-, Nord- und Nordosthängen heikle Schwachschichten vorhanden.

Tendenz

Mit der tageszeitlichen Erwärmung nimmt die Anzahl der Gefahrenstellen im Tagesverlauf zu.

Gefahrenstufe 1 - Gering

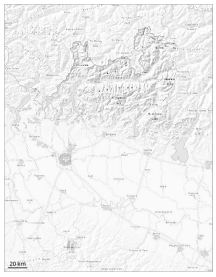

Tendenz: Lawinengefahr bleibt gleich
am Samstag, den 28.02.2026

Nassschnee

Waldgrenze

Error: Incomplete joker sentence

Schneedecke

Gefahrenmuster gm.10: frühjahrssituation