Venerdì 27.02.2026

Pubblicato il 26.02.2026 alle ore 17:00

Mattina

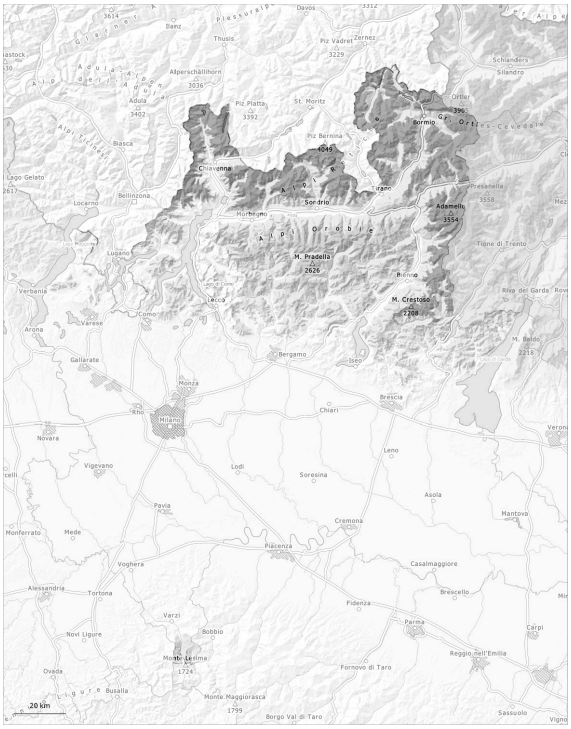
Davos
Piz Vadret
3229
Zernez
Thusis
Alpe
Schlanders
Silandro
Alpe Bella
Alpe Adona
Alpe Gera
Alpe Cavaglia
Alpe Livigno
Alpe Sassella
Alpe Ortler
Alpe Cevedale
Alpe Orobie
Alpe Lepontine
Alpe Pennine
Alpe Lepontine
Alpe Pennine
Alpe Lepontine
Alpe Pennine

Grado di pericolo 3 - Marcato

AM:

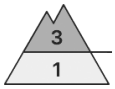

Limite del bosco

Tendenza: pericolo valanghe stabile
per Sabato il 28.02.2026

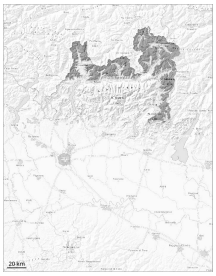

Lastrone da vento

Limite del bosco

Strati deboli persistenti

Limite del bosco

Neve bagnata

2000m

PM:

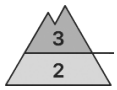

2000m

Tendenza: pericolo valanghe stabile
per Sabato il 28.02.2026

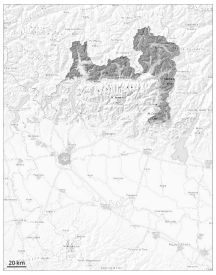

Neve bagnata

2000m

Lastrone da vento

Limite del bosco

Strati deboli persistenti

Limite del bosco

Il manto nevoso è instabile al di sopra dei circa 1800 m. Neve ventata e neve vecchia a debole coesione sono la principale fonte di pericolo. Gli strati deboli presenti nella neve vecchia richiedono una prudente scelta dell'itinerario.
Con il rialzo termico diurno, la probabilità di distacco di valanghe umide aumenterà sui pendii esposti a sud al di sotto dei 2500 m circa.

Attenzione alla neve ventata. Gli strati deboli presenti nella neve vecchia possono distaccarsi facilmente già

in seguito al passaggio di un singolo appassionato di sport invernali, soprattutto sui pendii ripidi esposti a ovest, nord ed est ad alta quota e in alta montagna. Le valanghe possono trascinare l'interno manto nevoso e raggiungere grandi dimensioni. I punti pericolosi sono frequenti difficilmente individuabili da parte del principiante.
I rumori di "whum" e la formazione di fessure quando si calpesta la coltre di neve sono campanelli di allarme che rimandano a questo pericolo.
Con il rialzo termico diurno, la probabilità di distacco di valanghe umide e bagnate aumenterà sui pendii esposti a sud al di sotto dei 2500 m circa.

Manto nevoso

Situazione tipo st.4: freddo su caldo / caldo su freddo st.1: strato debole persistente basale

La parte basale del manto nevoso ha subito un metamorfismo costruttivo a cristalli sfaccettati ed è debole. Le valanghe possono subire un distacco anche negli strati più profondi del manto nevoso.
Inoltre nelle zone in prossimità delle creste, nelle conche e nei canaloni gli accumuli di neve ventata di più recente formazione possono facilmente subire un distacco.

Tendenza

Con il rialzo termico diurno, nel corso della giornata il numero dei punti pericolosi aumenterà.

Grado di pericolo 2 - Moderato

AM:

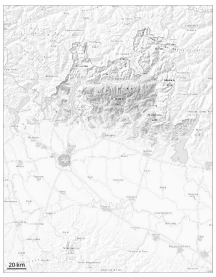

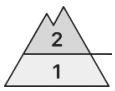

1500m

Tendenza: pericolo valanghe stabile
per Sabato il 28.02.2026

Lastrone da vento

1500m

Neve bagnata

1000m

PM:

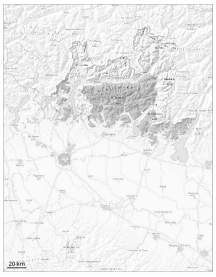

Tendenza: pericolo valanghe stabile
per Sabato il 28.02.2026

Lastrone da vento

1500m

Neve bagnata

1000m

Gli accumuli di neve ventata in alcuni punti possono facilmente subire un distacco soprattutto sui pendii ripidi ombreggiati. Gli strati deboli presenti nella neve vecchia richiedono attenzione e prudenza.
Con il rialzo termico, sono previste valanghe umide di piccole e medie dimensioni.

Le valanghe asciutte possono subire un distacco anche negli strati più profondi del manto nevoso.
Con il rialzo termico diurno, la probabilità di distacco di valanghe umide e bagnate aumenterà sui pendii esposti a sud al di sotto dei 2500 m circa.

Manto nevoso

Situazione tipo st.6: neve a debole coesione e vento | st.10: situazione primaverile

Soprattutto sui pendii ripidi esposti a nord ovest, nord e nord est, all'interno del manto di neve vecchia si trovano insidiosi strati fragili.

Tendenza

> Con il rialzo termico diurno, nel corso della giornata il numero dei punti pericolosi aumenterà.

Grado di pericolo 1 - Debole

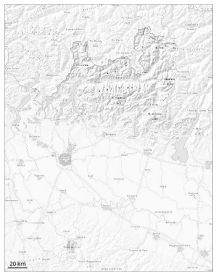

Tendenza: pericolo valanghe stabile
per Sabato il 28.02.2026

Neve bagnata

Limite del bosco

Situazione primaverile. Manto nevoso di esiguo spessore.

Manto nevoso

Situazione tipo st.10: situazione primaverile