ICGC Institut Cartogràfic i Geològic de Catalunya

Servei Meteorològic de Catalunya meteo.cat

Boletín de peligro de aludes para el Pirineo de Catalunya
Del 26/02/2026 al 27/02/2026

(Válido fuera pistas de esquí y zonas no controladas)

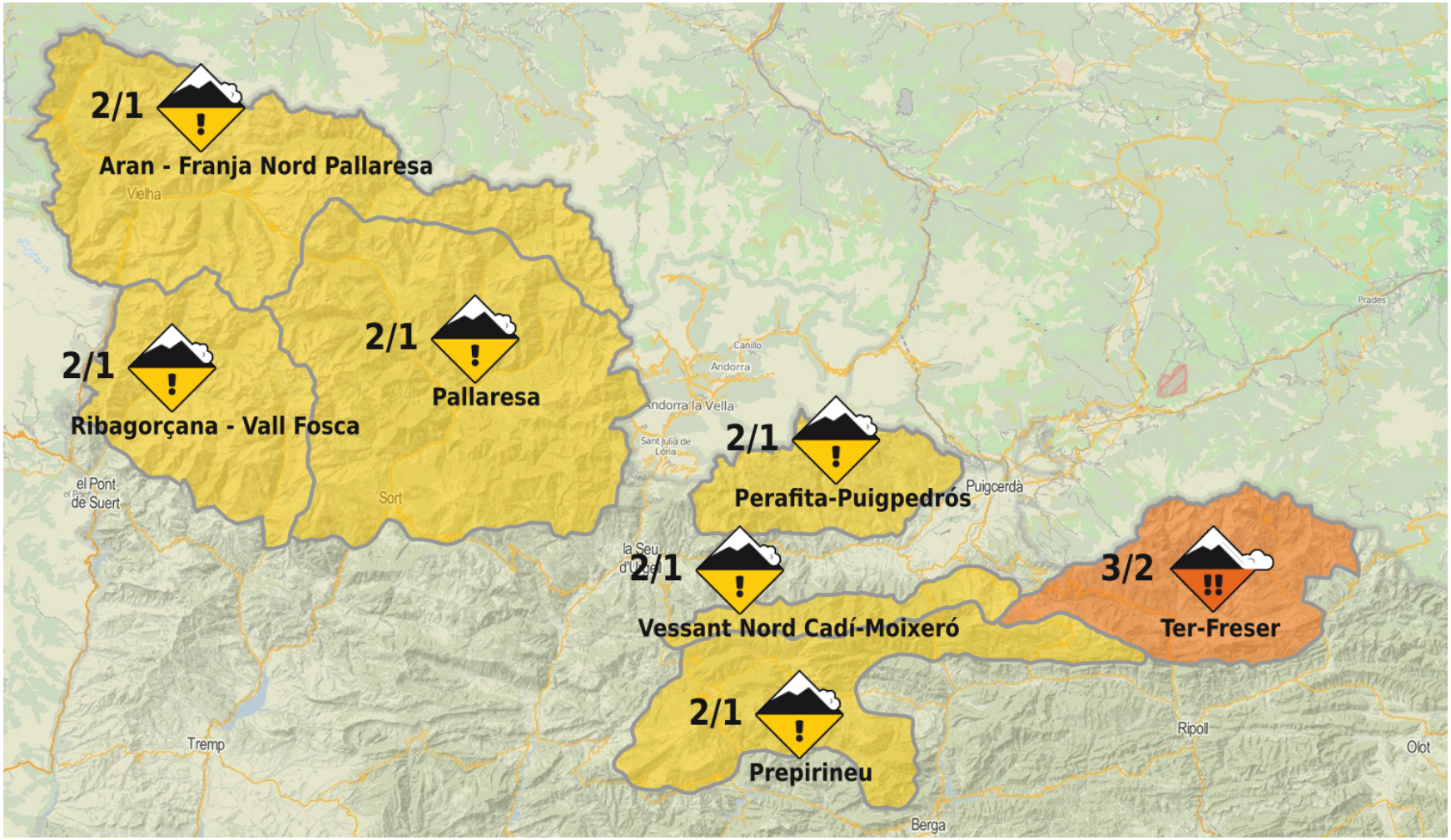

5 MUY FUERTE	4 FUERTE	3 NOTABLE	2 LIMITADO	1 DÉBIL

ICGC Institut Cartogràfic i Geològic de Catalunya

Servei Meteorològic de Catalunya

Boletín de peligro de aludes Aran - Franja Nord Pallaresa Del 26/02/2026 al 27/02/2026

(Válido fuera pistas de esquí y zonas no controladas)

LIMITADO (2) por encima del límite de bosque, DÉBIL (1) por debajo, hasta mediodía.

Situación primaria

Deslizamientos basales | **Distribución** | **Tamaño** | **Origen** | **Tendencia**

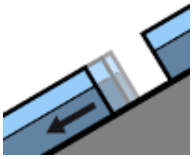

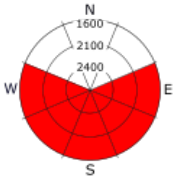

Situación secundaria

Capas débiles persistentes | **Distribución** | **Tamaño** | **Origen** | **Tendencia**

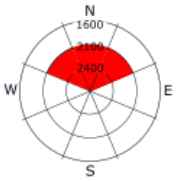

Estado del manto nivoso

Continúa la actividad de deslizamientos basales en el sector, de tamaño 2 o incluso 3, con capacidad para enterrar a un grupo de personas. De forma ocasional también hay purgas nieve húmeda. La elevada temperatura e insolación diurnas humedecen el manto, especialmente a partir de mediodía y en solanas. A primeras horas de la mañana podemos encontrar el manto encostrado en estas orientaciones. Se espera que continúen los deslizamientos basales y las purgas superficiales húmedas, más frecuentes en terreno soleado y de fuerte pendiente y en momentos de máxima insolación. Se recomienda evitar el terreno donde aparezcan grietas hasta el suelo, ya que indican que la totalidad del manto puede deslizarse. En umbrías por encima de 2.200 m encontramos placas de viento antiguas y locales sobre niveles de facetas; en muchos casos se encuentran bien consolidadas, pero localmente podrían romper y dar lugar a aludes de tamaño 1, por lo general por sobrecarga fuerte.

Distribución del manto nivoso

Hay nieve por encima de unos 1.400 m a umbrías y 1.600 m a solanas. Los espesores a unos 2.200 m son superiores a los normales y rondan los 120-140 cm en el norte de Aran y los 160-200 cm en la Franja Norte Pallaresa y en el sur de Aran, puntualmente superiores.

Tendencia para las próximas 48-72h

De cara al sábado se espera un cambio de patrón, con formación de nuevas placas en laderas umbrías y pérdida de protagonismo del humedecimiento superficial. Aún podrán haber deslizamientos. Peligro EN LEVE AUMENTO.

El próximo boletín será emitido el día 2026-02-27

5 MUY FUERTE	4 FUERTE	3 NOTABLE	2 LIMITADO	1 DÉBIL

EAWS EUROPEAN AVALANCHE WARNING SERVICES

ICGC Institut Cartogràfic i Geològic de Catalunya

Servei Meteorològic de Catalunya

Boletín de peligro de aludes Ribagorçana - Vall Fosca Del 26/02/2026 al 27/02/2026

(Válido fuera pistas de esquí y zonas no controladas)

LIMITADO (2) durante las horas de máxima insolación. DÉBIL (1) el resto.

Situación primaria

Deslizamientos basales

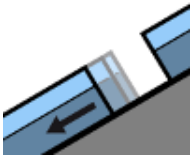

Distribución

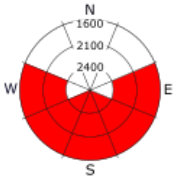

Tamaño

Origen

Tendencia

Situación secundaria

Capas débiles persistentes

Distribución

Tamaño

Origen

Tendencia

Estado del manto nivoso

El manto presenta un comportamiento típicamente primaveral, con la superficie endurecida a primera hora por rehielo, y que se ablanda a este sur y oeste con el paso de las horas. Las últimas jornadas no hay actividad de aludes de nieve húmeda superficiales, aunque no pueden descartarse a lo largo de la jornada. Sin embargo, son probables caídas de deslizamientos basales de tamaño 2, suficiente para enterrar a una persona, o incluso mayor. Se desprenden de terreno soleado, de fuerte pendiente, liso y herboso o rocoso, o bajo paredes rocosas. Se debe evitar el terreno bajo grietas, ya que pueden indicar condiciones de deslizamiento del manto sobre el suelo. En umbrías, en cota alta, todavía se pueden encontrar placas antiguas que descansan sobre niveles de nieve facetada, poco reactivas en general, pero que todavía pueden ceder por sobrecargas y generar aludes de pequeño tamaño.

Distribución del manto nivoso

Hay nieve en el suelo a 1.500 m en terreno umbrío, y por encima de unos 1.700-1800 m en laderas soleadas. El manto es esquiable por encima de unos 1.600 m en umbrías. Los espesores alcanzan los 120-150 cm en cotas medias. Estos valores son superiores a los normales para la época.

Tendencia para las próximas 48-72h

Tenderán a remitir el humedecimiento diurno, pero se podrán formar nuevas placas de viento a lo largo de la jornada. Peligro EN LEVE AUMENTO.

El próximo boletín será emitido el día 2026-02-27

5 MUY FUERTE	4 FUERTE	3 NOTABLE	2 LIMITADO	1 DÉBIL

EAWS EUROPEAN AVALANCHE WARNING SERVICES

ICGC Institut Cartogràfic i Geològic de Catalunya

Servei Meteorològic de Catalunya

Boletín de peligro de aludes Pallaresa
Del 26/02/2026 al 27/02/2026

(Válido fuera pistas de esquí y zonas no controladas)

LIMITADO (2) durante las horas de máxima insolación. DÉBIL (1) el resto.

Situación primaria

Deslizamientos basales | **Distribución** | **Tamaño** | **Origen** | **Tendencia**

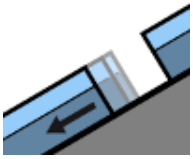

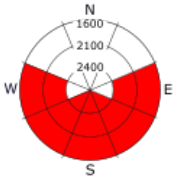

Situación secundaria

Capas débiles persistentes | **Distribución** | **Tamaño** | **Origen** | **Tendencia**

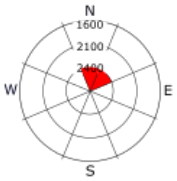

Estado del manto nivoso

El manto presenta un comportamiento típicamente primaveral, con la superficie endurecida a primera hora por rehielo, y que se ablanda a este sur y oeste con el paso de las horas. Las últimas jornadas no hay actividad de aludes de nieve húmeda superficiales, aunque no pueden descartarse a lo largo de la jornada. Sin embargo, son probables caídas de deslizamientos basales de tamaño 2, suficiente para enterrar a una persona, o incluso mayor. Se desprenden de terreno soleado, de fuerte pendiente, liso y herboso o rocoso, o bajo paredes rocosas. Se debe evitar el terreno bajo grietas, ya que pueden indicar condiciones de deslizamiento del manto sobre el suelo. En umbrías, en cota alta, todavía se pueden encontrar placas antiguas que descansan sobre niveles de nieve facetada, poco reactivas en general, pero que todavía pueden ceder por sobrecargas y generar aludes de pequeño tamaño.

Distribución del manto nivoso

Hay nieve en el suelo a 1.500 m en terreno umbrío, esquiable por encima de unos 1.600 m; en orientaciones soleadas la nieve está presente por encima de unos 1.700-1.800 m. Los espesores alcanzan los 110-150 cm en cotas medias. Estos valores son superiores a los normales para la época.

Tendencia para las próximas 48-72h

Tenderán a remitir el humedecimiento diurno, pero se podrán formar nuevas placas de viento a lo largo de la jornada. Peligro EN LEVE AUMENTO.

El próximo boletín será emitido el día 2026-02-27

5 MUY FUERTE	4 FUERTE	3 NOTABLE	2 LIMITADO	1 DÉBIL

EAWS EUROPEAN AVALANCHE WARNING SERVICES

ICGC Institut Cartogràfic i Geològic de Catalunya

Servei Meteorològic de Catalunya

Boletín de peligro de aludes Perafita-Puigpedrós Del 26/02/2026 al 27/02/2026

(Válido fuera pistas de esquí y zonas no controladas)

LIMITADO (2) durante las horas centrales del día, DÉBIL (1) el resto

Situación primaria

Deslizamientos basales **Distribución** **Tamaño** **Origen** **Tendencia**

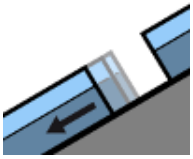

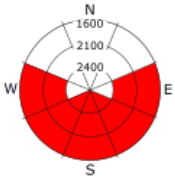

Situación secundaria

Capas débiles persistentes **Distribución** **Tamaño** **Origen** **Tendencia**

Estado del manto nivoso

El manto presenta un comportamiento típicamente primaveral, con la superficie endurecida a primera hora por rehielo, y que se ablanda a este sur y oeste con el paso de las horas. Las últimas jornadas no hay actividad de aludes de nieve húmeda superficiales, aunque no pueden descartarse a lo largo de la jornada. Sin embargo, son probables caídas de deslizamientos basales de tamaño 2, suficiente para enterrar a una persona, o incluso mayor. Se desprenden de terreno soleado, de fuerte pendiente, liso y herboso o rocoso, o bajo paredes rocosas. Se debe evitar el terreno bajo grietas, ya que pueden indicar condiciones de deslizamiento del manto sobre el suelo. En umbrías, en cota alta, todavía se pueden encontrar placas antiguas que descansan sobre niveles de nieve facetada, poco reactivas en general, pero que todavía pueden ceder por sobrecargas y generar aludes de pequeño tamaño.

Distribución del manto nivoso

Hay nieve en el suelo por encima de unos 1.600 m, aunque en las solanas más derechas el manto va retranqueando y la nieve está presente por encima de 1.800 m. Los espesores, aunque irregulares, rondan los 70-110 cm en cotas medias, con frecuentes deflaciones en orientaciones norte y oeste por encima del nivel del bosque. Son grosores muy por encima de los habituales por la época.

Tendencia para las próximas 48-72h

Podrá aumentar el peligro con las nevadas y el viento esperado. La situación de nieve húmeda va a perder protagonismo. Peligro EN LEVE AUMENTO.

El próximo boletín será emitido el día 2026-02-27

5 MUY FUERTE	4 FUERTE	3 NOTABLE	2 LIMITADO	1 DÉBIL

EAWS EUROPEAN AVALANCHE WARNING SERVICES

ICGC Institut Cartogràfic i Geològic de Catalunya

Servei Meteorològic de Catalunya meteo.cat

Boletín de peligro de aludes Vessant Nord Cadí-Moixeró Del 26/02/2026 al 27/02/2026

(Válido fuera pistas de esquí y zonas no controladas)

LIMITADO (2) a mediodía, DÉBIL (1) el resto

Situación primaria

Capas débiles persistentes

Distribución

Tamaño

Origen

Tendencia

Situación secundaria

Deslizamientos basales

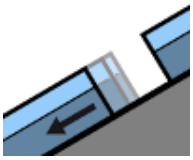

Distribución

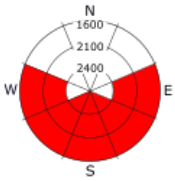

Tamaño

Origen

Tendencia

Estado del manto nivoso

Pese a las elevadas temperaturas y la insolación en las últimas jornadas no ha habido mucha actividad de aludes de nieve húmeda en el sector, y se espera que el viernes tampoco haya actividad significativa. Sin embargo, son probables caídas de deslizamientos basales de tamaño 2, suficiente para enterrar a una persona, o incluso mayor. Se desprenden de terreno soleado, de fuerte pendiente, liso y herboso o rocoso, o bajo paredes rocosas. Se debe evitar el terreno bajo grietas, ya que pueden indicar condiciones de deslizamiento del manto sobre el suelo. En las umbrías de cota alta todavía podemos encontrar pequeñas placas locales que por sobrecarga puedan ceder y generar aludes de pequeño tamaño.

Distribución del manto nivoso

En umbrías hay nieve por encima de 1.500 m, esquiable por encima de unos 1.700 m. En solanas la nieve está presente por encima de 1.700 m. Los espesores están alrededor de 130-160 cm en cotas medias. Estos valores son excedentarios para la época del año.

Tendencia para las próximas 48-72h

El peligro aumentará por la formación de nuevas placas de viento en orientaciones umbrías. Perlejo EN AUMENTO.

El próximo boletín será emitido el día 2026-02-27

5 MUY FUERTE	4 FUERTE	3 NOTABLE	2 LIMITADO	1 DÉBIL

EAWS EUROPEAN AVALANCHE WARNING SERVICES

ICGC Institut Cartogràfic i Geològic de Catalunya

Servei Meteorològic de Catalunya

Boletín de peligro de aludes Prepirineu
Del 26/02/2026 al 27/02/2026

(Válido fuera pistas de esquí y zonas no controladas)

LIMITADO (2) durante las horas centrales del día, DÉBIL (1) el resto

Situación primaria

Deslizamientos basales **Distribución** **Tamaño** **Origen** **Tendencia**

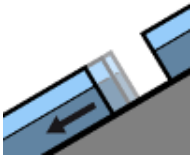

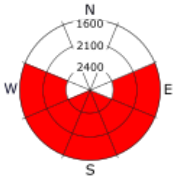

Situación secundaria

Nieve húmeda **Distribución** **Tamaño** **Origen** **Tendencia**

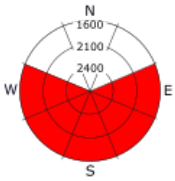

Estado del manto nivoso

El manto se presenta endurecido por rehielo a primera hora, especialmente hasta 2.300 m ya que por encima podría quedar alguna capa de nieve vieja sin encostar. Con el paso de las horas, con la insolación y las temperaturas elevadas, el manto humedecerá superficialmente. Son probables caídas de deslizamientos basales de tamaño 2, suficiente para enterrar a una persona, o incluso mayor. Se desprenden de terreno soleado, de fuerte pendiente, liso y herboso o rocoso, o bajo paredes rocosas. Se debe evitar el terreno bajo grietas, ya que pueden indicar condiciones de deslizamiento del manto sobre el suelo. También son posibles aludes de nieve húmeda, especialmente en orientaciones este, sur y oeste, en forma de caída de bolas, purgas y aludes pequeños, que pueden producirse hasta cota alta, en laderas soleadas de fuerte pendiente preferentemente. No se descarta puntualmente algún deslizamiento basal sobre sustrato liso o herboso.

Distribución del manto nivoso

Hay nieve desde 1.500 a 1600 m esquiable a partir de unos 1.700 m en orientaciones umbrías. En solanas el manto está presente a partir de unos 1.700-1.800 m. Los grosores están alrededor de 100-120 cm a unos 2.200 my son superiores a los habituales. Aparecen deflaciones por encima del nivel del bosque, sobre todo en lugares bien expuestos al viento de norte y oeste.

Tendencia para las próximas 48-72h

La situación de nieve húmeda tenderá a remitir con la bajada de temperatura prevista pero no se descarta la formación de alguna placa local por las nevadas previstas. Peligro ESTACIONARIO.

El próximo boletín será emitido el día 2026-02-27

5 MUY FUERTE	4 FUERTE	3 NOTABLE	2 LIMITADO	1 DÉBIL

EAWS EUROPEAN AVALANCHE WARNING SERVICES

ICGC Institut Cartogràfic i Geològic de Catalunya

meteo.cat Servei Meteorològic de Catalunya

Boletín de peligro de aludes Ter-Freser
Del 26/02/2026 al 27/02/2026

(Válido fuera pistas de esquí y zonas no controladas)

NOTABLE (3) durante las horas diurnas. LIMITADO (2) el resto.

Situación primaria

Deslizamientos basales | **Distribución** | **Tamaño** | **Origen** | **Tendencia**

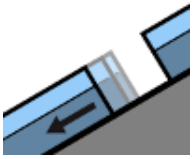

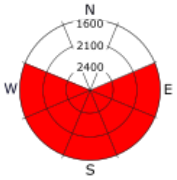

Situación secundaria

Nieve húmeda | **Distribución** | **Tamaño** | **Origen** | **Tendencia**

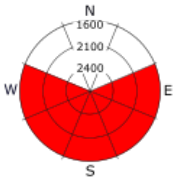

Estado del manto nivoso

En las últimas jornadas se ha registrado varios deslizamientos basales de tamaño grande e incluso muy grande (suficiente para llegar a fondo de valle y recorrer más de 50 m en terreno llano), así como purgas superficiales de nieve húmeda. Fuera de las orientaciones más umbrías el manto se encuentra humedecido en todo su espesor debido a la insolación, las temperaturas elevadas y las ocasionales nieblas. Aún son probables deslizamientos basales con aludes que podrían llegar a tamaño 3 o localmente 4. Tendrán lugar en laderas empinadas y herbosas, o bajo resaltes rocosos. Habrá que prestar atención con la aparición de grietas hasta el suelo y evitar terreno similar a donde se hayan detectado estos aludes. Podrá haber purgas, o incluso algún alud de tamaño 2 (suficiente para enterrar a una persona) muy local fuera del terreno más umbrío. Tendrán lugar en laderas de fuerte inclinación que todavía no hayan purgado.

Distribución del manto nivoso

El manto nivoso presenta grosores muy excedentarios para la época del año. En lugares no afectados por el viento, los espesores oscilan entre 80-100 cm a unos 2.000 m, siendo esquiable a partir de unos 1.600 m. Aparecen deflaciones por encima del nivel del bosque, sobre todo en lugares bien expuestos al viento de norte y oeste.

Tendencia para las próximas 48-72h

Los deslizamientos aún podrán ser los protagonistas el sábado, con ausencia de rehielo matinal. A lo largo del día, bajará la temperatura y se podrán formar placas locales de viento. Peligro ESTACIONARIO.

El próximo boletín será emitido el día 2026-02-27

5 MUY FUERTE	4 FUERTE	3 NOTABLE	2 LIMITADO	1 DÉBIL

EAWS EUROPEAN AVALANCHE WARNING SERVICES