BUTLLETÍ DEL PERILL D'ALLAUS DEL PRINCIPAT D'ANDORRA

Elaborado el 26/02/2026 16:00
Proxima actualización 27/02/2026 a las 16h

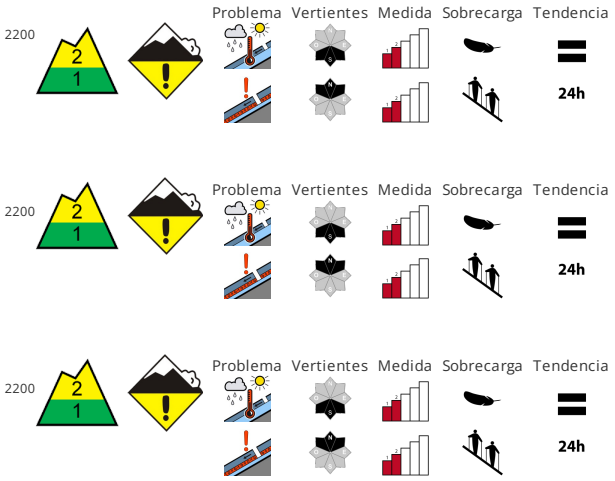

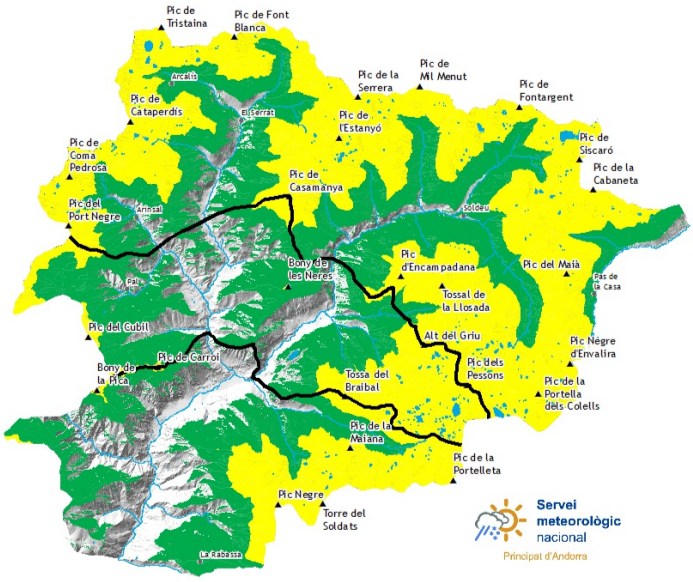

CALIDAD DE LA NIEVE

Luego de una noche serena, por la mañana las condiciones de aludes son favorables en muchos sectores. Todavía en las laderas muy inclinadas orientadas a norte en la parte central del manto de nieve hay capas débiles. Estos pueden de manera aislada ser desencadenadas con una sobrecarga fuerte y alcanzar un tamaño mediano. Se recomienda mantener la distancia de seguridad entre los miembros del grupo. A partir del mediodía la probabilidad de desencadenamiento de aludes de nieve húmeda aumentará claramente sobre todo en las laderas solanas inclinadas. Esto se da especialmente en la base de las paredes rocosas, y en terreno pendiente y escarpado. Además son posibles aludes de deslizamiento basal en cualquier momento. Debido a la costra dura hay el peligro de resbalar y caer en las laderas inclinadas.

ESTABILIDAD DEL MANTO NIVOSO

Las condiciones son primaverales. El enfriamiento nocturno será bueno. La superficie del manto de nieve se volverá a helar para formar una costra portante y se ablandará durante el día. Esto se da en las laderas inclinadas orientadas a sudeste, sur y sudoeste. Los espesores de nieve varían mucho por encima de los 2500 m aproximadamente por la influencia del viento. Evitar las zonas con grietas de deslizamiento basal.

ESPESORES DEL MANTO NIVOSO FUERA DE PISTA

Zona norte		Espesor nieve		
Manto Nival		1500m	2000m	2500m
N	1400 m	30 cm	150 cm	200 cm
S	1800 m	0 cm	100 cm	150 cm

zona centro		Espesor nieve		
Manto Nival		1500m	2000m	2500m
N	1400 m	20 cm	150 cm	200 cm
S	1800 m	0 cm	100 cm	150 cm

Zona sur		Espesor nieve		
Manto Nival		1500m	2000m	2500m
N	1400 m	20 cm	120 cm	150 cm
S	1800 m	0 cm	60 cm	100 cm

Govern d'Andorra

EAWS EUROPEAN AVALANCHE WARNING SERVICES

Aquest butlletí ha estat elaborat seguint les normes i recomanacions de l'**European Avalanche Warning Services**, del qual el **Servei meteorològic Nacional** n'és membre

Información detallada por espacios naturales protegidos

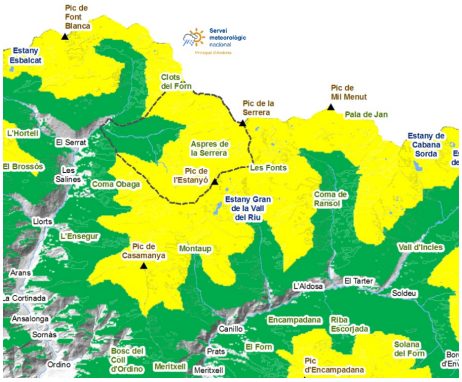

SORTENY

Encontramos nieve en todos los caminos desde Llorts y el acceso en esquís hasta el Refugio se puede hacer como hacía años que no se veía durante tantas semanas seguidas. Por encima del estanque, en las laderas norte encontramos capas débiles persistentes escondidas bajo la nieve polvo. Estas capas débiles persistentes podrían desencadenar aludes de placa medias que podrían crear cortes de nieve o cicatrices importantes que podrían tener consecuencias graves. Por tanto, aunque este tipo de estabilidad sólo la tenemos identificada en las vertientes más inclinadas, por encima de 2.400 metros y orientadas a norte (umbrías), debemos tenerla en cuenta para escoger nuestro itinerario con seguridad.

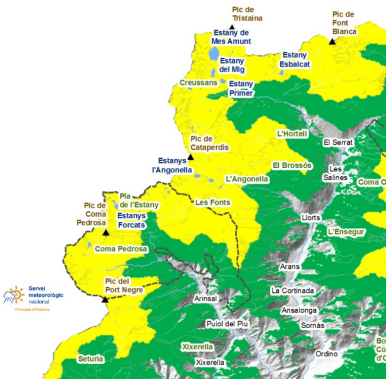

COMAPEDROSA

En cotas bajas la nieve se ha compactado y ha reducido su grosor debido a la humidificación. Deberemos vigilar a no resbalar debido a la corteza de rehielo. La distribución de la nieve es muy irregular a causa del viento. En las vertientes norte más inclinadas deberemos circular con precaución y manteniendo la distancia de seguridad para evitar activar las capas débiles persistentes.

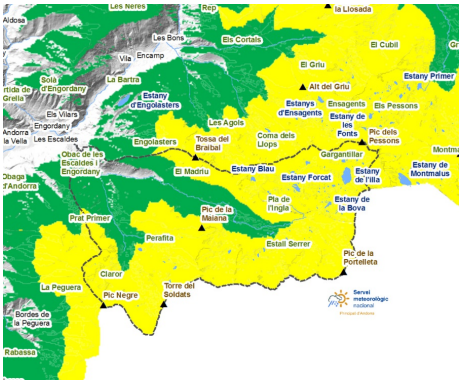

MADRIU-PERAFITA-CLAROR

En las vertientes sur y en cotas bajas las condiciones son primaverales, nieve dura por la mañana y blanda al mediodía, con formas típicas de fusión cuando el sol incide perpendicularmente a la pendiente. En las vertientes norte y en los lugares planos la nieve se mantiene polvo.

BUTLLETÍ DEL PERILL D'ALLAUS DEL PRINCIPAT D'ANDORRA

Servei meteorològic nacional
Principat d'Andorra

Espesores de nieve nueva de los últimos días (de las ultimas 24h mesurado a las 06:00h UTC)

	22/02/2026	23/02/2026	24/02/2026	25/02/2026
FEDA (Central)	0 cm	0 cm	0 cm	0 cm
Engolasters - FEDA	0 cm	0 cm	0 cm	0 cm
Ransol - FEDA	0 cm	0 cm	0 cm	0 cm
Fontverd	0 cm	0 cm	0 cm	0 cm
Setúria	0 cm	0 cm	0 cm	0 cm
Bony de les Neres	0 cm	0 cm	0 cm	0 cm
Grau Roig - FEDA	0 cm	0 cm	0 cm	0 cm
Caborreu	0 cm	0 cm	0 cm	0 cm
Sorteny	0 cm	0 cm	0 cm	0 cm
Perafita	0 cm	0 cm	0 cm	0 cm
Tossa Espiolets	0 cm	0 cm	0 cm	0 cm
La Solana	0 cm	0 cm	0 cm	0 cm
Vall del Riu FEDA	0 cm	0 cm	0 cm	0 cm
Envalira Antenes	0 cm	0 cm	0 cm	0 cm