MINISTERO DELLA DIFESA

meteomont Servizio Nazionale di previsione neve e valanghe

EAWS EUROPEAN AVALANCHE WARNING SERVICES

CARABINIERI

In collaborazione con: arpav

DOLOMITI SETTENTRIONALI

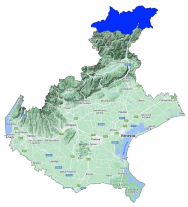

Bollettino Valanghe N. 357/2026 del 26/02/2026 ore 14.00
Validità 48 ore prossima emissione 27/02/2026
A cura del Servizio METEOMONT dell'ARMA dei CARABINIERI
In collaborazione con Servizio Meteorologico dell'Aeronautica militare

SITUAZIONE alle 14:00 del 26/02/2026

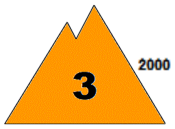

SITUAZIONE TIPO: passaggio da poca a molta neve.



SITUAZIONE TIPO: situazione primaverile.

Quota neve (mslm)	Nord	Sud
	900 - 1400	1400 - 1500

Altezza Neve (cm)	Neve al suolo	Neve Fresca	Quota (mslm)
	080	00	2119
	58	00	1759

VALANGHE OSSERVATE: Nessuna valanga.

PREVISIONI 27/02/2026

GRADO DI PERICOLO: MARCATO 3

SITUAZIONE TIPO: passaggio da poca a molta neve.

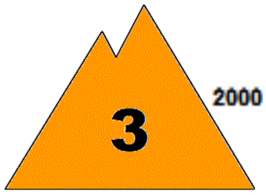



SITUAZIONE TIPO: situazione primaverile.

MANTO NEVOSO: La stabilità del manto nevoso è molto scarsa su alcuni punti (aree) per versanti da ovest a est al di sopra di 2000 mslm, possibili valanghe di dimensioni medie.
La stabilità del manto nevoso è molto scarsa su alcuni punti (aree) per versanti da est a ovest al di sotto di 2000 mslm, possibili valanghe di dimensioni medie.

AVVERTENZE

Il rialzo termico diurno richiede un'attenta valutazione temporale dell'escursione che eviti l'attraversamento di pendii ripidi nelle ore più calde della giornata.

SCALA EUROPEA DEL GRADO DI PERICOLO VALANGHE

LEGENDA PROBLEMA

Bollettino realizzato su scala sinottica-regionale (standard EAWS). La sua valutazione non può escludere in alcun modo la necessità di una seria e capace valutazione locale del pericolo (singolo pendio) che può essere anche sensibilmente diverso. Le previsioni meteorologiche sono relative all'orario UTC (per l'Italia +1 in inverno e +2 in estate).

MINISTERO DELLA DIFESA

meteomont
Servizio Nazionale di previsione neve e valanghe

EAWS EUROPEAN AVALANCHE WARNING SERVICES

CARABINIERI

In collaborazione con: arpav

DOLOMITI SETTENTRIONALI

PREVISIONE METEO

Quota		27/02/2026 h6:00	27/02/2026 h12:00	27/02/2026 h18:00
1000	Venti	01 Nodi da N-Est	00 Calma	01 Nodi da S-Est
	Temperature	+06 °C	+06 °C	+06 °C
	Temp.percepita	6 °C	6 °C	6 °C
2000	Venti	00 Calma	00 Calma	01 Nodi da Est
	Temperature	+05 °C	+05 °C	+05 °C
	Temp.percepita	5 °C	5 °C	5 °C
3000	Venti	02 Nodi da S-Ovest	01 Nodi da S-Ovest	02 Nodi da Sud
	Temperature	+00 °C	+00 °C	+01 °C
	Temp.percepita	0 °C	0 °C	1 °C
Zero termico		2700-2900 m.	2900-3100 m.	3000-3200 m.
Fenomeno		—	—	—
Stato del cielo				

LEGENDA FENOMENI

— Assenza Fenomeni · Nebbia · Foschia · Pioggia debole · Pioggia moderata · Pioggia forte · Temporali

Nevicata debole · Nevicata moderata · Nevicata forte

STATO DEL CIELO

Sereno · Poco nuvoloso · Nuvoloso · Molto nuvoloso · Coperto

Parametri meteonivometrici registrati presso i campi di rilevamento il 26/02/2026.

Località	Comune	Quota (m.s.l.m.)	Altezza neve (cm)	Neve caduta nelle 24 ore (cm)	Temp. Min (°C)	Temp. Max (°C)	Condizioni del tempo
MISURINA	Auronzo di Cadore (BL)	1759	58	0	-6	+20	Assenza di precipitazioni
MONTE AGUDO	Auronzo di Cadore (BL)	1530	70	0	-1	+9	Assenza di precipitazioni
MONTE FALORIA	Cortina d'Ampezzo (BL)	2119	80	0	0	+19	Assenza di precipitazioni
COL DELLA TENDA	Comelico Superiore (BL)	1930	84	0	-1	+16	Assenza di precipitazioni
FORCELLA RINBIANCO *	Auronzo di Cadore (BL)	2263	103	0	N.P.	N.P.	Assenza di precipitazioni
LA VALLAZZA *	Chies d'Alpago (BL)	2080	135	0	N.P.	N.P.	Assenza di precipitazioni

(*) Rilievi fuori campo

L'INFORMAZIONE E' PREVENZIONE - LEGGI L'ATTUALE GRADO DI PERICOLO VALANGHE!

IL CAPO DEL CENTRO NAZIONALE METEOMONT
(Ten. Col. RFI Emanuela Gini)
FIRMA AUTOGRAFA OMESSA AI SENSI
DELL'ART.3 DEL D.LGS N.39/1993

Bollettino realizzato su scala sinottica-regionale (standard EAWS). La sua valutazione non può escludere in alcun modo la necessità di una seria e capace valutazione locale del pericolo (singolo pendio) che può essere anche sensibilmente diverso. Le previsioni meteorologiche sono relative all'orario UTC (per l'Italia +1 in inverno e +2 in estate).