MINISTERO DELLA DIFESA

meteomont
Servizio Nazionale di previsione neve e valanghe

EAWS EUROPEAN AVALANCHE WARNING SERVICES

CARABINIERI

AERONAUTICA MILITARE SERVIZIO METEOROLOGICO

# ALPI RETICHE

Bollettino Valanghe N. 359/2026 del 26/02/2026 ore 14.00
Validità 48 ore prossima emissione 27/02/2026

**A cura del Servizio METEOMONT dell'ARMA dei CARABINIERI**
**In collaborazione con Servizio Meteorologico dell'Aeronautica militare**

## SITUAZIONE alle 14:00 del 26/02/2026

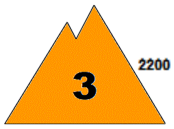


**SITUAZIONE TIPO: passaggio da poca a molta neve.**




**SITUAZIONE TIPO: situazione primaverile.**

| Quota neve (mslm) | Nord | Sud |
|---|---|---|
| | 1200 - 1400 | 1400 - 1600 |

| Altezza Neve (cm) | Neve al suolo | Neve Fresca | Quota (mslm) |
|---|---|---|---|
| | 59 | 0 | 2582 |
| | 53 | 0 | 1640 |

**VALANGHE OSSERVATE: Alcune valanghe di grandi dimensioni, Valanghe a lastroni di fondo.**

## PREVISIONI 27/02/2026

# GRADO DI PERICOLO: MARCATO 3

## SITUAZIONE TIPO: passaggio da poca a molta neve.

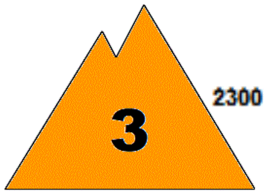





## SITUAZIONE TIPO: situazione primaverile.

**MANTO NEVOSO: La stabilità del manto nevoso è molto scarsa su alcuni punti (aree) per versanti da ovest a est al di sopra di 2300 mslm, possibili valanghe di dimensioni medie.**
**La stabilità del manto nevoso è scarsa su molti punti (aree) per versanti al sole al di sotto di 2300 mslm, possibili valanghe di dimensioni medie.**

## AVVERTENZE

Il rialzo termico diurno richiede un'attenta valutazione temporale dell'escursione che eviti l'attraversamento di pendii ripidi nelle ore più calde della giornata.

## SCALA EUROPEA DEL GRADO DI PERICOLO VALANGHE

5 - MOLTO FORTE | 4 - FORTE | 3 - MARCATO | 2 - MODERATO | 1 - DEBOLE | NO NEVE | NO INFO

## LEGENDA PROBLEMA

NEVE FRESCA | LASTRONI DA VENTO | STRATI DEBOLI PERSISTENTI | NEVE BAGNATA | SLITTAMENTO | CORNICI | NESSUN PROBLEMA VALANGHIVO EVIDENTE | NO_INFO

**Bollettino realizzato su scala sinottica-regionale (standard EAWS). La sua valutazione non può escludere in alcun modo la necessità di una seria e capace valutazione locale del pericolo (singolo pendio) che può essere anche sensibilmente diverso. Le previsioni meteorologiche sono relative all'orario UTC (per l'Italia +1 in inverno e +2 in estate).**

# ALPI RETICHE

## PREVISIONE METEO

| Quota | | 27/02/2026 h6:00 | 27/02/2026 h12:00 | 27/02/2026 h18:00 |
|---|---|---|---|---|
| 1000 | Venti | 00 Calma | 00 Calma | 00 Calma |
| | Temperature | +06 °C | +05 °C | +05 °C |
| | Temp.percepita | 6 °C | 5 °C | 5 °C |
| 2000 | Venti | 00 Calma | 00 Calma | 00 Calma |
| | Temperature | +06 °C | +05 °C | +05 °C |
| | Temp.percepita | 6 °C | 5 °C | 5 °C |
| 3000 | Venti | 03 Nodi da S-Ovest | 02 Nodi da S-Ovest | 03 Nodi da S-Ovest |
| | Temperature | +00 °C | +00 °C | +00 °C |
| | Temp.percepita | -2 °C | 0 °C | -2 °C |
| Zero termico | | 2700-2900 m. | 2900-3100 m. | 2800-3000 m. |
| Fenomeno | | — | — | — |
| Stato del cielo | | | | |

## LEGENDA FENOMENI

— Assenza Fenomeni · Nebbia · Foschia · Pioggia debole · Pioggia moderata · Pioggia forte · Temporali

Nevicata debole · Nevicata moderata · Nevicata forte

## STATO DEL CIELO

Sereno · Poco nuvoloso · Nuvoloso · Molto nuvoloso · Coperto

## Parametri meteonivometrici registrati presso i campi di rilevamento il 26/02/2026.

| Località | Comune | Quota (m.s.l.m.) | Altezza neve (cm) | Neve caduta nelle 24 ore (cm) | Temp. Min (°C) | Temp. Max (°C) | Condizioni del tempo |
|---|---|---|---|---|---|---|---|
| SPONDA | Livigno (SO) | 2150 | 65 | 0 | -5 | +11 | Assenza di precipitazioni |
| BORMIO2000-LECCIONA | Valdisotto (SO) | 2050 | 70 | 0 | N.P. | N.P. | Assenza di precipitazioni |
| DOSSO DEL VALLONE | Valfurva (SO) | 2582 | 59 | 0 | -2 | +5 | Assenza di precipitazioni |
| GARBOI * | Vezza d'Oglio (BS) | 1421 | 13 | 0 | N.P. | N.P. | Assenza di precipitazioni |
| ALPE PALU' | Chiesa in Valmalenco (SO) | 2010 | 78 | 0 | -1 | +11 | Assenza di precipitazioni |
| PREDA | Edolo (BS) | 1580 | 35 | 0 | 0 | +10 | Assenza di precipitazioni |
| COLONIA VIGILI | Ponte di Legno (BS) | 1640 | 53 | 0 | 0 | +10 | Assenza di precipitazioni |

**(*) Rilievi fuori campo**

**L'INFORMAZIONE E' PREVENZIONE - LEGGI L'ATTUALE GRADO DI PERICOLO VALANGHE!**

**IL CAPO DEL CENTRO NAZIONALE METEOMONT**
**(Ten. Col. RFI Emanuela Gini)**
**FIRMA AUTOGRAFA OMESSA AI SENSI**
**DELL'ART.3 DEL D.LGS N.39/1993**

**Bollettino realizzato su scala sinottica-regionale (standard EAWS). La sua valutazione non può escludere in alcun modo la necessità di una seria e capace valutazione locale del pericolo (singolo pendio) che può essere anche sensibilmente diverso. Le previsioni meteorologiche sono relative all'orario UTC (per l'Italia +1 in inverno e +2 in estate).**