MINISTERO DELLA DIFESA

meteomont
Servizio Nazionale di previsione neve e valanghe

EAWS EUROPEAN AVALANCHE WARNING SERVICES

CARABINIERI

AERONAUTICA MILITARE SERVIZIO METEOROLOGICO

## GRAN SASSO OVEST

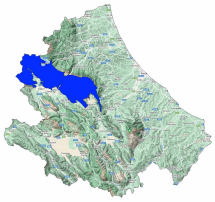

Bollettino Valanghe N. 347/2026 del 26/02/2026 ore 14.00
Validità 48 ore prossima emissione 27/02/2026

**A cura del Servizio METEOMONT dell'ARMA dei CARABINIERI**
**In collaborazione con Servizio Meteorologico dell'Aeronautica militare**

## SITUAZIONE alle 14:00 del 26/02/2026

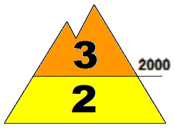


**SITUAZIONE TIPO: passaggio da poca a molta neve.**




**SITUAZIONE TIPO: situazione primaverile.**

| Quota neve (mslm) | Nord | Sud |
|---|---|---|
| | 1600 - 1700 | 1700 - 1800 |

| Altezza Neve (cm) | Neve al suolo | Neve Fresca | Quota (mslm) |
|---|---|---|---|
| | 158 | 000 | 2382 |
| | 132 | 000 | 2135 |

**VALANGHE OSSERVATE: Alcune valanghe di medie dimensioni, Valanghe di neve a debole coesione di fondo.**

## PREVISIONI 27/02/2026

# GRADO DI PERICOLO: MARCATO 3

## SITUAZIONE TIPO: passaggio da poca a molta neve.

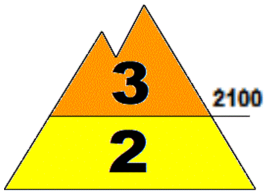


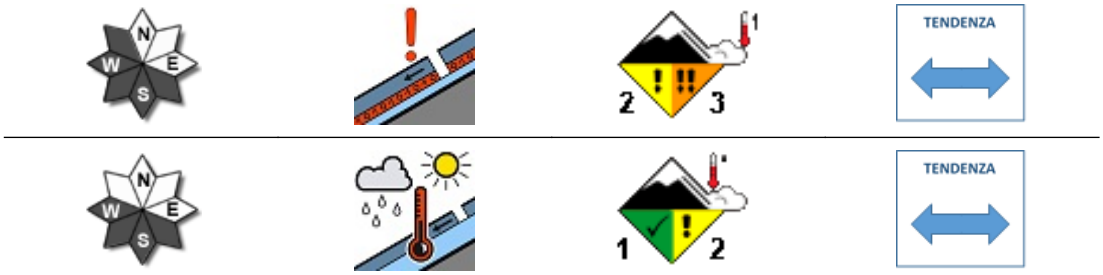


## SITUAZIONE TIPO: situazione primaverile.

**MANTO NEVOSO: La stabilità del manto nevoso è scarsa su alcuni punti (aree) per versanti da sud est a nord ovest al di sopra di 2100 mslm, possibili valanghe di dimensioni grandi.**
**La stabilità del manto nevoso è scarsa su pochi punti (aree) per versanti al sole al di sotto di 2100 mslm, possibili valanghe di dimensioni medie.**

## AVVERTENZE

Il rialzo termico diurno richiede un'attenta valutazione temporale dell'escursione che eviti l'attraversamento di pendii ripidi nelle ore più calde della giornata.

## SCALA EUROPEA DEL GRADO DI PERICOLO VALANGHE

## LEGENDA PROBLEMA

**Bollettino realizzato su scala sinottica-regionale (standard EAWS). La sua valutazione non può escludere in alcun modo la necessità di una seria e capace valutazione locale del pericolo (singolo pendio) che può essere anche sensibilmente diverso. Le previsioni meteorologiche sono relative all'orario UTC (per l'Italia +1 in inverno e +2 in estate).**

MINISTERO DELLA DIFESA

meteomont
Servizio Nazionale di previsione neve e valanghe

EAWS EUROPEAN AVALANCHE WARNING SERVICES

CARABINIERI

# GRAN SASSO OVEST

## PREVISIONE METEO

| Quota | | 27/02/2026 h6:00 | 27/02/2026 h12:00 | 27/02/2026 h18:00 |
|---|---|---|---|---|
| 1000 | Venti | 01 nodi da N-Ovest | 02 Nodi da S-Ovest | 01 Nodi da Nord |
| | Temperature | +09 °C | +09 °C | +07 °C |
| | Temp.percepita | 9 °C | 9 °C | 7 °C |
| 2000 | Venti | 01 nodi da N-Ovest | 02 nodi da Ovest | 02 Nodi da Ovest |
| | Temperature | +06 °C | +07 °C | +06 °C |
| | Temp.percepita | 6 °C | 7 °C | 6 °C |
| 3000 | Venti | 03 nodi da N-Ovest | 03 nodi da Ovest | 04 Nodi da Ovest |
| | Temperature | +00 °C | +00 °C | +00 °C |
| | Temp.percepita | -2 °C | -2 °C | -3 °C |
| Zero termico | | 2900-3100 m. | 2900-3100 m. | 2900-3100 m. |
| Fenomeno | | — | — | — |
| Stato del cielo | | | | |

## LEGENDA FENOMENI

— Assenza Fenomeni · Nebbia · Foschia · Pioggia debole · Pioggia moderata · Pioggia forte · Temporali

Nevicata debole · Nevicata moderata · Nevicata forte

## STATO DEL CIELO

Sereno · Poco nuvoloso · Nuvoloso · Molto nuvoloso · Coperto

## Parametri meteonivometrici registrati presso i campi di rilevamento il 26/02/2026.

| Località | Comune | Quota (m.s.l.m.) | Altezza neve (cm) | Neve caduta nelle 24 ore (cm) | Temp. Min (°C) | Temp. Max (°C) | Condizioni del tempo |
|---|---|---|---|---|---|---|---|
| COLLE RUTO | Campotosto (AQ) | 1384 | 0 | 0 | +1 | +8 | Assenza di precipitazioni |
| S. DONATO | Castel del Monte (AQ) | 1400 | 0 | 0 | +2 | +12 | Assenza di precipitazioni |
| CAMPO IMPERATORE | L'Aquila (AQ) | 2135 | 132 | 0 | 0 | +5 | Assenza di precipitazioni |
| CAMPO PERICOLI - M.TE PORTELLA * | L'Aquila (AQ) | 2382 | 158 | 0 | N.P. | N.P. | Assenza di precipitazioni |

**(*) Rilievi fuori campo**

**L'INFORMAZIONE E' PREVENZIONE - LEGGI L'ATTUALE GRADO DI PERICOLO VALANGHE!**

**IL CAPO DEL CENTRO NAZIONALE METEOMONT**
**(Ten. Col. RFI Emanuela Gini)**
**FIRMA AUTOGRAFA OMESSA AI SENSI**
**DELL'ART.3 DEL D.LGS N.39/1993**

**Bollettino realizzato su scala sinottica-regionale (standard EAWS). La sua valutazione non può escludere in alcun modo la necessità di una seria e capace valutazione locale del pericolo (singolo pendio) che può essere anche sensibilmente diverso. Le previsioni meteorologiche sono relative all'orario UTC (per l'Italia +1 in inverno e +2 in estate).**