Bulletin d'estimation du risque d'avalanche
(valable en dehors des pistes balisées et ouvertes)

MASSIF : Aravis

Rédigé le jeudi 26 février 2026 à 16h

Estimation des risques pour le : VENDREDI 27 FÉVRIER

MANTEAU NEIGEUX RÉACTIF AU RÉCHAUFFEMENT

3

2 → 3

N O E S

Indice de risque limité évoluant en marqué.

Départs spontanés : avalanches de neige humide et plaques de fond

Déclenchements provoqués : coulée humides + rares anciennes plaques peu réactives

Indices de risque : 5 très fort - 4 fort - 3 marqué - 2 limité - 1 faible -- En noir : les pentes les plus dangereuses

Stabilité du manteau neigeux

Situation avalancheuse typique : neige humide — avalanches de fond

Départs spontanés :
* la plupart des versants S ont déjà bien purgé, mais l'humidification gagne à présent vers les orientations E et W.
* **avalanches de neige humide**. Au réchauffement, diverses orientations en suivant la course du soleil. La plupart en forme de poire, mais pouvant s'élargir et entraîner une plaque en contrebas. Taille 2 (moyenne), voire 3 (grande) en cas de grande pente pas encore purgée, notamment versants W. *Observables :* escargots, départs souvent près des rochers/falaises réchauffés, enfoncement piéton pour estimer le volume humidifié mobilisable.
* **plaques de fond**. Surtout l'après-midi, mais possibles à n'importe quelle heure y compris la nuit. Sur terrains raides et lisses en herbe, vires, dalles rocheuses. Versants E, NE : en dessous de 2000 m. Versants SE, S, SW, W : en dessous de 2200/2400 m. Taille 2 à 3.

Déclenchements provoqués :
* **coulées ponctuelles de neige humide** sous les skis. En pentes raides réchauffées. Taille 2.
* **plaque dure sur ancienne couche fragile persistante enfouie**. Versants W/N/E, au-dessus de 2000/2200 m. Peu probable, car cette ancienne couche fragile est généralement bien enfouie. Toutefois, une première plaque de surface, voire une chute de corniche, pourrait déclencher une plaque épaisse (60cm/1m).

Autres :
* **chutes de corniches**, épaisses et volumineuses, pouvant entraîner une plaque en contrebas.

Qualité de la neige

Enneigement : bon pour une fin février. On peut chausser les skis vers 1200/1300 m. Épaisseur du manteau neigeux hétérogène : fort tassement sous l'effet de la douceur, grosses corniches et accumulations, crêtes érodées par les forts vents pendant et après les perturbations (de SW puis NW).

Qualité de la neige vendredi :
* qualité du ski : pas facile, avec des croûtes cassantes, surplombant une neige par encore complètement tassée (en E et W) voire très humide (en S).
* sous 2200/2300 m : neige dense, croûtée le matin, s'humidifiant rapidement. Tendance à l'humidification en profondeur.
* au-dessus de 2200/2400 m : variable, neige dense, encore assez froide. Humidification superficielle en adrets. Cartonnée dans les secteurs qui ont été exposés aux vents de W/NW/N.

Aperçu météo pour le vendredi 27 février

	nuit	matin	après-midi	soir
Soleil et grande douceur. +8 DG à 2000 m.				
Pluie-Neige				
Iso 0 °C	3 000 m	2 900 m	2 800 m	2 600 m
Vent 2000 m	↑ 10 km/h	↑ 10 km/h	↑ 20 km/h	↗ 20 km/h
Vent 2500 m	↗ 20 km/h	↗ 20 km/h	↗ 30 km/h	↗ 30 km/h

Épaisseur de neige hors-piste

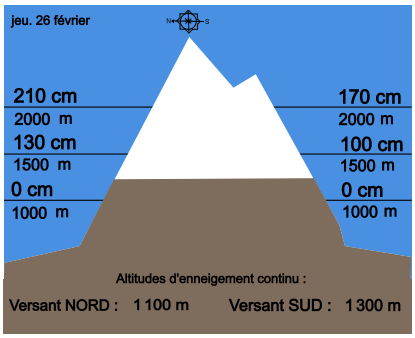

Précipitations à 1800 m

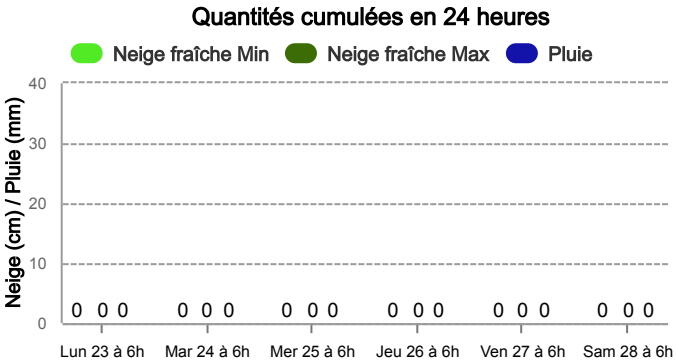

Tendance du samedi 28 février

2

Indice de risque limité

Un peu plus frais, risque en légère baisse.

Pour consulter la vigilance en cours, veuillez vous rendre sur le site https://vigilance.meteofrance.fr/fr

Météo-France - 73 avenue de Paris, 94165 Saint-Mandé cedex - Contact : contact@meteo.fr

Rédigé par Météo-France avec la contribution des observateurs du réseau nivo-météorologiques. Partenariat : ANMSM (Maires de Stations de Montagne), DSF (Domaines Skiables de France), ADSP (Directeurs de Pistes et de la Sécurité des Stations de Sports d'Hiver) et autres acteurs de la montagne.

Bulletin neige & avalanches par téléphone au 0 892 68 10 20 Service 0,35 € / min + prix appel

RÉPUBLIQUE FRANÇAISE
Liberté Égalité Fraternité

METEO FRANCE
À VOS CÔTÉS, DANS UN CLIMAT QUI CHANGE

Bulletin d'estimation du risque d'avalanche

(valable en dehors des pistes balisées et ouvertes)

MASSIF : Aravis

Rédigé le jeudi 26 février 2026 à 16h

Conditions nivo-météo des 7 derniers jours

	ven. 20/02				sam. 21/02				dim. 22/02				lun. 23/02				mar. 24/02				mer. 25/02				jeu. 26/02			
	03h	09h	15h	21h	03h	09h	15h	21h	03h	09h	15h	21h	03h	09h	15h	21h	03h	09h	15h	21h	03h	09h	15h	21h	03h	09h	15h	21h
Météo																												
Vent (km/h)	50	35	30	35	35	35	35	45	40	35	40	30	30	20	20	25	25	25	15	15	15	15	20	20	10	10	15	15
à 2500m																												
Vent (km/h)	35	25	20	20	20	20	20	20	20	20	25	20	20	10	15	15	15	15	10	10	10	10	10	10	5	5	10	10
à 2000m																												

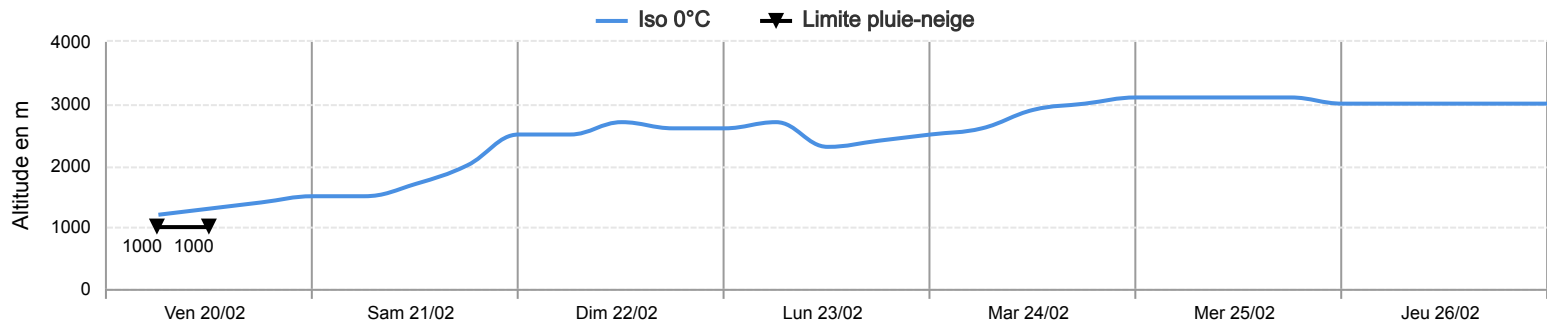

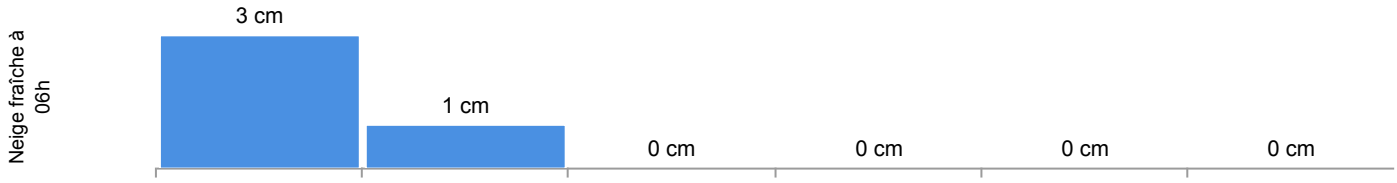

Risque d'avalanche	ven. 20/02	sam. 21/02	dim. 22/02	lun. 23/02	mar. 24/02	mer. 25/02	jeu. 26/02
	4	4	3	2	3	3	3

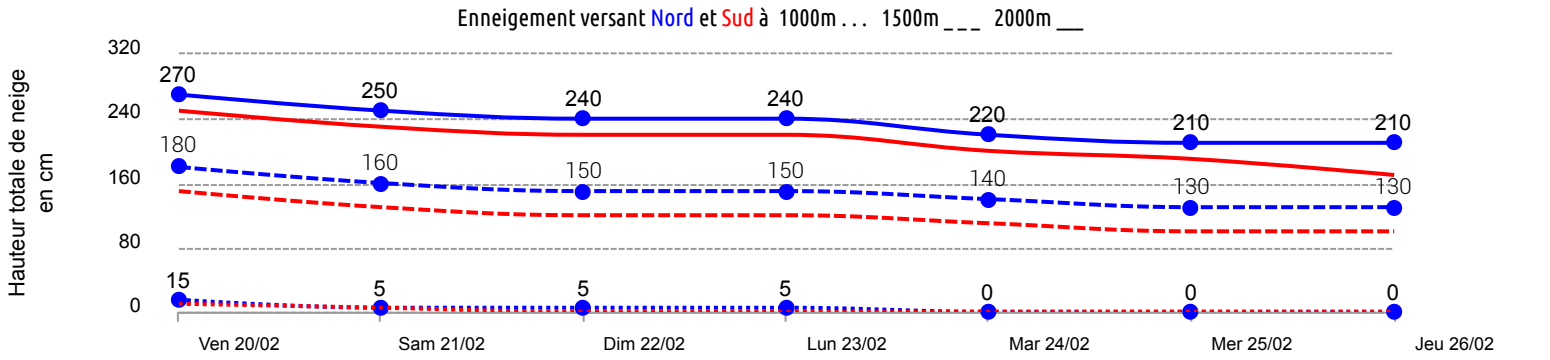

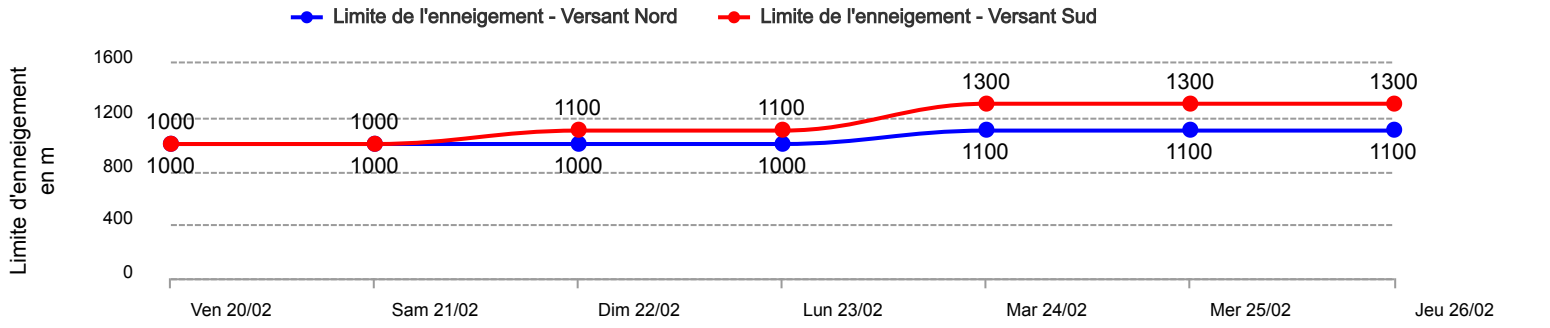

Pour consulter la vigilance en cours, veuillez vous rendre sur le site https://vigilance.meteofrance.fr/fr

Météo-France - 73 avenue de Paris, 94165 Saint-Mandé cedex - Contact : contact@meteo.fr

Rédigé par Météo-France avec la contribution des observateurs du réseau nivo-météorologiques. Partenariat : ANMSM (Maires de Stations de Montagne), DSF (Domaines Skiables de France), ADSP (Directeurs de Pistes et de la Sécurité des Stations de Sports d'Hiver) et autres acteurs de la montagne.

Bulletin neige & avalanches par téléphone au

0 892 68 10 20 Service 0,35 € / min + prix appel