Bulletin d'estimation du risque d'avalanche
(valable en dehors des pistes balisées et ouvertes)

MASSIF : Bauges

Rédigé le jeudi 26 février 2026 à 16h

Estimation des risques pour le : VENDREDI 27 FÉVRIER

MANTEAU NEIGEUX RÉACTIF AU RÉCHAUFFEMENT

3

2 → 3

N O E S

Indice de risque limité évoluant en marqué.

Départs spontanés : plaques de fond et avalanches de neige humide

Déclenchements provoqués : coulées humides

Indices de risque : 5 très fort - 4 fort - 3 marqué - 2 limité - 1 faible -- En noir : les pentes les plus dangereuses

Stabilité du manteau neigeux

Situation avalancheuse typique : avalanches de fond — neige humide

Départs spontanés :
* la plupart des versants S ont déjà bien purgé, mais l'humidification gagne à présent vers les orientations E et W.
* **avalanches de neige humide**. Au réchauffement, diverses orientations en suivant la course du soleil. La plupart en forme de poire, mais localement pouvant s'élargir et entraîner une plaque en contrebas. Taille 2 (moyenne), voire 3 (grande) en cas de grande pente pas encore purgée, notamment versants W. *Observables :* escargots, départs souvent près des rochers/falaises réchauffés, enfoncement piéton pour estimer le volume humidifié mobilisable.
* **plaques de fond**. Surtout l'après-midi, mais possibles à n'importe quelle heure y compris la nuit. Sur terrains raides et lisses en herbe, vires, dalles rocheuses. Taille 2, éventuellement 3.

Déclenchements provoqués :
* **coulées ponctuelles de neige humide** sous les skis. En pentes raides réchauffées. Taille 2.

Autres :
* **chutes de corniches**, épaisses et volumineuses, pouvant entraîner une plaque en contrebas.

Qualité de la neige

Enneigement : bon pour une fin février. On peut chausser les skis vers 1200/1400 m. Poursuite du tassement sous l'effet de la douceur, grosses corniches, crêtes érodées par les forts vents pendant et après les perturbations (de SW puis de N).

Qualité de la neige vendredi :
* neige très dense, croûte plutôt portante en début de matinée, puis s'humidifiant rapidement. Tendance à l'humidification en profondeur.
* versants N : neige dense, croûtée le matin, puis lourde. Cartonnée près des crêtes exposées au vent de N.

Aperçu météo pour le vendredi 27 février

Soleil et grande douceur. +8 DG à 2000 m.

	nuit	matin	après-midi	soir
Pluie-Neige				
Iso 0 °C	3 000 m	2 900 m	2 800 m	2 600 m
Vent 1500 m	10 km/h	15 km/h	15 km/h	20 km/h
Vent 2000 m	20 km/h	20 km/h	20 km/h	30 km/h

Épaisseur de neige hors-piste

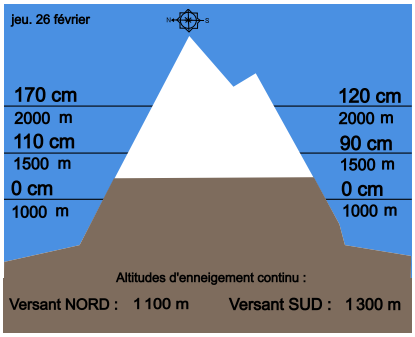

Précipitations à 1800 m

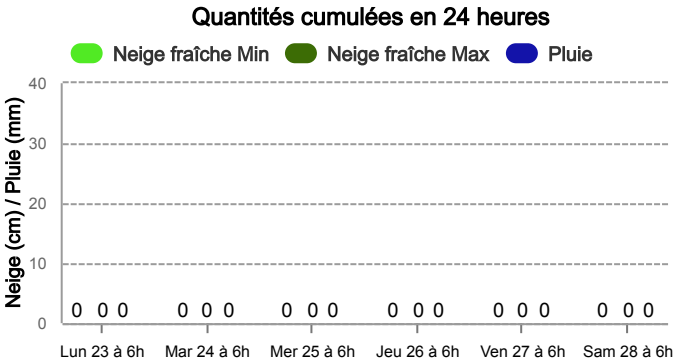

Tendance du samedi 28 février

2

Indice de risque limité

Un peu plus frais, risque en légère baisse.

Pour consulter la vigilance en cours, veuillez vous rendre sur le site https://vigilance.meteofrance.fr/fr

Météo-France - 73 avenue de Paris, 94165 Saint-Mandé cedex - Contact : contact@meteo.fr

Rédigé par Météo-France avec la contribution des observateurs du réseau nivo-météorologiques. Partenariat : ANMSM (Maires de Stations de Montagne), DSF (Domaines Skiables de France), ADSP (Directeurs de Pistes et de la Sécurité des Stations de Sports d'Hiver) et autres acteurs de la montagne.

Bulletin neige & avalanches par téléphone au 0 892 68 10 20 Service 0,35 € / min + prix appel

Bulletin d'estimation du risque d'avalanche

(valable en dehors des pistes balisées et ouvertes)

MASSIF : Bauges

Rédigé le jeudi 26 février 2026 à 16h

Conditions nivo-météo des 7 derniers jours

	ven. 20/02				sam. 21/02				dim. 22/02				lun. 23/02				mar. 24/02				mer. 25/02				jeu. 26/02			
	03h	09h	15h	21h	03h	09h	15h	21h	03h	09h	15h	21h	03h	09h	15h	21h	03h	09h	15h	21h	03h	09h	15h	21h	03h	09h	15h	21h
Météo																												
Vent (km/h)	55	35	25	25	25	25	30	30	25	25	25	20	25	20	20	30	30	25	20	20	20	20	20	20	15	15	15	15
à 2000m	↓	↻	↓	↓	↓	↘	→	→	→	→	↗	↗	↗	↗	↘	↓	↙	↙	↙	←	↑	↑	↗	↗	↑	↗	↗	↑
Vent (km/h)	40	25	20	15	20	15	15	10	10	5	15	10	15	10	15	20	20	15	10	10	10	10	10	10	5	10	10	10
à 1500m	↓	↓	↓	↓	↓	↘	→	→	→	↗	↗	↑	↗	↙	↙	↓	↓	↙	↙	↖	↑	↑	↑	↑	↑	↑	↑	↑

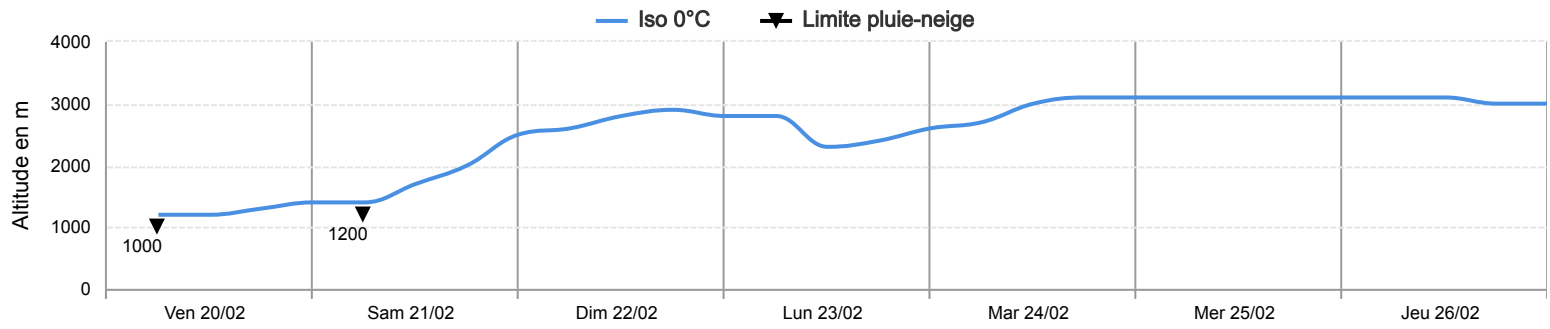

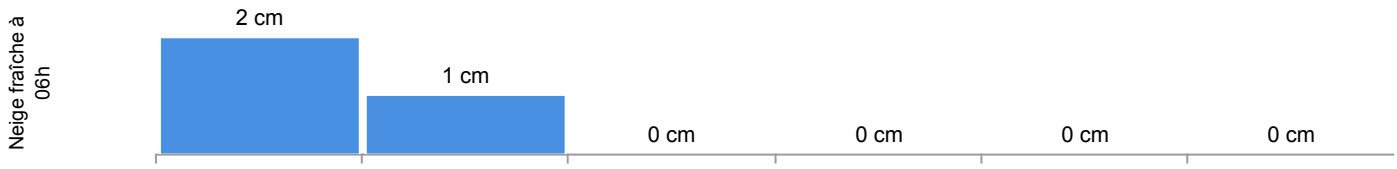

Risque d'avalanche	ven. 20/02	sam. 21/02	dim. 22/02	lun. 23/02	mar. 24/02	mer. 25/02	jeu. 26/02
	4	4	2	2	2	3	3

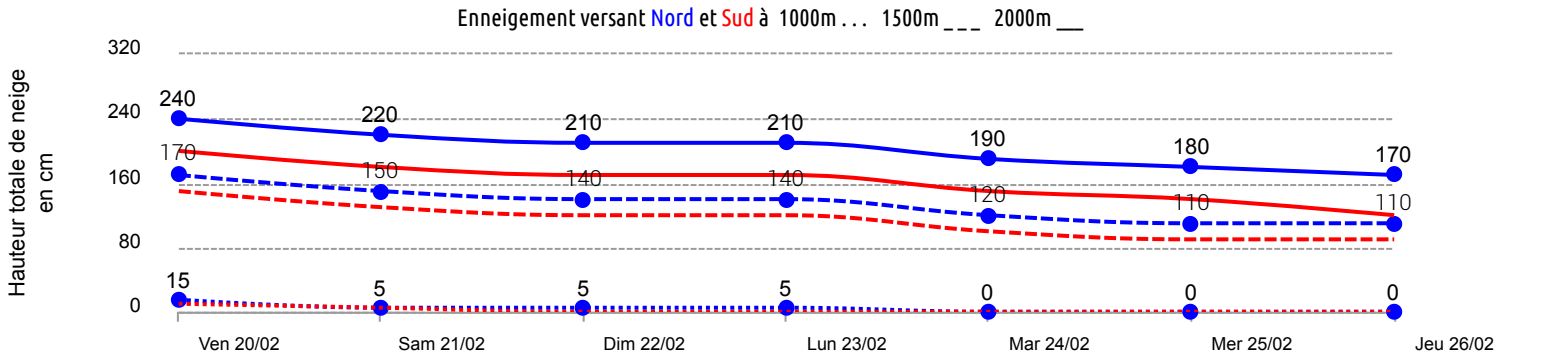

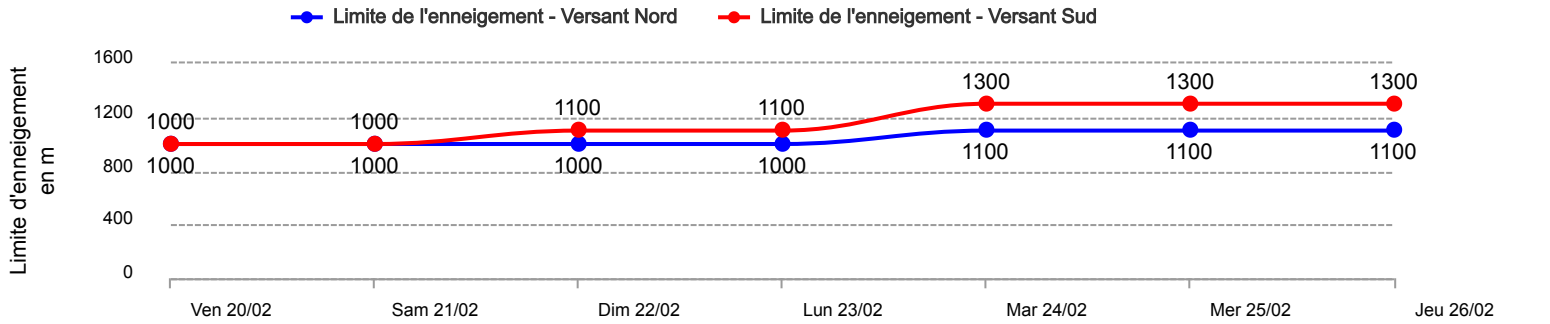

Pour consulter la vigilance en cours, veuillez vous rendre sur le site https://vigilance.meteofrance.fr/fr

Météo-France - 73 avenue de Paris, 94165 Saint-Mandé cedex - Contact : contact@meteo.fr

Rédigé par Météo-France avec la contribution des observateurs du réseau nivo-météorologiques. Partenariat : ANMSM (Maires de Stations de Montagne), DSF (Domaines Skiables de France), ADSP (Directeurs de Pistes et de la Sécurité des Stations de Sports d'Hiver) et autres acteurs de la montagne.

Bulletin neige & avalanches par téléphone au

0 892 68 10 20 Service 0,35 € / min + prix appel