Bulletin d'estimation du risque d'avalanche

(valable en dehors des pistes balisées et ouvertes)

MASSIF : Cerdagne Canigou

Rédigé le jeudi 26 février 2026 à 16h

Estimation des risques pour le : VENDREDI 27 FÉVRIER

HUMIDIFICATION QUI SE POURSUIT EN VERSANT SUD EN GAGNANT EN ALTITUDE ET EN PROFONDEUR

2

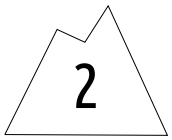

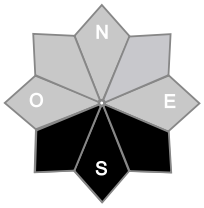

neige humide

Indice de risque limité.

Départs spontanés : En neige humide, dans les versants ensoleillés

Déclenchements provoqués : Peu probable ou en neige humide en surface

Indices de risque : 5 très fort - 4 fort - 3 marqué - 2 limité - 1 faible -- En noir : les pentes les plus dangereuses

Stabilité du manteau neigeux

Situation avalancheuse typique : neige humide avalanches de fond

Départs spontanés :
Activité avalancheuse qui devrait augmenter au fil de la journée dans les pentes raides prenant le soleil, notamment à proximités des rochers. Départs ponctuels d'avalanches petites à moyennes, plus rarement grandes, avec l'humidification qui se généralise jusqu'aux plus hauts sommets au soleil.
En dessous de 2000 m principalement, des avalanches de fond sont aussi possibles à toute heure, de taille petite à moyenne avec déjà des reptations ou gueules de baleine visibles actuellement.

Déclenchements provoqués :
Peu probables. Des coulées de neige humide sont tout de même possibles au passage d'un pratiquant dans une couche de neige profondément humidifiée.

Autre : La neige a pris des allures printanières dans de nombreux secteurs avec un risque accru de glissade sur la neige redurcie par les cycles gel/dégels successifs de ces derniers jours, le matin en tous versants, jusqu'en début d'après-midi en ouest, toute la journée en nord. De la glace est présente sur certaines crêtes (ouest principalement).

Qualité de la neige

Enneigement :
L'enneigement est largement supérieur à celui des cinq dernières années et se situe au plus haut par rapport aux statistiques plus anciennes. Malgré les belles journées qui s'enchaînent et la douceur, la limite d'enneigement skiable évolue peu avec le regel nocturne qui permet toujours de chausser les skis dès 1500 m dans les conditions les plus favorables.

Qualité de la neige :
Au matin, on trouvera une neige bien regelée en surface là où elle s'humidifie chaque jour au soleil. En journée avec l'ensoleillement, on trouvera des conditions printanières dans les versants prenant le soleil, avec une humidification en profondeur du manteau neigeux. L'humidification atteint les sommets en versant sud avec de la neige lourde et très humide, notamment à basse altitude. Dans certains secteurs ombragés d'altitude, on peut trouver une neige encore froide et sèche à défaut d'être légère, tassée par le vent.
Proche des crêtes et sommet, l'enneigement est très hétérogène avec des secteurs bien soufflés et parfois glacés, particulièrement sur les flancs ouest.

Aperçu météo pour le vendredi 27 février

	nuit	matin	après-midi	soir
Grand Soleil, arrivée de nuages en fin de journée				
Pluie-Neige				
Iso 0 °C	3 100 m	3 100 m	3 000 m	2 700 m
Vent 2000 m	↘ 15 km/h	→ 15 km/h	↗ 15 km/h	↗ 20 km/h
Vent 3000 m	↘ 20 km/h	→ 20 km/h	↗ 25 km/h	↗ 30 km/h

Épaisseur de neige hors-piste

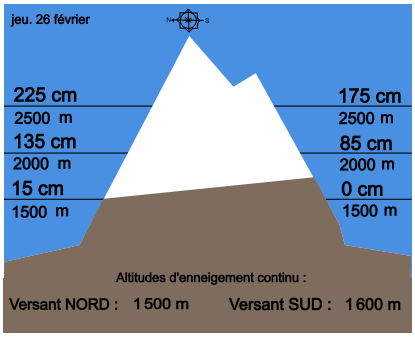

Précipitations à 1800 m

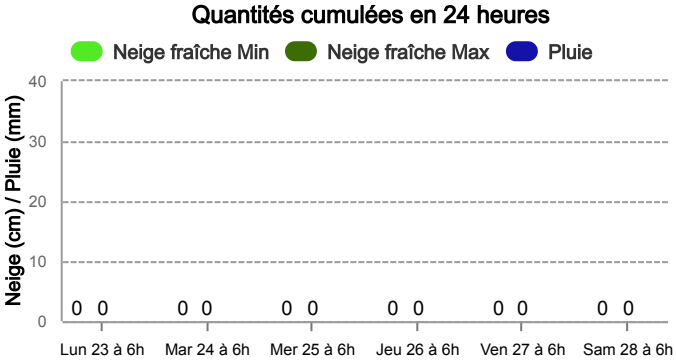

Tendance du samedi 28 février

2

Indice de risque limité

Peu d'évolution

Pour consulter la vigilance en cours, veuillez vous rendre sur le site https://vigilance.meteofrance.fr/fr

Météo-France - 73 avenue de Paris, 94165 Saint-Mandé cedex - Contact : contact@meteo.fr

Rédigé par Météo-France avec la contribution des observateurs du réseau nivo-météorologiques. Partenariat : ANMSM (Maires de Stations de Montagne), DSF (Domaines Skiables de France), ADSP (Directeurs de Pistes et de la Sécurité des Stations de Sports d'Hiver) et autres acteurs de la montagne.

Bulletin neige & avalanches par téléphone au
0 892 68 10 20 Service 0,35 € / min + prix appel

RÉPUBLIQUE FRANÇAISE
Liberté Égalité Fraternité

METEO FRANCE
À VOS CÔTÉS, DANS UN CLIMAT QUI CHANGE

Bulletin d'estimation du risque d'avalanche
(valable en dehors des pistes balisées et ouvertes)
MASSIF : Cerdagne Canigou

Rédigé le jeudi 26 février 2026 à 16h

Conditions nivo-météo des 7 derniers jours

	ven. 20/02				sam. 21/02				dim. 22/02				lun. 23/02				mar. 24/02				mer. 25/02				jeu. 26/02			
	03h	09h	15h	21h	03h	09h	15h	21h	03h	09h	15h	21h	03h	09h	15h	21h	03h	09h	15h	21h	03h	09h	15h	21h	03h	09h	15h	21h
Météo																												
Vent (km/h)	65	65	55	50	45	35	30	25	20	15	15	15	20	20	20	15	20	20	20	25	20	25	25	20	20	15	15	15
à 3000m																												
Vent (km/h)	60	60	40	30	25	20	20	15	10	10	10	10	10	10	10	10	10	10	10	15	15	15	15	10	10	10	10	10
à 2000m																												

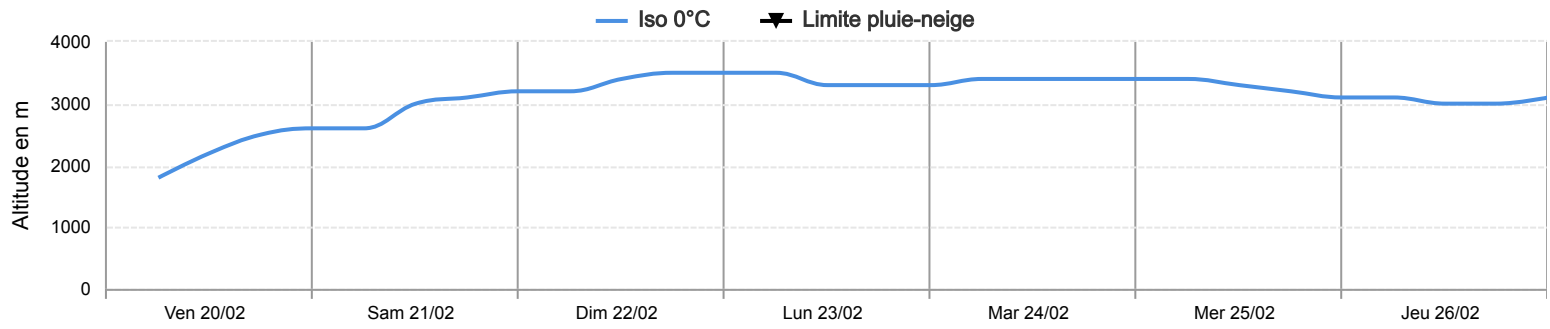

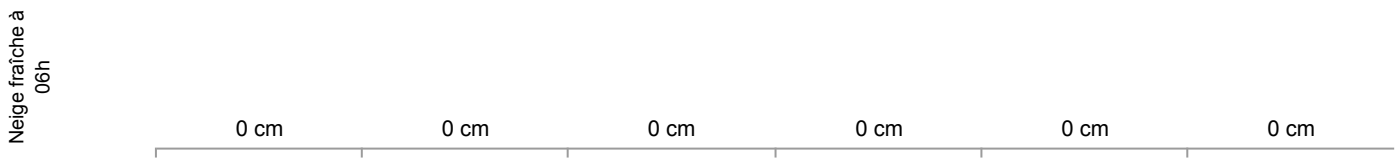

Risque d'avalanche	ven. 20/02	sam. 21/02	dim. 22/02	lun. 23/02	mar. 24/02	mer. 25/02	jeu. 26/02
	3	3	2	2	2	2	2

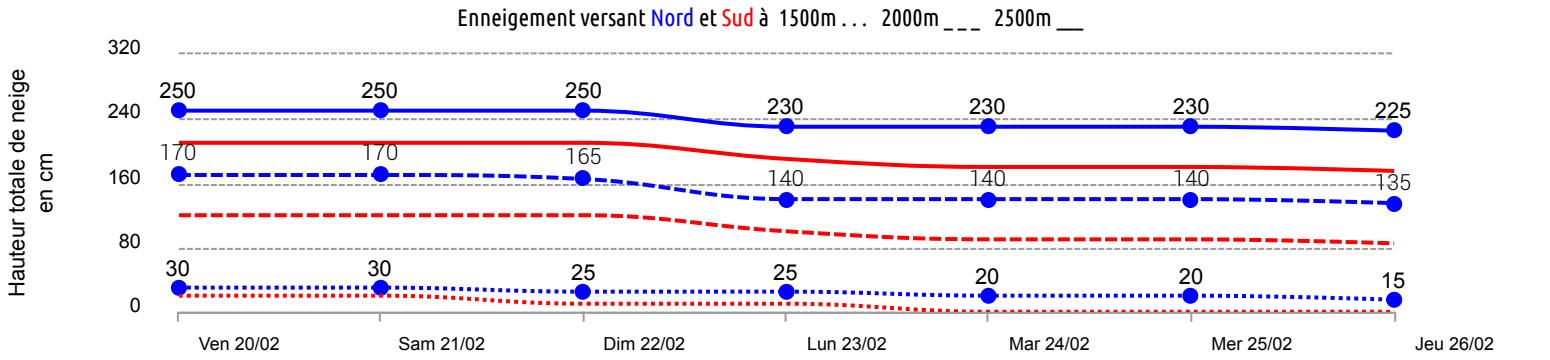

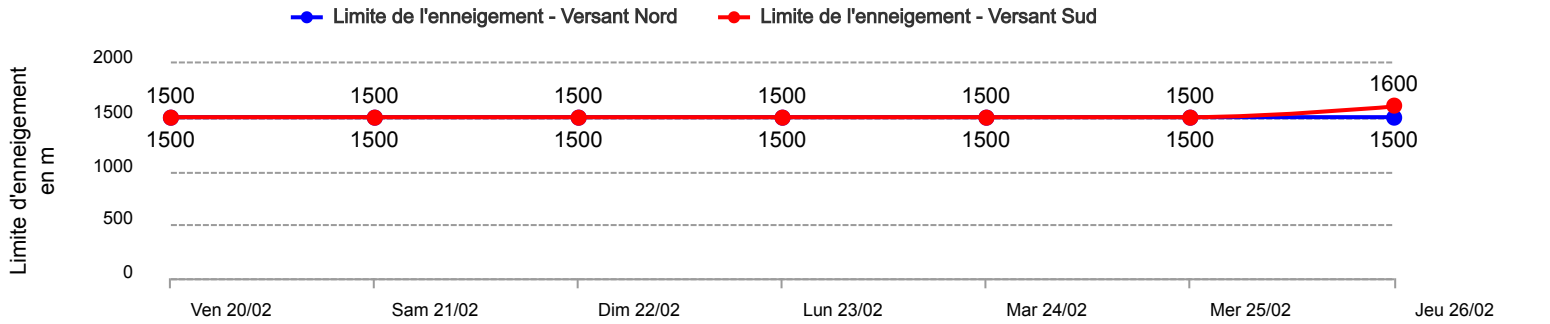

Pour consulter la vigilance en cours, veuillez vous rendre sur le site https://vigilance.meteofrance.fr/fr

Météo-France - 73 avenue de Paris, 94165 Saint-Mandé cedex - Contact : contact@meteo.fr

Bulletin neige & avalanches par téléphone au
0 892 68 10 20 Service 0,35 € / min + prix appel

Rédigé par Météo-France avec la contribution des observateurs du réseau nivo-météorologiques. Partenariat : ANMSM (Maires de Stations de Montagne), DSF (Domaines Skiables de France), ADSP (Directeurs de Pistes et de la Sécurité des Stations de Sports d'Hiver) et autres acteurs de la montagne.