Bulletin d'estimation du risque d'avalanche

(valable en dehors des pistes balisées et ouvertes)

MASSIF : Cinto Rotondo

Rédigé le jeudi 26 février 2026 à 16h

Estimation des risques pour le : VENDREDI 27 FÉVRIER

AVALANCHES DE NEIGE HUMIDE ET PLAQUES RÉSIDUELLES DANS LA NEIGE VENTÉE EN ALTITUDE

2

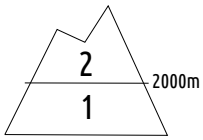

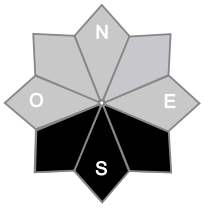

Au-dessus de 2000m indice de risque limité, plus bas indice faible.

Départs spontanés : En neige humide, devenant nombreux dans les versants ensoleillés au fil de la journée.

Déclenchements provoqués : Rares structures de plaques en Nord à Nord-Est au-delà de 2000 m.

Indices de risque : 5 très fort - 4 fort - 3 marqué - 2 limité - 1 faible -- En noir : les pentes les plus dangereuses

Stabilité du manteau neigeux

Situation avalancheuse typique : neige humide — neige ventée

Départs spontanés : Avec un regel nocturne quasi inexistant, l'humidification du manteau reprend dans les versants Sud et gagne davantage en profondeur. Après quelques heures de soleil, des coulées et avalanches de neige humide sont à attendre dans les pentes Sud raides. Avalanches de taille petite à moyenne (taille 1 à 2), voire grande (taille 3) où le manteau neigeux s'est déjà bien humidifié en profondeur ou suite à la rupture d'une corniche. Possibilité également à basse altitude dans une pente raide plus ombragée, d'une coulée ou d'un petit départ de plaque de fond.

Déclenchements provoqués : Quelques structures de plaques sont encore présentes dans la neige récente ventée, surtout dans les pentes orientées Nord à Est où persistent des couches fragiles (souvent de la neige roulée). Ces plaques se stabilisent progressivement ; elles peuvent surtout être déclenchées par une forte surcharge, plus rarement au passage d'un seul skieur ou randonneur. Déclenchements également faciles au passage d'un skieur ou randonneur de petites avalanches de neige humide dans les versants Sud à Sud-Ouest l'après-midi.

Qualité de la neige

Qualification de l'enneigement : L'enneigement est excellent pour la saison au-dessus de 1600 m. Sur la Maniccia, à 2400 m d'altitude dans le massif du Rotondo, on mesure 2m85 de hauteur totale de neige.

Limite d'enneigement skiable : 1400 à 1500 m selon le versant.

État de la neige : En versants ensoleillés, manteau neigeux désormais bien printanier jusqu'à haute altitude, neige dense, fine croûte cassante le matin. L'après-midi, elle sera généralement pourrie sous 1800/2000 m mais souvent suffisamment dense pour être portante au-dessus.

En Nord, sous 2000 m, neige plus mate, également densifiée au petit matin, ramollissant lentement en cours de journée et juste en surface. Au-dessus de 2000/2200 m, neige restant dure/cartonnée surtout en approchant des sommets avec un peu de vieille poudreuse dans les zones abritées. Neige parfois glacée dans les zones érodées par les forts vents.

A noter une neige colorée par endroits et des corniches parfois volumineuses.

Aperçu météo pour le vendredi 27 février

	nuit	matin	après-midi	soir
	800 m			

Mer de nuages dans les basses vallées.

Pluie-Neige				
Iso 0 °C	3 200 m	3 000 m	3 000 m	3 100 m
Vent 1500 m	↗ 10 km/h	↗ 10 km/h	↗ 10 km/h	→ 5 km/h
Vent 3000 m	↗ 20 km/h	↗ 15 km/h	→ 15 km/h	↘ 15 km/h

Épaisseur de neige hors-piste

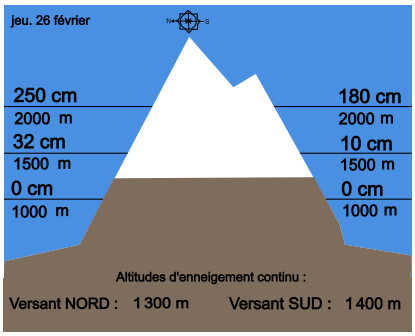

Précipitations à 1800 m

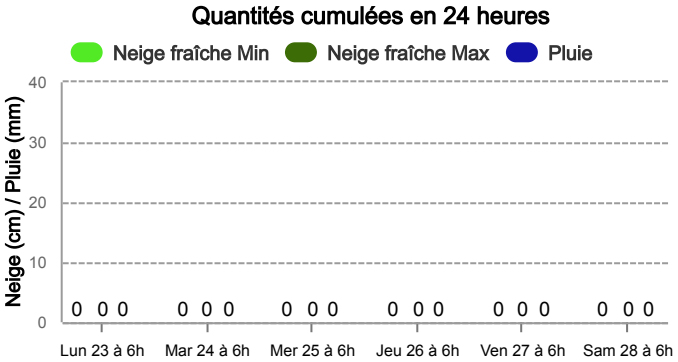

Tendance du samedi 28 février

2

Indice de risque limité

Poursuite d'un temps sec et ensoleillé, entrainant encore quelques départs dans les pentes raides exposées. La stabilisation des plaques se poursuit. Tendance du risque stationnaire.

Pour consulter la vigilance en cours, veuillez vous rendre sur le site https://vigilance.meteofrance.fr/fr

Météo-France - 73 avenue de Paris, 94165 Saint-Mandé cedex - Contact : contact@meteo.fr

Rédigé par Météo-France avec la contribution des observateurs du réseau nivo-météorologiques. Partenariat : ANMSM (Maires de Stations de Montagne), DSF (Domaines Skiables de France), ADSP (Directeurs de Pistes et de la Sécurité des Stations de Sports d'Hiver) et autres acteurs de la montagne.

Bulletin neige & avalanches par téléphone au 0 892 68 10 20 Service 0,35 € / min + prix appel

RÉPUBLIQUE FRANÇAISE
Liberté Égalité Fraternité

METEO FRANCE
À VOS CÔTÉS, DANS UN CLIMAT QUI CHANGE

Bulletin d'estimation du risque d'avalanche

(valable en dehors des pistes balisées et ouvertes)

MASSIF : Cinto Rotondo

Rédigé le jeudi 26 février 2026 à 16h

Conditions nivo-météo des 7 derniers jours

	ven. 20/02				sam. 21/02				dim. 22/02				lun. 23/02				mar. 24/02				mer. 25/02				jeu. 26/02			
	03h	09h	15h	21h	03h	09h	15h	21h	03h	09h	15h	21h	03h	09h	15h	21h	03h	09h	15h	21h	03h	09h	15h	21h	03h	09h	15h	21h
Météo																												
Vent (km/h)	80	60	60	40	40	40	30	25	25	30	50	80	80	80	70	60	40	35	30	20	5	5	5	5	10	15	15	15
à 3000m																												
Vent (km/h)	60	40	30	20	15	20	15	10	10	10	35	50	60	50	40	30	25	20	10	5	5	5	10	5	5	5	5	5
à 1500m																												

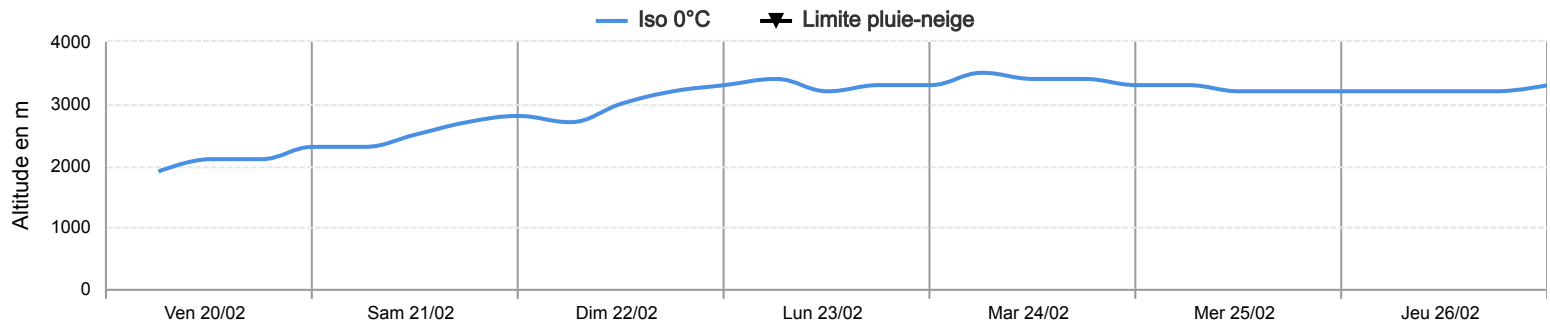

Neige fraîche à 06h

Ven 20/02	Sam 21/02	Dim 22/02	Lun 23/02	Mar 24/02	Mer 25/02
0 cm	0 cm	0 cm	0 cm	0 cm	0 cm

Risque d'avalanche	ven. 20/02	sam. 21/02	dim. 22/02	lun. 23/02	mar. 24/02	mer. 25/02	jeu. 26/02
	3	3	2	2	2	2	2

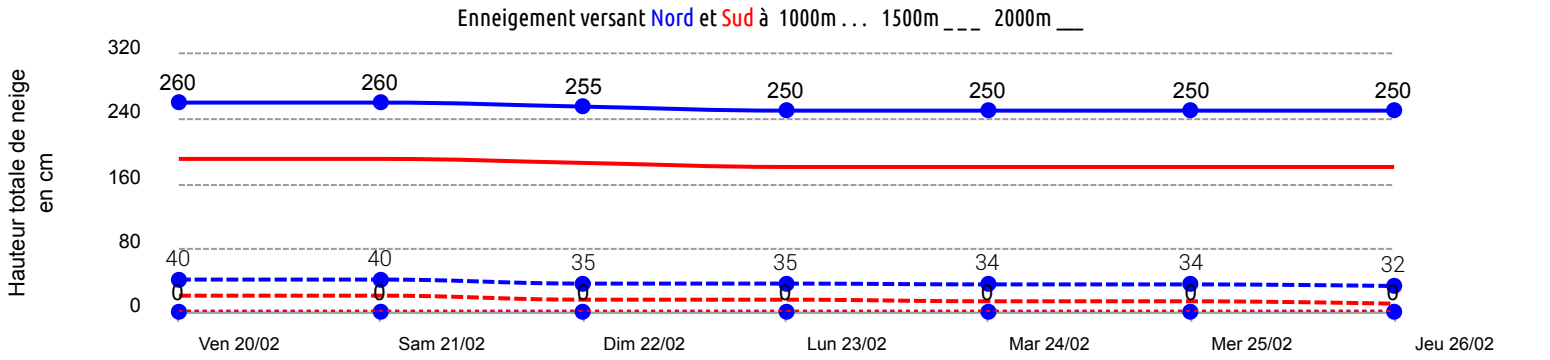

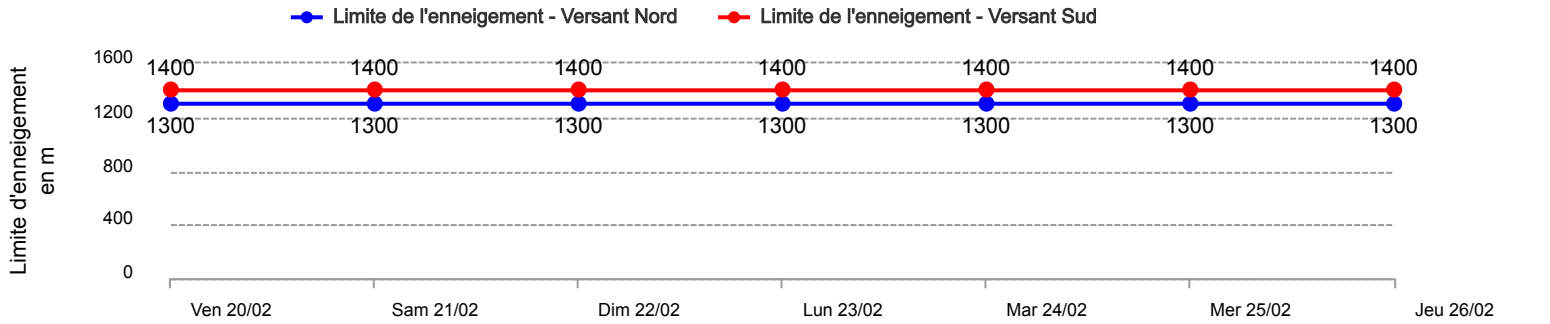

Pour consulter la vigilance en cours, veuillez vous rendre sur le site https://vigilance.meteofrance.fr/fr

Météo-France - 73 avenue de Paris, 94165 Saint-Mandé cedex - Contact : contact@meteo.fr

Bulletin neige & avalanches par téléphone au

0 892 68 10 20 Service 0,35 € / min + prix appel

Rédigé par Météo-France avec la contribution des observateurs du réseau nivo-météorologiques. Partenariat : ANMSM (Maires de Stations de Montagne), DSF (Domaines Skiables de France), ADSP (Directeurs de Pistes et de la Sécurité des Stations de Sports d'Hiver) et autres acteurs de la montagne.