Bulletin d'estimation du risque d'avalanche
(valable en dehors des pistes balisées et ouvertes)

MASSIF : Devoluy

Rédigé le jeudi 26 février 2026 à 16h

Estimation des risques pour le : VENDREDI 27 FÉVRIER

ACTIVITÉ NATURELLE LIMITÉE AU SOLEIL, MANTEAU NEIGEUX BIEN STABLE DANS LA NEIGE SÈCHE

2

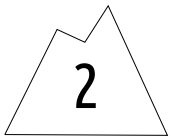

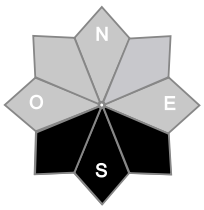

Indice de risque limité.

Départs spontanés : avalanches de neige humide au soleil, départs ponctuels ou linéaires, rarement de grande taille

Déclenchements provoqués : rares en neige sèche

Indices de risque : 5 très fort - 4 fort - 3 marqué - 2 limité - 1 faible -- En noir : les pentes les plus dangereuses

Stabilité du manteau neigeux

Situation avalancheuse typique : neige humide avalanches de fond

Déclenchements provoqués :
Des instabilités persistent au-dessus de 2200/2300 m d'altitude. Très enfouies en large versant nord, et pour la plupart non déclenchables par un seul skieur, elles peuvent l'être dans les versants d'un large secteur sud et générer des avalanches de taille moyenne, rarement grande (taille 2 à 3).

Départs spontanés : activité en neige humide en hausse selon la course du soleil, mais probablement moins marquée que les jours précédents. Les départs, le plus souvent ponctuels près des rochers ou des barres et de taille 1 à 2, peuvent, plus rarement, engendrer des avalanches linéaires et jusqu'au sol de taille 2 à 3. A toute heure du jour ou de la nuit, une avalanche de glissement de taille 2 est possible, et une taille 3 n'est pas exclue compte tenu des épaisseurs de neige encore mobilisables dans les versants bien ensoleillés.

Qualité de la neige

L'enneigement est très excédentaire pour un mois de février. Il faut remonter à 2009 pour trouver un enneigement encore plus abondant à cette période de l'année. Donnée observée : 240 cm à 2000 m à Superdévoluy.

Limite d'enneigement skiable dès 1100/1200 m sur terrain favorable, mais la neige fond rapidement en adrets raides et devient un peu juste sous 1600 m.

État de la neige de surface : * En adrets, manteau neigeux désormais bien printanier jusqu'à très haute altitude, petite croûte le matin, puis humidification au soleil l'après-midi, sur une grande épaisseur dans les pentes bien exposées.
* En ubacs (nord-ouest à nord-est), croûte de quelques cm le matin sous 2200 m environ sur les zones peu pentues, s'humidifiant en cours de journée. Ailleurs, la neige est soit cartonnée/durcie par les épisodes de vent passés, ou en poudreuse dense dans les combes ou pentes abritées.

Aperçu météo pour le vendredi 27 février

nuit	matin	après-midi	soir

Printanier : sec, ensoleillé et très doux, vent calme ou faible.

Pluie-Neige				
Iso 0 °C	3 100 m	3 000 m	2 900 m	2 800 m
Vent 2000 m	↑ 5 km/h	↑ 0 km/h	↑ 5 km/h	↑ 10 km/h
Vent 3000 m	↗ 10 km/h	↘ 10 km/h	↗ 15 km/h	↗ 20 km/h

Épaisseur de neige hors-piste

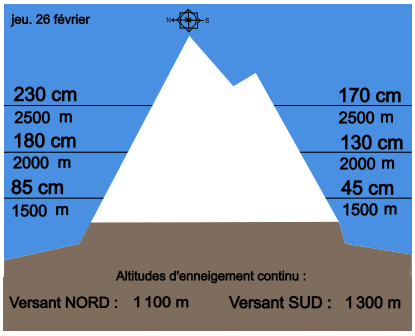

Précipitations à 1800 m

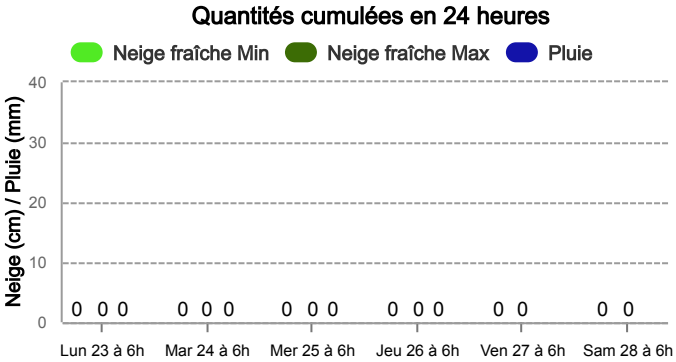

Tendance du samedi 28 février

2

Indice de risque limité

Risque en lente baisse avec le léger rafraîchissement de la masse d'air et la nébulosité. Maintien d'un risque limité

Pour consulter la vigilance en cours, veuillez vous rendre sur le site https://vigilance.meteofrance.fr/fr

Météo-France - 73 avenue de Paris, 94165 Saint-Mandé cedex - Contact : contact@meteo.fr

Rédigé par Météo-France avec la contribution des observateurs du réseau nivo-météorologiques. Partenariat : ANMSM (Maires de Stations de Montagne), DSF (Domaines Skiables de France), ADSP (Directeurs de Pistes et de la Sécurité des Stations de Sports d'Hiver) et autres acteurs de la montagne.

Bulletin neige & avalanches par téléphone au **0 892 68 10 20** Service 0,35 € / min + prix appel

RÉPUBLIQUE FRANÇAISE
Liberté Égalité Fraternité

METEO FRANCE
À VOS CÔTÉS, DANS UN CLIMAT QUI CHANGE

Bulletin d'estimation du risque d'avalanche

(valable en dehors des pistes balisées et ouvertes)

MASSIF : Devoluy

Rédigé le jeudi 26 février 2026 à 16h

Conditions nivo-météo des 7 derniers jours

	ven. 20/02				sam. 21/02				dim. 22/02				lun. 23/02				mar. 24/02				mer. 25/02				jeu. 26/02			
	03h	09h	15h	21h	03h	09h	15h	21h	03h	09h	15h	21h	03h	09h	15h	21h	03h	09h	15h	21h	03h	09h	15h	21h	03h	09h	15h	21h
Météo																												
Vent (km/h)	80	90	80	80	80	80	80	60	40	35	35	40	45	50	60	60	50	25	15	5	10	10	15	20	15	10	10	10
à 3000m																												
Vent (km/h)	75	60	60	60	45	60	60	40	25	15	15	15	20	40	40	30	35	20	10	10	10	15	20	15	5	5	5	5
à 2000m																												

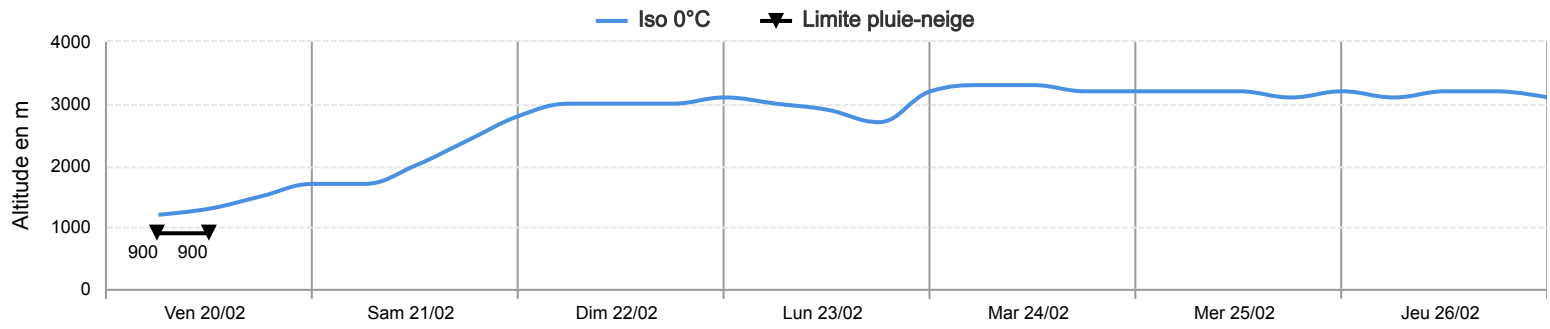

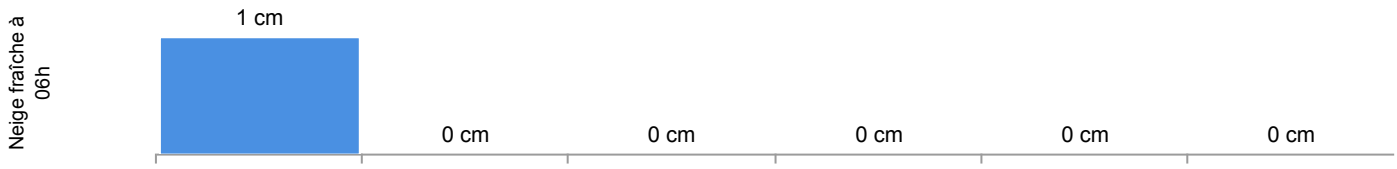

Risque d'avalanche	ven. 20/02	sam. 21/02	dim. 22/02	lun. 23/02	mar. 24/02	mer. 25/02	jeu. 26/02
	4	4	3	3	3	3	3

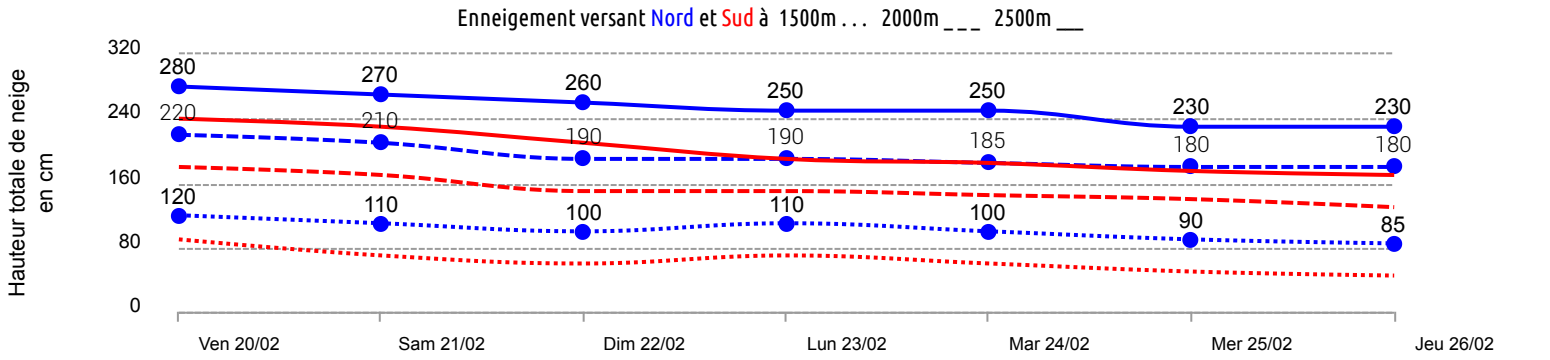

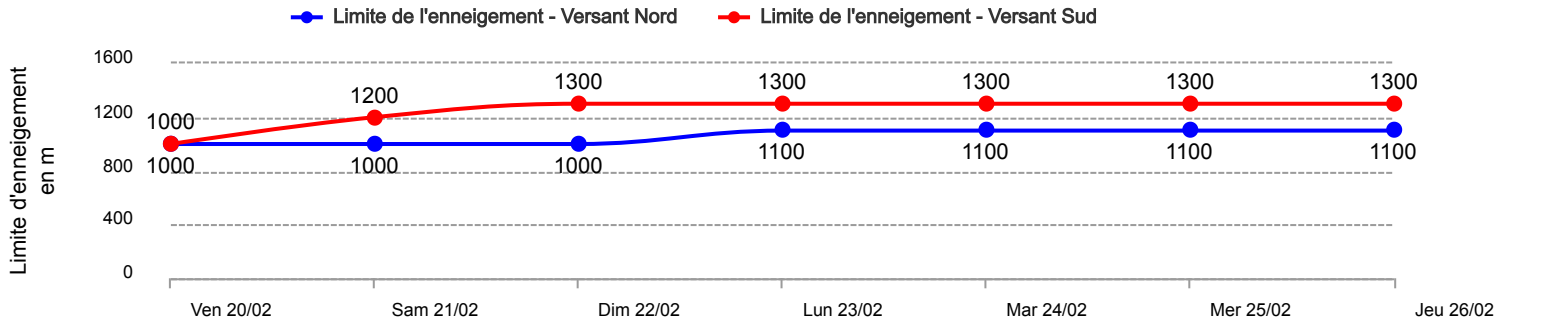

Pour consulter la vigilance en cours, veuillez vous rendre sur le site https://vigilance.meteofrance.fr/fr

Météo-France - 73 avenue de Paris, 94165 Saint-Mandé cedex - Contact : contact@meteo.fr

Bulletin neige & avalanches par téléphone au

0 892 68 10 20 Service 0,35 € / min + prix appel

Rédigé par Météo-France avec la contribution des observateurs du réseau nivo-météorologiques. Partenariat : ANMSM (Maires de Stations de Montagne), DSF (Domaines Skiables de France), ADSP (Directeurs de Pistes et de la Sécurité des Stations de Sports d'Hiver) et autres acteurs de la montagne.