Bulletin d'estimation du risque d'avalanche
(valable en dehors des pistes balisées et ouvertes)

MASSIF : Embrunais Parpaillon

Rédigé le jeudi 26 février 2026 à 16h

Estimation des risques pour le : VENDREDI 27 FÉVRIER

INSTABILITÉS RAREMENT DÉCLENCHABLES, MAIS POUVANT ÊTRE ÉPAISSES. ACTIVITÉ NATURELLE LIMITÉE AU SOLEIL

2

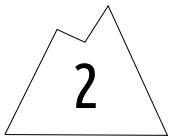

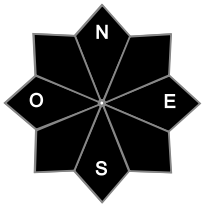

Indice de risque limité.

Départs spontanés : avalanches de neige humide au soleil, départs ponctuels ou linéaires, rarement de grande taille

Déclenchements provoqués : rares, mais pouvant mobiliser beaucoup de neige

Indices de risque : 5 très fort - 4 fort - 3 marqué - 2 limité - 1 faible -- En noir : les pentes les plus dangereuses

Stabilité du manteau neigeux

Situation avalancheuse typique : couche fragile persistante neige humide

Déclenchements provoqués :
Des instabilités persistent au-dessus de 2200/2300 m d'altitude. Elles sont plus nombreuses en versant ouest, nord et est. La plupart sont difficilement déclenchables par un seul skieur, mais elles peuvent générer des avalanches de taille moyenne à grande (taille 2 à 3), avec cassure épaisse et large, éventuellement à distance.
Le danger principal demeure la couche fragile persistante, enfouie dans la partie inférieure du manteau neigeux, voire au sol. La nette densification du manteau neigeux depuis les abondantes chutes de neige à la mi-février la rend nettement moins sollicitable. Les déclenchements, peu probables en milieu de pente, sont encore possibles dans les zones de plus faible enneigement, au niveau des discontinuités de terrain (croupes, rochers affleurants, transitions entre zones plus enneigées et moins enneigées), notamment dans la partie sud et est du massif.
En versants bien réchauffés par le soleil, notamment entre 2400 et 2800 m environ, un skieur peut également initier une avalanche de neige humide avec départ linéaire.

Départs spontanés : peu probables au petit matin, à l'exception de rares avalanches de glissement de taille 2 sur terrain favorable : sols herbeux, rochers lisses en versants sud raides. Activité en neige humide en hausse selon la course du soleil, mais probablement moins marquée que les jours précédents. Les départs, le plus souvent ponctuels près des rochers ou des barres et de taille 1 à 2, peuvent, plus rarement, engendrer des avalanches linéaires et jusqu'au sol de taille 2 à 3.

Qualité de la neige

L'enneigement est excédentaire pour un mois de février. En moyenne montagne, il faut remonter à 2018 (et localement 2014) pour trouver un enneigement encore plus abondant à cette période de l'année.
Hauteurs de neige observées : environ 100 cm à la Nivôse du Parpaillon à 2550 m, secteur soufflé par le vent.

Limite d'enneigement skiable vers 1200/1300 m en ubacs, plutôt 1600/1800 m en adrets.

État de la neige de surface: manteau neigeux printanier en adrets, bien regelé le matin, s'humifiant au soleil l'après-midi, sur une grande épaisseur en versants raides. En versants nord-est, nord et nord-ouest, le manteau neigeux est resté froid, ou humidifié / regelé seulement en surface sous 2000/2200 m. Plus haut, neige dense, souvent cartonnée ou durcie par les épisodes de vent passés. Neige encore d'aspect poudreux dense en limite supérieure de forêt ou dans les combes abritées du vent.

Aperçu météo pour le vendredi 27 février

	nuit	matin	après-midi	soir

Printanier : sec, ensoleillé et très doux, vent calme ou faible.

Pluie-Neige				
Iso 0 °C	3 100 m	3 000 m	2 900 m	2 800 m
Vent 2000 m	↖ 5 km/h	↖ 5 km/h	↗ 10 km/h	→ 5 km/h
Vent 3000 m	→ 10 km/h	→ 10 km/h	→ 15 km/h	↗ 20 km/h

Épaisseur de neige hors-piste

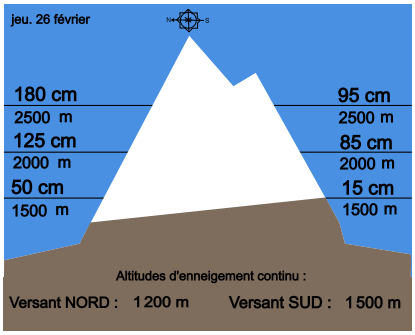

Précipitations à 1800 m

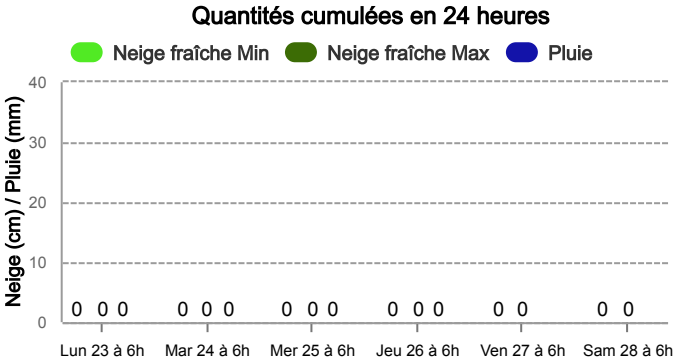

Tendance du samedi 28 février

2

Indice de risque limité

Risque en baisse pour la neige humide, avec le léger rafraîchissement de la masse d'air et la nébulosité. Maintien d'un risque limité en altitude en raison de la persistance des couches fragiles.

Pour consulter la vigilance en cours, veuillez vous rendre sur le site https://vigilance.meteofrance.fr/fr

Météo-France - 73 avenue de Paris, 94165 Saint-Mandé cedex - Contact : contact@meteo.fr

Rédigé par Météo-France avec la contribution des observateurs du réseau nivo-météorologiques. Partenariat : ANMSM (Maires de Stations de Montagne), DSF (Domaines Skiables de France), ADSP (Directeurs de Pistes et de la Sécurité des Stations de Sports d'Hiver) et autres acteurs de la montagne.

Bulletin neige & avalanches par téléphone au
0 892 68 10 20 Service 0,35 € / min + prix appel

RÉPUBLIQUE FRANÇAISE
Liberté Égalité Fraternité

METEO FRANCE
À VOS CÔTÉS, DANS UN CLIMAT QUI CHANGE

Bulletin d'estimation du risque d'avalanche
(valable en dehors des pistes balisées et ouvertes)
MASSIF : Embrunais Parpaillon

Rédigé le jeudi 26 février 2026 à 16h

Conditions nivo-météo des 7 derniers jours

	ven. 20/02				sam. 21/02				dim. 22/02				lun. 23/02				mar. 24/02				mer. 25/02				jeu. 26/02			
	03h	09h	15h	21h	03h	09h	15h	21h	03h	09h	15h	21h	03h	09h	15h	21h	03h	09h	15h	21h	03h	09h	15h	21h	03h	09h	15h	21h
Météo																												
Vent (km/h)	70	60	60	60	60	60	70	60	35	30	40	40	40	40	40	35	25	10	5	5	15	10	15	20	10	5	10	10
à 3000m																												
Vent (km/h)	25	50	40	50	40	25	25	45	15	10	10	10	10	10	0	10	15	20	0	10	10	5	5	10	5	5	5	5
à 2000m																												

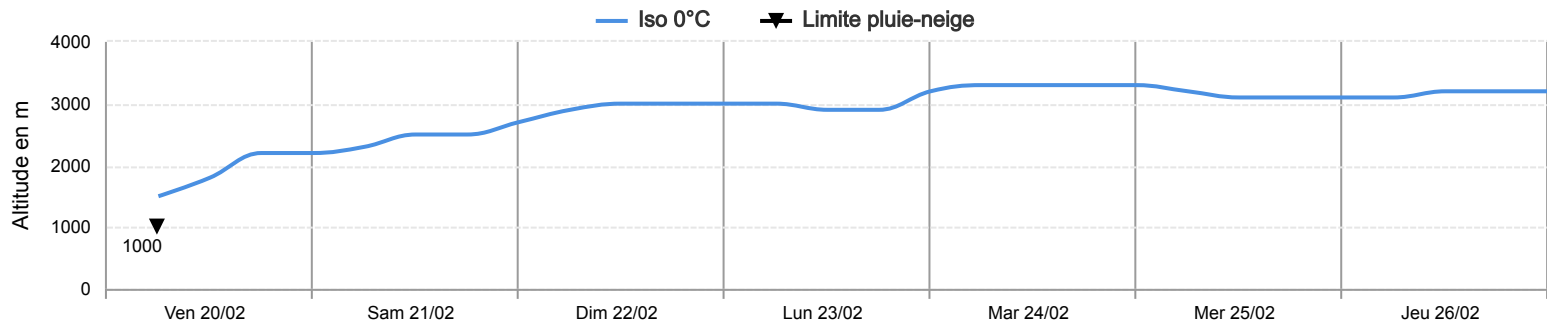

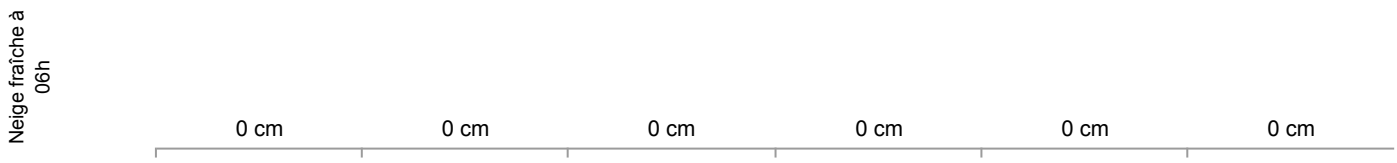

Risque d'avalanche	ven. 20/02	sam. 21/02	dim. 22/02	lun. 23/02	mar. 24/02	mer. 25/02	jeu. 26/02
	3	3	3	3	3	3	3

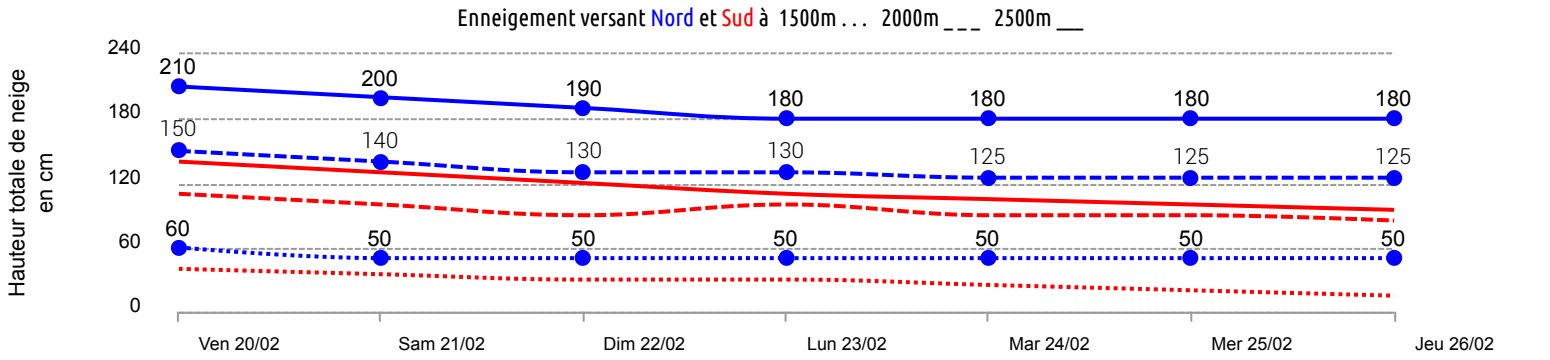

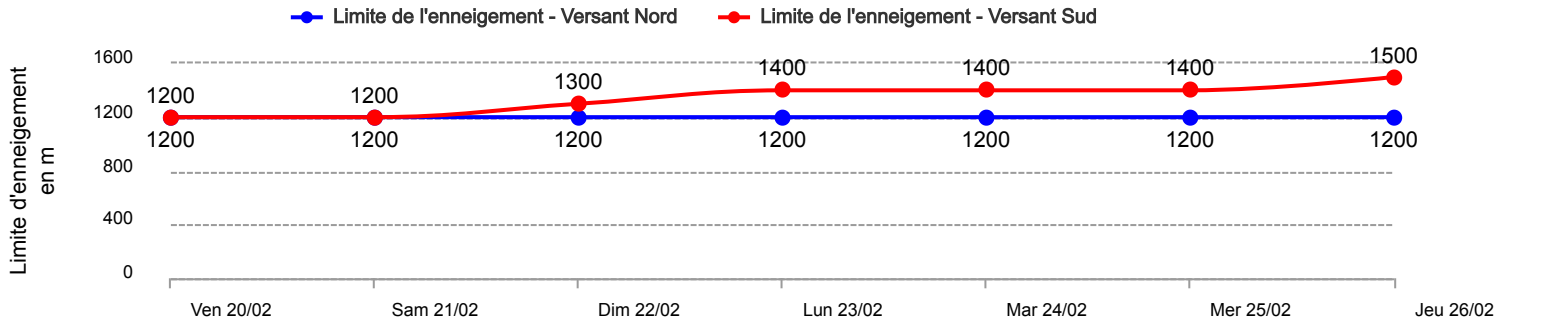

Pour consulter la vigilance en cours, veuillez vous rendre sur le site https://vigilance.meteofrance.fr/fr

Météo-France - 73 avenue de Paris, 94165 Saint-Mandé cedex - Contact : contact@meteo.fr

Rédigé par Météo-France avec la contribution des observateurs du réseau nivo-météorologiques. Partenariat : ANMSM (Maires de Stations de Montagne), DSF (Domaines Skiables de France), ADSP (Directeurs de Pistes et de la Sécurité des Stations de Sports d'Hiver) et autres acteurs de la montagne.

Bulletin neige & avalanches par téléphone au
0 892 68 10 20 Service 0,35 € / min + prix appel