Bulletin d'estimation du risque d'avalanche

(valable en dehors des pistes balisées et ouvertes)

MASSIF : Haut-Var Haut-Verdon

Rédigé le jeudi 26 février 2026 à 16h

Estimation des risques pour le : VENDREDI 27 FÉVRIER

MAINTIEN DE L'ACTIVITÉ EN NEIGE HUMIDE EN VERSANTS ENSOLEILLÉS, PARFOIS VOLUMINEUSE. EN UBACS, PLAQUES ÉPAISSES DIFFICILES À DÉCLENCHER.

2

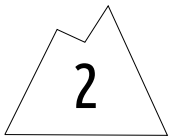

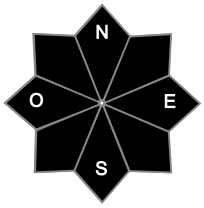

Indice de risque limité.

Départs spontanés : avalanches de neige humide et quelques avalanches de fond

Déclenchements provoqués : plaques épaisses en ubacs d'altitude, difficiles à déclencher + départs en neige humide

Indices de risque : 5 très fort - 4 fort - 3 marqué - 2 limité - 1 faible -- En noir : les pentes les plus dangereuses

Stabilité du manteau neigeux

Situation avalancheuse typique : neige humide couche fragile persistante

Départs spontanés :

- **avalanches de neige humide**, peu probables au levé du jour, puis devenant fréquentes au soleil en fil de la journée, affectant surtout les orientations est / sud / ouest. Départs ponctuels de taille petite à moyenne en général, mais de rares grand départs linéaires sont possibles en cas d'humidification d'une couche fragile persistante enfouie, notamment en versant est et ouest.
- **quelques avalanches de fond** suite à la rupture de reptations (gueules de baleine). Taille moyenne, voire grande. Possibles à n'importe quel moment du jour et de la nuit. En versant sud, plutôt au-dessous de 2500/2700 m. En versant nord, plutôt au-dessous de 2000 m.

Déclenchements provoqués :

- **plaques dures épaisses sur couche fragile persistante enfouie** encore présentes **plutôt sur le Haut-Verdon** dans les orientations ouest / nord / est au-dessus de 2000/2200 m. Déclenchement difficile au passage d'un skieur, mais restant localement possible là où le manteau neigeux est moins épais (croupes, bords de couloir), ou en cascade après un premier départ en surface. Avalanche de grande taille, cassure épaisse et large. Danger difficile à détecter.
- **en neige humide**. Un skieur peut également favoriser un départ superficiel en neige fortement humidifiée en pente raide ensoleillée, généralement de taille petite à moyenne.

Qualité de la neige

Enneigement très excédentaire pour un mois de février.
Données observées : 73 cm à Valberg à 1780 m, 123 cm vers les Cabanes de Sanguinière à 2040 m et 169 vers la Maison Forestière de Valdemars à 2020 m.

Enneigement skiable dès 1300/1400 m en terrains favorables, 1600 m en adrets.

État de la neige en surface : croute souvent portante le matin après un bon regel nocturne, s'humidifiant en journée au fil de l'ensoleillement. En ubacs au-dessus de 1800/2000 m environ, neige froide souvent travaillée/durcie par le vent de nord. Zones dégarnies proches des crêtes, alternant avec des corniches parfois épaisses.

Aperçu météo pour le vendredi 27 février

	nuit	matin	après-midi	soir
Temps sec et ensoleillé.				
Pluie-Neige				
Iso 0 °C	3 200 m	3 000 m	3 000 m	2 900 m
Vent 2000 m	→ 5 km/h	↓ 5 km/h	→ 5 km/h	↖ 5 km/h
Vent 3000 m	↘ 10 km/h	↘ 10 km/h	→ 10 km/h	↘ 10 km/h

Épaisseur de neige hors-piste

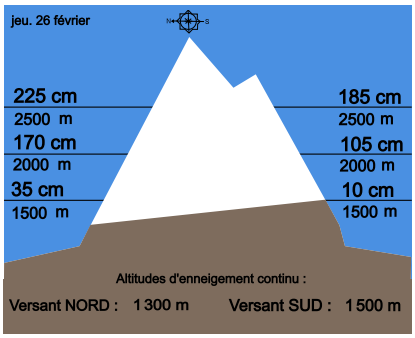

Précipitations à 1800 m

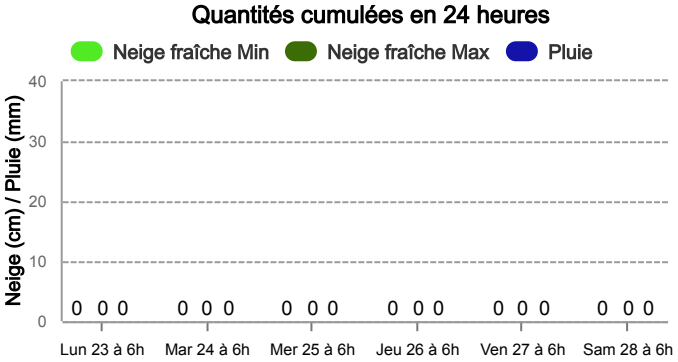

Tendance du samedi 28 février

2

Indice de risque limité

Encore un peu d'activité en neige humide, malgré la légère baisse des températures. Toujours de rares plaques épaisses en ubacs d'altitude.

Pour consulter la vigilance en cours, veuillez vous rendre sur le site https://vigilance.meteofrance.fr/fr

Météo-France - 73 avenue de Paris, 94165 Saint-Mandé cedex - Contact : contact@meteo.fr

Rédigé par Météo-France avec la contribution des observateurs du réseau nivo-météorologiques. Partenariat : ANMSM (Maires de Stations de Montagne), DSF (Domaines Skiables de France), ADSP (Directeurs de Pistes et de la Sécurité des Stations de Sports d'Hiver) et autres acteurs de la montagne.

Bulletin neige & avalanches par téléphone au **0 892 68 10 20** Service 0,35 € / min + prix appel

RÉPUBLIQUE FRANÇAISE
Liberté Égalité Fraternité

METEO FRANCE
À VOS CÔTÉS, DANS UN CLIMAT QUI CHANGE

Bulletin d'estimation du risque d'avalanche

(valable en dehors des pistes balisées et ouvertes)

MASSIF : Haut-Var Haut-Verdon

Rédigé le jeudi 26 février 2026 à 16h

Conditions nivo-météo des 7 derniers jours

	ven. 20/02				sam. 21/02				dim. 22/02				lun. 23/02				mar. 24/02				mer. 25/02				jeu. 26/02			
	03h	09h	15h	21h	03h	09h	15h	21h	03h	09h	15h	21h	03h	09h	15h	21h	03h	09h	15h	21h	03h	09h	15h	21h	03h	09h	15h	21h
Météo																												
Vent (km/h)	90	75	50	30	55	60	55	40	40	40	45	50	45	40	30	25	35	25	10	10	15	10	10	10	10	10	10	10
à 3000m																												
Vent (km/h)	50	35	20	20	20	20	25	20	20	25	25	25	30	30	25	15	15	10	5	5	10	5	5	5	5	5	5	5
à 2000m																												

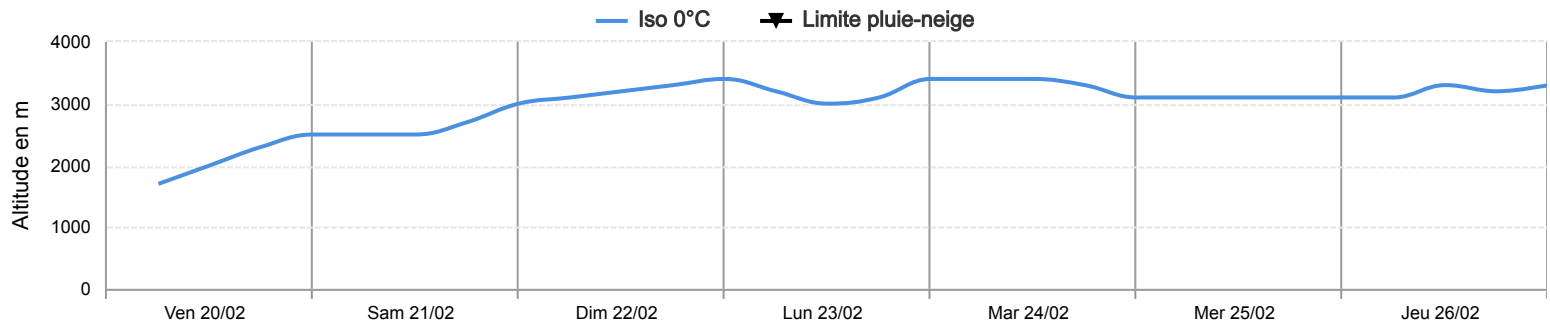

Neige fraîche à 06h

0 cm	0 cm	0 cm	0 cm	0 cm	0 cm

Risque d'avalanche	ven. 20/02	sam. 21/02	dim. 22/02	lun. 23/02	mar. 24/02	mer. 25/02	jeu. 26/02
	3	3	3	3	3	3	3

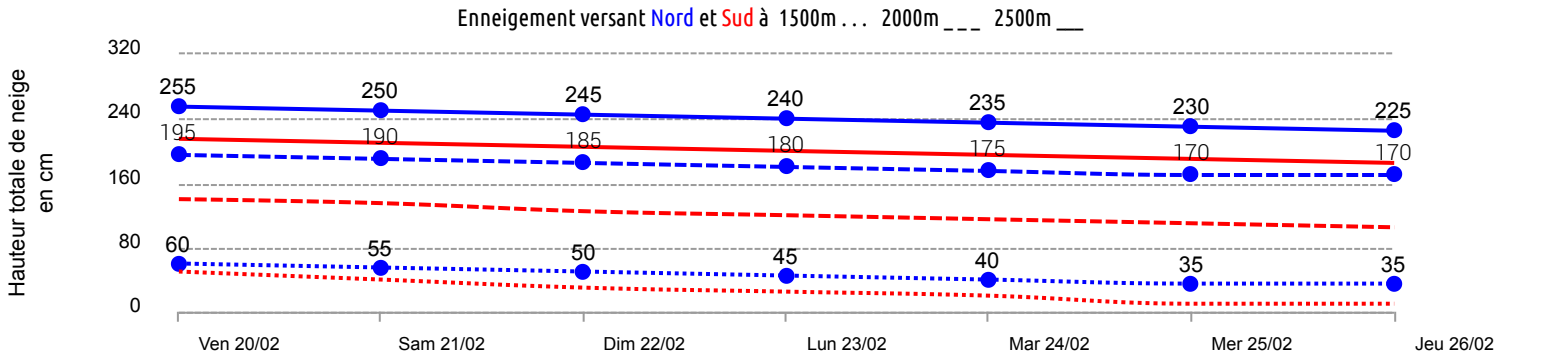

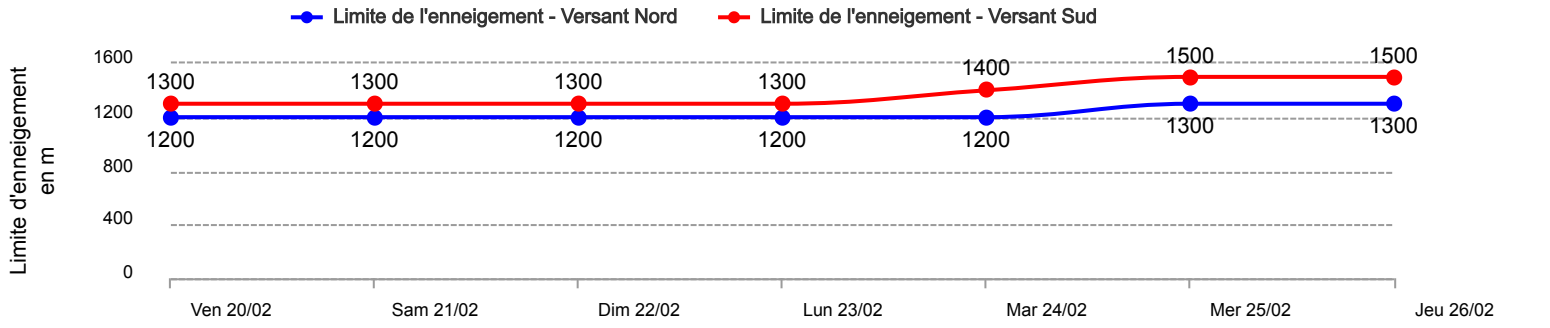

Pour consulter la vigilance en cours, veuillez vous rendre sur le site https://vigilance.meteofrance.fr/fr

Météo-France - 73 avenue de Paris, 94165 Saint-Mandé cedex - Contact : contact@meteo.fr

Bulletin neige & avalanches par téléphone au

0 892 68 10 20 Service 0,35 € / min + prix appel

Rédigé par Météo-France avec la contribution des observateurs du réseau nivo-météorologiques. Partenariat : ANMSM (Maires de Stations de Montagne), DSF (Domaines Skiables de France), ADSP (Directeurs de Pistes et de la Sécurité des Stations de Sports d'Hiver) et autres acteurs de la montagne.