Bulletin d'estimation du risque d'avalanche
(valable en dehors des pistes balisées et ouvertes)

MASSIF : Haute-Bigorre

Rédigé le jeudi 26 février 2026 à 16h

Estimation des risques pour le : VENDREDI 27 FÉVRIER

MANTEAU NEIGEUX PRINTANIER DANS UN LARGE SECTEUR SUD, STRUCTURES DE PLAQUES ENCORE POSSIBLES A L'OMBRE EN ALTITUDE.

2

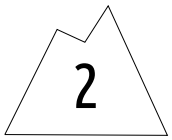

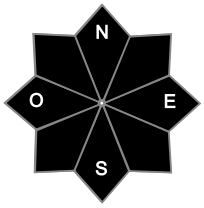

Indice de risque limité.

Départs spontanés : En neige humide au soleil, avalanches de fond possibles.

Déclenchements provoqués : Plaques encore présentes en altitude.

Indices de risque : 5 très fort - 4 fort - 3 marqué - 2 limité - 1 faible -- En noir : les pentes les plus dangereuses

Stabilité du manteau neigeux

Situation avalancheuse typique : couche fragile persistante neige humide

Déclenchements provoqués : **Au-dessus de 2200 à 2300m**, des plaques à vent sont encore en place dans les pentes raides des secteurs ombragés (versants allant du Nord-Ouest au Nord-Est). Elles peuvent être déclenchées par un simple skieur et par sollicitation faible à moyenne. Elles peuvent reposer sur des couches de neige avec moins de cohésion, constituées de neige frittée et roulée, ainsi que de grains anguleux. Leur déclenchement peut engendrer des cassures linéaires petites à moyennes. Il n'est pas exclu de rencontrer ces plaques aussi dans les versants Est et Ouest.
Un simple skieur peut aussi déclencher de petites avalanches dans la neige humide dans les versants Sud à Sud-Ouest l'après-midi.

Départs spontanés : **Au-dessus de 2200 à 2300m**, des départs ponctuels de plaques décrites ci-dessus restent possibles, par surcharge par le vent, engendrant des avalanches petites à moyennes.
Des départs ponctuels dans la neige humide sont attendus dans les pentes raides au fil de l'ensoleillement, concernant d'abord les pentes Est à Sud, puis rapidement les autres versants au fil de la journée. Des avalanches de petites tailles, parfois moyennes sont possibles.
Quelques **avalanches de fond,** avec cassure linéaire emportant la totalité du manteau neigeux en place, sont possibles en tous versants, en partant d'une accumulation importante et persistante en altitude.

Autres : **Très bon regel nocturne** du manteau neigeux humidifié dans la journée de jeudi, **propice aux glissades en début de journée** sous 2300m en Nord, 2500m en Sud, souvent **persistant dans les pentes raides à l'ombre.**

Qualité de la neige

Enneigement : très bon pour la saison au regard de ces derniers hivers. Avec le beau temps, fonte très limitée à l'ombre au-delà de 1500m, plus prononcée dans les versants d'un large secteur Sud. Le manteau neigeux s'amincit très doucement dans les pentes bien ensoleillées, la fonte est lente et progressive. Crêtes, cols et sommets pelés et en neige dure en expositions ouest.
Limites skiables : à partir de 1300 à 1500m au petit matin suivant les versants.
État de la neige : Neige regelée à dure jusqu'à 2300m en Nord le matin, pouvant aller jusqu'à 2500m en Sud. Persistance de neige durcie en journée dans les pentes raides à l'ombre. Neige s'humidifiant ensuite au fil de la journée, devenant lourde et poursuivant son humidification en profondeur. Neige sèche ou poudreuse dans les pentes raides des secteurs ombragés au-dessus de 2300m, pouvant être encore bien travaillée par le vent et restant en l'état malgré la douceur ambiante.

Aperçu météo pour le vendredi 27 février

	nuit	matin	après-midi	soir

Temps sec, bien ensoleillé jusqu'en fin d'après-midi. Arrivée d'une dégradation en fin de journée, quelques averses. Vent faible de Sud-Ouest.

Pluie-Neige			2 000 m	1 900 m
Iso 0 °C	3 100 m	3 000 m	2 700 m	2 300 m
Vent 2000 m	↗ 20 km/h	↑ 25 km/h	↗ 20 km/h	↑ 10 km/h
Vent 3000 m	↗ 40 km/h	↑ 40 km/h	↗ 30 km/h	↑ 30 km/h

Épaisseur de neige hors-piste

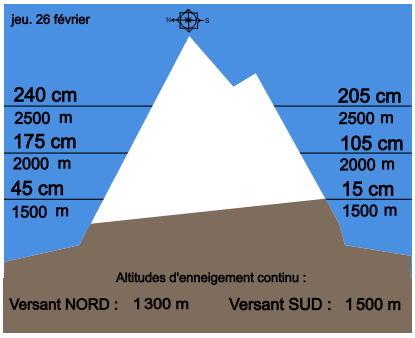

Précipitations à 1800 m

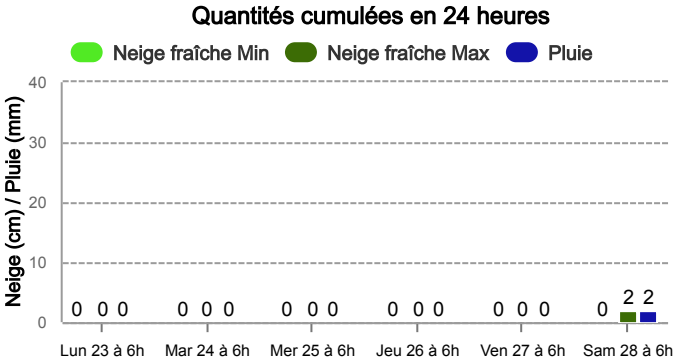

Tendance du samedi 28 février

2

Indice de risque limité

Maintien d'un risque limité. Temps faiblement perturbé dans la nuit de vendredi à samedi ainsi que samedi. Quelques averses attendues.

Pour consulter la vigilance en cours, veuillez vous rendre sur le site https://vigilance.meteofrance.fr/fr

Météo-France - 73 avenue de Paris, 94165 Saint-Mandé cedex - Contact : contact@meteo.fr

Rédigé par Météo-France avec la contribution des observateurs du réseau nivo-météorologiques. Partenariat : ANMSM (Maires de Stations de Montagne), DSF (Domaines Skiables de France), ADSP (Directeurs de Pistes et de la Sécurité des Stations de Sports d'Hiver) et autres acteurs de la montagne.

Bulletin neige & avalanches par téléphone au
0 892 68 10 20 Service 0,35 € / min + prix appel

Bulletin d'estimation du risque d'avalanche

(valable en dehors des pistes balisées et ouvertes)

MASSIF : Haute-Bigorre

Rédigé le jeudi 26 février 2026 à 16h

Conditions nivo-météo des 7 derniers jours

	ven. 20/02				sam. 21/02				dim. 22/02				lun. 23/02				mar. 24/02				mer. 25/02				jeu. 26/02			
	03h	09h	15h	21h	03h	09h	15h	21h	03h	09h	15h	21h	03h	09h	15h	21h	03h	09h	15h	21h	03h	09h	15h	21h	03h	09h	15h	21h
Météo																												
Vent (km/h)	30	55	55	35	15	10	15	15	15	15	25	30	25	15	25	20	60	45	35	30	30	25	30	30	30	30	35	45
à 3000m																												
Vent (km/h)	25	10	15	5	2	5	5	5	10	10	10	15	10	5	20	15	30	25	20	20	15	15	15	15	15	15	20	30
à 2000m																												

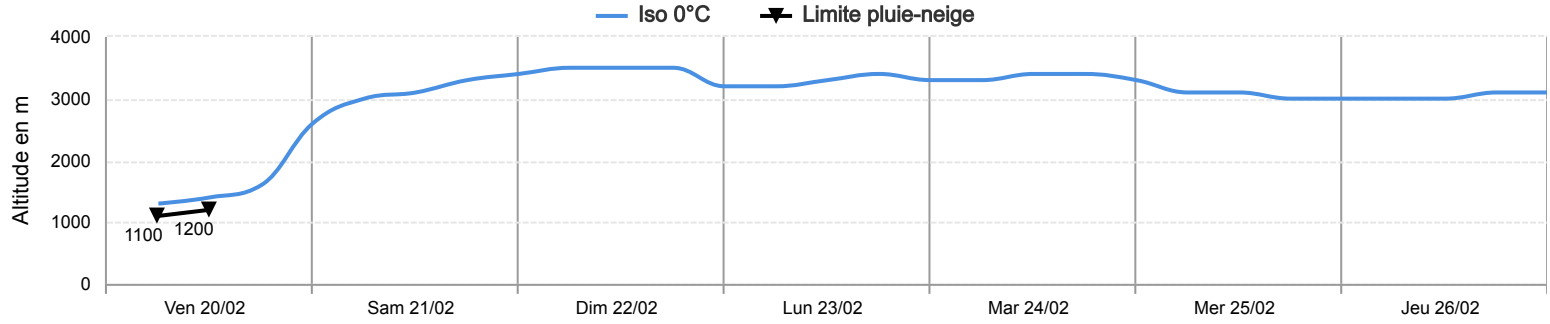

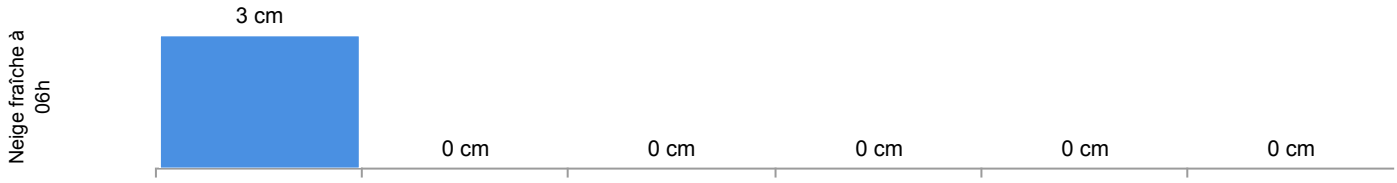

Risque d'avalanche	ven. 20/02	sam. 21/02	dim. 22/02	lun. 23/02	mar. 24/02	mer. 25/02	jeu. 26/02
	3	3	3	3	2	2	2

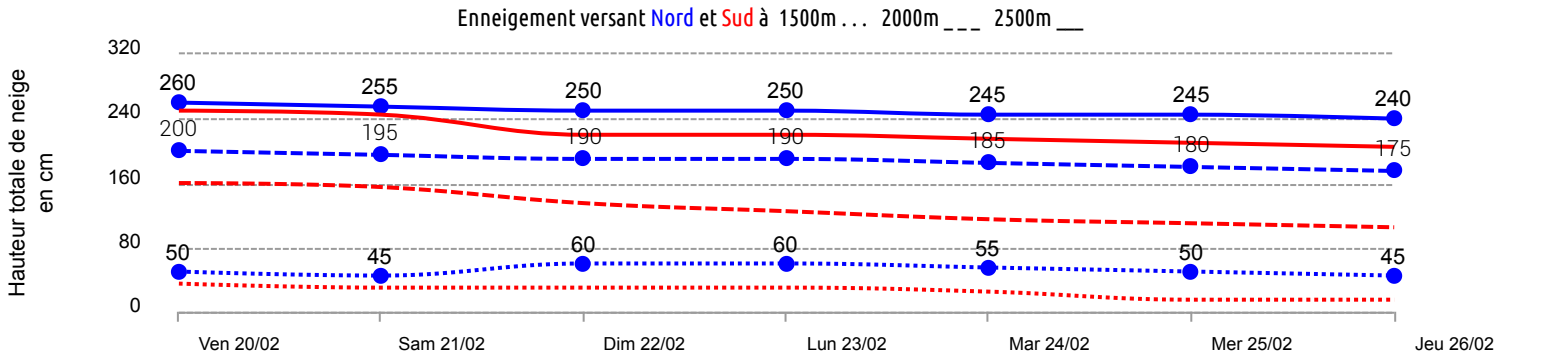

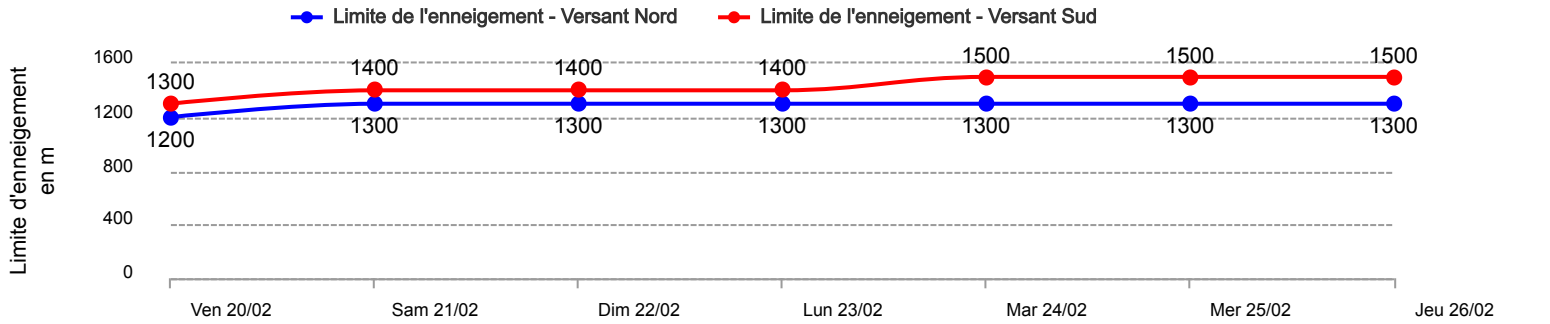

Pour consulter la vigilance en cours, veuillez vous rendre sur le site https://vigilance.meteofrance.fr/fr

Météo-France - 73 avenue de Paris, 94165 Saint-Mandé cedex - Contact : contact@meteo.fr

Rédigé par Météo-France avec la contribution des observateurs du réseau nivo-météorologiques. Partenariat : ANMSM (Maires de Stations de Montagne), DSF (Domaines Skiables de France), ADSP (Directeurs de Pistes et de la Sécurité des Stations de Sports d'Hiver) et autres acteurs de la montagne.

Bulletin neige & avalanches par téléphone au

0 892 68 10 20 Service 0,35 € / min + prix appel