Bulletin d'estimation du risque d'avalanche

(valable en dehors des pistes balisées et ouvertes)

MASSIF : Mont-Blanc

Rédigé le jeudi 26 février 2026 à 16h

Estimation des risques pour le : VENDREDI 27 FÉVRIER

MANTEAU NEIGEUX RÉACTIF AU RÉCHAUFFEMENT

3

2→3

N O E S

Indice de risque limité évoluant en marqué.

Départs spontanés : avalanches de neige humide et plaques de fond

Déclenchements provoqués : coulée humides + anciennes plaques peu réactives mais épaisses

Indices de risque : 5 très fort - 4 fort - 3 marqué - 2 limité - 1 faible -- En noir : les pentes les plus dangereuses

Stabilité du manteau neigeux

Situation avalancheuse typique : neige humide avalanches de fond

Départs spontanés :

* **avalanches de neige humide**, dès la fin de matinée, en suivant la course du soleil. Versants S raides : toutes altitudes. Versant N : sous 2200 m. La plupart en forme de poire, mais pouvant s'élargir nettement jusqu'à entraîner une plaque en contrebas. Taille 2 (moyenne), voire 3 (grande) en cas de grande pente pas encore purgée. Ces avalanches partent spontanément au réchauffement, mais aussi au passage d'un skieur. *Observables :* escargots, départs souvent près des rochers/falaises réchauffés.
* **plaques de fond**. Surtout l'après-midi, mais possibles à n'importe quelle heure. Sur terrains raides et lisses en herbes ou dalles rocheuses. Versants E, NE : en dessous de 2000 m. Versants SE, S, SW, W : en dessous de 2300/2400 m. Taille 2 à 3..
* **chutes de corniches**, épaisses et volumineuses, pouvant entraîner une plaque en contrebas.

Déclenchements provoqués :

* **plaques dures sur couche fragile persistante enfouie**. Versants W/N/E, au-dessus de 2000/2200 m. Peu probables, car cette ancienne couche fragile est généralement bien enfouie. MAIS une première plaque de surface peut en déclencher une autre plus épaisse (80/150 cm). L'épaisseur de ces plaques peut varier du simple au double entre le centre et les bords. Taille 2 à 3.

Qualité de la neige

Enneigement : bon pour une fin février. On peut chausser les skis vers 1200/1300 m. Poursuite du tassement sous l'effet de la douceur, grosses corniches, arêtes érodées par les forts vents pendant et après les perturbations (de SW puis NW/N).

Qualité de la neige vendredi :

* qualité du ski : pas facile, avec des croûtes cassantes, surplombant une neige par encore complètement tassée (en E et W) voire très humide (en S).
* sous 2200/2300 m : neige dense, croûtée le matin, s'humidifiant rapidement. Tendance à l'humidification en profondeur.
* au-dessus de 2200/2400 m : variable, neige dense, encore assez froide. Humidification superficielle en adrets. Cartonnée dans les secteurs qui ont été exposés aux vents de W/NW/N.

Aperçu météo pour le vendredi 27 février

Soleil et grande douceur. +8 DG à 2000 m, -3 à l'Aiguille du Midi.

	nuit	matin	après-midi	soir
Pluie-Neige				
Iso 0 °C	3 000 m	3 000 m	3 000 m	2 700 m
Vent 2000 m	↑ 10 km/h	↑ 10 km/h	↗ 20 km/h	↗ 20 km/h
Vent 4000 m	↗ 30 km/h	↓ 30 km/h	↗ 40 km/h	↗ 40 km/h

Épaisseur de neige hors-piste

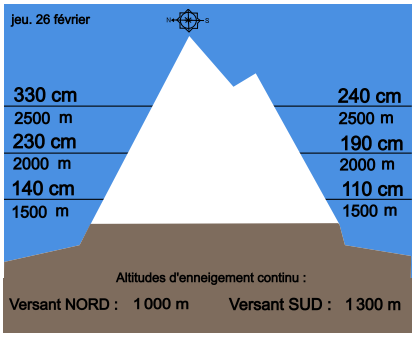

Précipitations à 1800 m

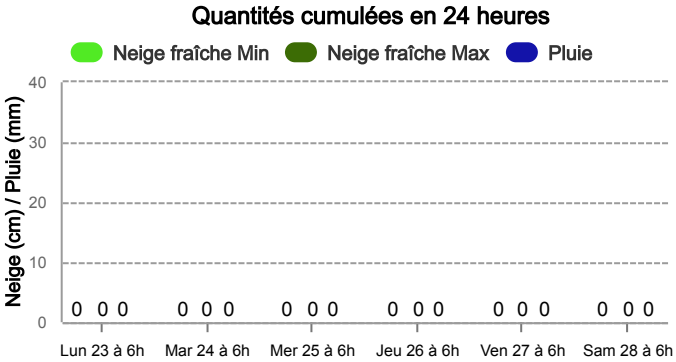

Tendance du samedi 28 février

3

Indice de risque marqué

Un peu plus frais, risque en légère baisse.

Pour consulter la vigilance en cours, veuillez vous rendre sur le site https://vigilance.meteofrance.fr/fr

Météo-France - 73 avenue de Paris, 94165 Saint-Mandé cedex - Contact : contact@meteo.fr

Rédigé par Météo-France avec la contribution des observateurs du réseau nivo-météorologiques. Partenariat : ANMSM (Maires de Stations de Montagne), DSF (Domaines Skiables de France), ADSP (Directeurs de Pistes et de la Sécurité des Stations de Sports d'Hiver) et autres acteurs de la montagne.

Bulletin neige & avalanches par téléphone au 0 892 68 10 20 Service 0,35 € / min + prix appel

RÉPUBLIQUE FRANÇAISE
Liberté Égalité Fraternité

METEO FRANCE
À VOS CÔTÉS, DANS UN CLIMAT QUI CHANGE

Bulletin d'estimation du risque d'avalanche

(valable en dehors des pistes balisées et ouvertes)

MASSIF : Mont-Blanc

Rédigé le jeudi 26 février 2026 à 16h

Conditions nivo-météo des 7 derniers jours

	ven. 20/02				sam. 21/02				dim. 22/02				lun. 23/02				mar. 24/02				mer. 25/02				jeu. 26/02			
	03h	09h	15h	21h	03h	09h	15h	21h	03h	09h	15h	21h	03h	09h	15h	21h	03h	09h	15h	21h	03h	09h	15h	21h	03h	09h	15h	21h
Météo																												
Vent (km/h)	90	80	80	85	70	80	100	100	75	60	60	65	60	60	60	70	70	60	40	30	20	20	20	20	20	20	30	30
à 4000m																												
Vent (km/h)	20	20	20	20	20	25	30	30	20	20	20	20	25	25	25	20	10	10	10	10	10	10	10	10	10	10	10	10
à 2000m																												

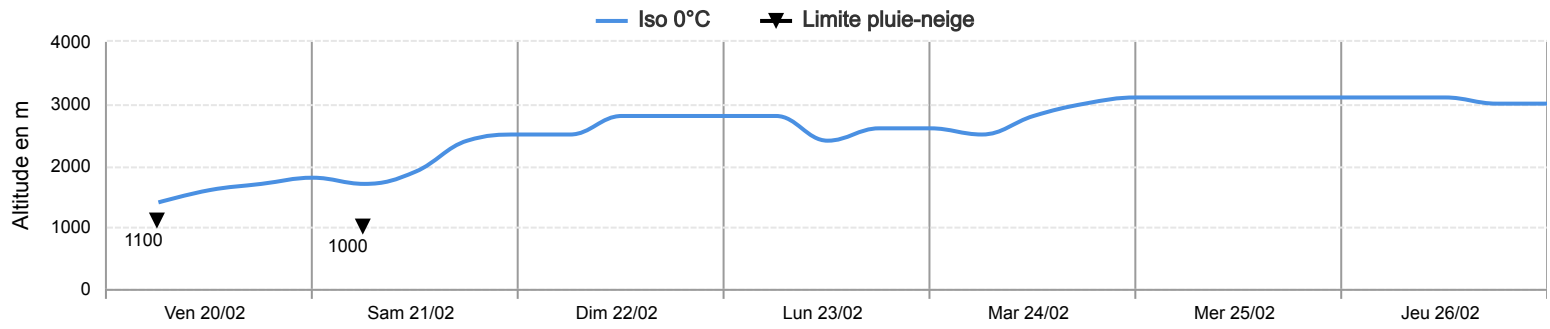

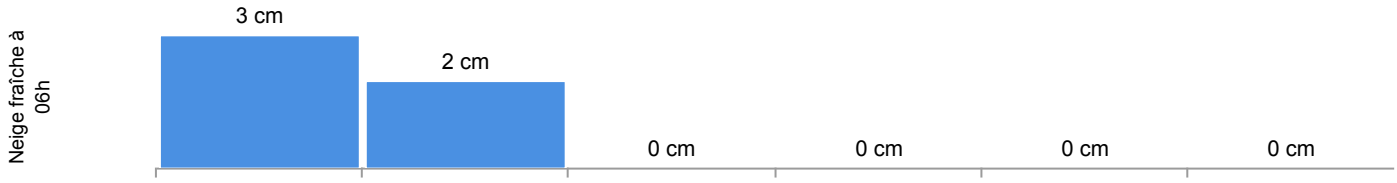

Risque d'avalanche							
	ven. 20/02	sam. 21/02	dim. 22/02	lun. 23/02	mar. 24/02	mer. 25/02	jeu. 26/02

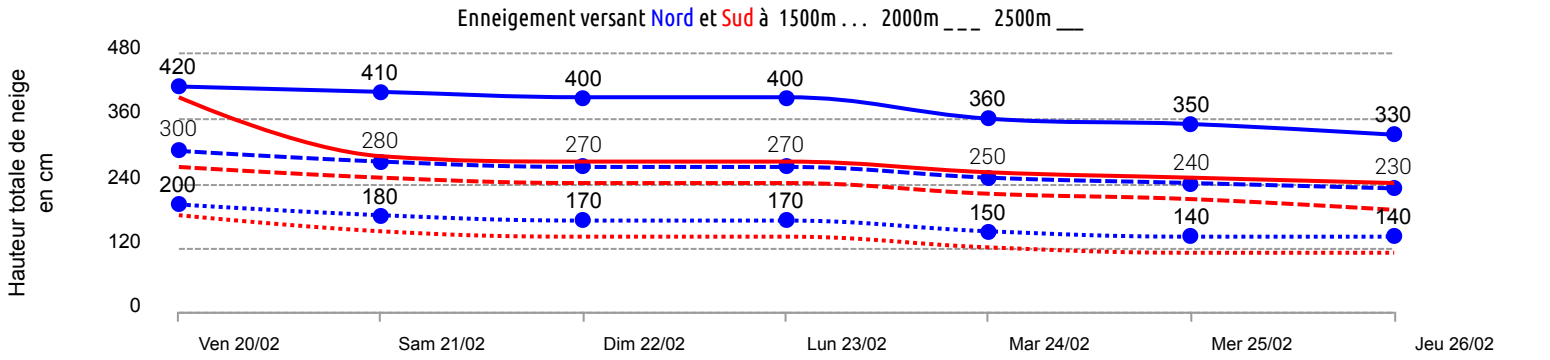

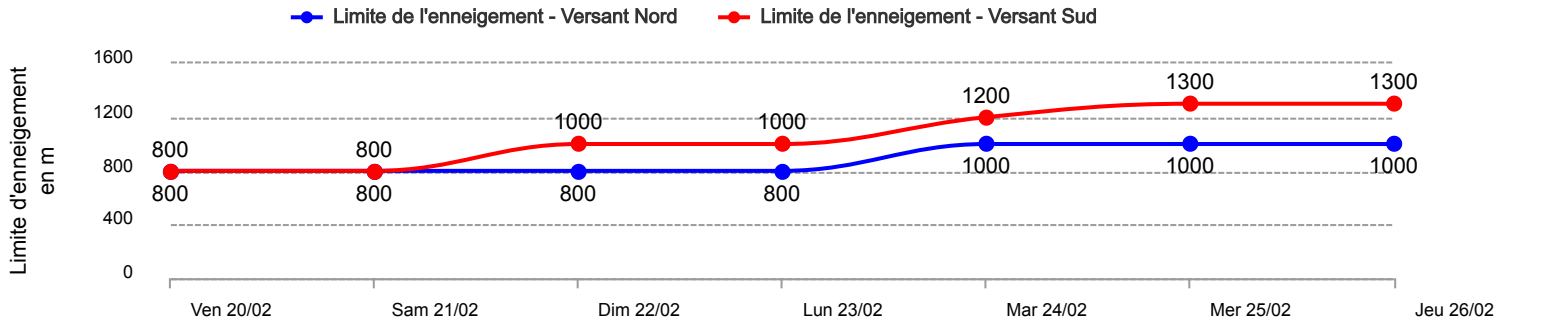

Pour consulter la vigilance en cours, veuillez vous rendre sur le site https://vigilance.meteofrance.fr/fr

Météo-France - 73 avenue de Paris, 94165 Saint-Mandé cedex - Contact : contact@meteo.fr

Bulletin neige & avalanches par téléphone au **0 892 68 10 20** Service 0,35 € / min + prix appel

Rédigé par Météo-France avec la contribution des observateurs du réseau nivo-météorologiques. Partenariat : ANMSM (Maires de Stations de Montagne), DSF (Domaines Skiables de France), ADSP (Directeurs de Pistes et de la Sécurité des Stations de Sports d'Hiver) et autres acteurs de la montagne.