Bulletin d'estimation du risque d'avalanche

(valable en dehors des pistes balisées et ouvertes)

MASSIF : Oisans

Rédigé le jeudi 26 février 2026 à 16h

Estimation des risques pour le : VENDREDI 27 FÉVRIER

DEPARTS EN NEIGE HUMIDE DANS LA NEIGE RÉCENTE, DE RARES PLAQUES EN VERSANTS FROIDS D'ALTITUDE.

2

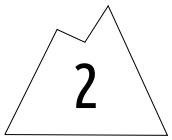

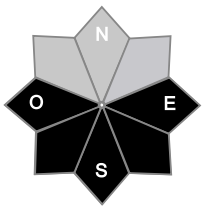

pentes au soleil

Indices de risque : 5 très fort - 4 fort - 3 marqué - 2 limité - 1 faible -- En noir : les pentes les plus dangereuses

Indice de risque limité.

Départs spontanés : Avalanches humides, départ possible au terrain. Risque de rupture de corniche.

Déclenchements provoqués : Quelques instabilités encore présentes en altitude, avec rarement, des cassures épaisses. Ou sous les skis dans la neige humide.

Stabilité du manteau neigeux

Situation avalancheuse typique : neige humide couche fragile persistante

Départs spontanés : Avec la période de grande douceur qui se prolonge, et l'humidification qui gagne en profondeur, des avalanches de neige humide restent possibles, plus probables en cours de journée dans les pentes réchauffées par le soleil. Localement en terrain herbeux / secteur de reptation de moyenne altitude, un départ d'une avalanche de fond reste possible à toute heure du jour ou de la nuit. A signaler également un risque de rupture de corniche près des crêtes sommitales, pouvant déclencher une avalanche en contrebas. Plus bas que 1800/2000 m, le risque semble être un peu plus limité, la neige s'y étant davantage transformée avec le redoux.

Déclenchements provoqués : De rares instabilités restent présentes sous les importantes quantités de neige récente tombée la semaine dernière, encore possibles dans de nombreuses orientations à l'exception des versants plein Sud. Ces plaques, parfois très épaisses dans les zones d'accumulations, reposent sur des couches fragiles persistantes enfouies. Leur stabilisation est assez lente, en particulier dans les versants ombragés d'altitude au-dessus de 2200/2300 m. Ainsi, on ne peut exclure qu'un skieur isolé ou un groupe de skieurs puisse les solliciter localement. Par exemple, dans les secteurs où l'épaisseur du manteau neigeux est un peu moins importante, permettant de les atteindre plus facilement : en bord de zone d'accumulation, à proximité des rochers, ou dans des ruptures de pentes. Plus bas que 2200 m en revanche, le risque principal est plutôt de faire couler de la neige humide sous les skis en évoluant l'après-midi dans une pente réchauffée.

Qualité de la neige

Qualification de l'enneigement : l'enneigement commence à régresser tout en bas, mais est bon pour la saison dès 1200 m, voire abondant au dessus de 1500 m environ, notamment dans les combes d'altitude. On trouve des crêtes un peu dégarnies par le vent, ou au contraire des corniches assez conséquentes.

Limites skiables : vers 1300/1400 m.

Qualité de la neige vendredi : Sous 2000/2400 m voire plus haut en Sud, neige humide avec un cycle de printemps, parfois croûtée en début de journée (regel pouvant être correct en l'absence de vent et sous ciel dégagé). L'humidification reprend en journée, plus marquée au soleil et gagnant en profondeur. Dans les versants ombragés au-dessus de 2000/2400 m, neige restée davantage poudreuse, bien que de plus en plus tassée/densifiée au fil des jours. A proximité des crêtes, neige parfois soufflée ou travaillée par le vent.

Aperçu météo pour le vendredi 27 février

	nuit	matin	après-midi	soir

Belle journée ensoleillée avec encore une grande douceur.

Pluie-Neige				
Iso 0 °C	3 100 m	3 200 m	3 000 m	2 900 m
Vent 2500 m	↓ 5 km/h	↓ 0 km/h	↘ 5 km/h	↓ 5 km/h
Vent 3500 m	↑ 10 km/h	→ 5 km/h	↗ 15 km/h	↑ 15 km/h

Épaisseur de neige hors-piste

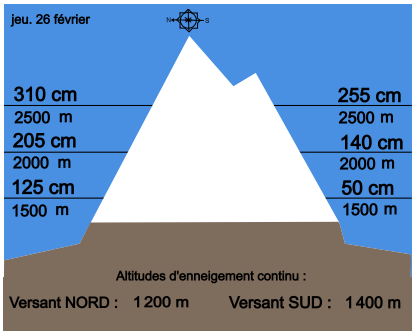

Précipitations à 1800 m

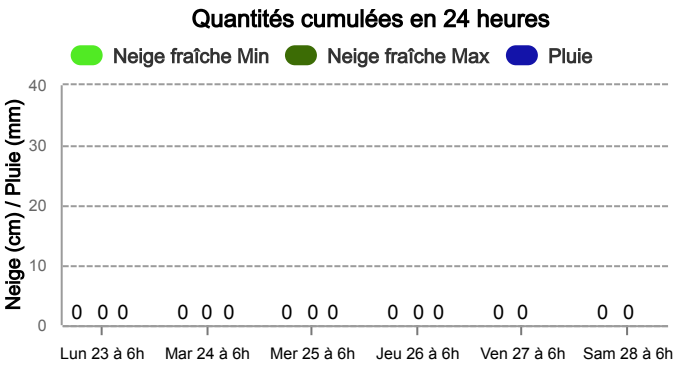

Tendance du samedi 28 février

2

Indice de risque limité

Satbilisation en cours avec l'humidification et le tassement du manteau.

Pour consulter la vigilance en cours, veuillez vous rendre sur le site https://vigilance.meteofrance.fr/fr

Météo-France - 73 avenue de Paris, 94165 Saint-Mandé cedex - Contact : contact@meteo.fr

Rédigé par Météo-France avec la contribution des observateurs du réseau nivo-météorologiques. Partenariat : ANMSM (Maires de Stations de Montagne), DSF (Domaines Skiables de France), ADSP (Directeurs de Pistes et de la Sécurité des Stations de Sports d'Hiver) et autres acteurs de la montagne.

Bulletin neige & avalanches par téléphone au

0 892 68 10 20 Service 0,35 € / min + prix appel

RÉPUBLIQUE FRANÇAISE
Liberté Égalité Fraternité

METEO FRANCE
À VOS CÔTÉS, DANS UN CLIMAT QUI CHANGE

Bulletin d'estimation du risque d'avalanche
(valable en dehors des pistes balisées et ouvertes)

MASSIF : Oisans

Rédigé le jeudi 26 février 2026 à 16h

Conditions nivo-météo des 7 derniers jours

	ven. 20/02				sam. 21/02				dim. 22/02				lun. 23/02				mar. 24/02				mer. 25/02				jeu. 26/02			
	03h	09h	15h	21h	03h	09h	15h	21h	03h	09h	15h	21h	03h	09h	15h	21h	03h	09h	15h	21h	03h	09h	15h	21h	03h	09h	15h	21h
Météo																												
Vent (km/h)	85	80	80	80	70	65	65	50	40	35	35	30	35	35	35	25	40	20	15	10	10	10	15	15	10	5	5	5
à 3500m																												
Vent (km/h)	70	70	70	75	55	45	40	35	25	25	20	20	20	20	25	20	25	15	10	5	5	5	10	5	5	0	0	5
à 2500m																												

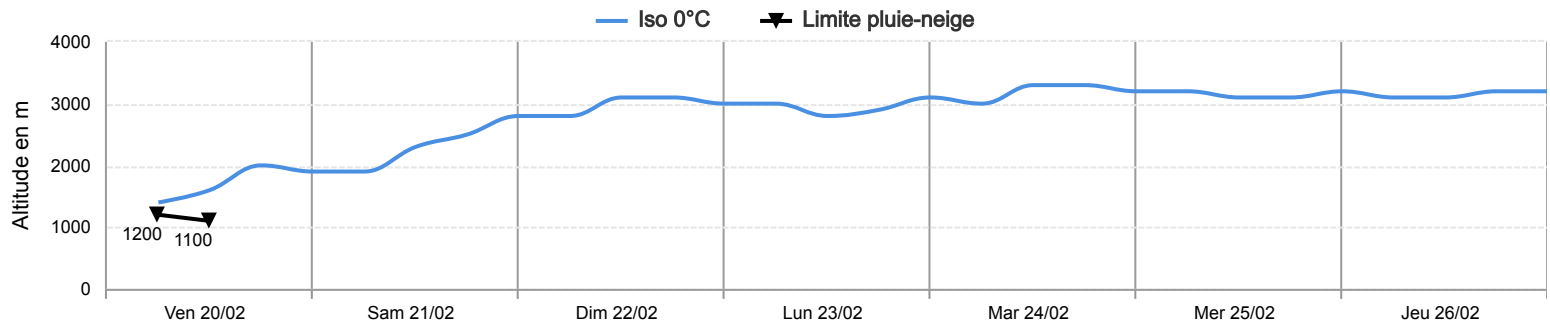

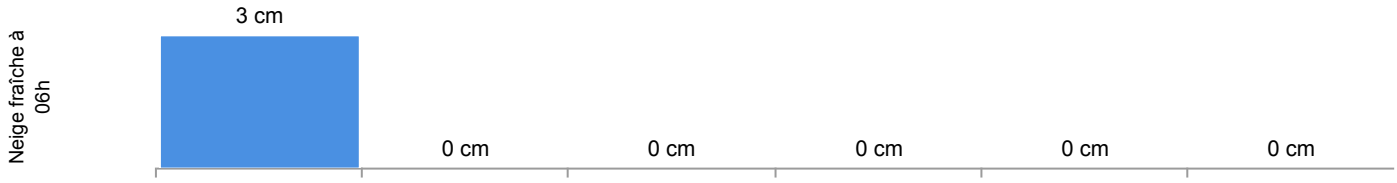

Risque d'avalanche	ven. 20/02	sam. 21/02	dim. 22/02	lun. 23/02	mar. 24/02	mer. 25/02	jeu. 26/02
	5	4	3	3	3	3	3

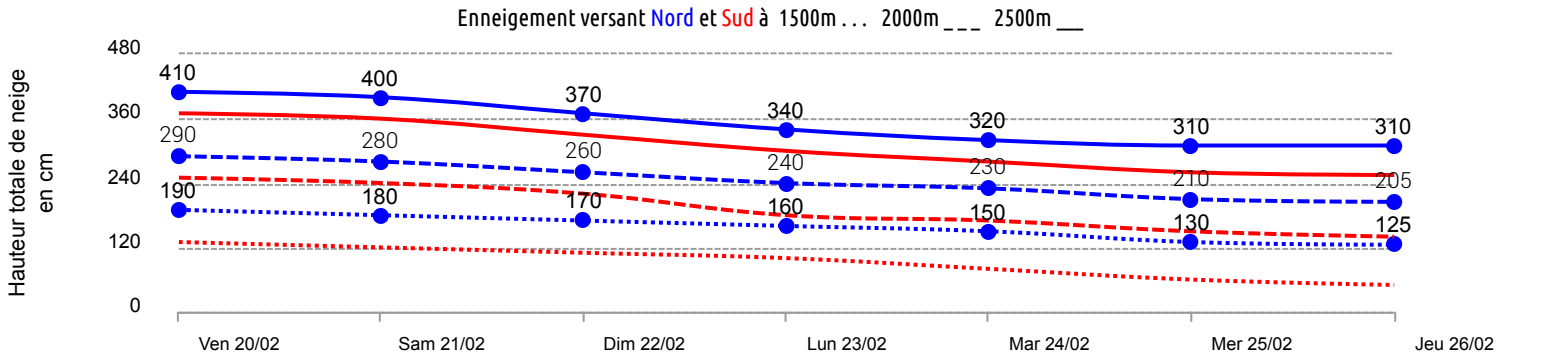

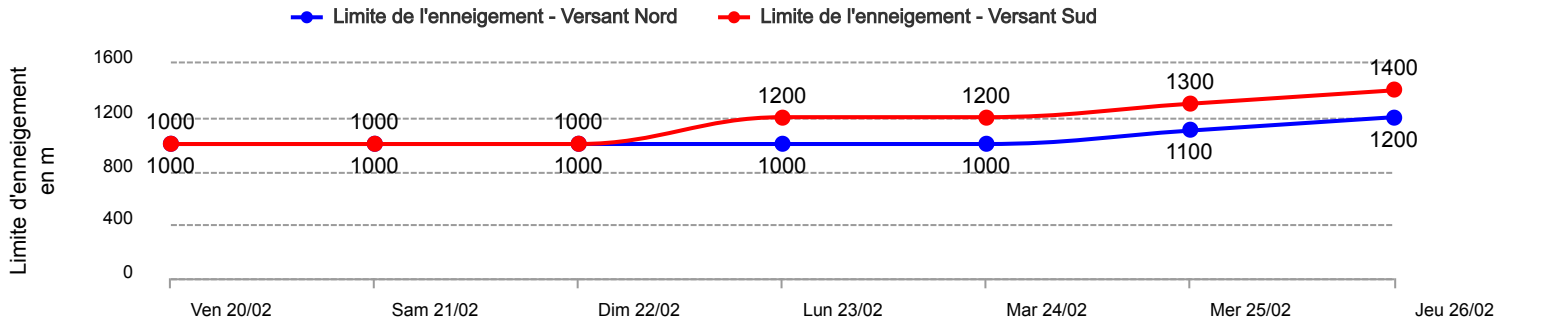

Pour consulter la vigilance en cours, veuillez vous rendre sur le site https://vigilance.meteofrance.fr/fr

Météo-France - 73 avenue de Paris, 94165 Saint-Mandé cedex - Contact : contact@meteo.fr

Bulletin neige & avalanches par téléphone au
0 892 68 10 20 Service 0,35 € / min + prix appel

Rédigé par Météo-France avec la contribution des observateurs du réseau nivo-météorologiques. Partenariat : ANMSM (Maires de Stations de Montagne), DSF (Domaines Skiables de France), ADSP (Directeurs de Pistes et de la Sécurité des Stations de Sports d'Hiver) et autres acteurs de la montagne.