Bulletin d'estimation du risque d'avalanche

(valable en dehors des pistes balisées et ouvertes)

MASSIF : Pays-Basque

Rédigé le jeudi 26 février 2026 à 16h

Estimation des risques pour le : VENDREDI 27 FÉVRIER

MANTEAU NEIGEUX PRINTANIER, RARES PLAQUES POSSIBLES DANS LES SECTEURS OMBRAGÉS AU PLUS HAUT DU MASSIF.

1

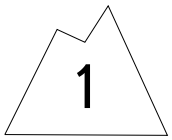

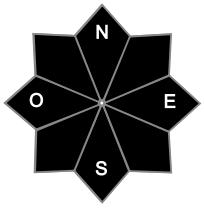

Indice de risque faible.

Départs spontanés : En neige humide dans les pentes raides ensoleillées, avalanches de fond possibles.

Déclenchements provoqués : Rares plaques au plus haut du massif.

Indices de risque : 5 très fort - 4 fort - 3 marqué - 2 limité - 1 faible -- En noir : les pentes les plus dangereuses

Stabilité du manteau neigeux

Situation avalancheuse typique : avalanches de fond neige humide

Départs spontanés : Des départs ponctuels dans la neige humide sont possibles dans les pentes raides au fil de l'ensoleillement, concernant d'abord les pentes Est à Sud, puis rapidement les autres versants au fil de la journée. Des avalanches de petites tailles, très localement moyennes sont attendues.
Quelques **avalanches de fond,** avec cassure linéaire emportant la totalité du manteau neigeux en place, sont possibles en tous versants, en partant d'une accumulation importante et persistante au plus haut du massif.

Déclenchements provoqués : **Peu probables**. De **rares plaques peu épaisses** peuvent encore être en place au plus haut du massif dans les secteurs ombragés. Elles restent difficilement déclenchables par un simple skieur, mais leur sollicitation peut engendrer de petites avalanches, rarement des moyennes.
Un simple skieur peut aussi déclencher de petites avalanches dans la neige humide dans les versants raides au fil de la journée et de l'ensoleillement.

Autres : **très bon regel nocturne** du manteau neigeux humidifié dans la journée de jeudi, **propice aux glissades** dans **tous les secteurs en début de journée**, souvent **persistant dans les pentes raides à l'ombre sur le haut du massif**.

Qualité de la neige

Enneigement : très bon pour la saison au regard de ces derniers hivers. Avec le beau temps, fonte très limitée à l'ombre au-delà de 1500m, plus prononcée dans les versants d'un large secteur sud. Le manteau neigeux s'amincit très doucement dans les pentes bien ensoleillées, la fonte est lente et progressive. Crêtes, cols et sommets pelés et en neige dure en expositions ouest.
Limites skiables : à partir de 1300 à 1500 m au petit matin suivant les versants.
État de la neige : Neige regelée à dure le matin. Persistance de neige durcie en journée dans les pentes raides à l'ombre au plus haut du massif. Neige s'humidifiant ensuite au fil de la journée, devenant lourde et poursuivant son humidification en profondeur. Neige parfois sèche ou poudreuse dans les pentes raides des secteurs ombragés au plus haut du massif, pouvant être encore bien travaillée par le vent et restant en l'état malgré la douceur ambiante.

Aperçu météo pour le vendredi 27 février

	nuit	matin	après-midi	soir

Temps sec, bien ensoleillé jusqu'en fin d'après-midi. Arrivée d'une dégradation ensuite, quelques averses. Vent faible à modéré de Sud-Ouest.

Pluie-Neige			2 100 m	1 900 m
Iso 0 °C	3 000 m	3 000 m	2 700 m	2 200 m
Vent 1000 m	↑ 40 km/h	↑ 40 km/h	↓ 25 km/h	↑ 15 km/h
Vent 2000 m	↑ 50 km/h	↑ 55 km/h	↑ 45 km/h	↑ 30 km/h

Épaisseur de neige hors-piste

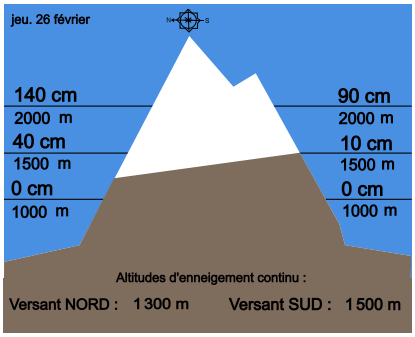

Précipitations à 1800 m

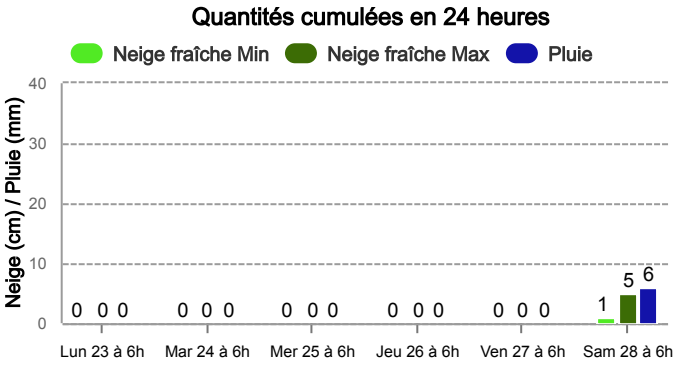

Tendance du samedi 28 février

Indice de risque limité

Risque limité possible. Temps faiblement perturbé dans la nuit de vendredi à samedi ainsi que samedi. Quelques averses attendues.

Pour consulter la vigilance en cours, veuillez vous rendre sur le site https://vigilance.meteofrance.fr/fr

Météo-France - 73 avenue de Paris, 94165 Saint-Mandé cedex - Contact : contact@meteo.fr

Rédigé par Météo-France avec la contribution des observateurs du réseau nivo-météorologiques. Partenariat : ANMSM (Maires de Stations de Montagne), DSF (Domaines Skiables de France), ADSP (Directeurs de Pistes et de la Sécurité des Stations de Sports d'Hiver) et autres acteurs de la montagne.

Bulletin neige & avalanches par téléphone au **0 892 68 10 20** Service 0,35 € / min + prix appel

RÉPUBLIQUE FRANÇAISE
Liberté Égalité Fraternité

METEO FRANCE
À VOS CÔTÉS, DANS UN CLIMAT QUI CHANGE

Bulletin d'estimation du risque d'avalanche

(valable en dehors des pistes balisées et ouvertes)

MASSIF : Pays-Basque

Rédigé le jeudi 26 février 2026 à 16h

Conditions nivo-météo des 7 derniers jours

	ven. 20/02				sam. 21/02				dim. 22/02				lun. 23/02				mar. 24/02				mer. 25/02				jeu. 26/02			
	03h	09h	15h	21h	03h	09h	15h	21h	03h	09h	15h	21h	03h	09h	15h	21h	03h	09h	15h	21h	03h	09h	15h	21h	03h	09h	15h	21h
Météo																												
Vent (km/h)	30	20	25	20	20	10	15	20	25	25	25	25	15	15	20	45	60	55	40	35	35	35	35	35	35	35	45	50
à 2000m																												
Vent (km/h)	15	10	15	10	5	2	10	10	15	15	10	5	5	5	10	15	20	15	15	15	15	15	15	15	20	20	25	30
à 1000m																												

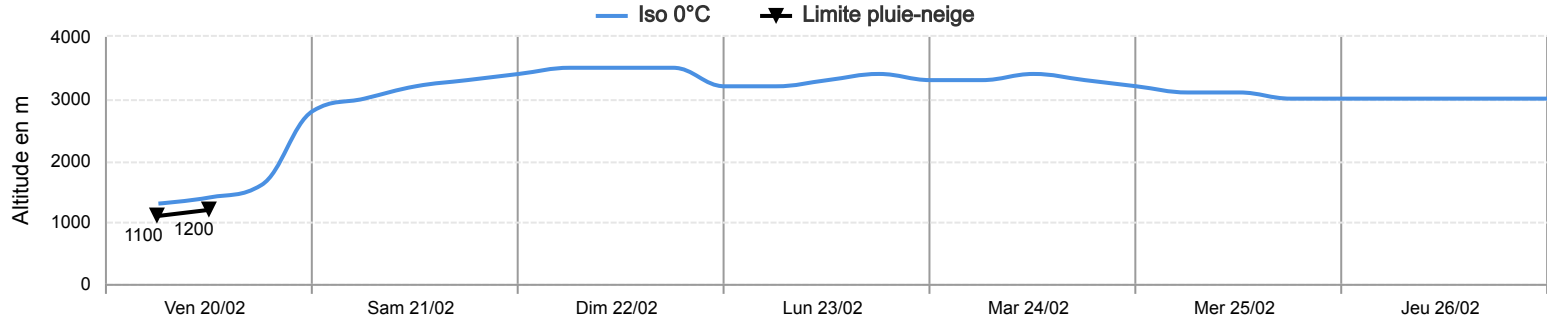

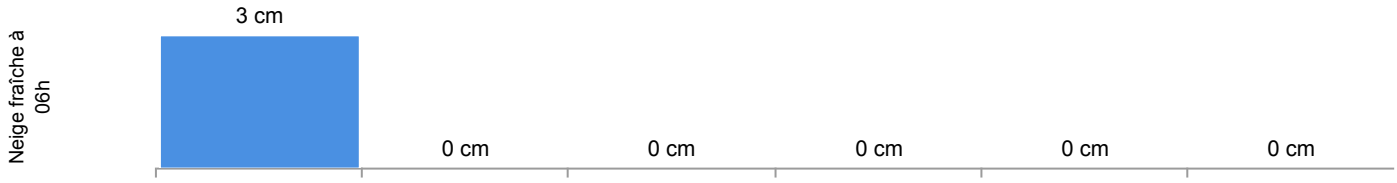

Risque d'avalanche							
	3	3	2	2	2	1	1
	ven. 20/02	sam. 21/02	dim. 22/02	lun. 23/02	mar. 24/02	mer. 25/02	jeu. 26/02

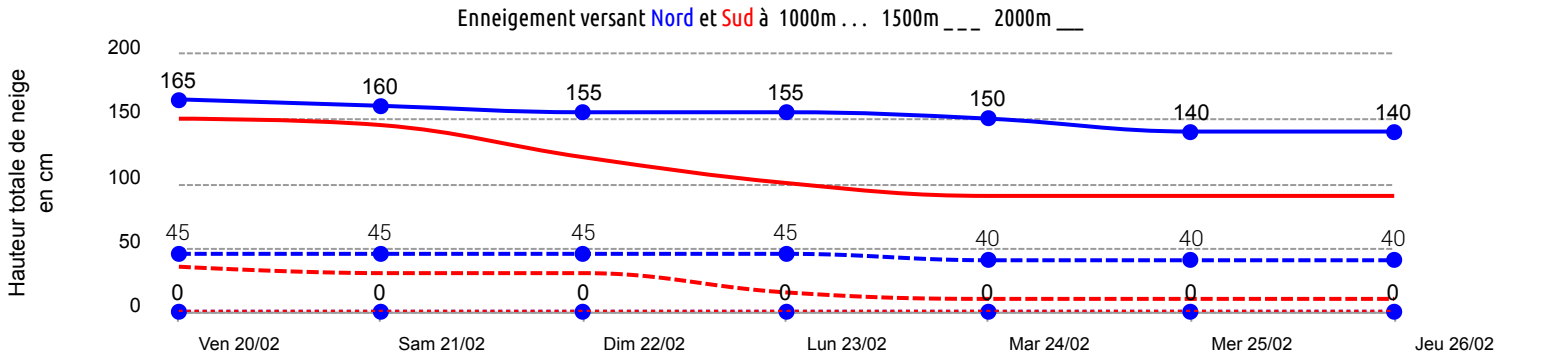

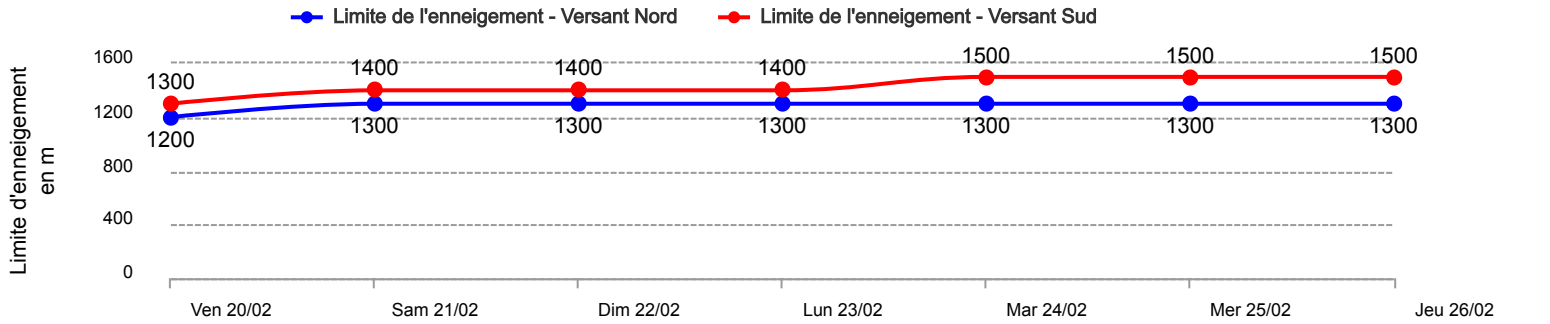

Pour consulter la vigilance en cours, veuillez vous rendre sur le site https://vigilance.meteofrance.fr/fr

Météo-France - 73 avenue de Paris, 94165 Saint-Mandé cedex - Contact : contact@meteo.fr

Rédigé par Météo-France avec la contribution des observateurs du réseau nivo-météorologiques. Partenariat : ANMSM (Maires de Stations de Montagne), DSF (Domaines Skiables de France), ADSP (Directeurs de Pistes et de la Sécurité des Stations de Sports d'Hiver) et autres acteurs de la montagne.

Bulletin neige & avalanches par téléphone au
0 892 68 10 20 Service 0,35 € / min + prix appel