Bulletin d'estimation du risque d'avalanche

(valable en dehors des pistes balisées et ouvertes)

MASSIF : Queyras

Rédigé le jeudi 26 février 2026 à 16h

Estimation des risques pour le : VENDREDI 27 FÉVRIER

INSTABILITÉS ENCORE DÉCLENCHABLES PAR UN SEUL SKIEUR ; GRANDES AVALANCHES POSSIBLES

3

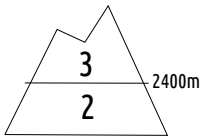

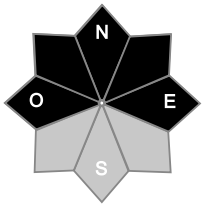

Au-dessus de 2400m indice de risque marqué, plus bas indice limité.

Départs spontanés : avalanches de neige humide au soleil, départs ponctuels ou linéaires, rarement de grande taille

Déclenchements provoqués : instabilités localisées en versants peu ensoleillés d'altitude, encore déclenchables par un seul skieur

Indices de risque : 5 très fort - 4 fort - 3 marqué - 2 limité - 1 faible -- En noir : les pentes les plus dangereuses

Stabilité du manteau neigeux

Situation avalancheuse typique : couche fragile persistante neige humide

Déclenchements provoqués :
Des instabilités persistent au-dessus de 2000 m d'altitude. Elles sont plus nombreuses en versant ouest, nord et est au-dessus de 2400 m d'altitude. Un seul skieur peut encore déclencher, parfois à distance, une avalanche de taille moyenne à grande (taille 2 à 3), avec cassure épaisse et large.
La couche fragile persistante en partie inférieure, voire à la base du manteau neigeux, demeure le danger principal. Elle est encore sollicitable dans un nombre significatif de pentes, car les chutes de neige de la mi-février ont été moins abondantes dans ce massif. Déclenchements surtout possibles dans les zones de plus faible enneigement, au niveau des discontinuités de terrain (croupes, rochers affleurants, transitions entre zones plus enneigées et moins enneigées).
En versants bien réchauffés par le soleil, notamment entre 2400 et 2800 m environ, un skieur peut également initier une avalanche de neige humide avec départ linéaire, avec largeur de cassure cependant plus modeste qu'en versants froids.

Départs spontanés : peu probables au petit matin, à l'exception de rares avalanches de glissement de taille 1 à 2 sur terrain favorable : sols herbeux, rochers lisses en versants sud raides. Activité en neige humide en hausse selon la course du soleil, mais probablement moins marquée que les jours précédents. Les départs, le plus souvent ponctuels près des rochers ou des barres et de taille 1 à 2, peuvent, plus rarement, engendrer des avalanches linéaires et jusqu'au sol de taille 2 à 3.

Qualité de la neige

L'enneigement est plutôt excédentaire vers le Briançonnais et le Guillestrois, plus proche des normales sur la majeure partie du massif.
Hauteurs de neige observées : 162 cm en versant nord du col Izoard à 2300 m, 90 cm à Cervières à 1610 m, 88 cm à la Nivôse du Col Agnel à 2630 m, 59 cm à Ristolas à 1670 m.

Limite d'enneigement skiable vers 1200/1300 m en ubacs, plutôt 1800/2000 m en adrets.

État de la neige de surface : manteau neigeux printanier en adrets, bien regelé le matin, s'humifiant au soleil l'après-midi, sur une grande épaisseur en versants raides. En versants nord-est, nord et nord-ouest, le manteau neigeux est resté froid, ou humidifié / regelé seulement en surface sous 2000/2200 m. Plus haut, neige dense, souvent cartonnée ou durcie par les épisodes de vent passés. Neige encore d'aspect poudreux dense en limite supérieure de forêt ou dans les rares combes bien abritées du vent.

Aperçu météo pour le vendredi 27 février

	nuit	matin	après-midi	soir

Printanier : sec, ensoleillé et très doux, vent calme ou faible.

Pluie-Neige				
Iso 0 °C	3 100 m	3 000 m	2 900 m	2 800 m
Vent 2000 m	5 km/h	5 km/h	5 km/h	5 km/h
Vent 3000 m	10 km/h	5 km/h	10 km/h	15 km/h

Épaisseur de neige hors-piste

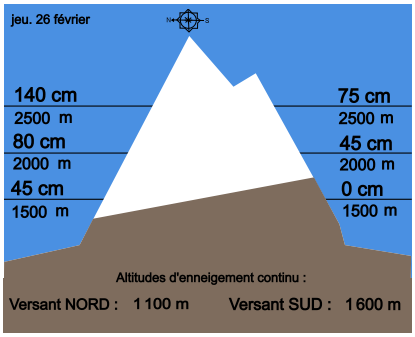

Précipitations à 1800 m

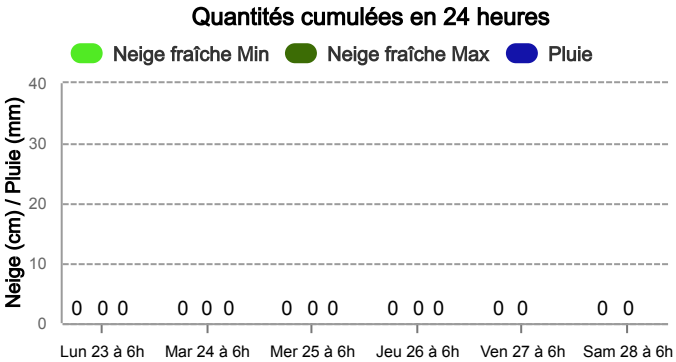

Tendance du samedi 28 février

2

Indice de risque limité

Poursuite de la stabilisation progressive du manteau neigeux. Risque limité

Pour consulter la vigilance en cours, veuillez vous rendre sur le site https://vigilance.meteofrance.fr/fr

Météo-France - 73 avenue de Paris, 94165 Saint-Mandé cedex - Contact : contact@meteo.fr

Rédigé par Météo-France avec la contribution des observateurs du réseau nivo-météorologiques. Partenariat : ANMSM (Maires de Stations de Montagne), DSF (Domaines Skiables de France), ADSP (Directeurs de Pistes et de la Sécurité des Stations de Sports d'Hiver) et autres acteurs de la montagne.

Bulletin neige & avalanches par téléphone au

0 892 68 10 20 Service 0,35 € / min + prix appel

Bulletin d'estimation du risque d'avalanche

(valable en dehors des pistes balisées et ouvertes)

MASSIF : Queyras

Rédigé le jeudi 26 février 2026 à 16h

Conditions nivo-météo des 7 derniers jours

	ven. 20/02				sam. 21/02				dim. 22/02				lun. 23/02				mar. 24/02				mer. 25/02				jeu. 26/02			
	03h	09h	15h	21h	03h	09h	15h	21h	03h	09h	15h	21h	03h	09h	15h	21h	03h	09h	15h	21h	03h	09h	15h	21h	03h	09h	15h	21h
Météo																												
Vent (km/h)	55	50	45	40	60	70	70	50	50	40	40	40	50	50	45	50	40	20	5	5	10	10	10	10	10	10	10	10
à 3000m																												
Vent (km/h)	45	35	35	25	35	45	40	15	15	15	15	15	20	20	20	10	5	5	5	5	5	5	10	5	5	5	5	5
à 2000m																												

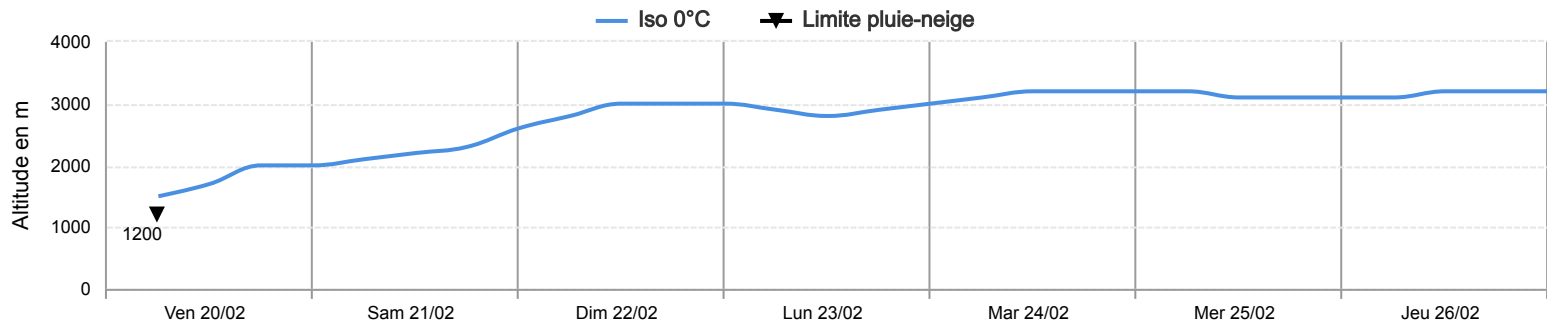

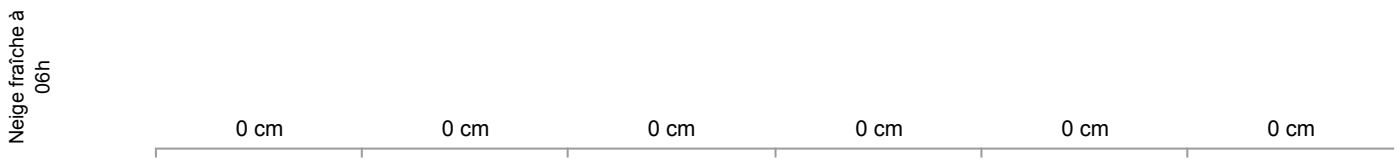

Risque d'avalanche	ven. 20/02	sam. 21/02	dim. 22/02	lun. 23/02	mar. 24/02	mer. 25/02	jeu. 26/02
	3	3	3	3	3	3	3

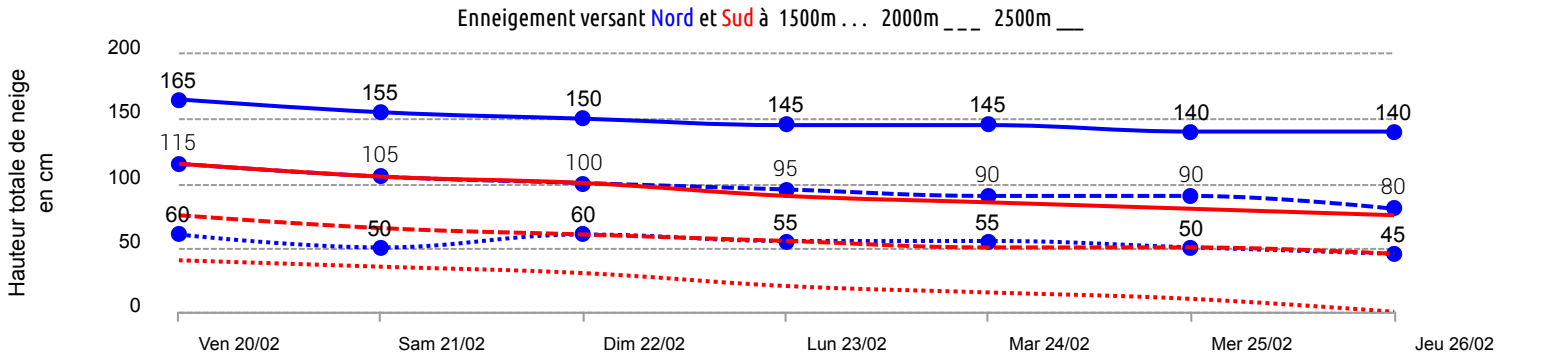

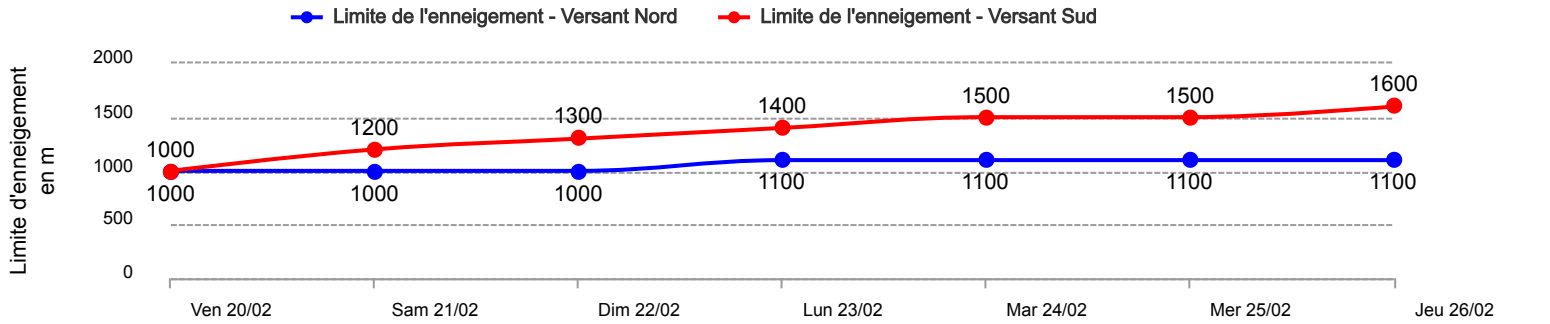

Pour consulter la vigilance en cours, veuillez vous rendre sur le site https://vigilance.meteofrance.fr/fr

Météo-France - 73 avenue de Paris, 94165 Saint-Mandé cedex - Contact : contact@meteo.fr

Rédigé par Météo-France avec la contribution des observateurs du réseau nivo-météorologiques. Partenariat : ANMSM (Maires de Stations de Montagne), DSF (Domaines Skiables de France), ADSP (Directeurs de Pistes et de la Sécurité des Stations de Sports d'Hiver) et autres acteurs de la montagne.

Bulletin neige & avalanches par téléphone au

0 892 68 10 20 Service 0,35 € / min + prix appel