Bulletin d'estimation du risque d'avalanche

(valable en dehors des pistes balisées et ouvertes)

MASSIF : Vanoise

Rédigé le jeudi 26 février 2026 à 16h

Estimation des risques pour le : VENDREDI 27 FÉVRIER

FORT REDOUX EN JOURNEE ENGENDRANT ENCORE QUELQUES AVALANCHES EN NEIGE HUMIDE

3

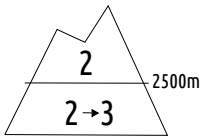

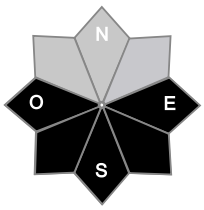

Au-dessus de 2500m indice de risque limité, plus bas indice limité évoluant en marqué.

Départs spontanés : encore quelques grandes en neige humide à craindre avec le réchauffement en journée

Déclenchements provoqués : rares plaques encore réactives dans les versants ombragés.

Indices de risque : 5 très fort - 4 fort - 3 marqué - 2 limité - 1 faible -- En noir : les pentes les plus dangereuses

Stabilité du manteau neigeux

Situation avalancheuse typique : neige humide couche fragile persistante

Départs spontanés :

(1) Après plusieurs heures au Soleil dans les **versants E/S/W,** , **la neige trop humide coule** dans les pentes raides , non encore purgées, souvent au départ des barres rocheuses. Au dessus de 2500m, avalanche de surface taille 1 à 2 rare 3 . **En dessous de 2500m** la couche de neige humide est plus importante et les épaisseurs de neige encore conséquentes ce qui peut engendrer (parfois en cascade et en plaque) **quelques grandes avalanches de taille 3** ***qui prennent rapidement de la vitesse et peuvent descendre assez bas.***

(2) ***rares*** **plaques de fond** dans les pentes habituelles raides en herbe ou en dalle rocheuse **à toutes heures et en toutes orientations**, plutôt **sous 2000/2200 m**. Le manteau neigeux actuel étant épais, les volumes mobilisés peuvent être plus conséquents que d'habitude.

Déclenchements provoqués :

Rares plaques dures sur couche fragile persistante en **versants W/N/E, au-dessus de 2000/2200 m.** le risque est toujours bien présent **dans une pente moins enneigée comme aux abords d'une crête ou d'une croupe ventée** avec des couches fragiles plus près de la surface. Avalanche de taille 2 à 3 alors possible. Ailleurs déclenchement maintenant peu probable, car cette couche fragile est généralement profondément enfouie et souvent hors d'atteinte par un skieur. . **Observables :** Test du bâton, tests d'instabilité.

Qualité de la neige

Enneigement : grâce aux chutes de neige de mi février, l'enneigement est actuellement excédentaire à toutes altitudes. Les températures anormalement douces engendrent une fonte marquée en Sud de moyenne et basse montagne. La limite d'enneigement dans ces pentes remonte vite. Ailleurs le manteau se tasse considérablement.

Limite skiable : encore skiable dès 1000 m dans les prairies orientées Nord, plutôt 1300 m en Sud pas trop raide.

Qualité de la neige :

En Sud, véritable ski de printemps. Croûte portante au réveil qui ramollie rapidement au soleil, neige pourrie ensuite

En Nord, neige croutée souvent non portante jusqu'à 1800/2000 qui chauffe doucement là où elle prend le Soleil. Plus haut, la neige est froide, poudreuse dense à l'abri du vent et très hétérogène entre carton et dure dans les secteurs ventés (à l'approche des crêtes).

En Est et Ouest, la croûte peu portante monte jusqu'aux sommets. Elle ramollie rapidement au Soleil.

Aperçu météo pour le vendredi 27 février

	nuit	matin	après-midi	soir
Beau et toujours trop chaud pour la saison				
Pluie-Neige				
Iso 0 °C	3 000 m	3 100 m	2 900 m	2 800 m
Vent 2500 m	5 km/h	5 km/h	10 km/h	10 km/h
Vent 3500 m	15 km/h	15 km/h	25 km/h	30 km/h

Épaisseur de neige hors-piste

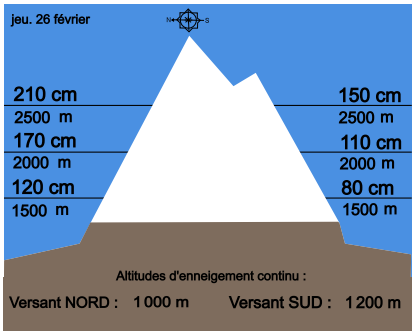

Précipitations à 1800 m

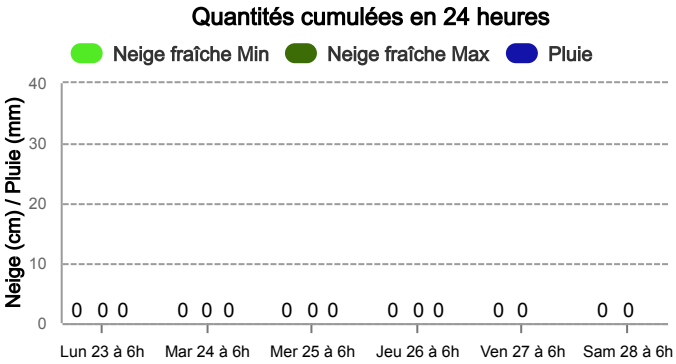

Tendance du samedi 28 février

Indice de risque limité

Baisse des températures qui devraient progressivement faire diminuer le risque naturel d'avalanche de neige humide.

Pour consulter la vigilance en cours, veuillez vous rendre sur le site https://vigilance.meteofrance.fr/fr

Météo-France - 73 avenue de Paris, 94165 Saint-Mandé cedex - Contact : contact@meteo.fr

Rédigé par Météo-France avec la contribution des observateurs du réseau nivo-météorologiques. Partenariat : ANMSM (Maires de Stations de Montagne), DSF (Domaines Skiables de France), ADSP (Directeurs de Pistes et de la Sécurité des Stations de Sports d'Hiver) et autres acteurs de la montagne.

Bulletin neige & avalanches par téléphone au **0 892 68 10 20** Service 0,35 € / min + prix appel

RÉPUBLIQUE FRANÇAISE
Liberté Égalité Fraternité

METEO FRANCE
À VOS CÔTÉS, DANS UN CLIMAT QUI CHANGE

Bulletin d'estimation du risque d'avalanche

(valable en dehors des pistes balisées et ouvertes)

MASSIF : Vanoise

Rédigé le jeudi 26 février 2026 à 16h

Conditions nivo-météo des 7 derniers jours

	ven. 20/02				sam. 21/02				dim. 22/02				lun. 23/02				mar. 24/02				mer. 25/02				jeu. 26/02			
	03h	09h	15h	21h	03h	09h	15h	21h	03h	09h	15h	21h	03h	09h	15h	21h	03h	09h	15h	21h	03h	09h	15h	21h	03h	09h	15h	21h
Météo																												
Vent (km/h)	65	60	55	55	55	55	55	60	40	50	50	50	50	40	50	45	45	40	30	25	20	20	20	15	15	15	15	15
à 3500m																												
Vent (km/h)	50	45	40	30	30	30	25	25	10	20	20	20	20	20	20	15	20	15	15	10	5	5	5	5	5	5	5	5
à 2500m																												

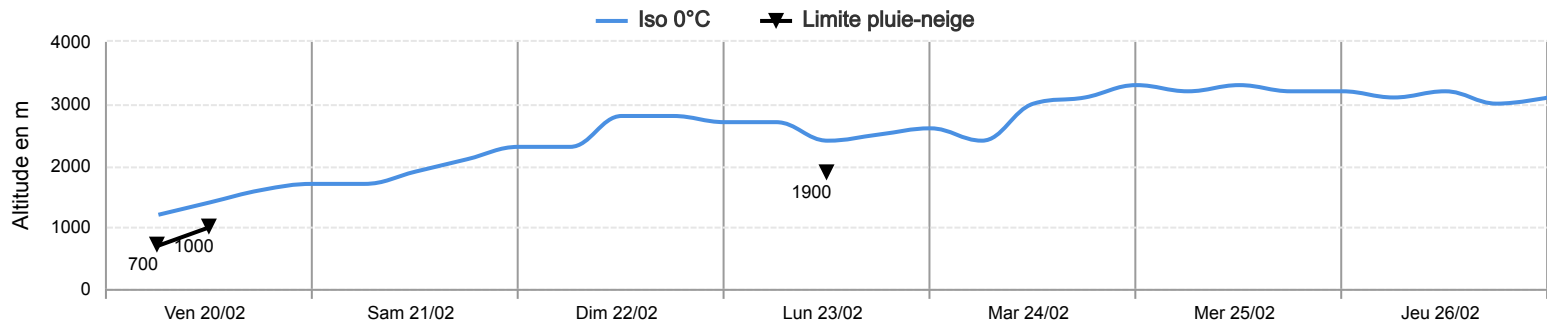

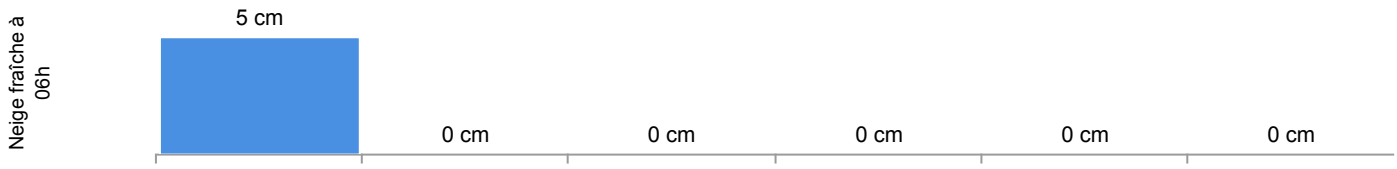

Risque d'avalanche	ven. 20/02	sam. 21/02	dim. 22/02	lun. 23/02	mar. 24/02	mer. 25/02	jeu. 26/02
	4	4	3	3	3	3	3

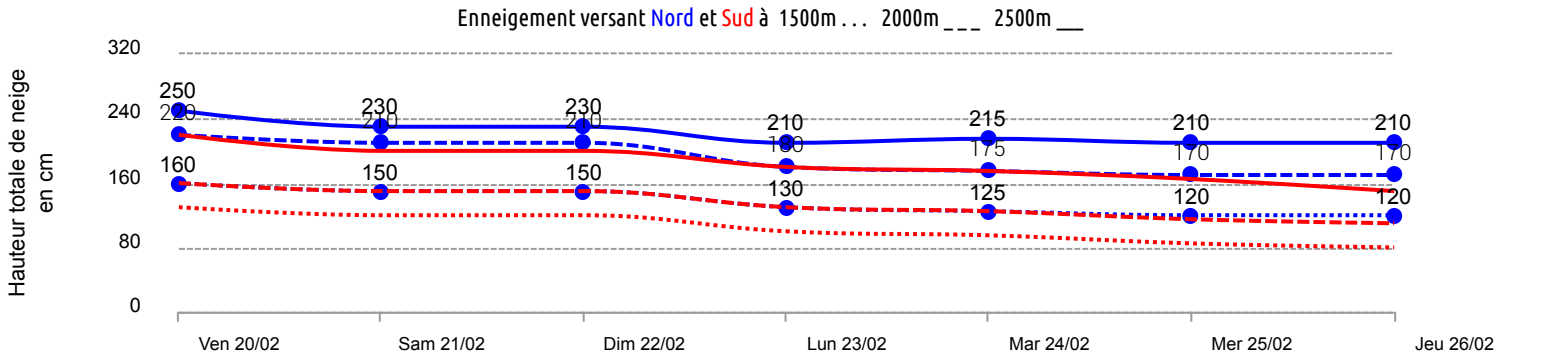

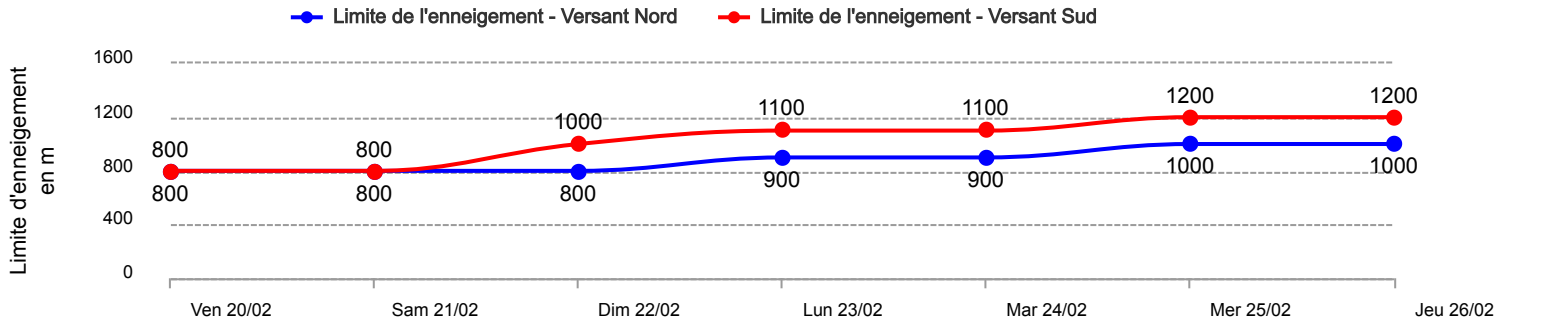

Pour consulter la vigilance en cours, veuillez vous rendre sur le site https://vigilance.meteofrance.fr/fr

Météo-France - 73 avenue de Paris, 94165 Saint-Mandé cedex - Contact : contact@meteo.fr

Bulletin neige & avalanches par téléphone au

0 892 68 10 20 Service 0,35 € / min + prix appel

Rédigé par Météo-France avec la contribution des observateurs du réseau nivo-météorologiques. Partenariat : ANMSM (Maires de Stations de Montagne), DSF (Domaines Skiables de France), ADSP (Directeurs de Pistes et de la Sécurité des Stations de Sports d'Hiver) et autres acteurs de la montagne.