GOBIERNO DE ESPAÑA
VICEPRESIDENCIA TERCERA DEL GOBIERNO
MINISTERIO PARA LA TRANSICIÓN ECOLÓGICA Y EL RETO DEMOGRÁFICO

Boletín de información nivológica y de peligro de aludes

Pirineo Navarro y Aragonés

aemet Agencia Estatal de Meteorología

viernes, 27 de febrero de 2026

Pronóstico hasta las 24 horas del sábado, día 28 de febrero

(Válido fuera de pistas de esquí balizadas y abiertas)

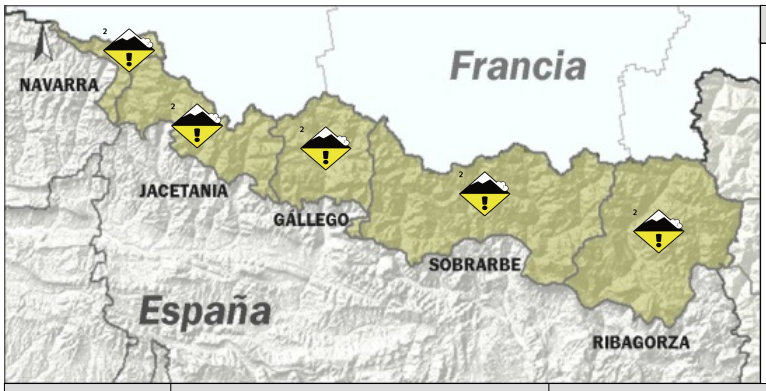

Problemas de aludes

Nieve húmeda

Placas de viento

Macizo	Peligro	Problemas de aludes, cota, orientación, tamaño	Innivación observada (m)
Navarra	2 — Limitado	Nieve húmeda: 2000 ↓, N O E S, 2 Placas de viento: 2000 ↑, N O E S, 2	2026-02-27 N S Cota más baja caras N
Jacetania	2 — Limitado	Nieve húmeda: 2000 ↓, N O E S, 2 Placas de viento: 2000 ↑, N O E S, 2	2026-02-27 N S Cota más baja caras N
Gállego	2 — Limitado	Nieve húmeda: 2000 ↓, N O E S, 2 Placas de viento: 2000 ↑, N O E S, 2	2026-02-27 N S Cota más baja caras N

AEMET. Se autoriza la reproducción de su contenido citando la fuente.

Boletín de información nivológica y de peligro de aludes

Pirineo Navarro y Aragonés

Sobrarbe	**Limitado**	**Nieve húmeda** 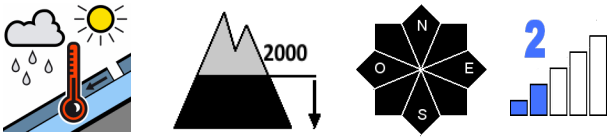 **Placas de viento** 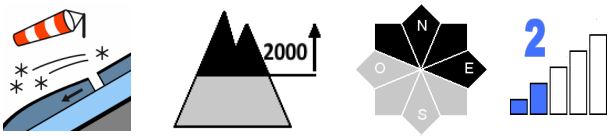	2026-02-27 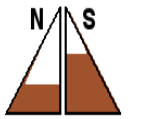 Cota más baja caras N
Ribagorza	**Limitado**	**Nieve húmeda** 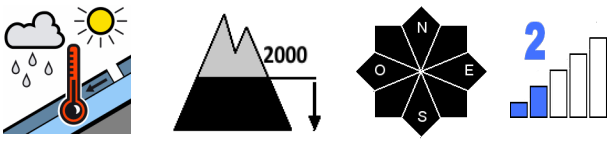 **Placas de viento**	2026-02-27 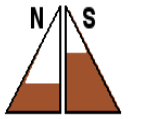 Cota más baja caras N

Estado del manto y observaciones recientes

Durante esta semana, el ambiente templado con temperaturas anormalmente altas y la abundante insolación han propiciado la humidificación y compactación del manto, a razón de algunos centímetros cada día. Estos procesos han sido más intensos en solanas de cotas bajas, donde incluso se pueden observar algunas áreas desprovistas de nieve. Pese a ello, los espesores se encuentran por encima de lo que sería habitual a estas alturas de la temporada, superando fácilmente los 150-200 cm a unos 2100 metros, aún más en ventisqueros, hoyas y otras zonas propensas a la acumulación.

En cotas medias y bajas, así como en solanas a mayor altitud, el manto se ha humidificado en profundidad, y por lo general amanece encostrado, si bien el calentamiento diurno y la intensa radiación van ablandando las costras durante la mañana. En umbrías de cotas altas, la nieve se mantiene más seca y aún podemos encontrar placas de viento que no se hayan estabilizado por completo, que muestran reactividad en algún test realizado pero sin propagación. También en estas zonas podría persistir alguna capa débil enterrada que pueda seguir latente.

En las últimas 24 horas se han reportado tres aludes medianos, de fondo de nieve vieja húmeda, con salida a 2000-2250 metros y orientación sur.

Evolución del manto y peligro de aludes para el sábado, día 28

Problema de nieve húmeda y deslizamientos basales. Problema de placas de viento y nieve reciente en cotas altas.

Mañana, sábado, se esperan nevadas débiles por encima de unos 1300-1500 metros, que podrían dejar alrededor de 5-15 cm nuevos, localmente más, sobre todo en los macizos occidentales y resto de la divisoria. Con estas condiciones serán probables las purgas de

AEMET. Se autoriza la reproducción de su contenido citando la fuente.

nieve reciente en las laderas suficientemente inclinadas de cotas altas, y también los aludes de nieve húmeda en cotas medias y bajas. Tanto unos como otros serán, por lo general, de tamaño pequeño (riesgo de caída), localmente mediano (capaz de enterrar a una persona) en las zonas de más acumulación. Igualmente podrán producirse deslizamientos basales, especialmente en las laderas herbosas o de roca lisa, que podrían movilizar una cantidad de nieve considerable y alcanzar en algún caso el tamaño 3 (grande, capaz de enterrar un vehículo).

En cotas altas se podrán formar nuevas placas de viento en diversas orientaciones, aunque con preferencia en las norte, este y sur, en principio de pequeñas dimensiones. Estas estructuras podrán colapsar ante una sobrecarga débil (paso de un esquiador o raquetista) ocasionando aludes de tamaño 1, si bien podrían arrastrar parte del manto subyacente y alcanzar dimensión 2. Además, no se descarta que se pueda fracturar alguna capa débil persistente en profundidad, principalmente en umbrías, que en el peor de los casos podría provocar un alud de mayor tamaño.

Predicción meteorológica para el sábado, día 28

Pirineo navarro:

Muy nuboso o cubierto con visibilidad localmente reducida, tendiendo a abrirse algunos claros por el sur al final del día. Se esperan precipitaciones débiles o localmente moderadas, que tenderán a remitir por la tarde. Cota de nieve bajando de 1700 a 1300 metros. Temperaturas en descenso, notable en las máximas. Las mínimas se podrán registrar al final del día. Heladas débiles en cotas altas. Viento moderado del suroeste tendiendo a flojo del oeste en cotas altas. De componente norte en el resto, moderado disminuyendo a flojo.

Pirineo aragonés:

Nuboso o con intervalos nubosos de madrugada, aumentando a muy nuboso o cubierto con visibilidad localmente reducida. Al final del día se abrirán algunos claros. Se esperan precipitaciones débiles o localmente moderadas, siendo más frecuentes e intensas en los macizos occidentales y resto de la divisoria, que tenderán a remitir por la tarde. Cota de nieve bajando de 1800 a 1400-1500 metros. Temperaturas en descenso, localmente notable en las máximas. Heladas débiles o moderadas en cotas altas. Viento moderado del suroeste tendiendo a flojo del oeste en cotas altas. Flojo de dirección variable en el resto.

Datos en la atmósfera libre:

Altitud de la isoterma de 0 ºC: 1700 m (W) - 2000 m (E)
Altitud de la isoterma de -10 ºC: 3600 m

Viento a 1500 m: VRB 10 km/h
Viento a 3000 m: SW 30 km/h

Evolución para el domingo día 1

Se acentuarán los problemas de nieve húmeda.

(Información elaborada a partir de los datos recibidos de los refugios de Linza, Lizara, Panticosa, Bachimaña, Góriz, Pineta, Estós, Angel Orús, La Renclusa, Cap de Llauset y Belagua, de las estaciones de esquí de Astún, Formigal y Panticosa (lagos) y de Ordesa Pradera)

AEMET. Se autoriza la reproducción de su contenido citando la fuente.

Boletín de información nivológica y de peligro de aludes

Pirineo Navarro y Aragonés

Escala europea de peligro de aludes

Débil | Limitado | Notable | Fuerte | Muy Fuerte

Problemas de aludes

Nieve reciente | Placas de viento | Capas débiles persistentes | Nieve húmeda | Deslizamientos basales | Sin problema evidente

Nota1: Se recuerda que, siempre que haya nieve, la ausencia total de peligro no existe. Hay que tener presente que en circunstancias desfavorables, con aludes de tamaño 1 (alud pequeño o colada) y tamaño 2 (alud mediano), se pueden sufrir severos daños personales.

Nota2: Los BPA se elaboran en base a información meteorológica así como al estado del manto nivoso a través de sondeos puntuales. Se advierte a los usuarios de la variabilidad de esta información al extrapolarla a zonas extensas de montaña. Por ello, AEMET no se hace responsable de su uso para la toma de decisiones que conciernen a la seguridad personal, ni de los riesgos físicos o materiales de ellas derivadas.

AEMET. Se autoriza la reproducción de su contenido citando la fuente.