ICGC Institut Cartogràfic i Geològic de Catalunya

Servei Meteorològic de Catalunya meteo.cat

Boletín de peligro de aludes para el Pirineo de Catalunya
Del 27/02/2026 al 28/02/2026

(Válido fuera pistas de esquí y zonas no controladas)

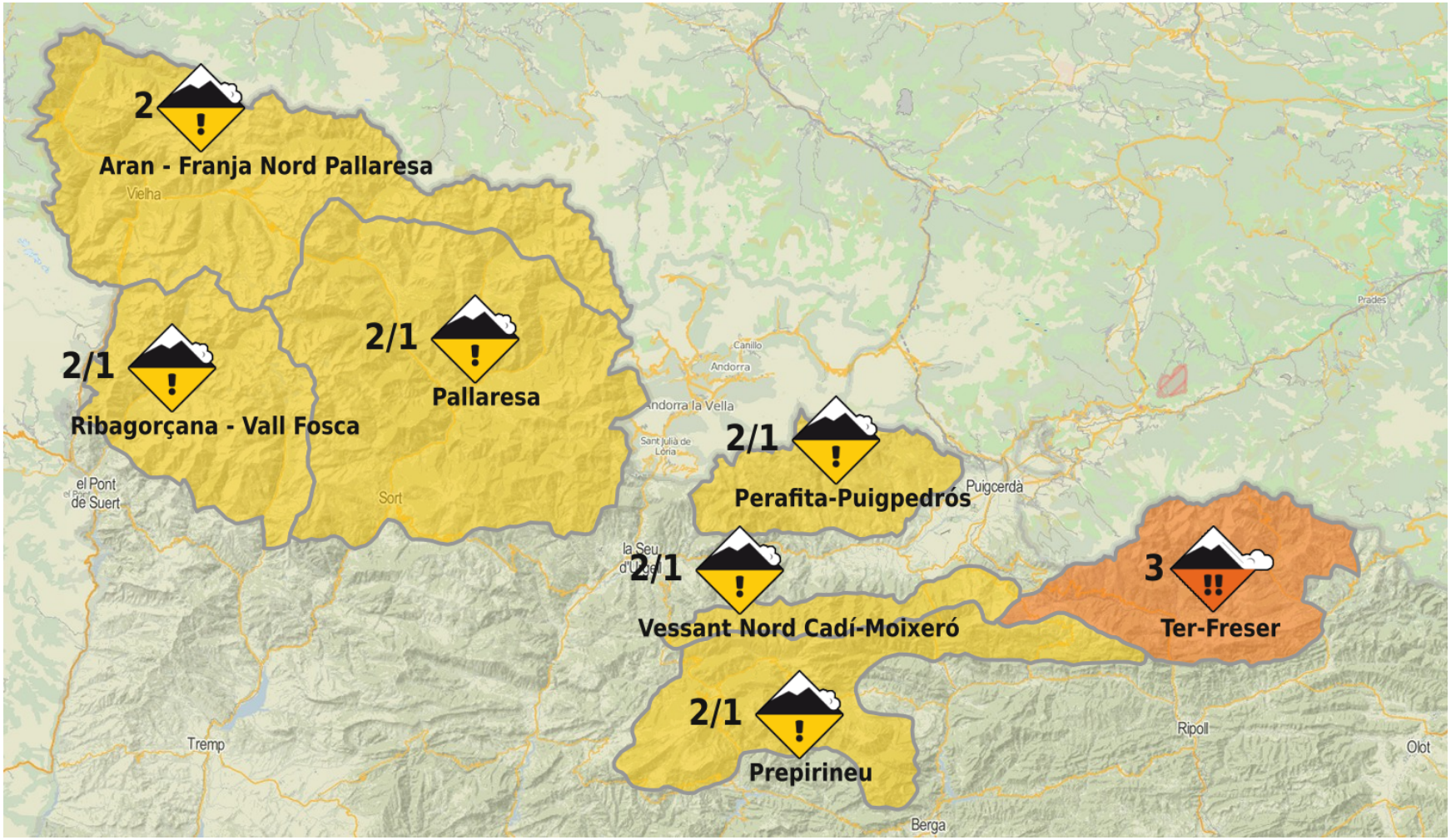

5 MUY FUERTE	4 FUERTE	3 NOTABLE	2 LIMITADO	1 DÉBIL

ICGC Institut Cartogràfic i Geològic de Catalunya

Servei Meteorològic de Catalunya

Boletín de peligro de aludes Aran - Franja Nord Pallaresa Del 27/02/2026 al 28/02/2026

(Válido fuera pistas de esquí y zonas no controladas)

LIMITADO (2)

Situación primaria

Nieve venteada

Distribución

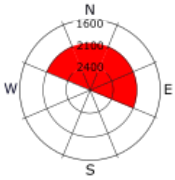

Tamaño

Origen

Tendencia

Situación secundaria

Nieve húmeda

Distribución

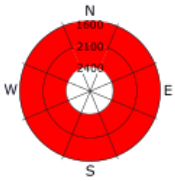

Tamaño

Origen

Tendencia

Estado del manto nivoso

Se espera la formación de nuevas placas por el viento del viernes, con leve transporte de nieve, y las nevadas del sábado. Se encontrarán especialmente en sotaventos elevados orientados a norte y este. En algunos casos estas placas nuevas repondrán sobre niveles de nieve facetada, que podrían facilitar su desencadenamiento y propagación de aludes. Al paso de una persona, se podrán desencadenar aludes en general de tamaño 1, aunque al final del día podrían ser mayores. Se espera que el rehielo matinal sea poco efectivo el sábado, y con la elevada humedad ambiental habrá aludes de nieve húmeda, en especial en umbrías hasta 2.400 m. Además, continúa la actividad de deslizamientos basales en el sector, de tamaño 2 o incluso mayor.

Distribución del manto nivoso

Hay nieve por encima de unos 1.400 ma umbrías y 1.600 ma solanas. Los espesores a unos 2.200 m son superiores a los normales y rondan los 120-140 cm en el norte de Aran y los 160-200 cm en la Franja Norte Pallaresa y en el sur de Aran, puntualmente superiores.

Tendencia para las próximas 48-72h

Habrá pocos cambios en lo que respecta a la estabilidad del manto; será necesario vigilar con las nuevas placas de viento, así como con la caída natural de deslizamientos basales. Peligro ESTACIONARIO.

El próximo boletín será emitido el día 2026-02-28

5 MUY FUERTE	4 FUERTE	3 NOTABLE	2 LIMITADO	1 DÉBIL

EAWS EUROPEAN AVALANCHE WARNING SERVICES

ICGC Institut Cartogràfic i Geològic de Catalunya

meteo.cat Servei Meteorològic de Catalunya

Boletín de peligro de aludes Ribagorçana - Vall Fosca Del 27/02/2026 al 28/02/2026

(Válido fuera pistas de esquí y zonas no controladas)

LIMITADO (2) por encima de 2.200 m. DÉBIL (1) por debajo.

Situación primaria

Nieve venteada

Distribución

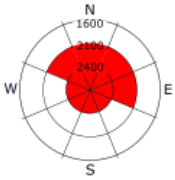

Tamaño

Origen

Tendencia

Situación secundaria

Deslizamientos basales

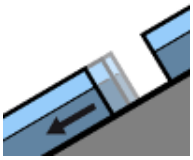

Distribución

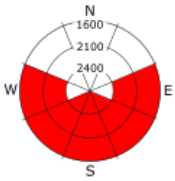

Tamaño

Origen

Tendencia

Estado del manto nivoso

Durante la jornada del sábado se espera que se formen placas de viento en el sector. Se encontrarán principalmente en laderas norte y este, en forma de placas blandas y se podrán desencadenar al paso de una persona dando lugar a aludes de tamaño 1, por lo general. Con el paso de las horas, las placas serán más abundantes y gruesas. Todavía son probables caídas de deslizamientos basales de tamaño 2, suficiente para enterrar a una persona, o incluso mayor. Se desprenden de terreno soleado, de fuerte pendiente, liso y herboso o rocoso, o bajo paredes rocosas. Se debe evitar el terreno bajo grietas, ya que pueden indicar condiciones de deslizamiento del manto sobre el suelo. El sábado, además, podría haber algunas purgas de nieve húmeda en cotas medias o bajas.

Distribución del manto nivoso

Hay nieve en el suelo a 1.500 m en terreno umbrío, y por encima de unos 1.700-1800 m en laderas soleadas. El manto es esquiable por encima de unos 1.600 m en umbrías. Los espesores alcanzan los 120-150 cm en cotas medias. Estos valores son superiores a los normales para la época.

Tendencia para las próximas 48-72h

Las placas de viento serán el elemento más destacable a tener en cuenta. continuará la actividad de deslizamientos basales. Peligro ESTACIONARIO.

El próximo boletín será emitido el día 2026-02-28

5 MUY FUERTE	4 FUERTE	3 NOTABLE	2 LIMITADO	1 DÉBIL

EAWS EUROPEAN AVALANCHE WARNING SERVICES

ICGC Institut Cartogràfic i Geològic de Catalunya

Servei Meteorològic de Catalunya

Boletín de peligro de aludes Pallaresa
Del 27/02/2026 al 28/02/2026

(Válido fuera pistas de esquí y zonas no controladas)

LIMITADO (2) por encima de 2.200 m.
DÉBIL (1) por debajo.

Situación primaria

Nieve venteada

Distribución

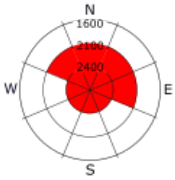

Tamaño

Origen

Tendencia

Situación secundaria

Deslizamientos basales

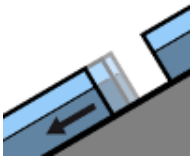

Distribución

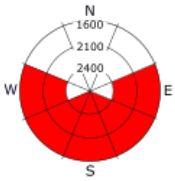

Tamaño

Origen

Tendencia

Estado del manto nivoso

Durante la jornada del sábado se espera que se formen placas de viento en el sector. Se encontrarán principalmente en laderas norte y este, en forma de placas blandas y se podrán desencadenar al paso de una persona dando lugar a aludes de tamaño 1, por lo general. Con el paso de las horas, las placas serán más abundantes y gruesas. Todavía son probables caídas de deslizamientos basales de tamaño 2, suficiente para enterrar a una persona, o incluso mayor. Se desprenden de terreno soleado, de fuerte pendiente, liso y herboso o rocoso, o bajo paredes rocosas. Se debe evitar el terreno bajo grietas, ya que pueden indicar condiciones de deslizamiento del manto sobre el suelo. El sábado, además, podría haber algunas purgas de nieve húmeda en cotas medias o bajas.

Distribución del manto nivoso

Hay nieve en el suelo a 1.500 m en terreno umbrío, esquiable por encima de unos 1.600 m; en orientaciones soleadas la nieve está presente por encima de unos 1.700-1.800 m. Los espesores alcanzan los 110-150 cm en cotas medias. Estos valores son superiores a los normales para la época.

Tendencia para las próximas 48-72h

Las placas de viento serán el elemento más destacable a tener en cuenta. continuará la actividad de deslizamientos basales. Peligro ESTACIONARIO.

El próximo boletín será emitido el día 2026-02-28

5 MUY FUERTE	4 FUERTE	3 NOTABLE	2 LIMITADO	1 DÉBIL

EAWS EUROPEAN AVALANCHE WARNING SERVICES

ICGC Institut Cartogràfic i Geològic de Catalunya

Servei Meteorològic de Catalunya

Boletín de peligro de aludes Perafita-Puigpedrós Del 27/02/2026 al 28/02/2026

(Válido fuera pistas de esquí y zonas no controladas)

LIMITADO (2) durante las horas centrales del día, DÉBIL (1) el resto

Situación primaria

Deslizamientos basales **Distribución** **Tamaño** **Origen** **Tendencia**

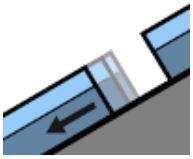

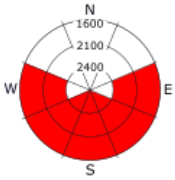

Situación secundaria

Capas débiles persistentes **Distribución** **Tamaño** **Origen** **Tendencia**

Estado del manto nivoso

El manto presenta un comportamiento típicamente primaveral, con la superficie endurecida a primera hora por rehielo, y que se ablanda a este sur y oeste con el paso de las horas. Las últimas jornadas no hay actividad de aludes de nieve húmeda superficiales, aunque no pueden descartarse a lo largo de la jornada. Sin embargo, son probables caídas de deslizamientos basales de tamaño 2, suficiente para enterrar a una persona, o incluso mayor. Se desprenden de terreno soleado, de fuerte pendiente, liso y herboso o rocoso, o bajo paredes rocosas. Se debe evitar el terreno bajo grietas, ya que pueden indicar condiciones de deslizamiento del manto sobre el suelo. En umbrías, en cota alta, todavía se pueden encontrar placas antiguas que descansan sobre niveles de nieve facetada, poco reactivas en general, pero que todavía pueden ceder por sobrecargas y generar aludes de pequeño tamaño.

Distribución del manto nivoso

Hay nieve en el suelo por encima de unos 1.600 m, aunque en las solanas más derechas el manto va retranqueando y la nieve está presente por encima de 1.800 m. Los espesores, aunque irregulares, rondan los 70-110 cm en cotas medias, con frecuentes deflaciones en orientaciones norte y oeste por encima del nivel del bosque. Son grosores muy por encima de los habituales por la época.

Tendencia para las próximas 48-72h

Se podrán formar nuevas placas en el sector, pequeñas y locales, pero susceptibles de romperse al paso de personas. Menguará la probabilidad de deslizamientos basales. Peligro ESTACIONARIO.

El próximo boletín será emitido el día 2026-02-28

5 MUY FUERTE	4 FUERTE	3 NOTABLE	2 LIMITADO	1 DÉBIL

EAWS EUROPEAN AVALANCHE WARNING SERVICES

ICGC Institut Cartogràfic i Geològic de Catalunya

Servei Meteorològic de Catalunya meteo.cat

Boletín de peligro de aludes Vessant Nord Cadí-Moixeró Del 27/02/2026 al 28/02/2026

(Válido fuera pistas de esquí y zonas no controladas)

LIMITADO (2) a mediodía, DÉBIL (1) el resto

Situación primaria

Capas débiles persistentes

Distribución

Tamaño

Origen

Tendencia

Situación secundaria

Deslizamientos basales

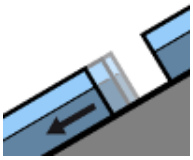

Distribución

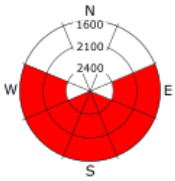

Tamaño

Origen

Tendencia

Estado del manto nivoso

En las umbrías de cota más alta todavía podemos encontrar pequeñas placas locales que descansan sobre capas débiles persistentes antiguas. Al paso de personas podrían desprenderse y dar lugar a aludes de tamaño 1, suficiente para producir caídas o lesiones. Al final de la jornada del sábado se podrían formar placas de viento pequeñas a sotaventos orientados a norte. Pese a las elevadas temperaturas y la insolación en las últimas jornadas no ha habido mucha actividad de aludes de nieve húmeda en el sector, y se espera que el sábado, pese al rehielo poco efectivo que se espera, tampoco haya actividad significativa. Sin embargo, son probables caídas de deslizamientos basales de tamaño 2, suficiente para enterrar a una persona, o incluso mayor. Se desprenden de terreno soleado, de fuerte pendiente, liso y herboso o rocoso, o bajo paredes rocosas. Se debe evitar el terreno bajo grietas, ya que pueden indicar condiciones de deslizamiento del manto sobre el suelo.

Distribución del manto nivoso

En umbrías hay nieve por encima de 1.500 m, esquiable por encima de unos 1.700 m. En solanas la nieve está presente por encima de 1.700 m. Los espesores están alrededor de 130-160 cm en cotas medias. Estos valores son excedentarios para la época del año.

Tendencia para las próximas 48-72h

Se podrán formar nuevas placas de viento sotaventos orientados al norte. Peligro EN AUMENTO.

El próximo boletín será emitido el día 2026-02-28

5 MUY FUERTE	4 FUERTE	3 NOTABLE	2 LIMITADO	1 DÉBIL

EAWS EUROPEAN AVALANCHE WARNING SERVICES

ICGC Institut Cartogràfic i Geològic de Catalunya

Servei Meteorològic de Catalunya

Boletín de peligro de aludes Prepirineu
Del 27/02/2026 al 28/02/2026

(Válido fuera pistas de esquí y zonas no controladas)

LIMITADO (2) durante las horas centrales del día, DÉBIL (1) el resto

Situación primaria

Deslizamientos basales | **Distribución** | **Tamaño** | **Origen** | **Tendencia**

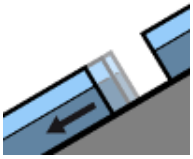

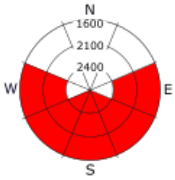

Situación secundaria

Nieve húmeda | **Distribución** | **Tamaño** | **Origen** | **Tendencia**

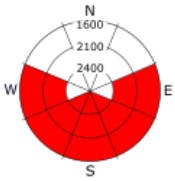

Estado del manto nivoso

Se espera que el rehielo de la mañana del sábado sea menos eficiente que el de días atrás. Con el paso de las horas, con la insolación y las temperaturas elevadas, el manto humedecerá superficialmente. Son probables caídas de deslizamientos basales de tamaño 2, suficiente para enterrar a una persona, o incluso mayor. Se desprenden de terreno soleado, de fuerte pendiente, liso y herboso o rocoso, o bajo paredes rocosas. Se debe evitar el terreno bajo grietas, ya que pueden indicar condiciones de deslizamiento del manto sobre el suelo. También son posibles aludes de nieve húmeda, especialmente en orientaciones este, sur y oeste, en forma de caída de bolas, purgas y aludes pequeños, que pueden producirse hasta cota alta, en laderas soleadas de fuerte pendiente preferentemente.

Distribución del manto nivoso

Hay nieve desde 1.500 a 1600 m esquiable a partir de unos 1.700 m en orientaciones umbrías. En solanas el manto está presente a partir de unos 1.700-1.800 m. Los grosores están alrededor de 100-120 cm a unos 2.200 my son superiores a los habituales. Aparecen deflaciones por encima del nivel del bosque, sobre todo en lugares bien expuestos al viento de norte y oeste.

Tendencia para las próximas 48-72h

Menguará la probabilidad de deslizamientos basales en el sector. Podría haber alguna placa de viento de nueva formación a sotaventos orientados a norte y este. Peligro ESTACIONARIO.

El próximo boletín será emitido el día 2026-02-28

5 MUY FUERTE	4 FUERTE	3 NOTABLE	2 LIMITADO	1 DÉBIL

EAWS EUROPEAN AVALANCHE WARNING SERVICES

ICGC Institut Cartogràfic i Geològic de Catalunya

Servei Meteorològic de Catalunya meteo.cat

Boletín de peligro de aludes Ter-Freser Del 27/02/2026 al 28/02/2026

(Válido fuera pistas de esquí y zonas no controladas)

NOTABLE (3)

Situación primaria

Deslizamientos basales **Distribución** **Tamaño** **Origen** **Tendencia**

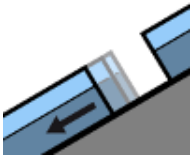

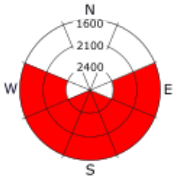

Situación secundaria

Nieve húmeda **Distribución** **Tamaño** **Origen** **Tendencia**

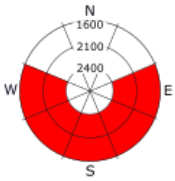

Estado del manto nivoso
La caída de deslizamientos basales ha sido intensa en el sector en las últimas jornadas, llegando a gran tamaño e incluso muy grande (suficiente para llegar a fondo de valle y recorrer más de 50 m en terreno llano); también ha habido purgas superficiales de nieve húmeda. El sábado el rehielo no será tan intenso como en días anteriores. Aún son probables deslizamientos basales con aludes que podrían llegar a tamaño 3 o localmente 4. Tendrán lugar en laderas empinadas y herbosas, o bajo resaltes rocosos. Habrá que prestar atención con la aparición de grietas hasta el suelo y evitar terreno similar a donde se hayan detectado estos aludes. Podrá haber purgas, o incluso algún alud de tamaño 2 (suficiente para enterrar a una persona) muy local fuera del terreno más umbrío. Tendrán lugar en laderas de fuerte inclinación que todavía no hayan purgado.

Distribución del manto nivoso
El manto nivoso presenta grosores muy excedentarios para la época del año. En lugares no afectados por el viento, los espesores oscilan entre 80-100 cm a unos 2.000 m, siendo esquiable a partir de unos 1.600 m. Aparecen deflaciones por encima del nivel del bosque, sobre todo en lugares bien expuestos al viento de norte y oeste.

Tendencia para las próximas 48-72h
Menguará la probabilidad de deslizamientos basales en el sector. De forma local se podría formar alguna placa de viento en orientaciones umbrías. Peligro EN DESCENSO.

El próximo boletín será emitido el día 2026-02-28

5 MUY FUERTE	4 FUERTE	3 NOTABLE	2 LIMITADO	1 DÉBIL

EAWS EUROPEAN AVALANCHE WARNING SERVICES