BUTLLETÍ DEL PERILL D'ALLAUS DEL PRINCIPAT D'ANDORRA

Servei meteorològic nacional
Principat d'Andorra

Elaborat el 27/02/2026 16:00
Propera actualització 28/02/2026 a les 16h

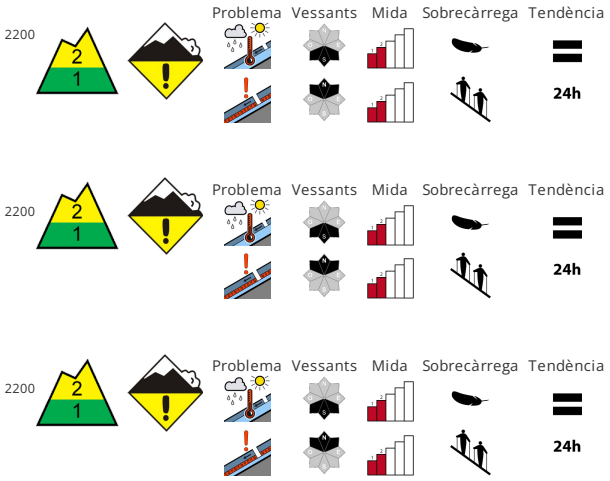

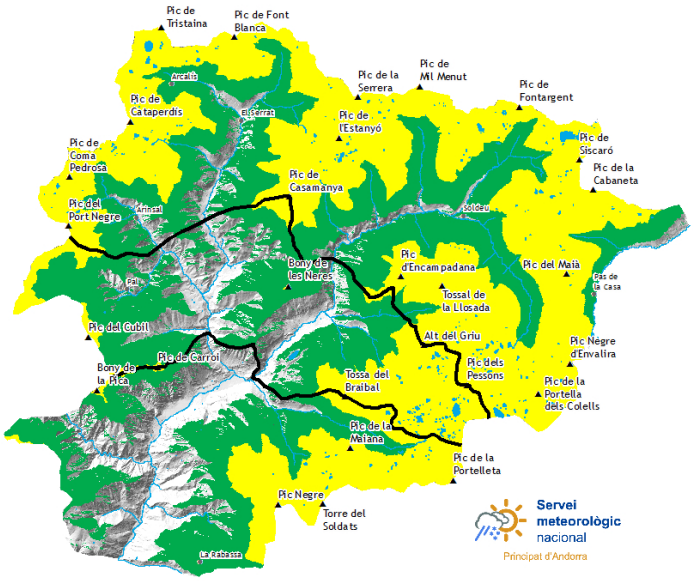

ESTABILITAT DEL MANTELL NIVAL

Encara als vessants molt inclinats orientats a nord a la part central del mantell de neu hi ha capes febles. Aquestes poden de manera aïllada ser desencadenades amb una sobrecàrrega forta i assolir mida mitjana. Es recomana mantenir la distància entre els components. A partir del migdia la probabilitat de desencadenament d'allaus humides augmentarà clarament. A més, són possibles allaus de lliscament basal en qualsevol moment. A causa de la crosta dura hi ha el perill de relliscar i caure als vessants inclinats.

QUALITAT DE LA NEU

Les condicions són primaverals. El refredament nocturn serà en alguns indrets reduït. Els gruixos de neu varien molt per sobre dels 2500 m aproximadament per la influència del vent. Evitar les zones amb esquerdes de lliscament basal.

GRUIXOS DEL MANTELL NIVAL FORA DE PISTA

Zona nord		Gruix neu		
Mantell Nival		1500m	2000m	2500m
N	1400 m	30 cm	150 cm	200 cm
S	1800 m	0 cm	100 cm	150 cm

Zona centre		Gruix neu		
Mantell Nival		1500m	2000m	2500m
N	1400 m	20 cm	150 cm	200 cm
S	1800 m	0 cm	100 cm	150 cm

Zona sud		Gruix neu		
Mantell Nival		1500m	2000m	2500m
N	1400 m	20 cm	120 cm	150 cm
S	1800 m	0 cm	60 cm	100 cm

Govern d'Andorra

EAWS
EUROPEAN AVALANCHE WARNING SERVICES

Aquest butlletí ha estat elaborat seguint les normes i recomanacions de l'**European Avalanche Warning Services**, del qual el **Servei meteorològic Nacional** n'és membre

Informació detallada per espais naturals protegits

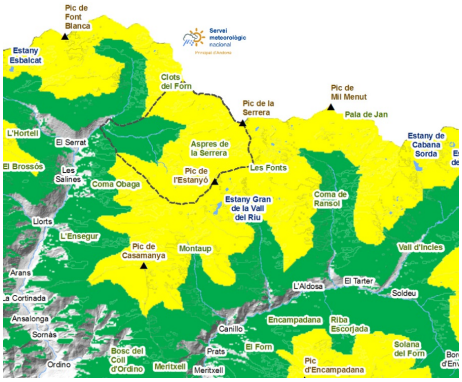

SORTENY

Trobem neu a tots els camins des de Llorts i l´accés amb esquís fins al Refugi es pot fer com feia anys que no es veia durant tantes setmanes seguides. Per sobre de l´estany, als vessants nord trobem capes febles persistents amagades sota la neu pols. Aquestes capes febles persistents podrien desencadenar allaus de placa mitjanes que podrien crear talls de neu o cicatrius importants que podrien tenir conseqüències greus. Per tant, tot i que aquest tipus d´estabilitat només la tenim identificada als vessants més inclinats, per sobre de 2.400 metres i orientats a nord (obacs), l´hem de tenir en compte per escollir el nostre itinerari amb seguretat.

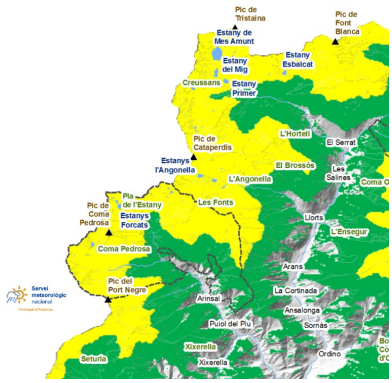

COMAPEDROSA

A cotes baixes la neu s´ha compactat i ha reduït el seu gruix a causa de l´humidificació. Haurem de vigilar a no relliscar a causa de la crosta de regel. La distribució de la neu és molt irregular a causa del vent. Als vessants nord més inclinats haurem de circular amb precaució i mantenint la distància de seguretat per evitar activar les capes febles persistents.

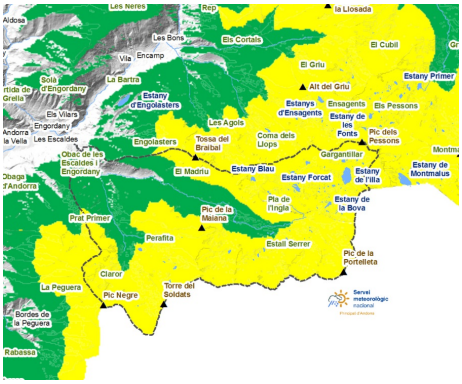

MADRIU-PERAFITA-CLAROR

Als vessants sud i a cotes baixes les condicions són primaverals, neu dura al matí i tova al migdia, amb formes típiques de fusió quan el sol incideix perpendicularment a la pendent. Als vessants nord i als indrets plans la neu es manté pols.

BUTLLETÍ DEL PERILL D'ALLAUS DEL PRINCIPAT D'ANDORRA

Servei meteorològic nacional
Principat d'Andorra

Gruixos de neu nova dels darrers dies (de les últimes 24h mesurat a les 06:00h UTC)

	23/02/2026	24/02/2026	25/02/2026	26/02/2026
FEDA (Central)	0 cm	0 cm	0 cm	0 cm
Engolasters - FEDA	0 cm	0 cm	0 cm	0 cm
Bony de les Neres	0 cm	0 cm	0 cm	0 cm
Sorteny	0 cm	0 cm	0 cm	0 cm
Perafita	0 cm	0 cm	0 cm	0 cm
Tossa Espiolets	0 cm	0 cm	0 cm	0 cm
Grau Roig - FEDA	0 cm	0 cm	0 cm	0 cm
Fontverd	0 cm	0 cm	0 cm	0 cm
Ransol - FEDA	0 cm	0 cm	0 cm	0 cm
Setúria	0 cm	0 cm	0 cm	0 cm
Caborreu	0 cm	0 cm	0 cm	0 cm
La Solana	0 cm	0 cm	0 cm	0 cm
Envalira Antenes	0 cm	0 cm	0 cm	0 cm
Vall del Riu FEDA	0 cm	0 cm	0 cm	0 cm