MINISTERO DELLA DIFESA

meteomont Servizio Nazionale di previsione neve e valanghe

EAWS EUROPEAN AVALANCHE WARNING SERVICES

CARABINIERI

## GRAN SASSO EST - LAGA EST

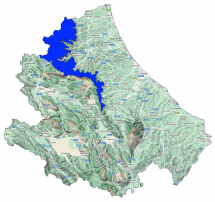

Bollettino Valanghe N. 347/2026 del 27/02/2026 ore 14.00

Validità 48 ore prossima emissione 28/02/2026

**A cura del Servizio METEOMONT dell'ARMA dei CARABINIERI**

**In collaborazione con Servizio Meteorologico dell'Aeronautica militare**

## SITUAZIONE alle 14:00 del 27/02/2026

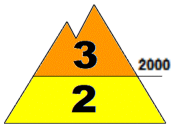


**SITUAZIONE TIPO: passaggio da poca a molta neve.**




**SITUAZIONE TIPO: situazione primaverile.**

| Quota neve (mslm) | Nord | Sud |
|---|---|---|
| | 1400 - 1500 | 1600 - 1700 |

| Altezza Neve (cm) | Neve al suolo | Neve Fresca | Quota (mslm) |
|---|---|---|---|
| | 000 | 000 | 1400 |
| | 000 | 000 | 1075 |

**VALANGHE OSSERVATE: Valanghe di piccole dimensioni, Valanghe di neve a debole coesione di fondo.**

## PREVISIONI 28/02/2026

# GRADO DI PERICOLO: MARCATO 3

## SITUAZIONE TIPO: passaggio da poca a molta neve.

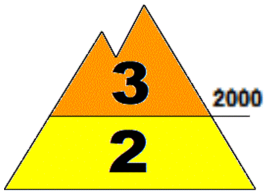


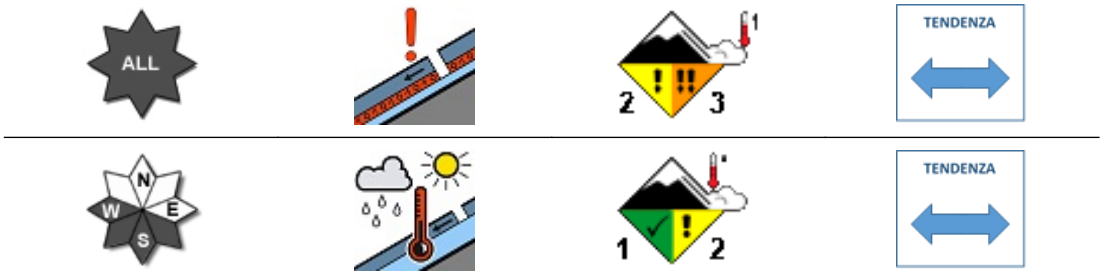


## SITUAZIONE TIPO: situazione primaverile.

**MANTO NEVOSO: La stabilità del manto nevoso è scarsa su alcuni punti (aree) per tutte le esposizioni al di sopra di 2000 mslm, possibili valanghe di dimensioni grandi.**
**La stabilità del manto nevoso è scarsa su alcuni punti (aree) per versanti al sole al di sotto di 2000 mslm, possibili valanghe di dimensioni medie.**

## AVVERTENZE

Il rialzo termico diurno richiede un'attenta valutazione temporale dell'escursione che eviti l'attraversamento di pendii ripidi nelle ore più calde della giornata.

## SCALA EUROPEA DEL GRADO DI PERICOLO VALANGHE

## LEGENDA PROBLEMA

**Bollettino realizzato su scala sinottica-regionale (standard EAWS). La sua valutazione non può escludere in alcun modo la necessità di una seria e capace valutazione locale del pericolo (singolo pendio) che può essere anche sensibilmente diverso. Le previsioni meteorologiche sono relative all'orario UTC (per l'Italia +1 in inverno e +2 in estate).**

MINISTERO DELLA DIFESA

meteomont
Servizio Nazionale di previsione neve e valanghe

EAWS EUROPEAN AVALANCHE WARNING SERVICES

CARABINIERI

# GRAN SASSO EST - LAGA EST

## PREVISIONE METEO

| Quota | | 28/02/2026 h6:00 | 28/02/2026 h12:00 | 28/02/2026 h18:00 |
|---|---|---|---|---|
| 1000 | Venti | 01 Nodi da S-Ovest | 02 Nodi da Ovest | 01 Nodi da Ovest |
| | Temperature | +07 °C | +09 °C | +08 °C |
| | Temp.percepita | 7 °C | 9 °C | 8 °C |
| 2000 | Venti | 01 Nodi da S-Ovest | 02 Nodi da S-Ovest | 02 Nodi da S-Ovest |
| | Temperature | +05 °C | +05 °C | +05 °C |
| | Temp.percepita | 5 °C | 5 °C | 5 °C |
| 3000 | Venti | 01 Nodi da Nord | 01 Nodi da S-Est | 01 Nodi da Sud |
| | Temperature | -01 °C | -01 °C | -01 °C |
| | Temp.percepita | -1 °C | -1 °C | -1 °C |
| Zero termico | | 2700-2900 m. | 2800-3000 m. | 2800-3000 m. |
| Fenomeno | | — | — | — |
| Stato del cielo | | | | |

## LEGENDA FENOMENI

— Assenza Fenomeni · Nebbia · Foschia · Pioggia debole · Pioggia moderata · Pioggia forte · Temporali

Nevicata debole · Nevicata moderata · Nevicata forte

## STATO DEL CIELO

Sereno · Poco nuvoloso · Nuvoloso · Molto nuvoloso · Coperto

## Parametri meteonivometrici registrati presso i campi di rilevamento il 27/02/2026.

| Località | Comune | Quota (m.s.l.m.) | Altezza neve (cm) | Neve caduta nelle 24 ore (cm) | Temp. Min (°C) | Temp. Max (°C) | Condizioni del tempo |
|---|---|---|---|---|---|---|---|
| FAVACCHIOLE | Crognaleto (TE) | 1016 | 0 | 0 | +4 | +14 | Assenza di precipitazioni |
| PRATO SELVA | Fano Adriano (TE) | 1355 | 0 | 0 | +6 | +14 | Assenza di precipitazioni |
| PIANO SAN PIETRO | Isola del Gran Sasso d'Italia (TE) | 950 | 0 | N.P. | N.P. | N.P. | Assenza di precipitazioni |
| PRATI DI TIVO | Pietracamela (TE) | 1380 | 0 | 0 | +3 | +15 | Assenza di precipitazioni |
| CEPPO | Rocca Santa Maria (TE) | 1349 | 0 | 0 | +5 | +12 | Assenza di precipitazioni |
| SAN PAOLO | Acquasanta Terme (AP) | 960 | 0 | 0 | +3 | +16 | Assenza di precipitazioni |
| COLLE SAN GIACOMO | Civitella del Tronto (TE) | 1075 | 0 | 0 | +6 | +15 | Assenza di precipitazioni |

**(*) Rilievi fuori campo**

**L'INFORMAZIONE E' PREVENZIONE - LEGGI L'ATTUALE GRADO DI PERICOLO VALANGHE!**

**IL CAPO DEL CENTRO NAZIONALE METEOMONT**
**(Ten. Col. RFI Emanuela Gini)**
**FIRMA AUTOGRAFA OMESSA AI SENSI**
**DELL'ART.3 DEL D.LGS N.39/1993**

**Bollettino realizzato su scala sinottica-regionale (standard EAWS). La sua valutazione non può escludere in alcun modo la necessità di una seria e capace valutazione locale del pericolo (singolo pendio) che può essere anche sensibilmente diverso. Le previsioni meteorologiche sono relative all'orario UTC (per l'Italia +1 in inverno e +2 in estate).**