Bulletin d'estimation du risque d'avalanche
(valable en dehors des pistes balisées et ouvertes)

MASSIF : Aravis

Rédigé le vendredi 27 février 2026 à 16h

Estimation des risques pour le : SAMEDI 28 FÉVRIER

MANTEAU NEIGEUX QUI SE RÉCHAUFFE AU FIL DE LA JOURNÉE. DÉPARTS DE PLUS EN PLUS NOMBREUX.

2

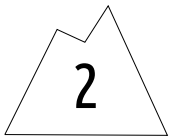

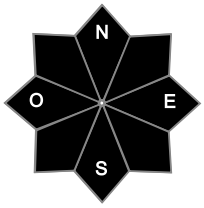

Indice de risque limité.

Départs spontanés : Neige humide au fil du réchauffement et plaques de fond.

Déclenchements provoqués : Neige humide sous les skis.

Indices de risque : 5 très fort - 4 fort - 3 marqué - 2 limité - 1 faible -- En noir : les pentes les plus dangereuses

Stabilité du manteau neigeux

Situation avalancheuse typique :

avalanches de fond

neige humide

Départs spontanés :

* **Plaques de fond**. En versants E/S/O à toute altitude et en versants N en-dessous de 1800 m. Départs possibles à toute heure du jour et de la nuit dans les pentes raides et lisses (dalles rocheuses, pentes herbeuses) mais plus nombreux au soleil. Taille 2 (moyenne) à 3 (grande).
* Départs en **neige humide, plus nombreux au fil du réchauffement diurne** et de la course du soleil. Départs ponctuels souvent dans les pentes raides et les vers les rochers/falaises. Une plaque peut aussi être déclenchée en cascade. Taille 2 (moyenne), rarement 3 (grande).
* Chutes de **corniches**, épaisses et volumineuses. Elles peuvent déclencher une plaque en contrebas.

Déclenchements provoqués :

* De la **neige humide** peut couler sous les skis au fil du réchauffement diurne.
* Présence locale d'une **couche fragile persistante enfouie en versants E/N/O au-dessus de 2000 m.** Difficile à déclencher mais elle peut être déclenchée **en cascade** et donner une avalanche de plus grande ampleur (cassure de 60cm/1m). La profondeur de l'enfouissement de la couche fragile varie énormément, même dans une même pente. Taille 2 (moyenne) à 3 (grande).

Qualité de la neige

Enneigement : bon pour une fin février. On peut chausser les skis vers 1200/1300 m en versants E/S/O et 1400/1500 m en versants Sud. Fort tassement sous l'effet de la douceur, grosses corniches, arêtes érodées par les forts vents pendant et après les perturbations (de SW puis NW/N).

Qualité de la neige samedi :

* Sous 1600/1800 m : le matin, la neige est croutée, puis elle devient rapidement lourde, humide même en profondeur.
* Au-dessus de 1600/1800 : dans les versants E/S/O, croute non portante à skis le matin en surface puis qui se ramollit au fil de la journée. Dans les versants N, la neige est restée assez froide mais elle est tassée.

Aperçu météo pour le samedi 28 février

nuit	matin	après-midi	soir

Ciel voilé qui se couvre en journée. Rares gouttes (flocons au-dessus de 1700 m) localement en fin de journée. Températures en légère baisse.

Pluie-Neige				
Iso 0 °C	2 600 m	2 300 m	2 000 m	1 800 m
Vent 2000 m	20 km/h	30 km/h	20 km/h	10 km/h
Vent 2500 m	30 km/h	40 km/h	25 km/h	20 km/h

Épaisseur de neige hors-piste

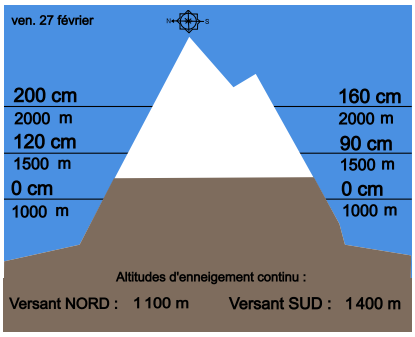

Précipitations à 1800 m

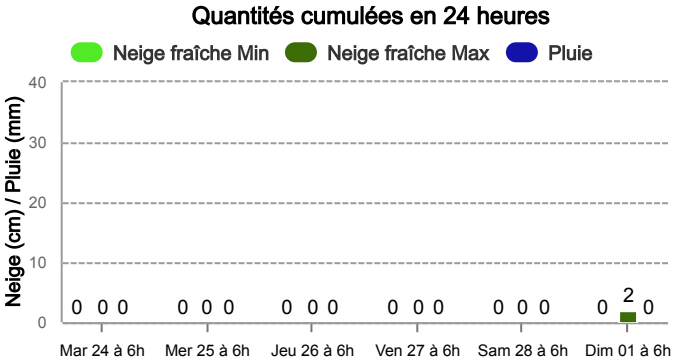

Tendance du dimanche 01 mars

2

Indice de risque limité

Peu d'évolution du manteau neigeux. Regel nocturne moins efficace. La journée, de nombreux nuages cachent les pentes. Isotherme 0°C vers 2200 m.

Pour consulter la vigilance en cours, veuillez vous rendre sur le site https://vigilance.meteofrance.fr/fr

Météo-France - 73 avenue de Paris, 94165 Saint-Mandé cedex - Contact : contact@meteo.fr

Rédigé par Météo-France avec la contribution des observateurs du réseau nivo-météorologiques. Partenariat : ANMSM (Maires de Stations de Montagne), DSF (Domaines Skiables de France), ADSP (Directeurs de Pistes et de la Sécurité des Stations de Sports d'Hiver) et autres acteurs de la montagne.

Bulletin neige & avalanches par téléphone au

0 892 68 10 20 Service 0,35 € / min + prix appel

RÉPUBLIQUE FRANÇAISE
Liberté Égalité Fraternité

METEO FRANCE
À VOS CÔTÉS, DANS UN CLIMAT QUI CHANGE

Bulletin d'estimation du risque d'avalanche

(valable en dehors des pistes balisées et ouvertes)

MASSIF : Aravis

Rédigé le vendredi 27 Février 2026 à 16h

Conditions nivo-météo des 7 derniers jours

	sam. 21/02				dim. 22/02				lun. 23/02				mar. 24/02				mer. 25/02				jeu. 26/02				ven. 27/02			
	03h	09h	15h	21h	03h	09h	15h	21h	03h	09h	15h	21h	03h	09h	15h	21h	03h	09h	15h	21h	03h	09h	15h	21h	03h	09h	15h	21h
Météo																												
Vent (km/h)	35	35	35	45	40	35	40	30	30	20	20	25	25	25	15	15	15	15	20	20	10	10	15	15	15	15	15	25
à 2500m																												
Vent (km/h)	20	20	20	20	20	20	25	20	20	10	15	15	15	15	10	10	10	10	10	10	5	5	10	10	10	10	10	20
à 2000m																												

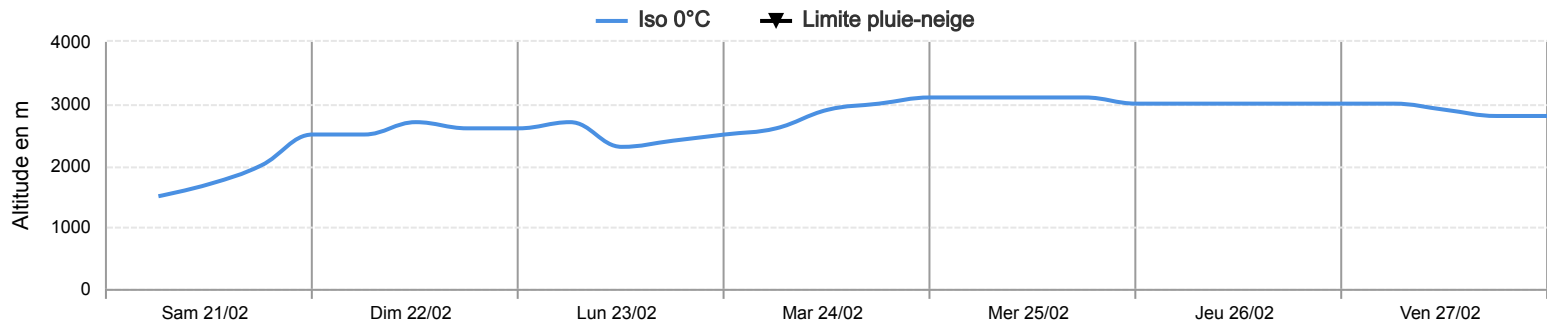

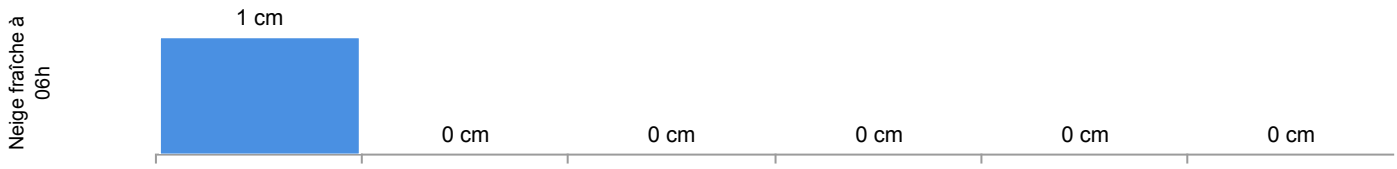

Risque d'avalanche	sam. 21/02	dim. 22/02	lun. 23/02	mar. 24/02	mer. 25/02	jeu. 26/02	ven. 27/02
	4	3	2	3	3	3	3

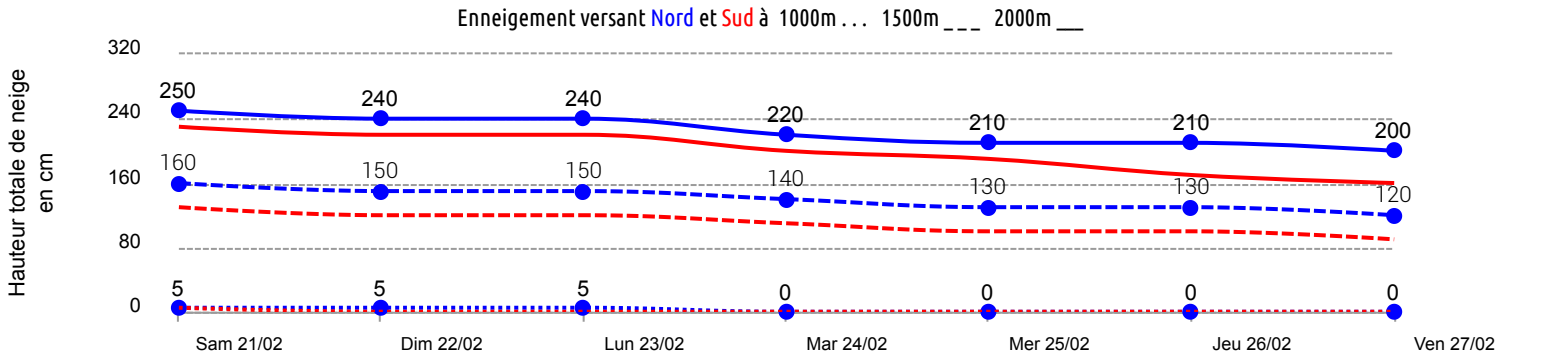

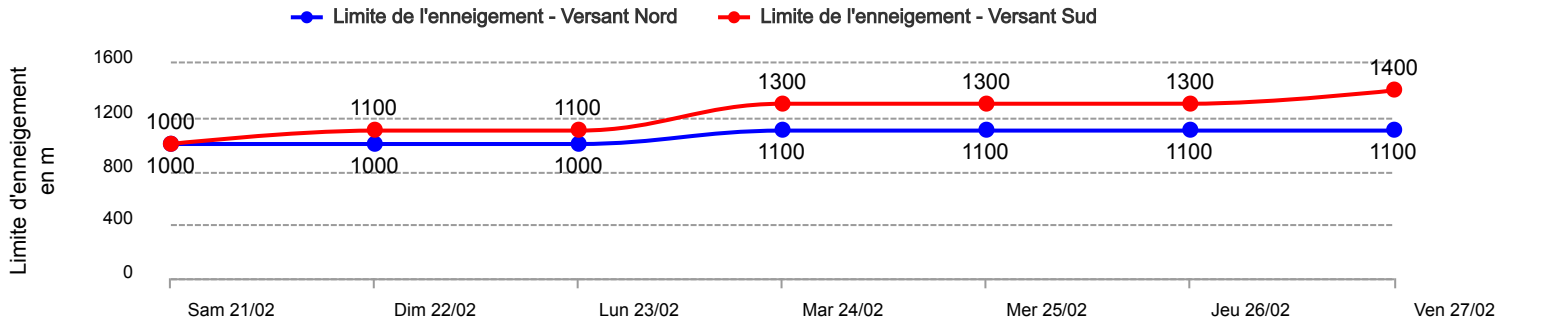

Pour consulter la vigilance en cours, veuillez vous rendre sur le site https://vigilance.meteofrance.fr/fr

Météo-France - 73 avenue de Paris, 94165 Saint-Mandé cedex - Contact : contact@meteo.fr

Bulletin neige & avalanches par téléphone au

0 892 68 10 20 Service 0,35 € / min + prix appel

Rédigé par Météo-France avec la contribution des observateurs du réseau nivo-météorologiques. Partenariat : ANMSM (Maires de Stations de Montagne), DSF (Domaines Skiables de France), ADSP (Directeurs de Pistes et de la Sécurité des Stations de Sports d'Hiver) et autres acteurs de la montagne.