Bulletin d'estimation du risque d'avalanche
(valable en dehors des pistes balisées et ouvertes)

MASSIF : Aspe Ossau

Rédigé le vendredi 27 février 2026 à 16h

Estimation des risques pour le : SAMEDI 28 FÉVRIER

STRUCTURES DE PLAQUES ENCORE POSSIBLES À L'OMBRE EN ALTITUDE.

2

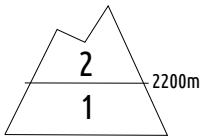

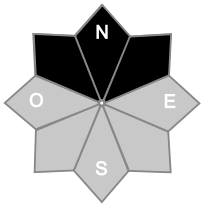

Au-dessus de 2200m indice de risque limité, plus bas indice faible.

Départs spontanés : Peu d'activité

Déclenchements provoqués : Plaques encore présentes en altitude.

Indices de risque : 5 très fort - 4 fort - 3 marqué - 2 limité - 1 faible -- En noir : les pentes les plus dangereuses

Stabilité du manteau neigeux

Situation avalancheuse typique : neige ventée

Déclenchements provoqués : **Au-dessus de 2200 à 2300m vers les pentes Nord**, des plaques à vent peu épaisses qui se sont formées par le vent de sud-ouest de ce vendredi, peuvent se déclencher facilement par le passage de skieurs, elles génèrent des avalanches de petites tailles rarement moyennes. Les plaques plus épaisses reposant sur les sous-couches fragiles bien enfouies sont maintenant difficilement déclenchables.
Sous 2200m le manteau neigeux est bien stabilisé avec une bonne cohésion de regel.

Départs spontanés : Peu d'activité samedi avec un net rafraîchissement et des chutes de neige faibles.

Qualité de la neige

Enneigement : Très bon pour la saison au-dessus de 1500 m, sur les massifs avec des combes très bien enneigées en altitudes, les corniches imposantes. Le temps très printanier de cette semaine a fait bien fondre la neige sous 1400 à 1500 m.
Limites skiables : à partir de 1400 à 1600 m suivant les versants, parfois plus bas.
État de la neige : Un peu de neige fraîche le matin reposant sur une sous-couche portante, occasionnellement bien regelée, et très localement meuble vers les pentes Nord.

Aperçu météo pour le samedi 28 février

	nuit	matin	après-midi	soir
Pluie-Neige	1 800 m	1 500 m	1 500 m	
Iso 0 °C	2 000 m	1 800 m	1 800 m	1 700 m
Vent 1500 m	10 km/h	10 km/h	15 km/h	5 km/h
Vent 3000 m	15 km/h	10 km/h	10 km/h	10 km/h

Épaisseur de neige hors-piste

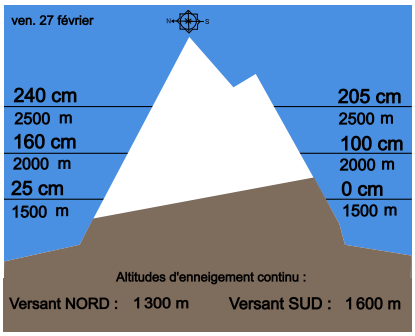

Précipitations à 1800 m

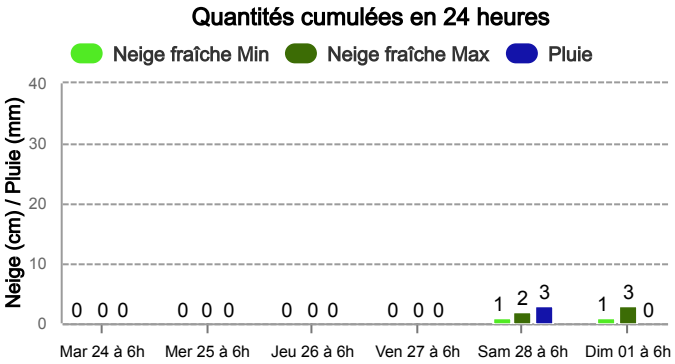

Tendance du dimanche 01 mars

2

Indice de risque limité

Pas d'évolution.

Pour consulter la vigilance en cours, veuillez vous rendre sur le site https://vigilance.meteofrance.fr/fr

Météo-France - 73 avenue de Paris, 94165 Saint-Mandé cedex - Contact : contact@meteo.fr

Rédigé par Météo-France avec la contribution des observateurs du réseau nivo-météorologiques. Partenariat : ANMSM (Maires de Stations de Montagne), DSF (Domaines Skiables de France), ADSP (Directeurs de Pistes et de la Sécurité des Stations de Sports d'Hiver) et autres acteurs de la montagne.

Bulletin neige & avalanches par téléphone au
0 892 68 10 20 Service 0,35 € / min + prix appel

RÉPUBLIQUE FRANÇAISE
Liberté Égalité Fraternité

METEO FRANCE
À VOS CÔTÉS, DANS UN CLIMAT QUI CHANGE

Bulletin d'estimation du risque d'avalanche

(valable en dehors des pistes balisées et ouvertes)

MASSIF : Aspe Ossau

Rédigé le vendredi 27 Février 2026 à 16h

Conditions nivo-météo des 7 derniers jours

	sam. 21/02				dim. 22/02				lun. 23/02				mar. 24/02				mer. 25/02				jeu. 26/02				ven. 27/02			
	03h	09h	15h	21h	03h	09h	15h	21h	03h	09h	15h	21h	03h	09h	15h	21h	03h	09h	15h	21h	03h	09h	15h	21h	03h	09h	15h	21h
Météo																												
Vent (km/h)	15	10	15	20	20	25	30	30	25	20	25	20	60	45	35	25	25	25	30	30	30	30	30	35	40	45	30	25
à 3000m																												
Vent (km/h)	5	2	5	5	5	5	10	10	10	5	10	5	25	20	15	15	10	10	15	15	15	15	15	15	25	25	20	10
à 1500m																												

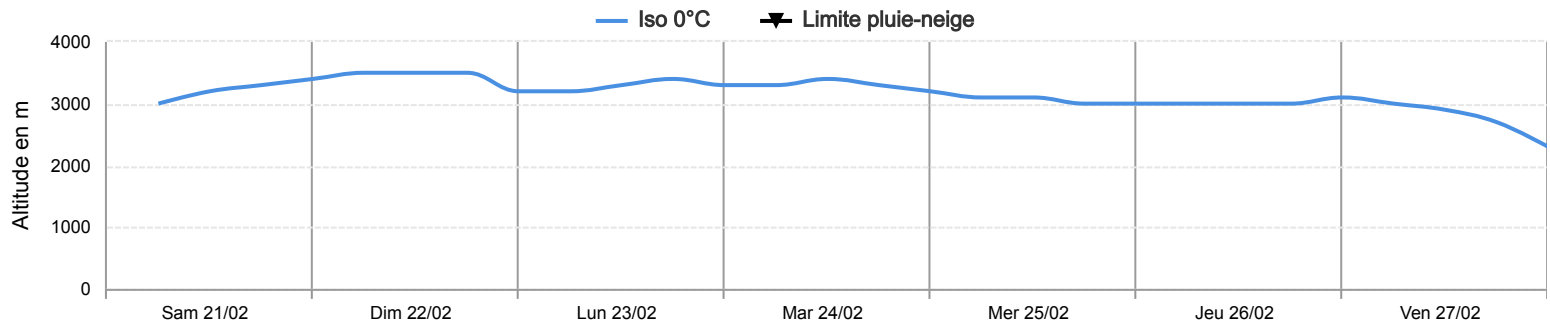

Neige fraîche à 06h

Sam 21/02	Dim 22/02	Lun 23/02	Mar 24/02	Mer 25/02	Jeu 26/02
0 cm	0 cm	0 cm	0 cm	0 cm	0 cm

Risque d'avalanche	sam. 21/02	dim. 22/02	lun. 23/02	mar. 24/02	mer. 25/02	jeu. 26/02	ven. 27/02
	3	3	3	2	2	2	2

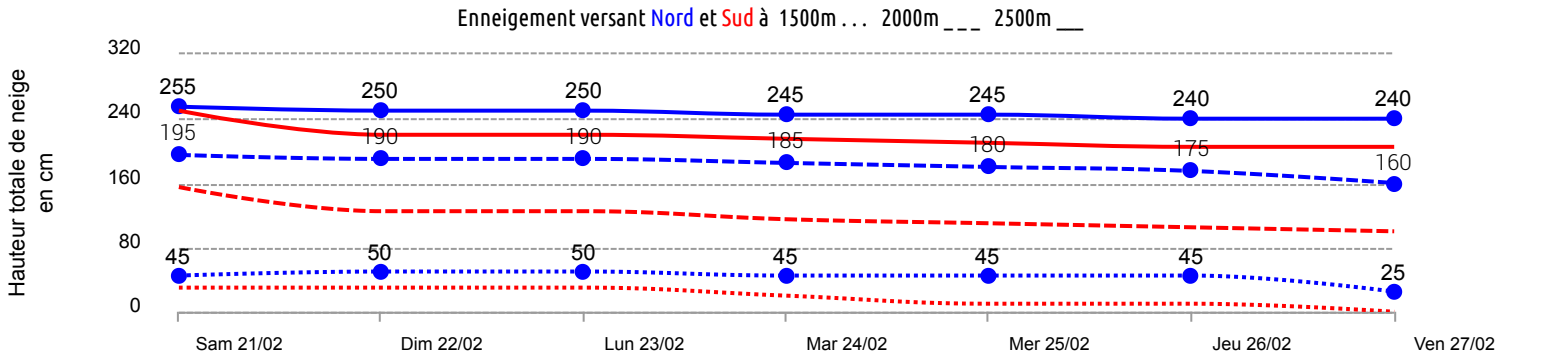

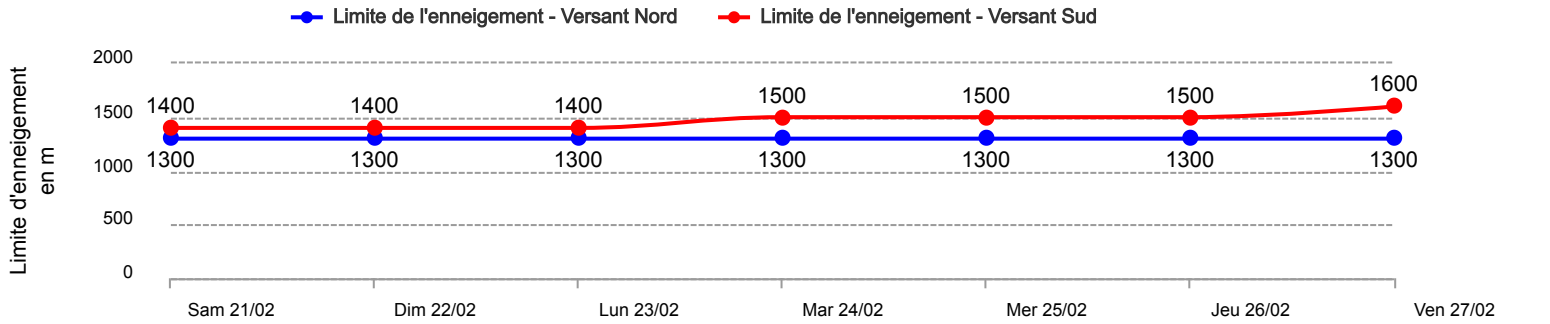

Pour consulter la vigilance en cours, veuillez vous rendre sur le site https://vigilance.meteofrance.fr/fr

Météo-France - 73 avenue de Paris, 94165 Saint-Mandé cedex - Contact : contact@meteo.fr

Bulletin neige & avalanches par téléphone au

0 892 68 10 20 Service 0,35 € / min + prix appel

Rédigé par Météo-France avec la contribution des observateurs du réseau nivo-météorologiques. Partenariat : ANMSM (Maires de Stations de Montagne), DSF (Domaines Skiables de France), ADSP (Directeurs de Pistes et de la Sécurité des Stations de Sports d'Hiver) et autres acteurs de la montagne.