Bulletin d'estimation du risque d'avalanche
(valable en dehors des pistes balisées et ouvertes)

MASSIF : Belledonne

Rédigé le vendredi 27 février 2026 à 16h

Estimation des risques pour le : SAMEDI 28 FÉVRIER

PLAQUES DE FOND EN MOYENNE MONTAGNE ET PLAQUES DURES DANS LES UBACS D'ALTITUDE.

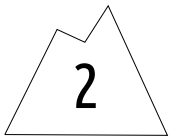

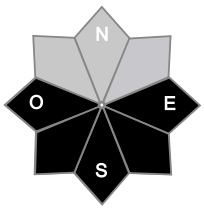

Indice de risque limité.

Départs spontanés : Aléatoires, sous forme d'avalanche de glissement.

Déclenchements provoqués : Rares plaques en versant froid.

Indices de risque : 5 très fort - 4 fort - 3 marqué - 2 limité - 1 faible -- En noir : les pentes les plus dangereuses

Stabilité du manteau neigeux

Situation avalancheuse typique : avalanches de fond couche fragile persistante

Sous l'effet d'une semaine de soleil et de grande douceur, le manteau neigeux s'est considérablement tassé et il est maintenant bien consolidé en dessous de 2000/2400 m selon les versants. A plus haute altitude, il reste quelques instabilités très localement.
Départs spontanés : Samedi, la baisse des températures et de l'ensoleillement va limiter l'humidification et diminuer le risque d'avalanche de neige lourde. Par contre, en raison de l'importante inertie lors de la percolation de l'eau dans le manteau neigeux, des avalanches de glissement emportant la totalité de la neige en place jusqu'au sol resteront envisageables. Ces départs, possibles à toute heure, devraient être de taille moyenne, rarement de taille 3, et se produire en dessous de 2000/2400 m.
Déclenchements provoqués : Dans les versants ombragés de haute montagne, on ne peut pas exclure la possibilité de déclencher une plaque de neige compactée par le vent qui reposerait sur une couche fragile insuffisamment enfouie, par exemple en bordure de zone d'accumulation ou à proximité des rochers. Le risque est faible, mais en cas d'avalanche la cassure peut facilement dépasser un mètre.

Qualité de la neige

Qualification de l'enneigement : l'enneigement commence à régresser tout en bas, mais est bon pour la saison dès 1200 m, voire abondant au dessus de 1500 m environ, notamment dans les combes d'altitude. On trouve des crêtes un peu dégarnies par le vent, ou au contraire des corniches assez conséquentes.

Limites skiables : vers 1300/1400 m.

Qualité de la neige vendredi : Sous 2000/2400 m voire plus haut en sud, manteau neigeux de type printanier avec une neige croûtée par le regel nocturne, s'humidifiant en journée moins profondément que les jours passés. Dans les versants ombragés au-dessus de 2000/2400 m, neige restée davantage froide, bien que de plus en plus densifiée au fil des jours. A proximité des crêtes, neige parfois soufflée ou travaillée par le vent.

Aperçu météo pour le samedi 28 février

	nuit	matin	après-midi	soir
Pluie-Neige				1 600 m
Iso 0 °C	2 800 m	2 400 m	2 200 m	1 900 m
Vent 2000 m	10 km/h	10 km/h	15 km/h	10 km/h
Vent 3000 m	25 km/h	30 km/h	30 km/h	20 km/h

Épaisseur de neige hors-piste

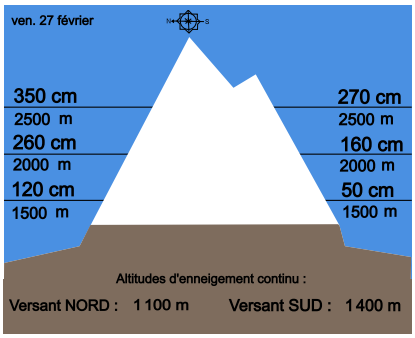

Précipitations à 1800 m

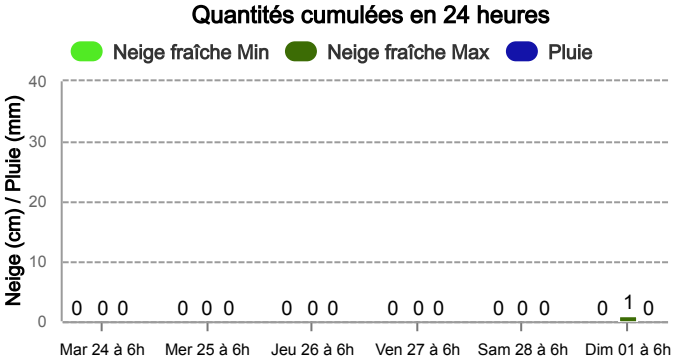

Tendance du dimanche 01 mars

Indice de risque limité

Risques stationnaires ou en légère baisse dimanche.

Pour consulter la vigilance en cours, veuillez vous rendre sur le site https://vigilance.meteofrance.fr/fr

Météo-France - 73 avenue de Paris, 94165 Saint-Mandé cedex - Contact : contact@meteo.fr

Rédigé par Météo-France avec la contribution des observateurs du réseau nivo-météorologiques. Partenariat : ANMSM (Maires de Stations de Montagne), DSF (Domaines Skiables de France), ADSP (Directeurs de Pistes et de la Sécurité des Stations de Sports d'Hiver) et autres acteurs de la montagne.

Bulletin neige & avalanches par téléphone au 0 892 68 10 20 Service 0,35 € / min + prix appel

Bulletin d'estimation du risque d'avalanche

(valable en dehors des pistes balisées et ouvertes)

MASSIF : Belledonne

Rédigé le vendredi 27 février 2026 à 16h

Conditions nivo-météo des 7 derniers jours

	sam. 21/02				dim. 22/02				lun. 23/02				mar. 24/02				mer. 25/02				jeu. 26/02				ven. 27/02			
	03h	09h	15h	21h	03h	09h	15h	21h	03h	09h	15h	21h	03h	09h	15h	21h	03h	09h	15h	21h	03h	09h	15h	21h	03h	09h	15h	21h
Météo																												
Vent (km/h)	65	60	60	60	55	50	45	40	40	45	45	45	45	35	15	10	10	10	15	5	0	5	5	5	10	5	15	20
à 3000m																												
Vent (km/h)	25	25	25	20	15	10	15	15	15	15	15	15	15	15	10	5	5	5	10	5	5	5	0	5	5	5	0	5
à 2000m																												

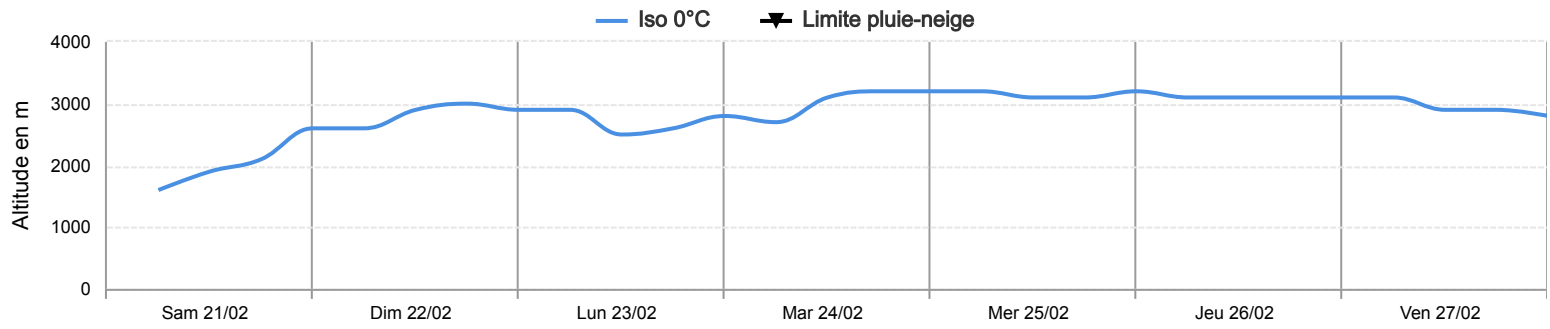

Neige fraîche à 06h

Sam 21/02	Dim 22/02	Lun 23/02	Mar 24/02	Mer 25/02	Jeu 26/02
0 cm	0 cm	0 cm	0 cm	0 cm	0 cm

Risque d'avalanche	sam. 21/02	dim. 22/02	lun. 23/02	mar. 24/02	mer. 25/02	jeu. 26/02	ven. 27/02
	4	3	3	3	3	3	2

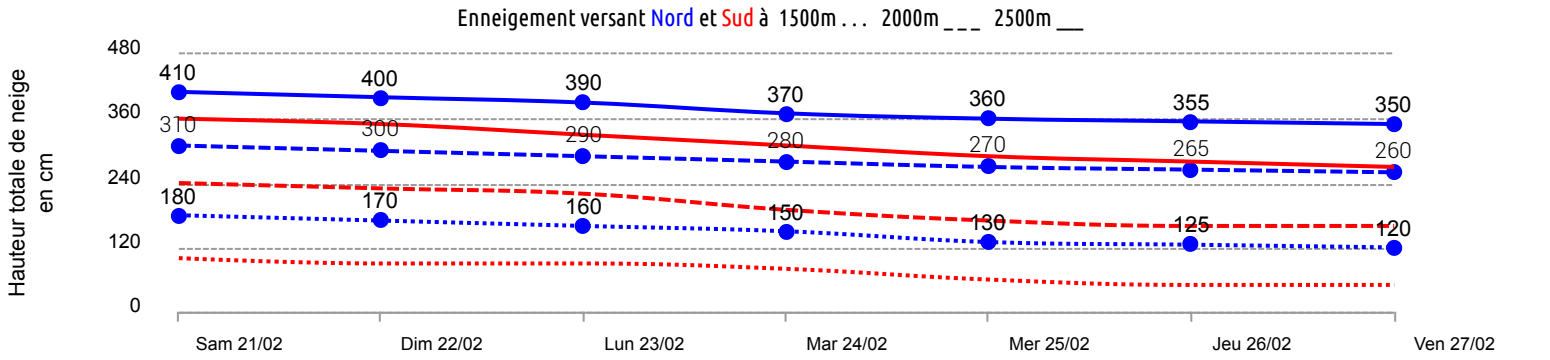

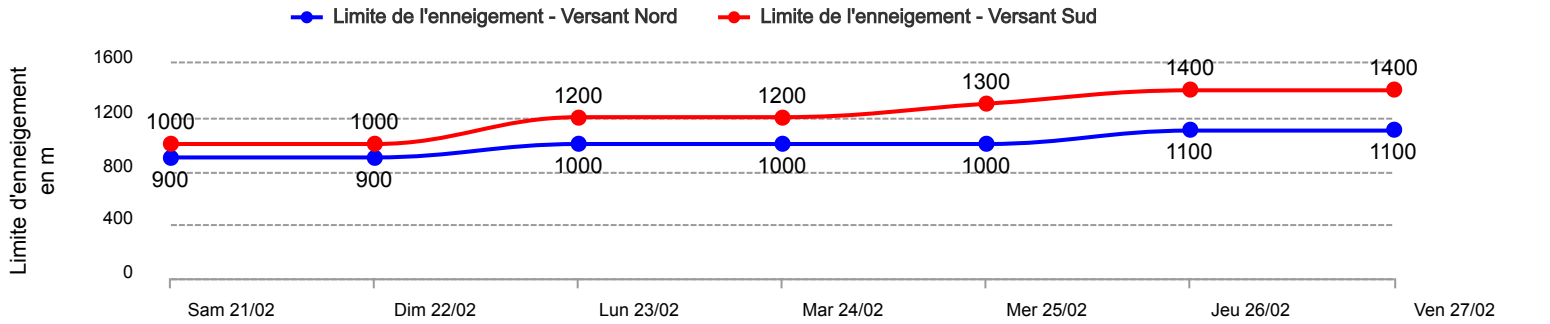

Pour consulter la vigilance en cours, veuillez vous rendre sur le site https://vigilance.meteofrance.fr/fr

Météo-France - 73 avenue de Paris, 94165 Saint-Mandé cedex - Contact : contact@meteo.fr

Bulletin neige & avalanches par téléphone au 0 892 68 10 20 Service 0,35 € / min + prix appel

Rédigé par Météo-France avec la contribution des observateurs du réseau nivo-météorologiques. Partenariat : ANMSM (Maires de Stations de Montagne), DSF (Domaines Skiables de France), ADSP (Directeurs de Pistes et de la Sécurité des Stations de Sports d'Hiver) et autres acteurs de la montagne.