# Bulletin d'estimation du risque d'avalanche

(valable en dehors des pistes balisées et ouvertes)

# MASSIF : Champsaur

Rédigé le vendredi 27 février 2026 à 16h

## Estimation des risques pour le : SAMEDI 28 FÉVRIER

**PLAQUES EN ALTITUDE, DIFFICILES À SOLLICITER - ACTIVITÉ NATURELLE AU SOLEIL LIMITÉE**

2

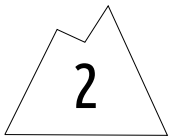


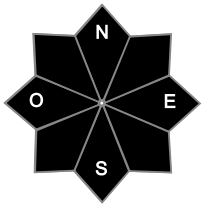


Indice de risque limité.

**Départs spontanés :** un peu d'activité en neige humide au soleil / Quelques avalanches de fond.

**Déclenchements provoqués :** plaques difficiles à déclencher, mais pouvant engendrer d'épaisses cassures.

Indices de risque : 5 très fort - 4 fort - 3 marqué - 2 limité - 1 faible -- En noir : les pentes les plus dangereuses

## Stabilité du manteau neigeux

**Situation avalancheuse typique :** couche fragile persistante neige humide

**Déclenchements provoqués :** * Au-dessus de 2200 m environ, dans les pentes où la neige n'est pas croûtée, des plaques difficiles à déclencher reposent sur des couches fragiles persistantes enfouies à la base du manteau neigeux. Déclenchement peu probable en milieu de pente, mais possible dans les endroits peu enneigés, ou dans les transitions entre secteurs très enneigés et peu enneigés (abords des croupes, bords des couloirs, à proximité des rochers, etc.). Cassures épaisses, parfois larges en ubacs, et pouvant se propager dans les grandes pentes très enneigées, emportant la quasi-totalité du manteau neigeux en place.
* Le passage d'un skieur dans une pente raide ayant trop chauffé peut favoriser un départ en neige humide.

**Départs spontanés :** * L'activité en neige humide au soleil reste limitée. Rares avalanches petites à moyennes dans les pentes raides ensoleillées près des rochers, au fil de la journée (taille 1 à 2). Départ linéaire possible.
* Quelques avalanches de fond peuvent céder spontanément à toute heure du jour ou de la nuit sur terrain favorable (pentes herbeuses, dalles rocheuses). Avalanches moyennes (taille 2).

## Qualité de la neige

**L'enneigement** est excédentaire pour un mois de février. Avec la douceur des derniers jours, les limites d'enneigement remontent dans les pentes bien exposées au soleil.
Hauteurs de neige observées : 60 cm au hameau des Portes dans le Valgaudemar à 1270 m, 150 cm à la Nivôse d'Orcières à 2280 m, et 185 cm au-dessus de Prapic à 2480 m.

**Limite d'enneigement skiable** à partir de 1100/1200 m en ubacs, désormais 1500/1700 m en adrets pas trop raides.

**État de la neige de surface** : manteau neigeux printanier en adrets, croûté le matin, s'humifiant au soleil l'après-midi, mais à des altitudes nettement moins élevées que les jours précédents. En versants nord-est, nord et nord-ouest, le manteau neigeux reste froid, ou humidifié / regelé seulement en surface sous 2100 m. Plus haut, la neige est plus ou moins cartonnée ou durcie par les épisodes de vent passés, mais évolue de plus en plus en vieille neige meuble dans les pentes ou combes abritées.

## Aperçu météo pour le samedi 28 février

| nuit | matin | après-midi | soir |
|---|---|---|---|
| | | | |

Nombreux voiles nuageux d'altitude, temporairement denses. Un peu moins doux que les jours précédents.

| Pluie-Neige | | | | |
|---|---|---|---|---|
| Iso 0 °C | 2 800 m | 2 500 m | 2 400 m | 2 300 m |
| Vent 2000 m | ↖ 5 km/h | ↖ 5 km/h | → 10 km/h | ↓ 5 km/h |
| Vent 3000 m | ↗ 20 km/h | ↗ 25 km/h | → 25 km/h | → 15 km/h |

## Épaisseur de neige hors-piste

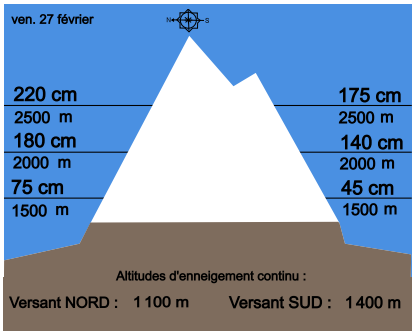


## Précipitations à 1800 m

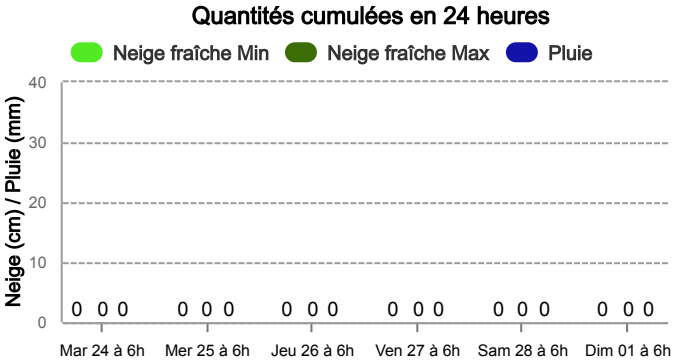


## Tendance du dimanche 01 mars

2

**Indice de risque limité**

Encore des plaques difficiles à déclencher en altitude. Activité en neige humide plus faible.
Les quelques averses attendues ont peu d'influence sur la stabilité du manteau neigeux.
Maintien probable d'un risque limité.

Pour consulter la vigilance en cours, veuillez vous rendre sur le site https://vigilance.meteofrance.fr/fr

Météo-France - 73 avenue de Paris, 94165 Saint-Mandé cedex - Contact : contact@meteo.fr

Rédigé par Météo-France avec la contribution des observateurs du réseau nivo-météorologiques. Partenariat : ANMSM (Maires de Stations de Montagne), DSF (Domaines Skiables de France), ADSP (Directeurs de Pistes et de la Sécurité des Stations de Sports d'Hiver) et autres acteurs de la montagne.

Bulletin neige & avalanches par téléphone au 0 892 68 10 20 Service 0,35 € / min + prix appel

RÉPUBLIQUE FRANÇAISE
*Liberté Égalité Fraternité*

METEO FRANCE
À VOS CÔTÉS, DANS UN CLIMAT QUI CHANGE

# Bulletin d'estimation du risque d'avalanche

## (valable en dehors des pistes balisées et ouvertes)

# MASSIF : Champsaur

Rédigé le vendredi 27 février 2026 à 16h

## Conditions nivo-météo des 7 derniers jours

| | sam. 21/02 | | | | dim. 22/02 | | | | lun. 23/02 | | | | mar. 24/02 | | | | mer. 25/02 | | | | jeu. 26/02 | | | | ven. 27/02 | | | |
|---|---|---|---|---|---|---|---|---|---|---|---|---|---|---|---|---|---|---|---|---|---|---|---|---|---|---|---|---|
| | 03h | 09h | 15h | 21h | 03h | 09h | 15h | 21h | 03h | 09h | 15h | 21h | 03h | 09h | 15h | 21h | 03h | 09h | 15h | 21h | 03h | 09h | 15h | 21h | 03h | 09h | 15h | 21h |
| Météo | | | | | | | | | | | | | | | | | | | | | | | | | | | | |
| Vent (km/h) | 60 | 60 | 60 | 55 | 45 | 30 | 30 | 35 | 30 | 40 | 35 | 30 | 25 | 15 | 5 | 10 | 10 | 10 | 10 | 10 | 10 | 5 | 10 | 10 | 10 | 10 | 10 | 15 |
| à 3000m | ↓ | ↓ | ↓ | ↓ | ↓ | ↘ | → | ↓ | ↘ | ↘ | ↘ | ↓ | ↓ | ↓ | ↘ | ↑ | ↖ | ↑ | ↖ | ↖ | → | ↗ | ↗ | ↻ | ↘ | ↘ | ↗ | ↗ |
| Vent (km/h) | 35 | 45 | 40 | 30 | 15 | 10 | 15 | 15 | 15 | 15 | 10 | 10 | 10 | 10 | 0 | 5 | 5 | 5 | 5 | 10 | 5 | 5 | 5 | 5 | 5 | 5 | 5 | 5 |
| à 2000m | ↓ | ↓ | ↓ | ↓ | ↓ | ↘ | ↘ | ↓ | ↘ | ↓ | ↓ | ↓ | ↓ | ↓ | ↻ | ↖ | ← | ← | ↑ | ← | ← | ← | ↑ | ← | ← | ↙ | ↑ | ↖ |

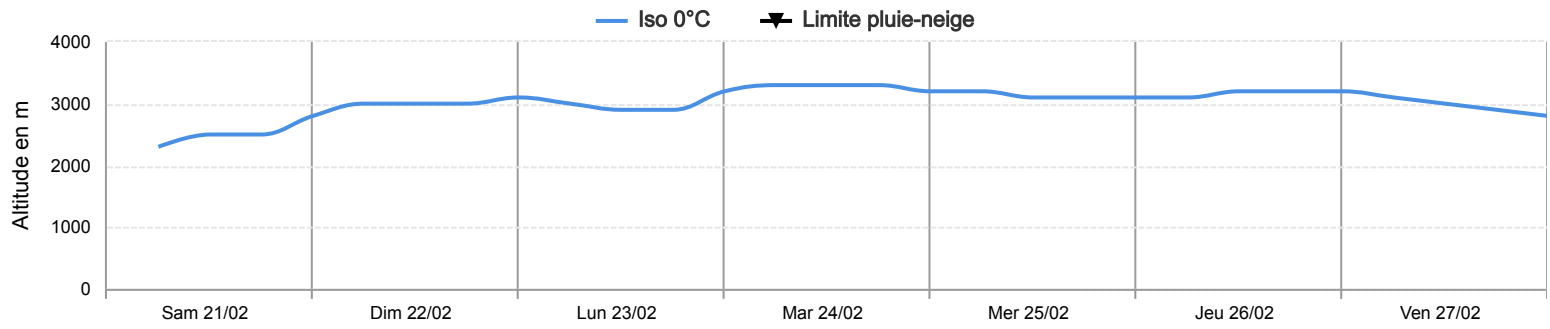


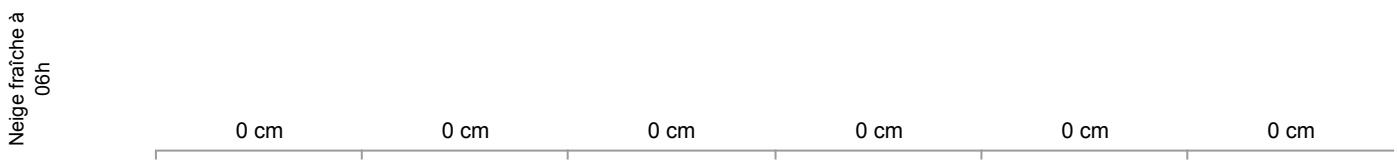


| Risque d'avalanche | sam. 21/02 | dim. 22/02 | lun. 23/02 | mar. 24/02 | mer. 25/02 | jeu. 26/02 | ven. 27/02 |
|---|---|---|---|---|---|---|---|
| | 4 | 3 | 3 | 3 | 3 | 3 | 2 |

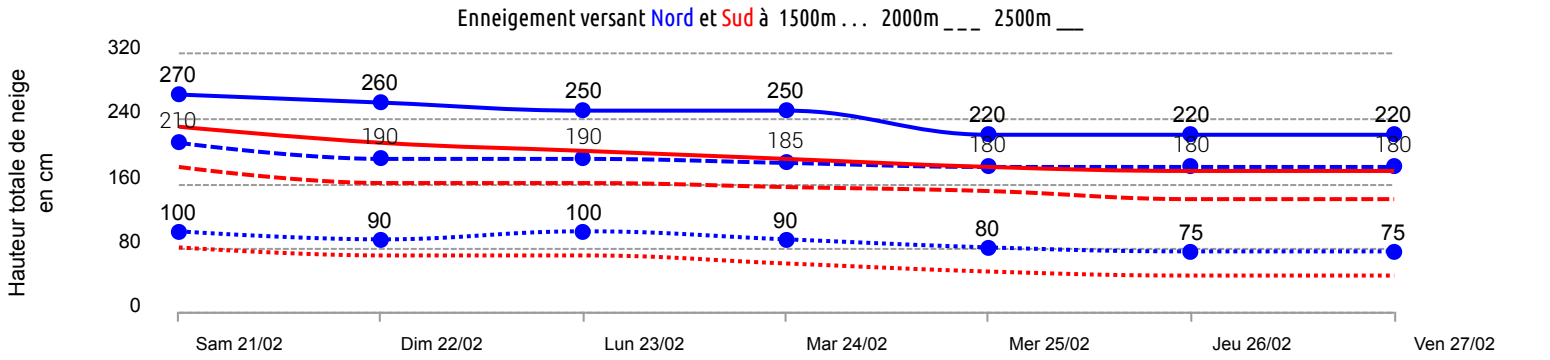


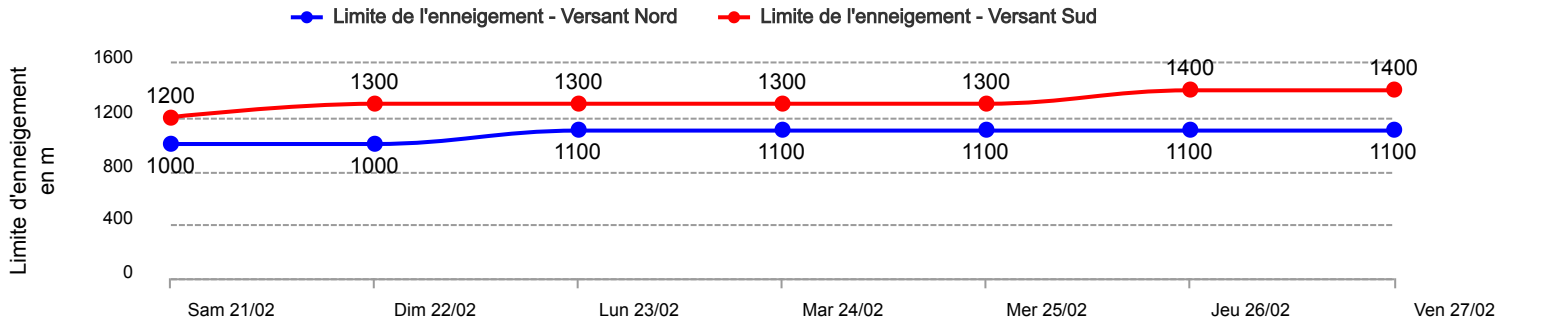


Pour consulter la vigilance en cours, veuillez vous rendre sur le site https://vigilance.meteofrance.fr/fr


Météo-France - 73 avenue de Paris, 94165 Saint-Mandé cedex - Contact : contact@meteo.fr


Bulletin neige & avalanches par téléphone au

0 892 68 10 20 Service 0,35 € / min + prix appel


Rédigé par Météo-France avec la contribution des observateurs du réseau nivo-météorologiques. Partenariat : ANMSM (Maires de Stations de Montagne), DSF (Domaines Skiables de France), ADSP (Directeurs de Pistes et de la Sécurité des Stations de Sports d'Hiver) et autres acteurs de la montagne.