RÉPUBLIQUE FRANÇAISE
Liberté Égalité Fraternité

METEO FRANCE
À VOS CÔTÉS, DANS UN CLIMAT QUI CHANGE

Bulletin d'estimation du risque d'avalanche
(valable en dehors des pistes balisées et ouvertes)
MASSIF : Haute-Ariege

Rédigé le vendredi 27 février 2026 à 16h

Estimation des risques pour le : SAMEDI 28 FÉVRIER

PAUSE TEMPORAIRE DANS L'HUMIDIFICATION, MAINTIENT DE QUELQUES STRUCTURES INSTABLES EN ALTITUDE.

2

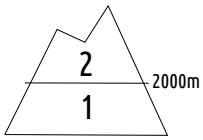

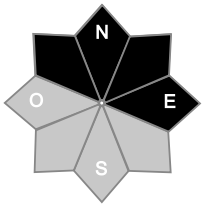

plaques en nord

Au-dessus de 2000m indice de risque limité, plus bas indice faible.

Départs spontanés : Peu probable avec le rafraichissement, quelques coulées possibles à basse altitude.

Déclenchements provoqués : Possibles structures de plaques dans les secteurs restés froids au delà de 2000/2200 m.

Indices de risque : 5 très fort - 4 fort - 3 marqué - 2 limité - 1 faible -- En noir : les pentes les plus dangereuses

Stabilité du manteau neigeux

Situation avalancheuse typique : neige ventée couche fragile persistante

Déclenchements provoqués :
Au-delà de 2000/2100 m, dans les secteurs restés en neige froide, donc plutôt orientés nord, possibles déclenchements au passage d'un pratiquant d'avalanches de taille 1 à 2. En effet, les dernières chutes de neige alternant avec des périodes de vent d'Ouest à Nord-Ouest ont favorisé la création de couches successives de plaques et de fines couches fragiles de grains anguleux. Les premières couches sont facilement sollicitables mais généralement très fines ; Des structures de plaques plus épaisse sont aussi présentes mais elles se semblent déclenchables que par fortes contraintes répétées.
Observables : neige travaillée par le vent en surface, couche de neige sans cohésion à 15/30 cm de la surface, une petite coupe rapide du manteau en surface neigeux peut suffire à identifier ces couches fragiles.

Départs spontanés :
- Activité avalancheuse de neige humide en baisse avec l'arrivée d'air plus froid et le manque d'ensoleillement. De rares départs peuvent se produire en dessous de 1500 à 1600m sous les premières précipitations pluvieuses cette nuit et demain matin alors que l'humidification en cours cesse plus haut.
Observables : risque accentué en dessous de la limite pluie-neige. neige pourrie, très humide jusqu'en profondeur.
- Présence par endroits de larges fissures (gueules de baleine) dans les pentes au sol lisse, signes avant-coureurs d'une éventuelle avalanche de glissement pouvant encore se produire à tout moment.

Autre :
- La neige a pris des allures printanières dans de nombreux secteurs avec un risque accru de glissade sur de la neige dure ou glacée en matinée après un bon regel nocturne, parfois encore plus tardivement en versant ouest. Certaines crêtes d'altitude sont aussi localement en glace dure.
- Les corniches sont volumineuses près des crêtes et sont fragilisées par l'humidification des derniers jours. Des ruptures ont été observées par endroits.

Qualité de la neige

Enneigement :
Avec les passages neigeux qui se sont succédé depuis janvier, l'enneigement est excédentaire par rapport aux normales pour la période. Les vallons ombragés sont encore bien enneigés avec des quantités de neige importantes dès 1400 m.
Les derniers jours chauds et ensoleillées ont fait remonter la limite skiable autour de 1500 à 1700m plein Sud alors que certaines vallées ombragées sont encore enneigées dès 1100 à 1200m

Qualité de la neige :
Bon regel nocturne des pentes humidifiées les jours précédents, avec une neige dure dès 1500 à 1700m dans les clairières mais pouvant rester humide voire pourrie en foret où le regel est moins efficace. Les crêtes, cols et sommets sont souvent pelés et en neige dure en expositions ouest alors que de grosses accumulation sont déjà présentes à 1700/1800m en versant Est.
En altitude, à partir de 1800m en général, rarement plus bas, neige encore sèche souvent en poudre dense dans les pentes abritées du vent d'Ouest alternant avec des secteurs en neige beaucoup plus dure.

Aperçu météo pour le samedi 28 février

	nuit	matin	après-midi	soir
Petite perturbation , averses de neige et fraîcheur.				
Pluie-Neige	1 800 m	1 500 m	1 500 m	1 400 m
Iso 0 °C	2 600 m	2 100 m	2 100 m	1 800 m
Vent 2000 m	10 km/h	10 km/h	15 km/h	5 km/h
Vent 3000 m	30 km/h	20 km/h	20 km/h	15 km/h

Pour consulter la vigilance en cours, veuillez vous rendre sur le site https://vigilance.meteofrance.fr/fr

Météo-France - 73 avenue de Paris, 94165 Saint-Mandé cedex - Contact : contact@meteo.fr

Rédigé par Météo-France avec la contribution des observateurs du réseau nivo-météorologiques. Partenariat : ANMSM (Maires de Stations de Montagne), DSF (Domaines Skiables de France), ADSP (Directeurs de Pistes et de la Sécurité des Stations de Sports d'Hiver) et autres acteurs de la montagne.

Bulletin neige & avalanches par téléphone au
0 892 68 10 20 Service 0,35 € / min + prix appel

Bulletin d'estimation du risque d'avalanche

(valable en dehors des pistes balisées et ouvertes)

MASSIF : Haute-Ariege

Rédigé le vendredi 27 février 2026 à 16h

Épaisseur de neige hors-piste

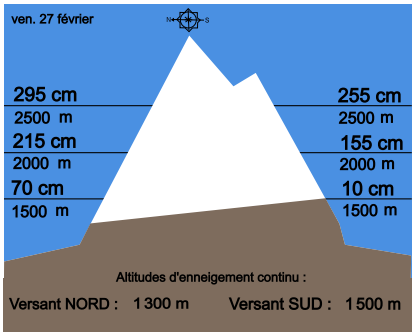

Précipitations à 1800 m

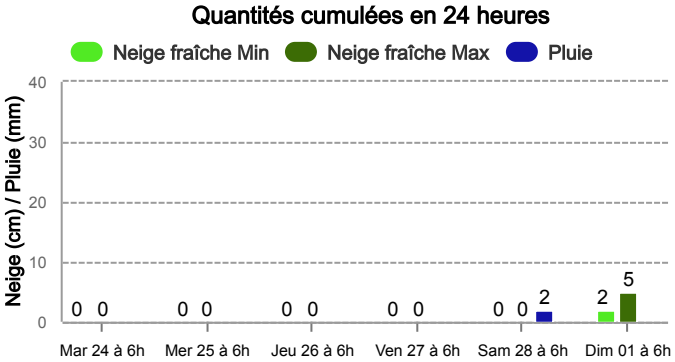

Tendance du dimanche 01 mars

Indice de risque limité

Reprise de l'activité en neige humide dimanche avec le retour du soleil.

Pour consulter la vigilance en cours, veuillez vous rendre sur le site https://vigilance.meteofrance.fr/fr

Météo-France - 73 avenue de Paris, 94165 Saint-Mandé cedex - Contact : contact@meteo.fr

Rédigé par Météo-France avec la contribution des observateurs du réseau nivo-météorologiques. Partenariat : ANMSM (Maires de Stations de Montagne), DSF (Domaines Skiables de France), ADSP (Directeurs de Pistes et de la Sécurité des Stations de Sports d'Hiver) et autres acteurs de la montagne.

Bulletin neige & avalanches par téléphone au

0 892 68 10 20 Service 0,35 € / min + prix appel

RÉPUBLIQUE FRANÇAISE
Liberté Égalité Fraternité

METEO FRANCE
À VOS CÔTÉS, DANS UN CLIMAT QUI CHANGE

Bulletin d'estimation du risque d'avalanche

(valable en dehors des pistes balisées et ouvertes)

MASSIF : Haute-Ariege

Rédigé le vendredi 27 Février 2026 à 16h

Conditions nivo-météo des 7 derniers jours

	sam. 21/02				dim. 22/02				lun. 23/02				mar. 24/02				mer. 25/02				jeu. 26/02				ven. 27/02			
	03h	09h	15h	21h	03h	09h	15h	21h	03h	09h	15h	21h	03h	09h	15h	21h	03h	09h	15h	21h	03h	09h	15h	21h	03h	09h	15h	21h
Météo																												
Vent (km/h)	45	35	30	25	15	15	15	15	15	20	20	20	20	20	25	25	20	25	25	20	20	15	15	15	20	20	25	30
à 3000m	↓	↓	↓	↓	↗	↗	↗	↗	↓	↓	→	↑	↘	↑	↗	↑	→	↘	↘	↘	↘	↘	↘	↘	↘	→	↗	↗
Vent (km/h)	25	20	20	15	10	10	5	10	10	10	10	10	10	10	15	15	15	15	15	10	10	10	10	10	15	15	15	20
à 2000m	↓	↓	↓	↓	↗	→	↗	↗	↗	↘	→	↑	↗	↑	↗	↗	→	↘	↘	↘	↘	↘	↘	↘	↘	→	↗	↗

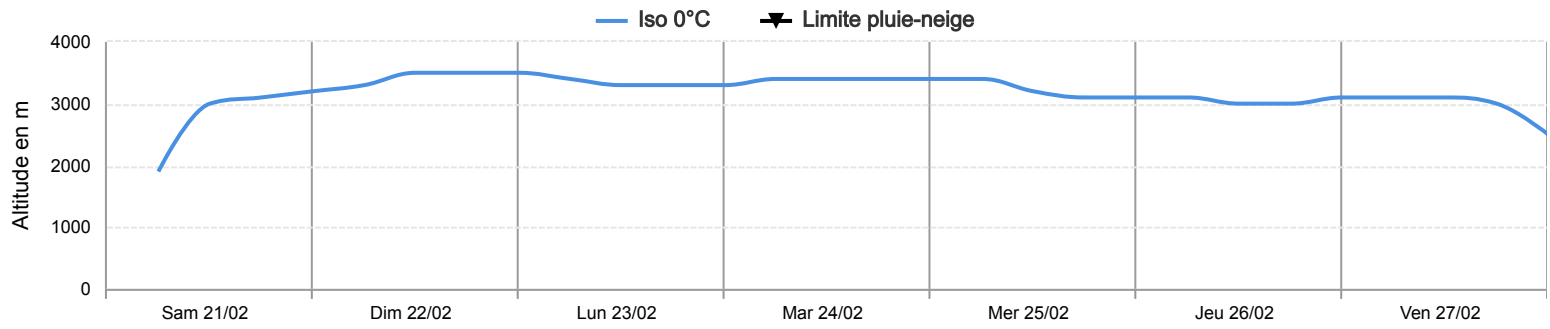

Neige fraîche à 06h

Sam 21/02	Dim 22/02	Lun 23/02	Mar 24/02	Mer 25/02	Jeu 26/02
0 cm	0 cm	0 cm	0 cm	0 cm	0 cm

Risque d'avalanche	sam. 21/02	dim. 22/02	lun. 23/02	mar. 24/02	mer. 25/02	jeu. 26/02	ven. 27/02
	3	3	3	2	2	2	2

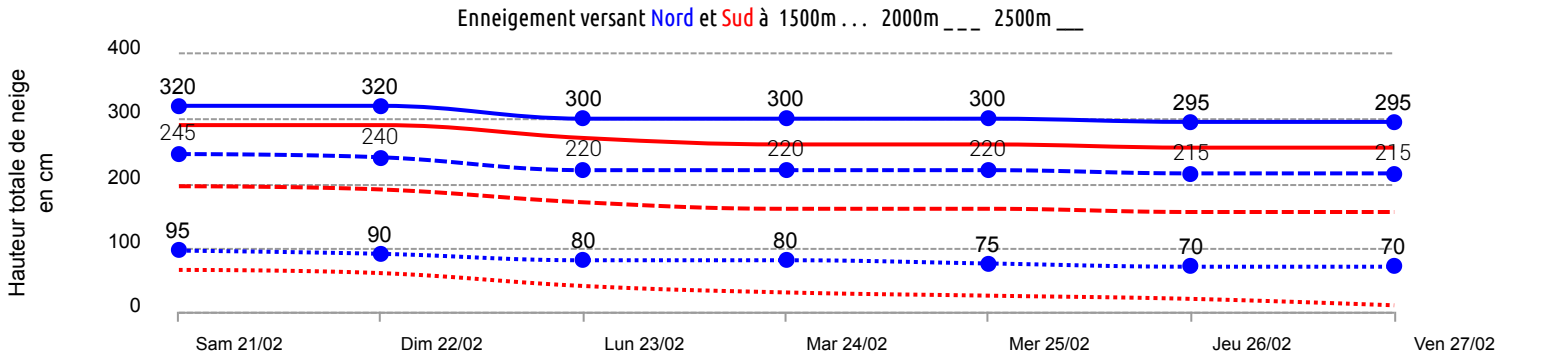

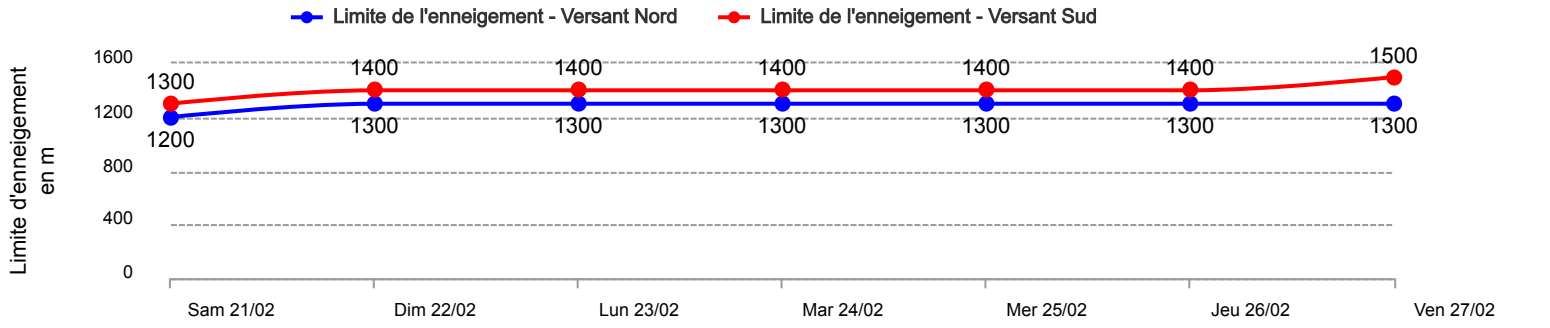

Pour consulter la vigilance en cours, veuillez vous rendre sur le site https://vigilance.meteofrance.fr/fr

Météo-France - 73 avenue de Paris, 94165 Saint-Mandé cedex - Contact : contact@meteo.fr

Rédigé par Météo-France avec la contribution des observateurs du réseau nivo-météorologiques. Partenariat : ANMSM (Maires de Stations de Montagne), DSF (Domaines Skiables de France), ADSP (Directeurs de Pistes et de la Sécurité des Stations de Sports d'Hiver) et autres acteurs de la montagne.

Bulletin neige & avalanches par téléphone au
0 892 68 10 20 Service 0,35 € / min + prix appel