Bulletin d'estimation du risque d'avalanche

(valable en dehors des pistes balisées et ouvertes)

MASSIF : Haute-Tarentaise

Rédigé le vendredi 27 février 2026 à 16h

Estimation des risques pour le : SAMEDI 28 FÉVRIER

ÉPAIS MANTEAU STABILISÉ DANS DE NOMBREUSES PENTES. RISQUE RÉSIDUEL DE PLAQUE DE FOND.

2

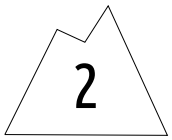

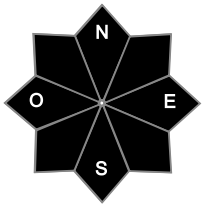

Indice de risque limité.

Départs spontanés : épaisses plaques de fond.

Déclenchements provoqués : rares plaques dans les versants ombragés.

Indices de risque : 5 très fort - 4 fort - 3 marqué - 2 limité - 1 faible -- En noir : les pentes les plus dangereuses

Stabilité du manteau neigeux

Situation avalancheuse typique : avalanches de fond couche fragile persistante

Départs spontanés :
- De **rares mais épaisses plaques de fond** peuvent descendre spontanément, **quelles que soient l'heure et l'orientation**. Plutôt **sous 2200/2400 m** et dans les pentes habituelles (herbe, dalle rocheuse). Le manteau neigeux actuel étant épais, les volumes mobilisés peuvent être plus conséquents que d'habitude. **Lourdes avalanches de taille 2 à 3 (moyenne à grande)**.
- **Sous 2400 m**, la poursuite de l'humidification cause **quelques départs humides** dans les pentes raides non purgées, parfois en larges plaques. Plutôt de taille 1 à 2. Rare taille 3 possible lorsque l'humidification atteint des couches fragiles (plutôt en O/N/E).

Déclenchements provoqués :
- **Au-dessus de 2000/2200 m, en versants O/N/E, rares plaques dures** sur couche fragile persistante. Le déclenchement est **plus facile dans les zones moins enneigées** (abords de crête, etc) car la couche fragile est plus près de la surface. Avalanches de taille 2 à 3 possibles.
- Ailleurs, le déclenchement est peu probable car la couche fragile est généralement profondément enfouie (donc très difficilement sollicitable par un skieur).

Qualité de la neige

Enneigement : après les chutes de neige de mi février, l'enneigement était devenu excédentaire à toutes altitudes. Les températures anormalement douces et le tassement font renter l'enneigement dans la normale, surtout en Sud et en basse montagne où la limite d'enneigement dans ces pentes remonte vite. Ailleurs le manteau se tasse considérablement.

Limite skiable : encore skiable dès 1100 m dans les prairies orientées Nord, plutôt 1400 m en Sud.

Qualité de la neige :
En Sud, croûte portante au réveil qui ramollie plus ou moins bien en fonction de l'épaisseur de la couche nuageuse et de l'altitude.
En Nord, neige croutée sous 1800/2000 m, s'humidifiant doucement. Plus haut, neige encore froide, poudreuse dense à l'abri du vent, cartonnée voire dure dans les secteurs ventés (à l'approche des crêtes). Elle tend à s'humidifier jusque vers 2400 m en cours de journée.

Aperçu météo pour le samedi 28 février

nuit	matin	après-midi	soir

Voile nuageux parfois épais donnant une impression tantôt lumineuse tantôt couverte.

Pluie-Neige				
Iso 0 °C	2 800 m	2 600 m	2 400 m	2 100 m
Vent 2500 m	↙ 10 km/h	↗ 10 km/h	→ 15 km/h	→ 15 km/h
Vent 3500 m	↗ 25 km/h	↗ 25 km/h	↗ 30 km/h	↗ 30 km/h

Épaisseur de neige hors-piste

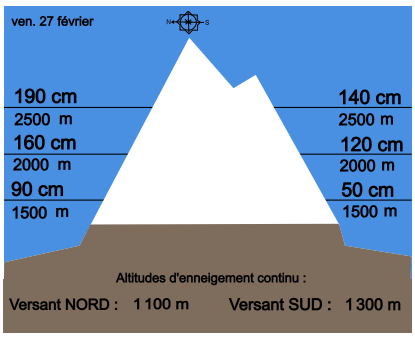

Précipitations à 1800 m

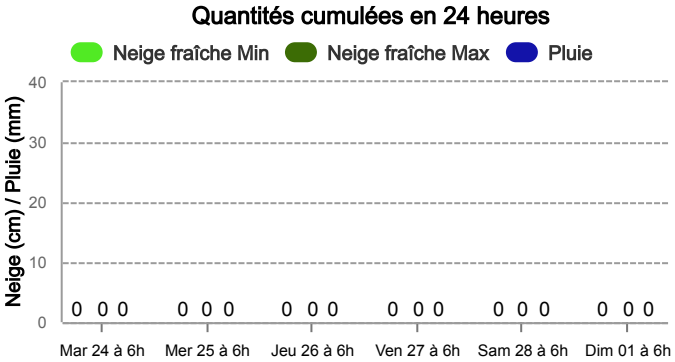

Tendance du dimanche 01 mars

2

Indice de risque limité

Risque stationnaire. Temps couvert avec quelques anecdotiques flocons.
L'humidification est moins marquée que les jours précédents.

Pour consulter la vigilance en cours, veuillez vous rendre sur le site https://vigilance.meteofrance.fr/fr

Météo-France - 73 avenue de Paris, 94165 Saint-Mandé cedex - Contact : contact@meteo.fr

Rédigé par Météo-France avec la contribution des observateurs du réseau nivo-météorologiques. Partenariat : ANMSM (Maires de Stations de Montagne), DSF (Domaines Skiables de France), ADSP (Directeurs de Pistes et de la Sécurité des Stations de Sports d'Hiver) et autres acteurs de la montagne.

Bulletin neige & avalanches par téléphone au
0 892 68 10 20 Service 0,35 € / min + prix appel

RÉPUBLIQUE FRANÇAISE
Liberté Égalité Fraternité

METEO FRANCE
À VOS CÔTÉS, DANS UN CLIMAT QUI CHANGE

Bulletin d'estimation du risque d'avalanche

(valable en dehors des pistes balisées et ouvertes)

MASSIF : Haute-Tarentaise

Rédigé le vendredi 27 février 2026 à 16h

Conditions nivo-météo des 7 derniers jours

	sam. 21/02				dim. 22/02				lun. 23/02				mar. 24/02				mer. 25/02				jeu. 26/02				ven. 27/02			
	03h	09h	15h	21h	03h	09h	15h	21h	03h	09h	15h	21h	03h	09h	15h	21h	03h	09h	15h	21h	03h	09h	15h	21h	03h	09h	15h	21h
Météo																												
Vent (km/h)	50	50	60	60	40	40	50	50	55	45	50	50	50	40	30	25	20	20	20	15	15	15	15	15	20	15	25	25
à 3500m																												
Vent (km/h)	30	35	40	40	20	20	30	30	25	25	25	20	20	15	15	10	5	5	5	5	5	5	5	5	5	5	10	10
à 2500m																												

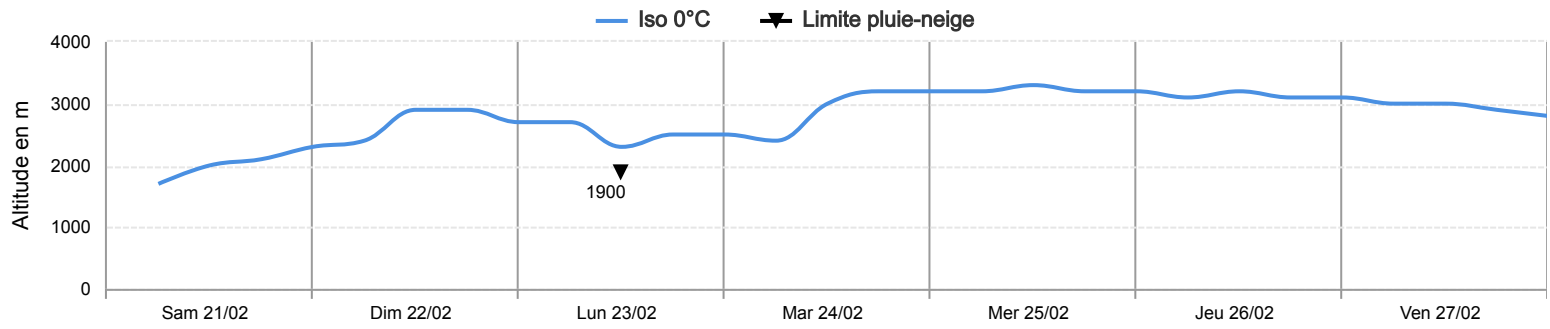

Neige fraîche à 06h

Sam 21/02	Dim 22/02	Lun 23/02	Mar 24/02	Mer 25/02	Jeu 26/02
0 cm	0 cm	0 cm	0 cm	0 cm	0 cm

Risque d'avalanche	sam. 21/02	dim. 22/02	lun. 23/02	mar. 24/02	mer. 25/02	jeu. 26/02	ven. 27/02
	4	3	3	3	3	3	3

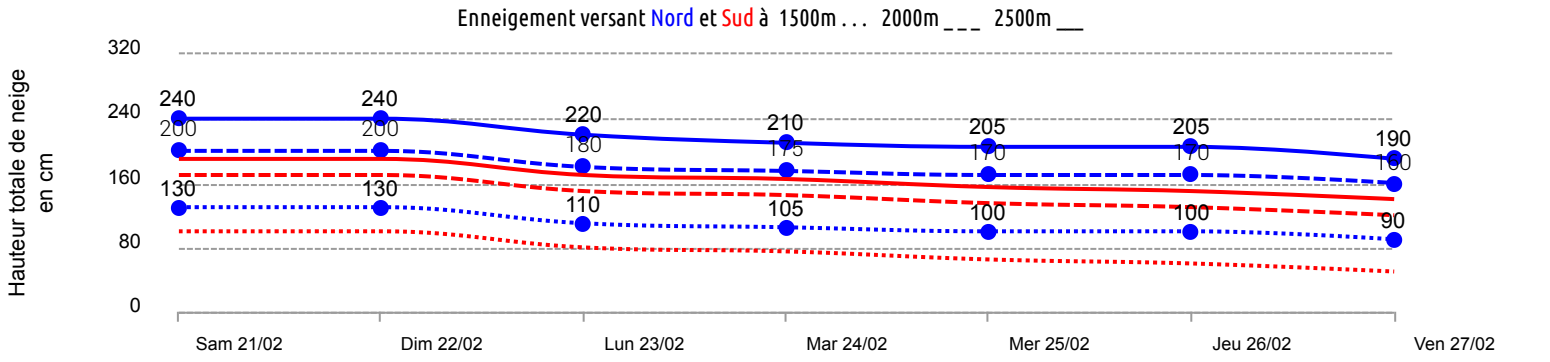

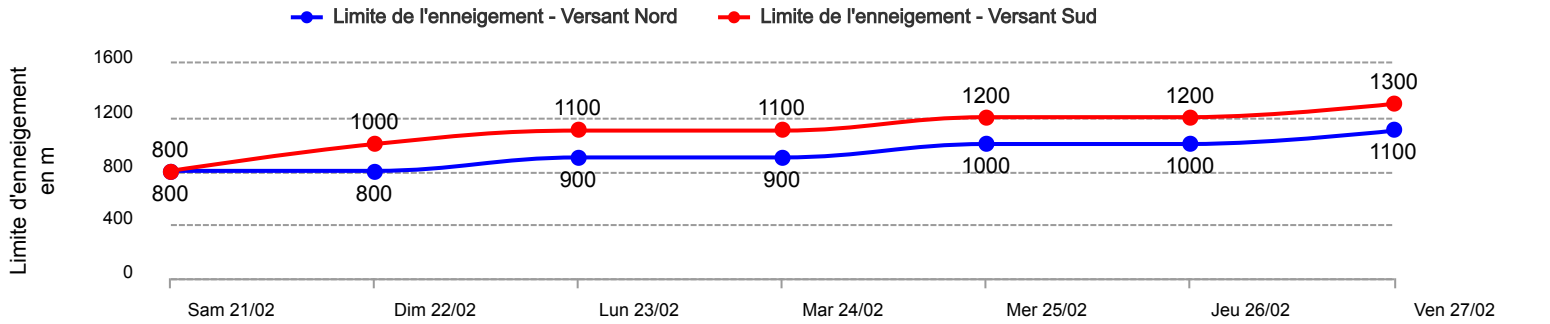

Pour consulter la vigilance en cours, veuillez vous rendre sur le site https://vigilance.meteofrance.fr/fr

Météo-France - 73 avenue de Paris, 94165 Saint-Mandé cedex - Contact : contact@meteo.fr

Bulletin neige & avalanches par téléphone au

0 892 68 10 20 Service 0,35 € / min + prix appel

Rédigé par Météo-France avec la contribution des observateurs du réseau nivo-météorologiques. Partenariat : ANMSM (Maires de Stations de Montagne), DSF (Domaines Skiables de France), ADSP (Directeurs de Pistes et de la Sécurité des Stations de Sports d'Hiver) et autres acteurs de la montagne.