Bulletin d'estimation du risque d'avalanche
(valable en dehors des pistes balisées et ouvertes)

MASSIF : Pays-Basque

Rédigé le vendredi 27 février 2026 à 16h

Estimation des risques pour le : SAMEDI 28 FÉVRIER

MANTEAU NEIGEUX BIEN STABILISÉ

1

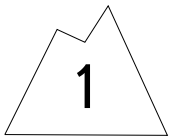

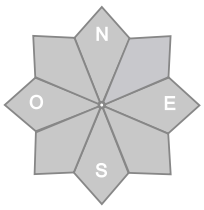

Indice de risque faible.

Départs spontanés : Rares coulées

Déclenchements provoqués : Peu probable

Indices de risque : 5 très fort - 4 fort - 3 marqué - 2 limité - 1 faible -- En noir : les pentes les plus dangereuses

Stabilité du manteau neigeux

Situation avalancheuse typique : pas de situation prédominante

Départs spontanés : Peu d'activité naturelle avec net rafraichissement

Déclenchements provoqués : Peu probable, bonne cohésion de regel sur ce massif.

Qualité de la neige

Enneigement : faible enneigement sous 1400/1500m, l'enneigement est bon au-dessus de 1800m mais irrégulièrement réparti, crêtes dégarnies, combes chargées, et corniches parfois imposantes.
Limites skiables : à partir de 1400 à 1600 m.
État de la neige : Un peu de neige fraiche sur une sous-couche souvent portante, occasionnellement regelée, et localement un peu de neige meuble sur les versants Nord.

Aperçu météo pour le samedi 28 février

	nuit	matin	après-midi	soir
Pluie-Neige	1 700 m	1 400 m	1 400 m	
Iso 0 °C	2 100 m	1 700 m	1 600 m	1 600 m
Vent 1000 m	15 km/h	15 km/h	20 km/h	10 km/h
Vent 2000 m	15 km/h	15 km/h	20 km/h	15 km/h

Épaisseur de neige hors-piste

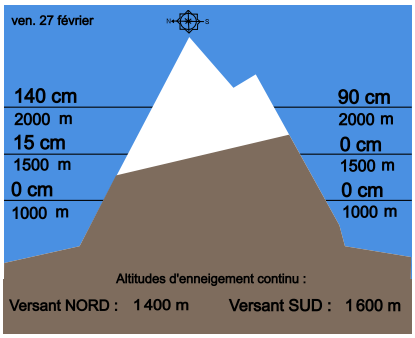

Précipitations à 1800 m

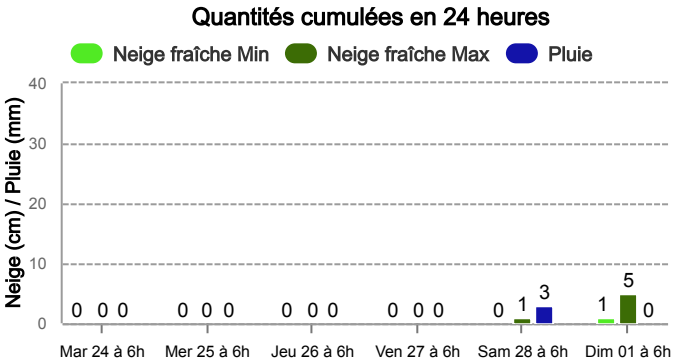

Tendance du dimanche 01 mars

1

Indice de risque faible

Pas d'évolution.

Pour consulter la vigilance en cours, veuillez vous rendre sur le site https://vigilance.meteofrance.fr/fr

Météo-France - 73 avenue de Paris, 94165 Saint-Mandé cedex - Contact : contact@meteo.fr

Rédigé par Météo-France avec la contribution des observateurs du réseau nivo-météorologiques. Partenariat : ANMSM (Maires de Stations de Montagne), DSF (Domaines Skiables de France), ADSP (Directeurs de Pistes et de la Sécurité des Stations de Sports d'Hiver) et autres acteurs de la montagne.

Bulletin neige & avalanches par téléphone au 0 892 68 10 20 Service 0,35 € / min + prix appel

Bulletin d'estimation du risque d'avalanche

(valable en dehors des pistes balisées et ouvertes)

MASSIF : Pays-Basque

Rédigé le vendredi 27 Février 2026 à 16h

Conditions nivo-météo des 7 derniers jours

	sam. 21/02				dim. 22/02				lun. 23/02				mar. 24/02				mer. 25/02				jeu. 26/02				ven. 27/02			
	03h	09h	15h	21h	03h	09h	15h	21h	03h	09h	15h	21h	03h	09h	15h	21h	03h	09h	15h	21h	03h	09h	15h	21h	03h	09h	15h	21h
Météo																												
Vent (km/h)	20	10	15	20	25	25	25	25	15	15	20	45	60	55	40	35	35	35	35	35	35	35	45	50	50	55	45	30
à 2000m																												
Vent (km/h)	5	2	10	10	15	15	10	5	5	5	10	15	20	15	15	15	15	15	15	15	20	20	25	30	40	40	25	15
à 1000m																												

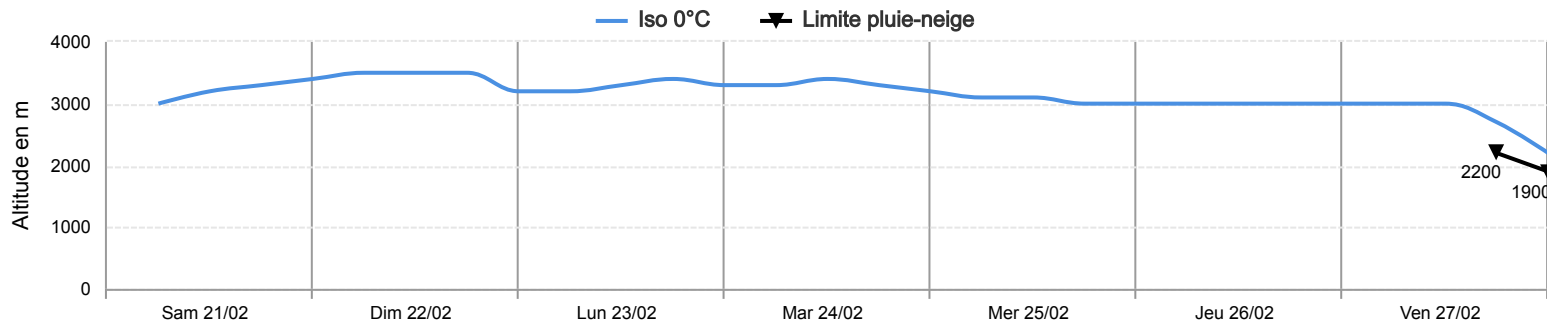

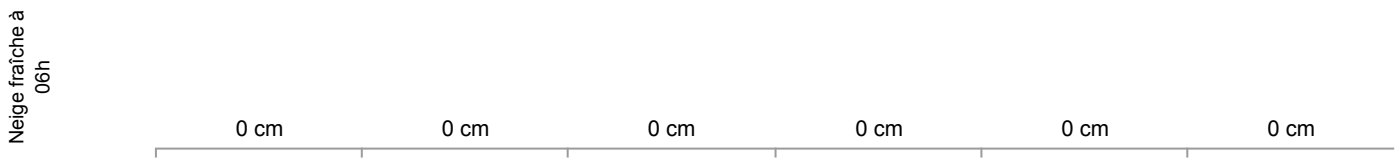

Risque d'avalanche	sam. 21/02	dim. 22/02	lun. 23/02	mar. 24/02	mer. 25/02	jeu. 26/02	ven. 27/02
	3	2	2	2	1	1	1

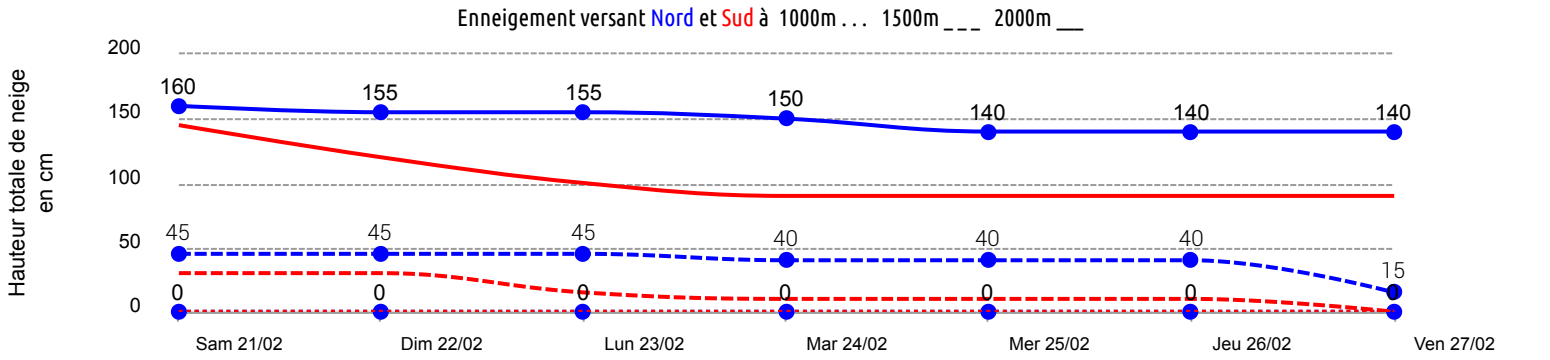

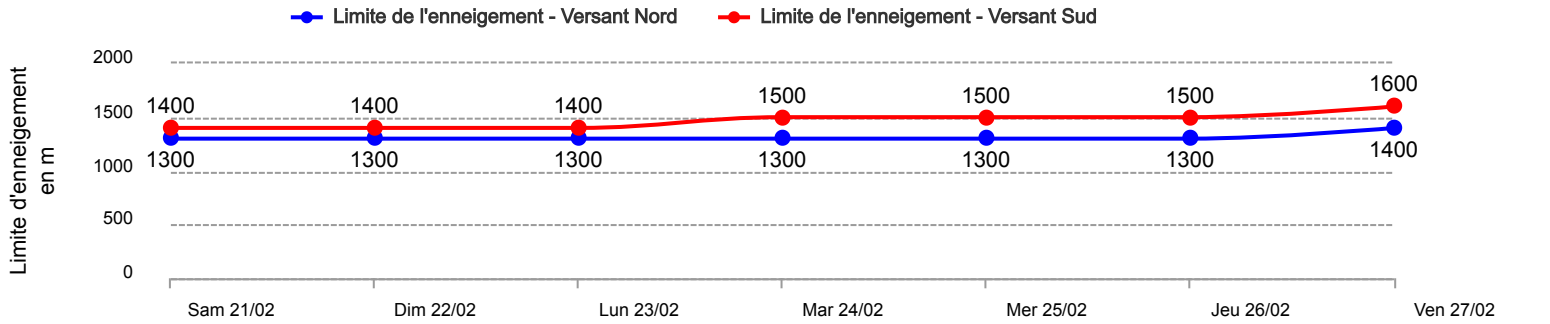

Pour consulter la vigilance en cours, veuillez vous rendre sur le site https://vigilance.meteofrance.fr/fr

Météo-France - 73 avenue de Paris, 94165 Saint-Mandé cedex - Contact : contact@meteo.fr

Rédigé par Météo-France avec la contribution des observateurs du réseau nivo-météorologiques. Partenariat : ANMSM (Maires de Stations de Montagne), DSF (Domaines Skiables de France), ADSP (Directeurs de Pistes et de la Sécurité des Stations de Sports d'Hiver) et autres acteurs de la montagne.

Bulletin neige & avalanches par téléphone au 0 892 68 10 20 Service 0,35 € / min + prix appel