Bulletin d'estimation du risque d'avalanche
(valable en dehors des pistes balisées et ouvertes)

MASSIF : Ubaye

Rédigé le vendredi 27 février 2026 à 16h

Estimation des risques pour le : SAMEDI 28 FÉVRIER

PLAQUES ÉPAISSES DIFFICILES À DÉCLENCHER EN UBACS D'ALTITUDE, QUELQUES DÉPARTS EN NEIGE HUMIDE, RAREMENT VOLUMINEUX.

2

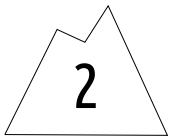

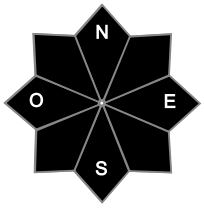

Indice de risque limité.

Départs spontanés : quelques avalanches de fond, départs superficiels en neige humide.

Déclenchements provoqués : plaques épaisses en ubacs d'altitude, difficiles à déclencher + départs en neige humide

Indices de risque : 5 très fort - 4 fort - 3 marqué - 2 limité - 1 faible -- En noir : les pentes les plus dangereuses

Stabilité du manteau neigeux

Situation avalancheuse typique : couche fragile persistante avalanches de fond

Déclenchements provoqués :
- **plaques dures épaisses sur couche fragile persistante enfouie** encore présentes dans les orientations ouest / nord / est au-dessus de 2000/2200 m. Déclenchement difficile au passage d'un skieur, mais restant possible là où le manteau neigeux est moins épais (croupes, bords de couloir), **notamment en Haute-Ubaye**. Avalanche de grande taille, cassure épaisse et large. Danger difficile à détecter.
- **en neige humide**. Un skieur peut favoriser un départ superficiel en neige fortement humidifiée en pente raide ensoleillée, généralement de petite taille.

Départs spontanés :
- **quelques avalanches de fond** suite à la rupture de reptations (gueules de baleine). Taille moyenne, voire grande. Possibles à n'importe quel moment du jour et de la nuit. En versant sud, plutôt au-dessous de 2500/2700 m. En versant nord, plutôt au-dessous de 2000 m.
- **avalanches de neige humide**, peu probables au levé du jour, puis quelques départs superficiels au soleil au fil de la journée, affectant surtout les orientations est / sud / ouest. Départs ponctuels de petite taille, rarement moyenne.

Qualité de la neige

Enneigement légèrement excédentaire pour une fin février.
Données observées : 94 cm au-dessus de Larche à 2270 m en adret.

Enneigement skiable dès 1400/1500 m en terrains favorables, 1600/1800 m en adrets, voir plus haut en Haute-Ubaye.

État de la neige en surface : croute souvent portante le matin après un bon regel nocturne, s'humidifiant progressivement en journée au fil de l'ensoleillement. En ubacs au-dessus de 2000/2200 m environ, neige froide, souvent travaillée/durcie par le vent de nord. Zones dégarnies proches des crêtes, alternant avec des corniches parfois épaisses.

Aperçu météo pour le samedi 28 février

nuit	matin	après-midi	soir

Temps sec avec un ciel passagèrement voilé. Températures en baisse.

Pluie-Neige				
Iso 0 °C	2 800 m	2 700 m	2 500 m	2 300 m
Vent 2000 m	↖ 5 km/h	↑ 10 km/h	↗ 15 km/h	→ 5 km/h
Vent 3000 m	↗ 10 km/h	↗ 20 km/h	→ 20 km/h	→ 15 km/h

Épaisseur de neige hors-piste

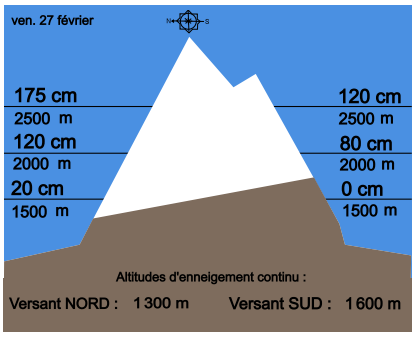

Précipitations à 1800 m

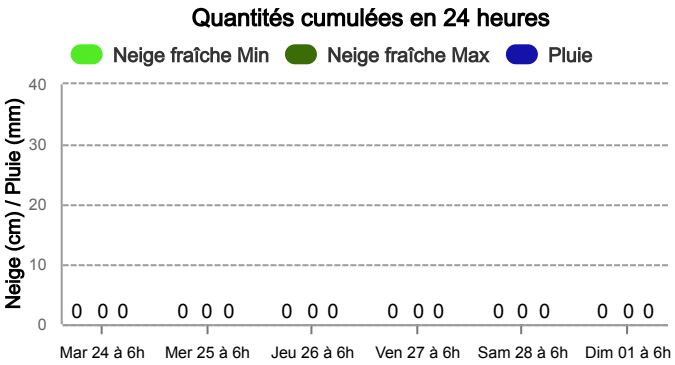

Tendance du dimanche 01 mars

2

Indice de risque limité

Encore un peu d'activité en neige humide malgré la baisse des températures, possible en versant nord avec la couverture nuageuse. Toujours de rares plaques épaisses en ubacs d'altitude.

Pour consulter la vigilance en cours, veuillez vous rendre sur le site https://vigilance.meteofrance.fr/fr

Météo-France - 73 avenue de Paris, 94165 Saint-Mandé cedex - Contact : contact@meteo.fr

Rédigé par Météo-France avec la contribution des observateurs du réseau nivo-météorologiques. Partenariat : ANMSM (Maires de Stations de Montagne), DSF (Domaines Skiables de France), ADSP (Directeurs de Pistes et de la Sécurité des Stations de Sports d'Hiver) et autres acteurs de la montagne.

Bulletin neige & avalanches par téléphone au
0 892 68 10 20 Service 0,35 € / min + prix appel

Bulletin d'estimation du risque d'avalanche

(valable en dehors des pistes balisées et ouvertes)

MASSIF : Ubaye

Rédigé le vendredi 27 Février 2026 à 16h

Conditions nivo-météo des 7 derniers jours

	sam. 21/02				dim. 22/02				lun. 23/02				mar. 24/02				mer. 25/02				jeu. 26/02				ven. 27/02			
	03h	09h	15h	21h	03h	09h	15h	21h	03h	09h	15h	21h	03h	09h	15h	21h	03h	09h	15h	21h	03h	09h	15h	21h	03h	09h	15h	21h
Météo																												
Vent (km/h)	55	60	50	35	35	35	40	45	40	35	35	30	35	25	15	10	10	10	10	10	10	10	10	10	10	10	10	10
à 3000m																												
Vent (km/h)	20	25	25	20	15	15	20	15	20	20	15	15	15	10	5	10	10	5	10	10	5	5	5	5	5	5	10	5
à 2000m																												

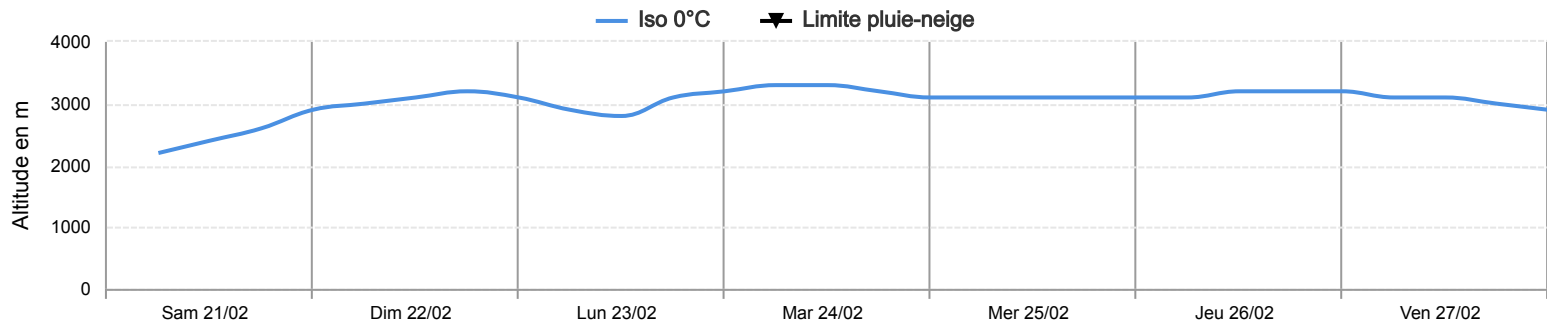

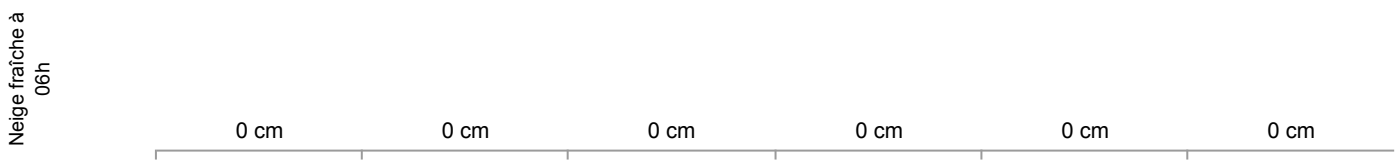

Risque d'avalanche	sam. 21/02	dim. 22/02	lun. 23/02	mar. 24/02	mer. 25/02	jeu. 26/02	ven. 27/02
	3	3	3	3	3	3	2

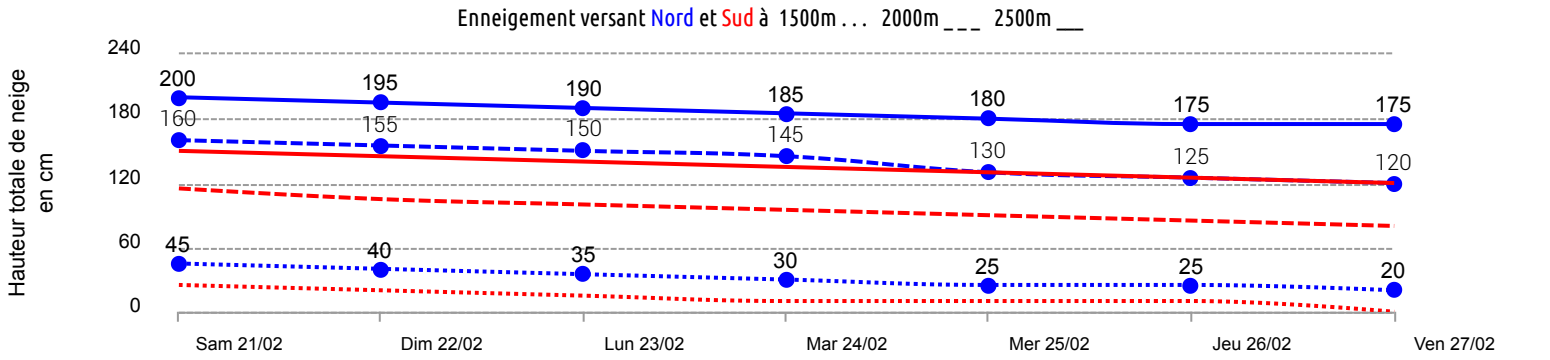

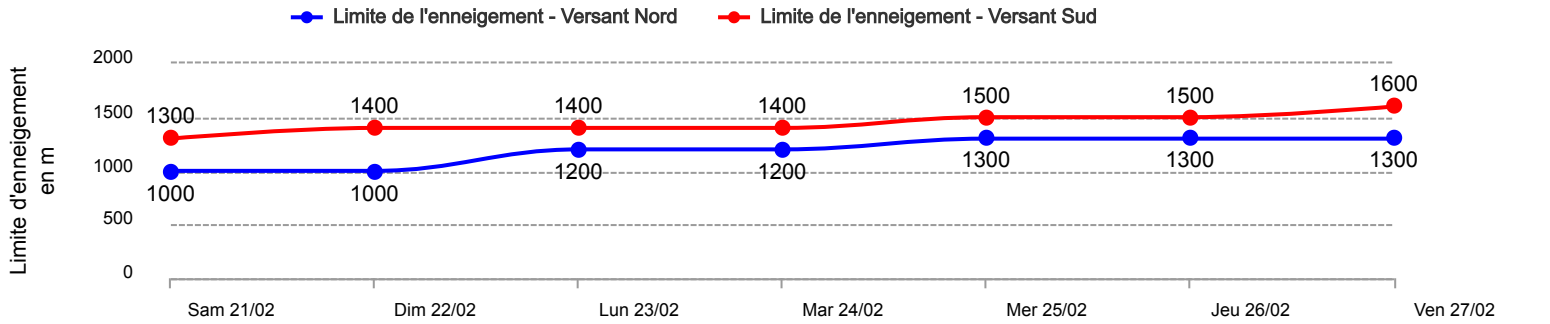

Pour consulter la vigilance en cours, veuillez vous rendre sur le site https://vigilance.meteofrance.fr/fr

Météo-France - 73 avenue de Paris, 94165 Saint-Mandé cedex - Contact : contact@meteo.fr

Bulletin neige & avalanches par téléphone au

0 892 68 10 20 Service 0,35 € / min + prix appel

Rédigé par Météo-France avec la contribution des observateurs du réseau nivo-météorologiques. Partenariat : ANMSM (Maires de Stations de Montagne), DSF (Domaines Skiables de France), ADSP (Directeurs de Pistes et de la Sécurité des Stations de Sports d'Hiver) et autres acteurs de la montagne.