Boletín de información nivológica y de peligro de aludes

Pirineo Navarro y Aragonés

sábado, 28 de febrero de 2026 (corrección)

Pronóstico hasta las 24 horas del domingo, día 1 de marzo

(Válido fuera de pistas de esquí balizadas y abiertas)

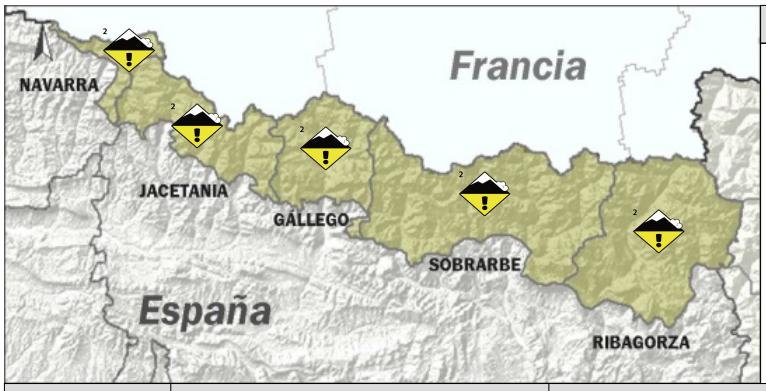

Problemas de aludes

Placas de viento

Nieve húmeda

Macizo	Peligro	Problemas de aludes, cota, orientación, tamaño	Innivación observada (m)
Navarra	2 2 / 1→2 / 2000 Durante el día Limitado	**Placas de viento** 2000 N E S O 2 **Nieve húmeda** 2200 N E S O 2	2026-02-28 N S Cota más baja caras N
Jacetania	2 2 / 1→2 / 2000 Durante el día Limitado	**Placas de viento** 2000 N E S O 2 **Nieve húmeda** 2200 N E S O 2	2026-02-28 N S Cota más baja caras N
Gállego	2 2 / 1→2 / 2000 Durante el día Limitado	**Placas de viento** 2000 N E S O 2 **Nieve húmeda** 2200 N E S O 2	2026-02-28 N S Cota más baja caras N

AEMET. Se autoriza la reproducción de su contenido citando la fuente.

Boletín de información nivológica y de peligro de aludes

Pirineo Navarro y Aragonés

Sobrarbe	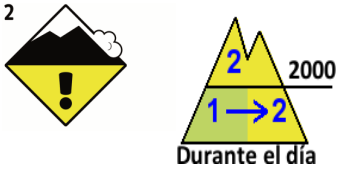 **Limitado**	**Placas de viento** 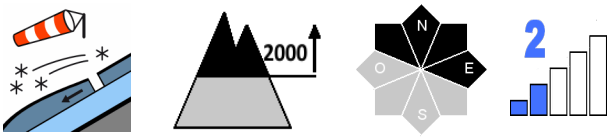 **Nieve húmeda** 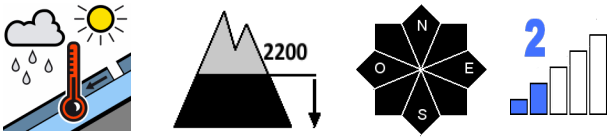	2026-02-28 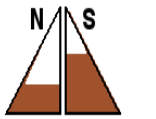 Cota más baja caras N
Ribagorza	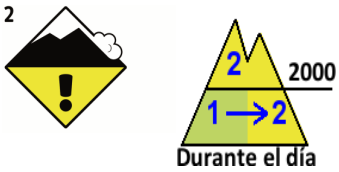 **Limitado**	**Placas de viento** 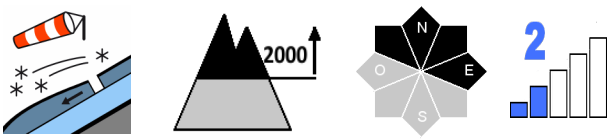 **Nieve húmeda** 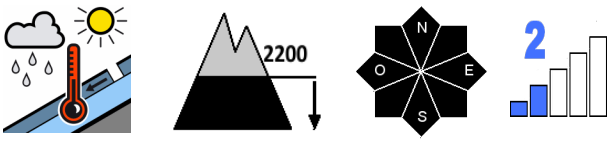	2026-02-28 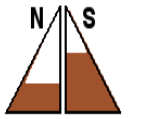 Cota más baja caras N

Estado del manto y observaciones recientes

Hoy se han vuelto a registrar nuevas pérdidas de espesor significativas, tal como lleva sucediendo en las jornadas anteriores, debido a la intensa insolación y el ambiente templado con temperaturas anormalmente altas. Aún con todo los espesores se encuentran por encima de lo que sería habitual a estas alturas de la temporada.

El manto comienza de manera continua a unos 1300 metros en umbrías y a unos 1500 metros en solanas. Aunque a estas altitudes se puedan alcanzar los 70-80 cm de espesor, ya se observa una asimetría norte-sur, con pérdidas notables en las solanas, donde incluso se pueden encontrar zonas desprovistas de nieve. Conforme ascendemos en altitud estos van incrementando, de manera que en cotas medias los espesores son muy abundantes, superando los 200 cm a unos 1900 metros y los 300 cm a unos 2300, pudiendo alcanzar los 4 metros en ventisqueros, hoyas y otras zonas propensas a la acumulación de cotas altas.

En cotas medias y bajas, así como en solanas a mayor altitud, el manto se ha humidificado en profundidad y, por lo general, amanece encostrado. El calentamiento diurno y la intensa radiación van ablandando las costras durante la mañana en las solanas, sometiéndose a un ciclo de rehielo-fusión diario, siendo menos efectivo en umbrías de cotas medias, donde las costras permanecen intactas durante toda la jornada.

En umbrías de cotas altas, la nieve se mantiene más seca y aún podemos encontrar placas de viento dispersas que no se han estabilizado por completo, que generalmente serán de tamaño pequeño y poco reactivas. Cabe destacar que se han realizado varios sondeos en estos enclaves, reaccionando a los test de estabilidad ante esfuerzos generalmente grandes, en algún caso medianos, y propagando la fractura en algunas ocasiones, en algún caso a profundidades considerables. Esto da cuenta de la posibilidad de desencadenamiento de aludes de tamaño mediano o incluso grande ante sobrecargas suficientemente grandes.

AEMET. Se autoriza la reproducción de su contenido citando la fuente.

Evolución del manto y peligro de aludes para el domingo, día 1

Problema de nieve húmeda y deslizamientos basales. Problema de placas de viento y capas débiles persistentes en cotas altas.

A lo largo del día de hoy se esperan algunas nevadas que podrán añadir unos pocos centímetros de nieve nueva, sin descartar que se puedan alcanzar localmente los 5-10 cm en cotas altas. Estas tenderán a remitir en el transcurso de la tarde hoy, siendo posibles algunas purgas y coladas de nieve reciente que cesarán de cara al día de mañana.

Además, durante los días de hoy y mañana se espera que soplen vientos moderados de componentes oeste y sur en cotas altas, que podrán formar algunas placas de viento nuevas a sotavento (en caras este y norte). Estas estructuras de nueva formación podrán colapsar ante sobrecargas débiles (paso de un sólo esquiador), generando aludes de tamaño 1 (pequeño) o localmente 2 (mediano), añadiéndose a otras de formación más antigua en todas las orientaciones que siguen sin estabilizarse por completo, sobre todo en umbrías, las cuales podrían reaccionar ante sobrecargas grandes (paso de dos o más esquiadores), localmente menores. En caso de que estas últimas colapsen, serían posibles los aludes de tamaño 2 (mediano), o incluso 3 (grande) en caso de afectar a niveles inferiores y fracturar alguna capa débil en profundidad.

En cotas medias y bajas, serán probables los aludes de nieve húmeda de tamaño 1 (pequeño) ó 2 (mediano), así como los deslizamientos basales en zonas herbosas o de roca lisa, que podrían movilizar una cantidad de nieve considerable y alcanzar localmente el tamaño 3 (grande). Cabe mencionar que se espera que mañana se formen numerosas costras de rehielo que aportarán estabilidad al manto durante la madrugada, pero que tenderán a desaparecer en el transcurso de la mañana debido al calentamiento diurno y a la insolación. Así, con el avance del día, el manto se hará cada vez más inestable, especialmente en solanas.

Predicción meteorológica para el domingo, día 1

Pirineo navarro:
Intervalos de nubes bajas al inicio, localmente asociadas a brumas y nieblas, tendiendo a poco nuboso o despejado. No se esperan precipitaciones. Temperaturas mínimas con algunos ligeros descensos. Máximas en moderado ascenso, que localmente podría ser notable. Heladas débiles, localmente moderadas en cotas altas. Viento de componente sur, flojo aumentando a moderado con intervalos fuertes.

Pirineo aragonés:
Poco nuboso o con intervalos de nubes bajas, localmente asociadas a brumas y nieblas, tendiendo a despejar a partir del mediodía. No se esperan precipitaciones. Temperaturas mínimas en moderado descenso. Máximas con pocos cambios, salvo en la Jacetania donde ascenderán ligera o moderadamente. Heladas débiles o moderadas, localmente notables en cotas altas. Viento con predominio de la componente sur, flojo con intervalos de moderado. Más intenso en la Jacetania donde irá acompañado de rachas fuertes, sin descartar alguna en el resto de la divisoria con Francia.

AEMET. Se autoriza la reproducción de su contenido citando la fuente.

Datos en la atmósfera libre:

Altitud de la isoterma de 0 ºC: 2000 m
Altitud de la isoterma de -10 ºC: 3800 m

Viento a 1500 m: S 20 km/h
Viento a 3000 m: W 10 km/h

Evolución para el lunes día 2

Nivel de peligro con pocos cambios.

(Información elaborada a partir de los datos recibidos de los refugios de Linza, Lizara, Panticosa, Bachimaña, Góriz, Pineta, Estós, Angel Orús, La Renclusa, Cap de Llauset y Belagua, de las estaciones de esquí de Astún, Formigal y Panticosa (lagos) y de Ordesa Pradera)

Escala europea de peligro de aludes

Débil | Limitado | Notable | Fuerte | Muy Fuerte

Problemas de aludes

Nieve reciente | Placas de viento | Capas débiles persistentes | Nieve húmeda | Deslizamientos basales | Sin problema evidente

Nota1: Se recuerda que, siempre que haya nieve, la ausencia total de peligro no existe. Hay que tener presente que en circunstancias desfavorables, con aludes de tamaño 1 (alud pequeño o colada) y tamaño 2 (alud mediano), se pueden sufrir severos daños personales.

Nota2: Los BPA se elaboran en base a información meteorológica así como al estado del manto nivoso a través de sondeos puntuales. Se advierte a los usuarios de la variabilidad de esta información al extrapolarla a zonas extensas de montaña. Por ello, AEMET no se hace responsable de su uso para la toma de decisiones que conciernen a la seguridad personal, ni de los riesgos físicos o materiales de ellas derivadas.

AEMET. Se autoriza la reproducción de su contenido citando la fuente.